Bulletin d'estimation du risque d'avalanche
(valable en dehors des pistes balisées et ouvertes)

MASSIF : Haut-Var Haut-Verdon

Rédigé le mercredi 25 mars 2026 à 16h

Estimation des risques pour le : JEUDI 26 MARS

NOMBREUSES PLAQUES EN FORMATION DANS LA NEIGE VENTÉE

3

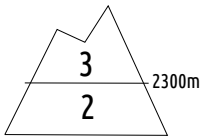

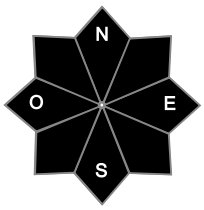

Au-dessus de 2300m indice de risque marqué, plus bas indice limité.

Départs spontanés : quelques ruptures spontanées suite au transport de neige par le vent

Déclenchements provoqués : plaques faciles à déclencher dans la neige transportée par le vent

Indices de risque : 5 très fort - 4 fort - 3 marqué - 2 limité - 1 faible -- En noir : les pentes les plus dangereuses

Stabilité du manteau neigeux

Situation avalancheuse typique : neige ventée

Déclenchements provoqués : plaques en place et nombreuses en formation au dessus de 2300 m environ, même loin des crêtes, entretenues par un fort vent de nord à nord-ouest. Ces plaques sont facilement déclenchables, surtout dans les versants froids où le manteau neigeux n'est pas encore printanier. Elles génèrent des avalanches souvent de taille moyenne (taille 2), une rare grande (taille 3) non exclue dans les zones de forte accumulation de neige ou couloirs chargés.
Sous 2300 m, la probabilité de déclencher une plaque est plus limitée.

Départs spontanés : quelques plaques cèdent spontanément en pentes raides sous le fort vent de nord à nord-ouest. Avalanches de taille 1 à 2.

Qualité de la neige

Enneigement plutôt excédentaire dans le Haut-Verdon, proche des normales dans le Haut Var.
Hauteurs de neige observées : vers 2000 m, 185 cm dans le vallon de Valdemars, 124 cm dans le Haut Var.

Enneigement skiable : vers 1400/1500 m en ubacs, 1700/1800 m en adrets peu pentus.

État de la neige en surface : en sud, neige souvent croûtée, parfois recouverte par des accumulations de neige rapportée par le fort vent de nord. Dans les versants froids, la neige reste froide au dessus de 2000/2200 m environ, encore assez légère dans les combes abritées du vent, mais de plus en plus travaillée et durcie par le vent dans les secteurs exposés.

Aperçu météo pour le jeudi 26 mars

nuit	matin	après-midi	soir

Temps hivernal et venté avec des passages nuageux. -2° à 2000 m et -14° à 3000 m

Pluie-Neige				
Iso 0 °C	1 200 m	1 000 m	1 700 m	1 200 m
Vent 2000 m	85 km/h	65 km/h	60 km/h	50 km/h
Vent 3000 m	100 km/h	80 km/h	70 km/h	60 km/h

Épaisseur de neige hors-piste

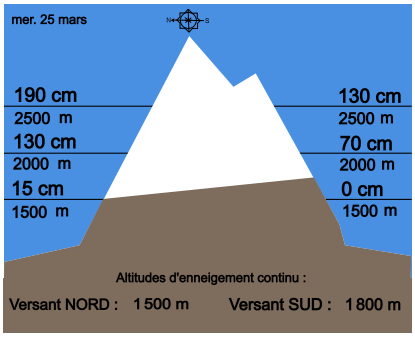

Précipitations à 1800 m

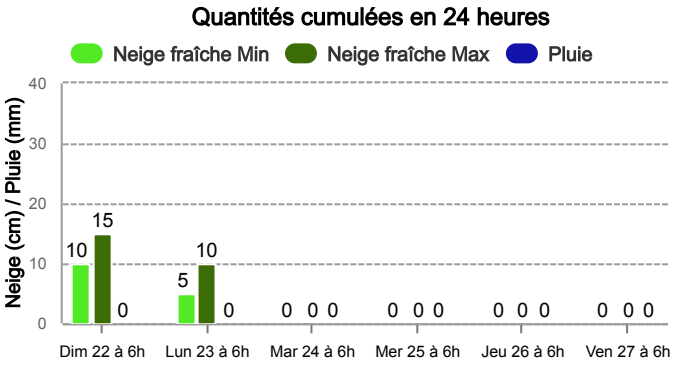

Tendance du vendredi 27 mars

2

Indice de risque limité

Risque en baisse redevenant limité avec la stabilisation rapide des plaques dans la neige ventée au soleil. Ces instabilités persistent un peu plus longtemps en versants ombragés.

Pour consulter la vigilance en cours, veuillez vous rendre sur le site https://vigilance.meteofrance.fr/fr

Météo-France - 73 avenue de Paris, 94165 Saint-Mandé cedex - Contact : contact@meteo.fr

Rédigé par Météo-France avec la contribution des observateurs du réseau nivo-météorologiques. Partenariat : ANMSM (Maires de Stations de Montagne), DSF (Domaines Skiables de France), ADSP (Directeurs de Pistes et de la Sécurité des Stations de Sports d'Hiver) et autres acteurs de la montagne.

Bulletin neige & avalanches par téléphone au
0 892 68 10 20 Service 0,35 € / min + prix appel

RÉPUBLIQUE FRANÇAISE
Liberté Égalité Fraternité

METEO FRANCE
À VOS CÔTÉS, DANS UN CLIMAT QUI CHANGE

Bulletin d'estimation du risque d'avalanche

(valable en dehors des pistes balisées et ouvertes)

MASSIF : Haut-Var Haut-Verdon

Rédigé le mercredi 25 mars 2026 à 16h

Conditions nivo-météo des 7 derniers jours

	jeu. 19/03				ven. 20/03				sam. 21/03				dim. 22/03				lun. 23/03				mar. 24/03				mer. 25/03			
	03h	09h	15h	21h	03h	09h	15h	21h	03h	09h	15h	21h	03h	09h	15h	21h	03h	09h	15h	21h	03h	09h	15h	21h	03h	09h	15h	21h
Météo																												
Vent (km/h)	65	50	30	30	25	15	15	15	10	15	20	15	20	20	35	45	40	25	20	25	20	10	15	15	25	40	70	100
à 3000m																												
Vent (km/h)	45	30	20	15	10	10	15	5	5	10	20	10	10	10	25	30	25	15	15	15	10	10	10	10	10	25	55	80
à 2000m																												

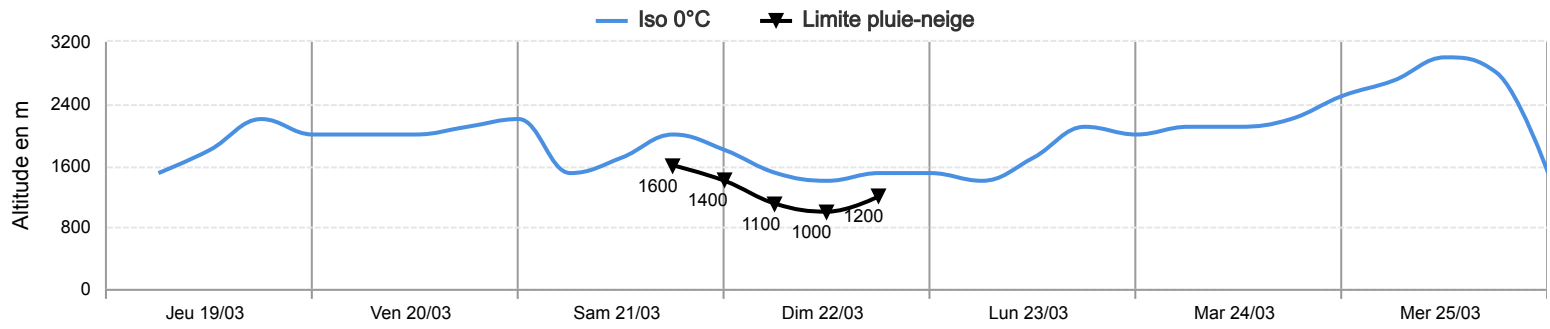

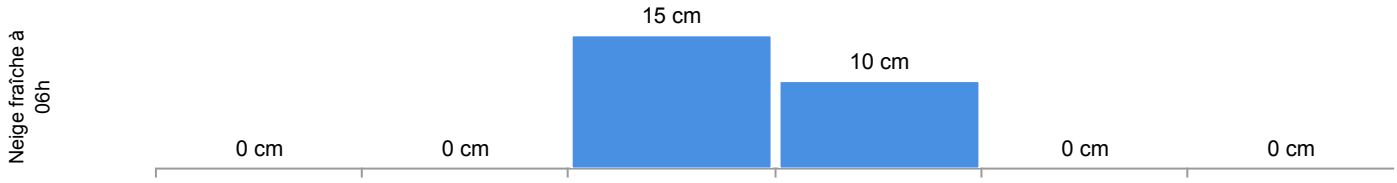

Risque d'avalanche	jeu. 19/03	ven. 20/03	sam. 21/03	dim. 22/03	lun. 23/03	mar. 24/03	mer. 25/03
	3	2	2	3	3	2	2

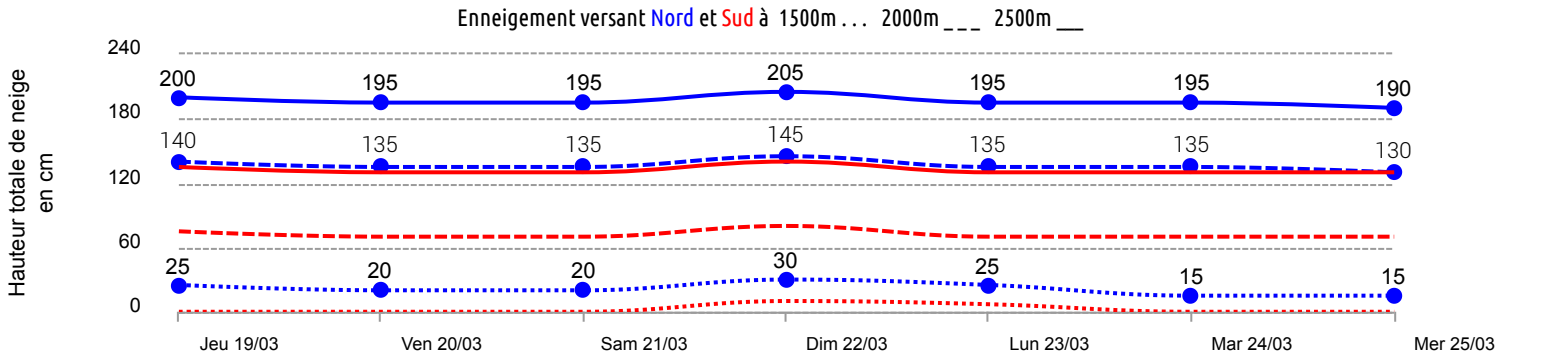

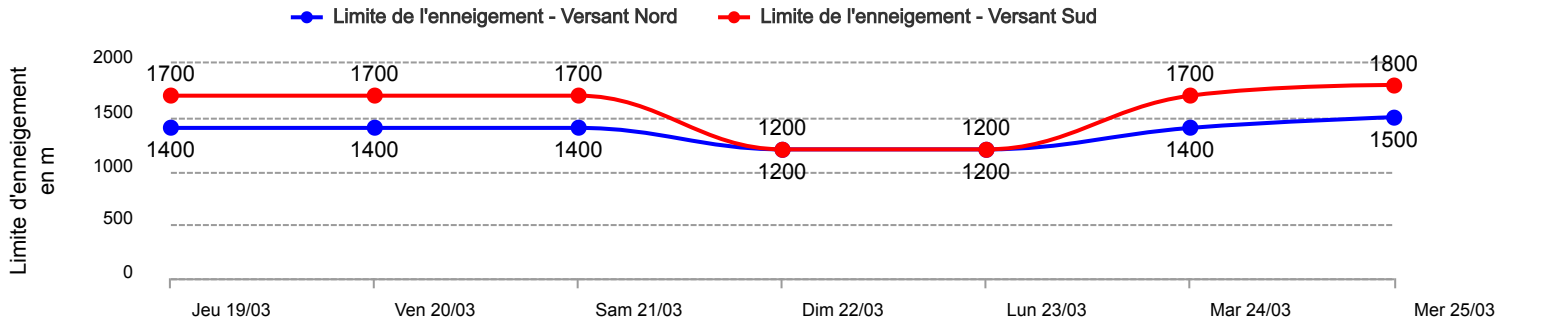

Pour consulter la vigilance en cours, veuillez vous rendre sur le site https://vigilance.meteofrance.fr/fr

Météo-France - 73 avenue de Paris, 94165 Saint-Mandé cedex - Contact : contact@meteo.fr

Bulletin neige & avalanches par téléphone au

0 892 68 10 20 Service 0,35 € / min + prix appel

Rédigé par Météo-France avec la contribution des observateurs du réseau nivo-météorologiques. Partenariat : ANMSM (Maires de Stations de Montagne), DSF (Domaines Skiables de France), ADSP (Directeurs de Pistes et de la Sécurité des Stations de Sports d'Hiver) et autres acteurs de la montagne.