Bulletin d'estimation du risque d'avalanche
(valable en dehors des pistes balisées et ouvertes)

MASSIF : Maurienne

Rédigé le mercredi 25 mars 2026 à 16h

Estimation des risques pour le : JEUDI 26 MARS

TEMPETE EN MONTANGE. NEIGE ET VENT FORT.

3

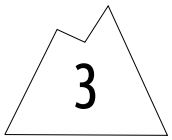

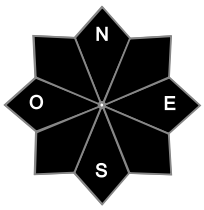

Même loin des crêtes

Indice de risque marqué.

Départs spontanés : toute la journée.

Déclenchements provoqués : nombreuses plaques très réactives.

Indices de risque : 5 très fort - 4 fort - 3 marqué - 2 limité - 1 faible -- En noir : les pentes les plus dangereuses

Stabilité du manteau neigeux

Situation avalancheuse typique : neige ventée neige fraîche

Déclenchements provoqués : nombreuses plaques dans ce contexte neigeux et venté. On le trouve en tous versants, aussi bien aux **abords des crêtes qu'en bas de pentes**. Elles sont **très réactives** car en cours de formation (averses de neige et vent de Nord soutenu en cours) et d'épaisseur très variable. Les avalanches engendrées sont fréquemment de taille moyenne (taille 2).
Secteur Belledonne/Sybelles : les cumuls de neige sont plus importants qu'ailleurs, les avalanches sont plus nombreuses et généralement de plus grandes tailles.
Observables : transport de neige en cours, accumulation, fissures devant les skis.

Départs spontanés : pendant les averses et/ou tant que le vent transporte la neige, des plaques se décrochent dans les pentes/talus raides (sous le vent). Activité possible toute la journée. Avalanches petites à moyennes (taille 1 à 2).

Qualité de la neige

Enneigement : Encore un peu au dessus de la moyenne, sauf aux plus basses altitudes où les hauteurs de neige sont tout juste correctes pour la saison.

Limite skiable : 1300 m au mieux en Nord. Plutôt 1600 m en sud pas trop raide.

Qualité de la neige : nouvelle livraison de neige fraiche malheureusement battue par le vent. La couche est hétérogène. Des zones sont pelées, décapées. D'autres accumulent la neige fraîche. Le vent entretient la sensation de froid et la neige reste hivernale en journée.

Aperçu météo pour le jeudi 26 mars

	nuit	matin	après-midi	soir
Vent soutenu et chutes de neige régulières.				
Pluie-Neige	600 m	300 m	500 m	400 m
Iso 0 °C	500 m	700 m	700 m	800 m
Vent 2000 m	↓ 60 km/h	↓ 70 km/h	↓ 65 km/h	↓ 50 km/h
Vent 3000 m	↓ 75 km/h	↓ 80 km/h	↓ 80 km/h	↓ 65 km/h

Épaisseur de neige hors-piste

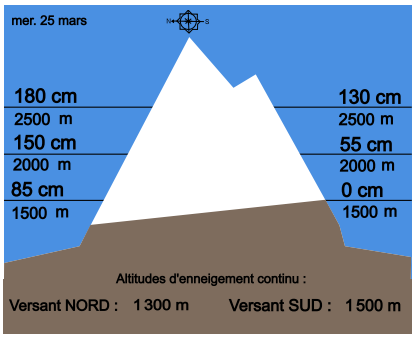

Précipitations à 1800 m

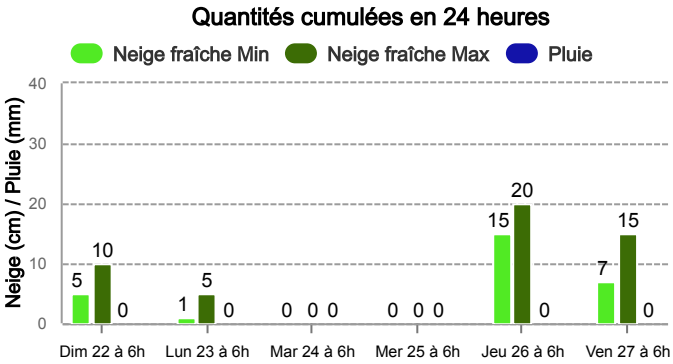

Tendance du vendredi 27 mars

3

Indice de risque marqué

Début de la stabilisation des plaques en place. Activité naturelle en adret.

Pour consulter la vigilance en cours, veuillez vous rendre sur le site https://vigilance.meteofrance.fr/fr

Météo-France - 73 avenue de Paris, 94165 Saint-Mandé cedex - Contact : contact@meteo.fr

Rédigé par Météo-France avec la contribution des observateurs du réseau nivo-météorologiques. Partenariat : ANMSM (Maires de Stations de Montagne), DSF (Domaines Skiables de France), ADSP (Directeurs de Pistes et de la Sécurité des Stations de Sports d'Hiver) et autres acteurs de la montagne.

Bulletin neige & avalanches par téléphone au

0 892 68 10 20 Service 0,35 € / min + prix appel

RÉPUBLIQUE FRANÇAISE
Liberté Égalité Fraternité

METEO FRANCE
À VOS CÔTÉS, DANS UN CLIMAT QUI CHANGE

Bulletin d'estimation du risque d'avalanche
(valable en dehors des pistes balisées et ouvertes)
MASSIF : Maurienne

Rédigé le mercredi 25 mars 2026 à 16h

Conditions nivo-météo des 7 derniers jours

	jeu. 19/03				ven. 20/03				sam. 21/03				dim. 22/03				lun. 23/03				mar. 24/03				mer. 25/03			
	03h	09h	15h	21h	03h	09h	15h	21h	03h	09h	15h	21h	03h	09h	15h	21h	03h	09h	15h	21h	03h	09h	15h	21h	03h	09h	15h	21h
Météo																												
Vent (km/h)	35	20	20	20	15	15	10	5	15	20	25	30	20	30	30	25	25	10	20	20	20	25	35	40	50	60	80	85
à 3000m																												
Vent (km/h)	20	10	10	10	5	5	5	0	5	5	15	10	10	15	25	15	10	10	20	10	10	5	15	25	30	40	65	70
à 2000m																												

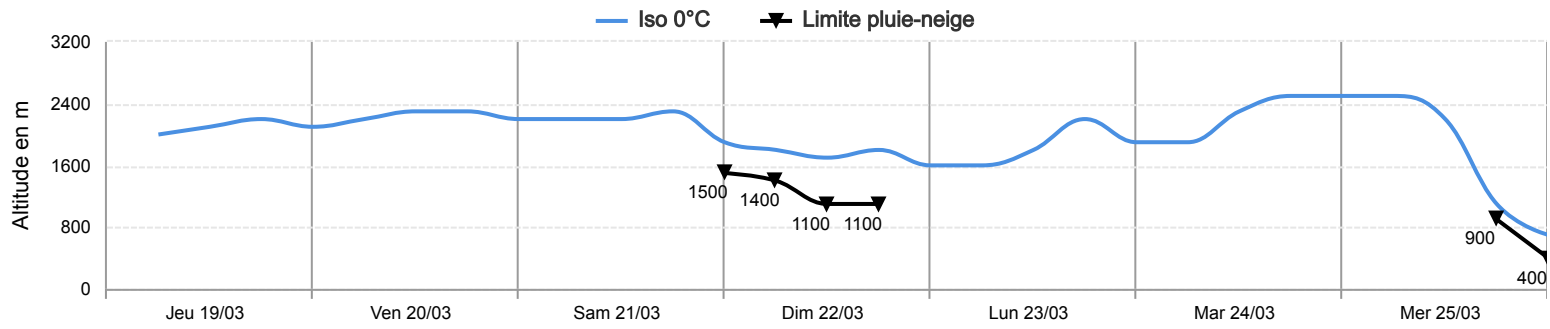

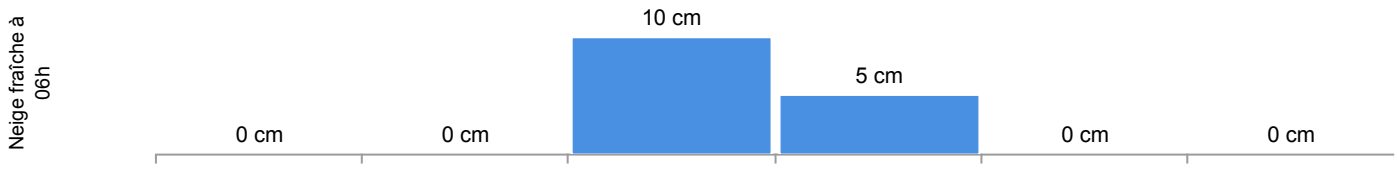

Risque d'avalanche	jeu. 19/03	ven. 20/03	sam. 21/03	dim. 22/03	lun. 23/03	mar. 24/03	mer. 25/03
	3	2	2	2	2	2	3

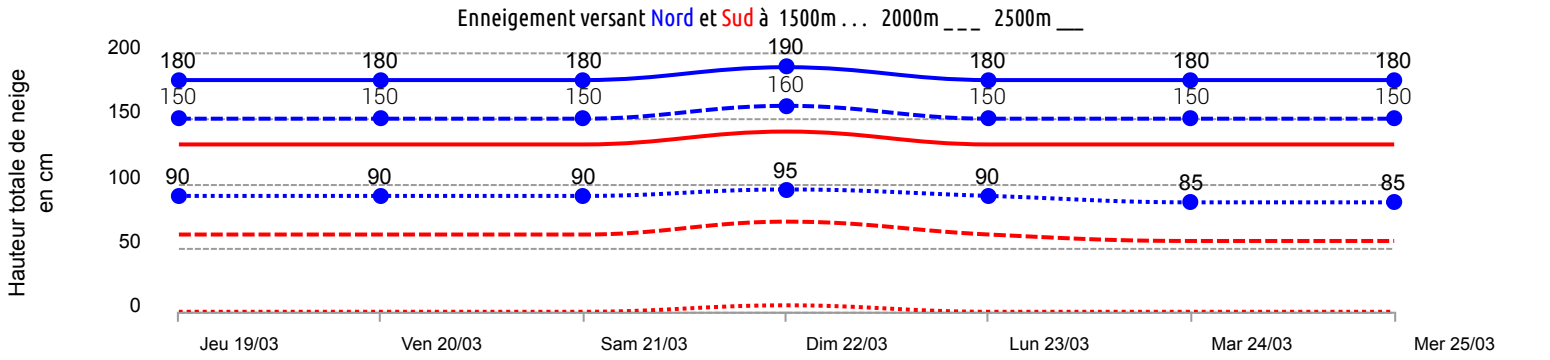

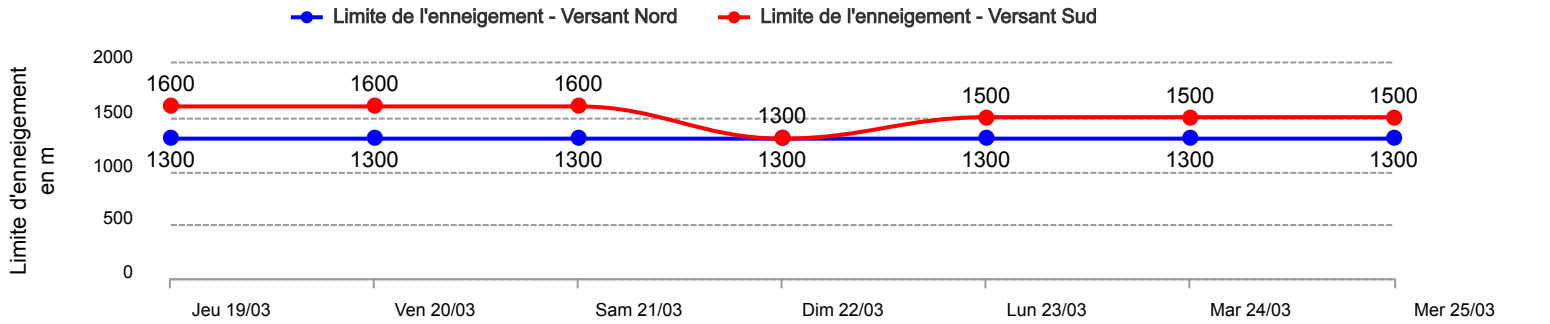

Pour consulter la vigilance en cours, veuillez vous rendre sur le site https://vigilance.meteofrance.fr/fr

Météo-France - 73 avenue de Paris, 94165 Saint-Mandé cedex - Contact : contact@meteo.fr

Rédigé par Météo-France avec la contribution des observateurs du réseau nivo-météorologiques. Partenariat : ANMSM (Maires de Stations de Montagne), DSF (Domaines Skiables de France), ADSP (Directeurs de Pistes et de la Sécurité des Stations de Sports d'Hiver) et autres acteurs de la montagne.

Bulletin neige & avalanches par téléphone au
0 892 68 10 20 Service 0,35 € / min + prix appel