Bulletin d'estimation du risque d'avalanche
(valable en dehors des pistes balisées et ouvertes)

MASSIF : Queyras

Rédigé le mercredi 25 mars 2026 à 16h

Estimation des risques pour le : JEUDI 26 MARS

NOUVELLES INSTABILITÉS DANS LA NEIGE FORTEMENT VENTÉE

3

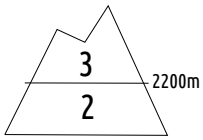

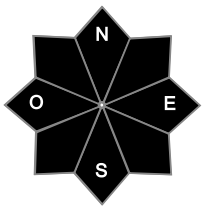

Au-dessus de 2200m indice de risque marqué, plus bas indice limité.

Départs spontanés : sous l'effet du vent, taille petite à moyenne

Déclenchements provoqués : nouvelles instabilités formées par le vent

Indices de risque : 5 très fort - 4 fort - 3 marqué - 2 limité - 1 faible -- En noir : les pentes les plus dangereuses

Stabilité du manteau neigeux

Situation avalancheuse typique : neige ventée couche fragile persistante

Déclenchements provoqués : instabilités sur de nombreuses pentes d'altitude, surtout au-dessus de 2200 m. Possibles en toute orientation, même loin des crêtes, elles sont facilement déclenchables par un seul skieur et génèrent des avalanches de taille petite à moyenne (taille 1 à 2). Ces instabilités dans la neige récente fortement ventée se multiplient et deviennent localement épaisses au fil des heures, notamment sur le nord du massif, où elles sont en outre rendues difficilement identifiables par la faible visibilité. Leur déclenchement peut solliciter des couches fragiles plus enfouies et générer des avalanches de taille moyenne à grande, en large versant nord d'altitude.
Sous 2200 m, instabilité plus limitée, sous forme de plaques plus minces et localisées, car les quantités de neige mobilisable par le vent sont moindres.

Départs spontanés : nombreux sous l'effet du vent, taille petite à moyenne, grande avalanche possible dans les secteurs de plus forte accumulation par le vent à haute altitude

Qualité de la neige

L'enneigement est proche des normales pour une fin mars.
Hauteurs de neige observées : 158 cm en versant nord du col Izoard à 2300 m, 148 cm au-dessus de St Véran à 2700 m, 104 cm à la Nivôse du Col Agnel à 2630 m

Limite d'enneigement skiable : au plus bas à 1400/1500 m en ubacs bien protégés ou sur pistes forestières, plutôt 2000/2100 m en adrets.

État de la neige de surface : neige fortement travaillée par le vent, crêtes parfois décapées.

Aperçu météo pour le jeudi 26 mars

	nuit	matin	après-midi	soir

Vent fort et températures très basses, iso -10°C à 2400 m. Un peu de neige en altitude

Pluie-Neige	500 m	500 m		
Iso 0 °C	900 m	900 m	1 100 m	1 000 m
Vent 2000 m	→ 20 km/h	↓ 40 km/h	↓ 50 km/h	↘ 50 km/h
Vent 3000 m	↘ 90 km/h	↓ 80 km/h	↓ 70 km/h	↓ 60 km/h

Épaisseur de neige hors-piste

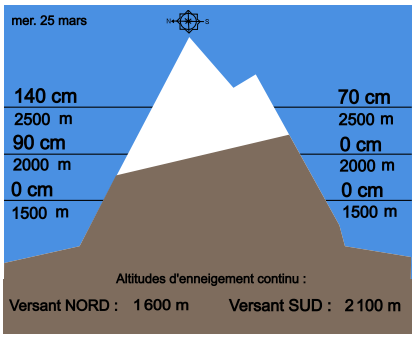

Précipitations à 1800 m

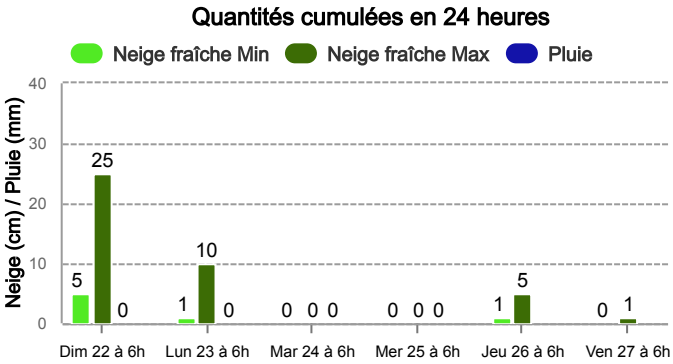

Tendance du vendredi 27 mars

Indice de risque limité

Instabilités résiduelles dans la neige ventée.
Risque limité en altitude

Pour consulter la vigilance en cours, veuillez vous rendre sur le site https://vigilance.meteofrance.fr/fr

Météo-France - 73 avenue de Paris, 94165 Saint-Mandé cedex - Contact : contact@meteo.fr

Rédigé par Météo-France avec la contribution des observateurs du réseau nivo-météorologiques. Partenariat : ANMSM (Maires de Stations de Montagne), DSF (Domaines Skiables de France), ADSP (Directeurs de Pistes et de la Sécurité des Stations de Sports d'Hiver) et autres acteurs de la montagne.

Bulletin neige & avalanches par téléphone au
0 892 68 10 20 Service 0,35 € / min + prix appel

RÉPUBLIQUE FRANÇAISE
Liberté Égalité Fraternité

METEO FRANCE
À VOS CÔTÉS, DANS UN CLIMAT QUI CHANGE

Bulletin d'estimation du risque d'avalanche

(valable en dehors des pistes balisées et ouvertes)

MASSIF : Queyras

Rédigé le mercredi 25 mars 2026 à 16h

Conditions nivo-météo des 7 derniers jours

	jeu. 19/03				ven. 20/03				sam. 21/03				dim. 22/03				lun. 23/03				mar. 24/03				mer. 25/03			
	03h	09h	15h	21h	03h	09h	15h	21h	03h	09h	15h	21h	03h	09h	15h	21h	03h	09h	15h	21h	03h	09h	15h	21h	03h	09h	15h	21h
Météo																												
Vent (km/h)	55	35	30	25	20	15	5	10	15	15	15	15	20	30	40	35	25	20	20	15	15	10	15	10	25	40	70	80
à 3000m																												
Vent (km/h)	25	20	20	15	15	10	15	5	5	10	15	10	15	25	30	30	20	15	20	10	10	10	15	5	10	20	50	60
à 2000m																												

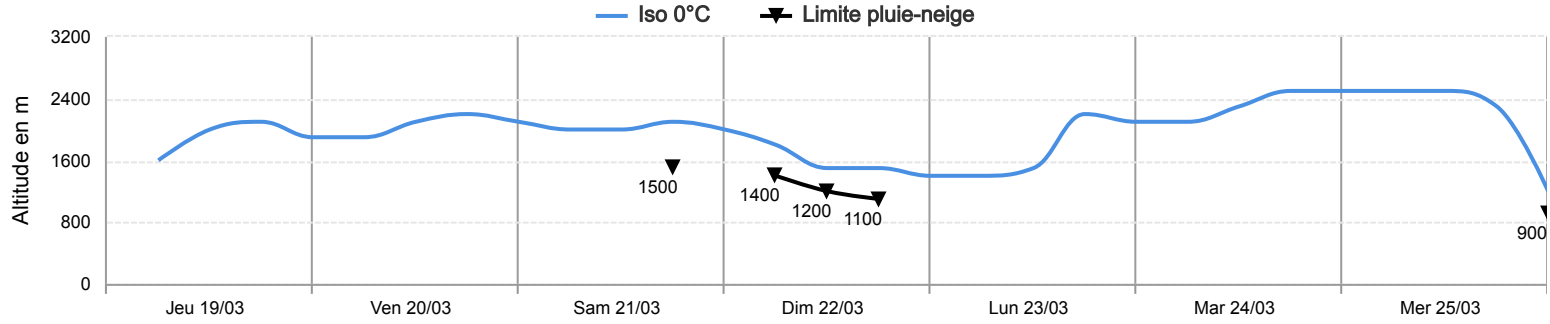

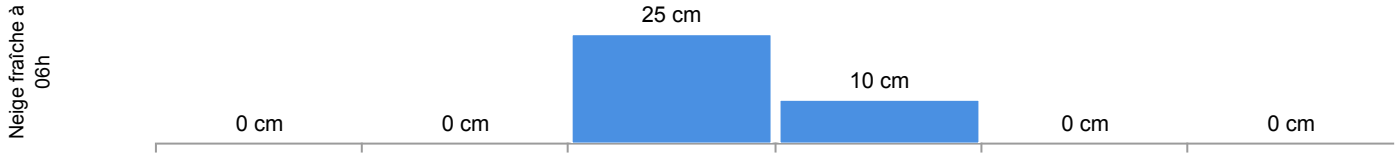

Risque d'avalanche	jeu. 19/03	ven. 20/03	sam. 21/03	dim. 22/03	lun. 23/03	mar. 24/03	mer. 25/03
	3	2	2	3	3	2	2

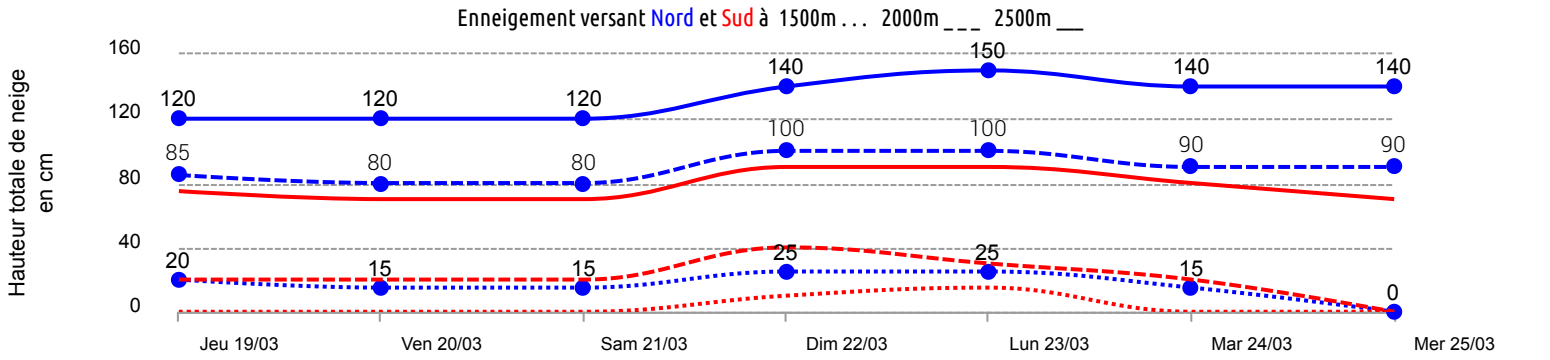

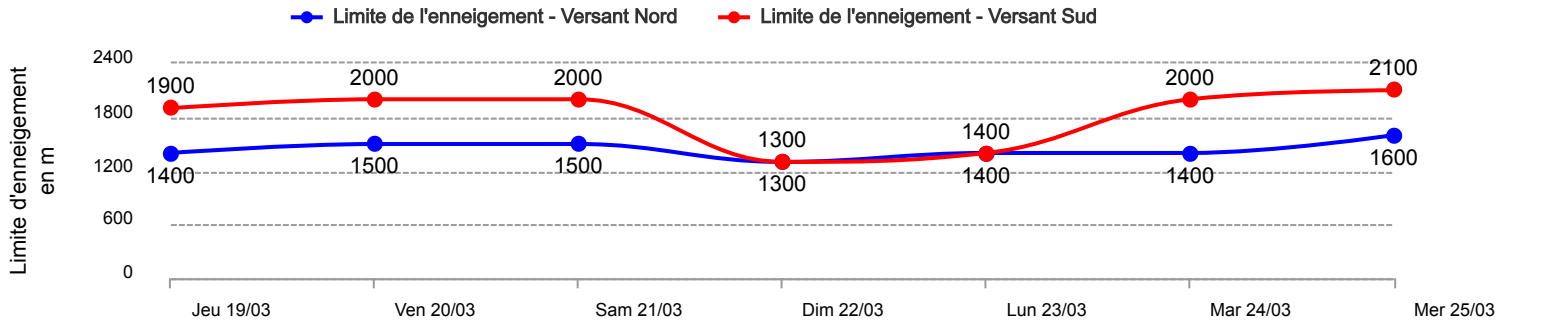

Pour consulter la vigilance en cours, veuillez vous rendre sur le site https://vigilance.meteofrance.fr/fr

Météo-France - 73 avenue de Paris, 94165 Saint-Mandé cedex - Contact : contact@meteo.fr

Bulletin neige & avalanches par téléphone au

0 892 68 10 20 Service 0,35 € / min + prix appel

Rédigé par Météo-France avec la contribution des observateurs du réseau nivo-météorologiques. Partenariat : ANMSM (Maires de Stations de Montagne), DSF (Domaines Skiables de France), ADSP (Directeurs de Pistes et de la Sécurité des Stations de Sports d'Hiver) et autres acteurs de la montagne.