Bulletin d'estimation du risque d'avalanche
(valable en dehors des pistes balisées et ouvertes)

MASSIF : Thabor

Rédigé le mercredi 25 mars 2026 à 16h

Estimation des risques pour le : JEUDI 26 MARS

NOMBREUSES NOUVELLES INSTABILITÉS DIFFICILEMENT IDENTIFIABLES EN ALTITUDE

3

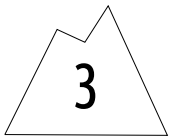

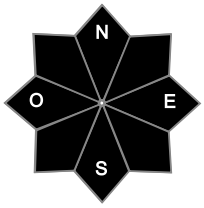

Indice de risque marqué.

Départs spontanés : sous les chutes de neige fortement ventées, taille petite à moyenne, parfois grande à haute altitude

Déclenchements provoqués : nombreuses nouvelles instabilités formées par le vent

Indices de risque : 5 très fort - 4 fort - 3 marqué - 2 limité - 1 faible -- En noir : les pentes les plus dangereuses

Stabilité du manteau neigeux

Situation avalancheuse typique : neige fraîche neige ventée

Déclenchements provoqués : instabilités sur de nombreuses pentes. Possibles en toute orientation, même loin des crêtes, elles sont facilement déclenchables par un seul skieur et génèrent des avalanches de taille petite à moyenne (taille 1 à 2), parfois grande (taille 3) dans les secteurs d'accumulation par le vent de haute altitude. Ces instabilités dans la neige fraîche ventée se multiplient et deviennent localement très épaisses au fil des heures, notamment sur le secteur des Cerces et du Thabor, plus abondamment enneigés. Elles sont en outre rendues difficilement identifiables par la visibilité quasi-nulle.
En allant vers le sud du massif, ces instabilités sont un peu moins épaisses, et plutôt identifiables, d'aspect fortement durci dans les zones d'accumulation par le vent.

Départs spontanés : nombreux sous les chutes de neige ventée, taille petite à moyenne, grande avalanche possible dans les secteurs de plus forte accumulation par le vent à haute altitude.

Qualité de la neige

L'enneigement est proche des normales pour une fin mars.
Hauteurs de neige observées vers 2500 m : 177 cm dans le vallon du Chardonnet, 121 cm à la nivôse des Rochilles, 83 cm à la Nivôse du Galibier.

Limite d'enneigement skiable : dès 1400 m en ubacs favorables (terrains herbeux, pistes forestières), 1800/1900 m en adrets pas trop raides.

État de la neige de surface : neige fraîche fortement travaillée par le vent. Formation de congères en pleine pente et d'épaisses corniches sur les crêtes, côtoyant des zones durcies voire décapées.

Aperçu météo pour le jeudi 26 mars

	nuit	matin	après-midi	soir

Conditions de blizzard à haute altitude : neige et vent fort réduisant très fortement la visibilité, températures très basses, iso -10°C à 2200 m

Pluie-Neige	600 m	300 m	500 m	400 m
Iso 0 °C	900 m	700 m	900 m	700 m
Vent 2000 m	↘ 60 km/h	↘ 60 km/h	↘ 50 km/h	↘ 50 km/h
Vent 3000 m	↓ 90 km/h	↓ 90 km/h	↓ 80 km/h	↓ 70 km/h

Épaisseur de neige hors-piste

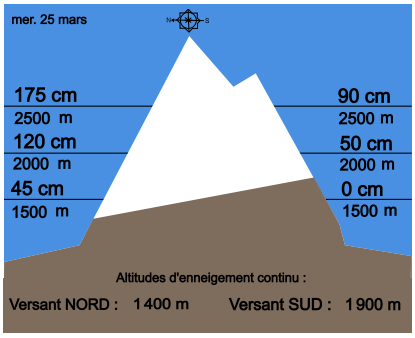

Précipitations à 1800 m

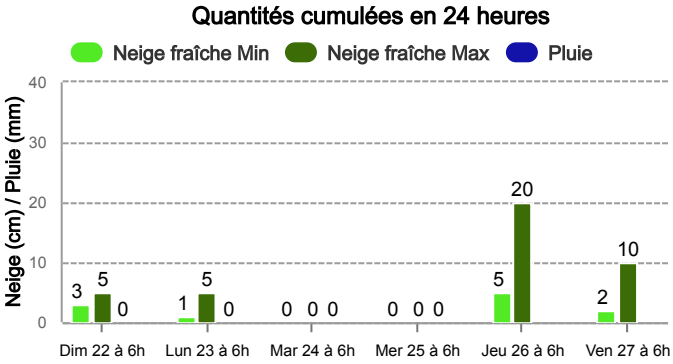

Tendance du vendredi 27 mars

3

Indice de risque marqué

Lente stabilisation des nombreuses plaques formées jeudi. Risque restant marqué en altitude

Pour consulter la vigilance en cours, veuillez vous rendre sur le site https://vigilance.meteofrance.fr/fr

Météo-France - 73 avenue de Paris, 94165 Saint-Mandé cedex - Contact : contact@meteo.fr

Rédigé par Météo-France avec la contribution des observateurs du réseau nivo-météorologiques. Partenariat : ANMSM (Maires de Stations de Montagne), DSF (Domaines Skiables de France), ADSP (Directeurs de Pistes et de la Sécurité des Stations de Sports d'Hiver) et autres acteurs de la montagne.

Bulletin neige & avalanches par téléphone au 0 892 68 10 20 Service 0,35 € / min + prix appel

RÉPUBLIQUE FRANÇAISE
Liberté Égalité Fraternité

METEO FRANCE
À VOS CÔTÉS, DANS UN CLIMAT QUI CHANGE

Bulletin d'estimation du risque d'avalanche
(valable en dehors des pistes balisées et ouvertes)

MASSIF : Thabor

Rédigé le mercredi 25 mars 2026 à 16h

Conditions nivo-météo des 7 derniers jours

	jeu. 19/03				ven. 20/03				sam. 21/03				dim. 22/03				lun. 23/03				mar. 24/03				mer. 25/03			
	03h	09h	15h	21h	03h	09h	15h	21h	03h	09h	15h	21h	03h	09h	15h	21h	03h	09h	15h	21h	03h	09h	15h	21h	03h	09h	15h	21h
Météo																												
Vent (km/h)	55	45	30	10	15	15	10	10	15	15	15	20	25	30	35	35	30	15	20	20	20	15	15	15	30	50	70	80
à 3000m																												
Vent (km/h)	20	15	15	10	10	5	5	5	5	5	5	5	10	20	25	25	20	15	20	15	10	10	15	10	15	25	70	70
à 2000m																												

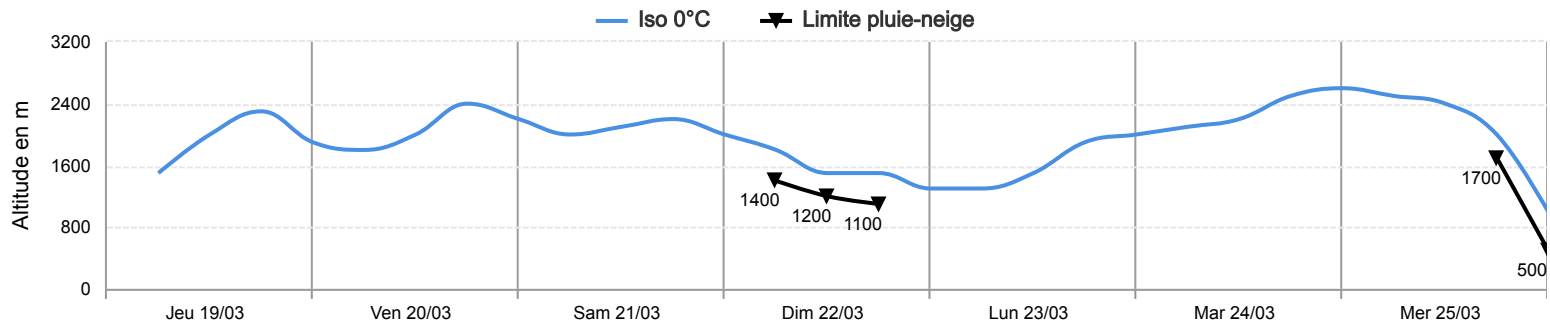

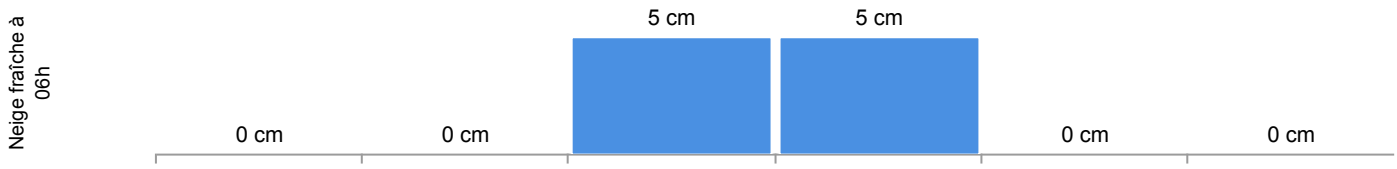

Risque d'avalanche	jeu. 19/03	ven. 20/03	sam. 21/03	dim. 22/03	lun. 23/03	mar. 24/03	mer. 25/03
	3	2	2	2	2	2	2

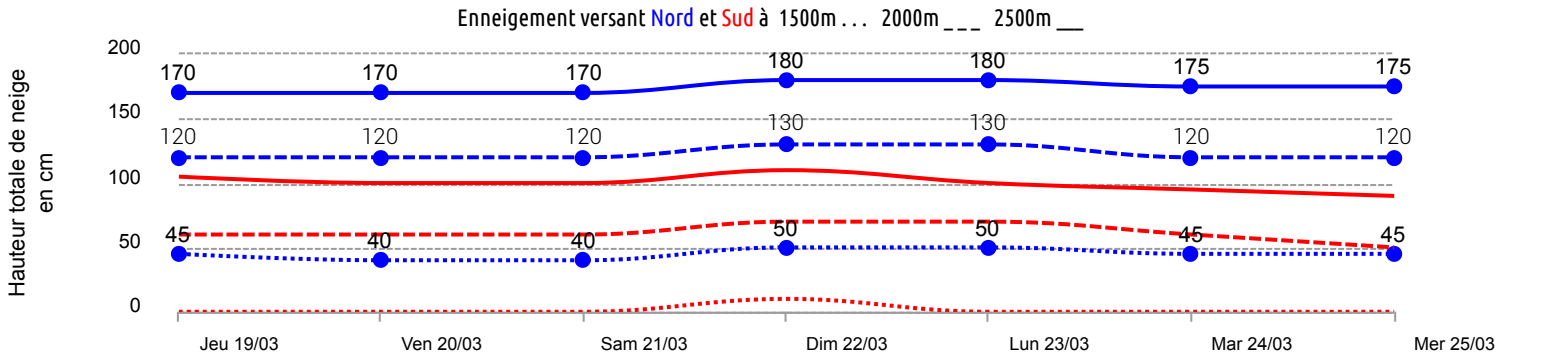

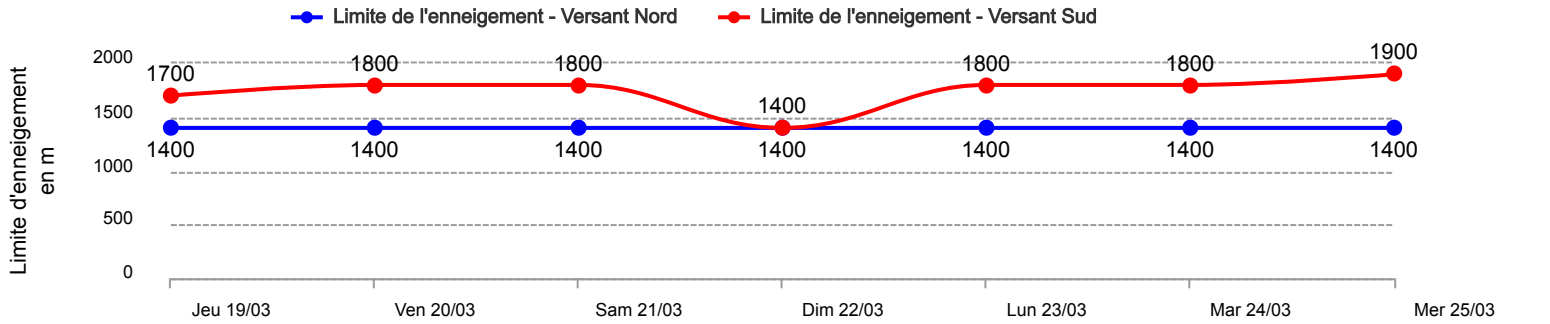

Pour consulter la vigilance en cours, veuillez vous rendre sur le site https://vigilance.meteofrance.fr/fr

Météo-France - 73 avenue de Paris, 94165 Saint-Mandé cedex - Contact : contact@meteo.fr

Rédigé par Météo-France avec la contribution des observateurs du réseau nivo-météorologiques. Partenariat : ANMSM (Maires de Stations de Montagne), DSF (Domaines Skiables de France), ADSP (Directeurs de Pistes et de la Sécurité des Stations de Sports d'Hiver) et autres acteurs de la montagne.

Bulletin neige & avalanches par téléphone au
0 892 68 10 20
Service 0,35 € / min + prix appel