Bulletin d'estimation du risque d'avalanche

(valable en dehors des pistes balisées et ouvertes)

MASSIF : Vercors

Rédigé le mercredi 25 mars 2026 à 16h

Estimation des risques pour le : JEUDI 26 MARS

FORMATION DE NOMBREUSES PLAQUES SOUS LES CHUTES DE NEIGE VENTEES

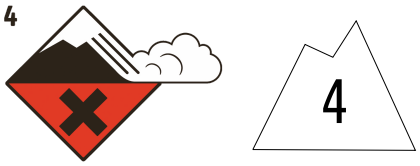

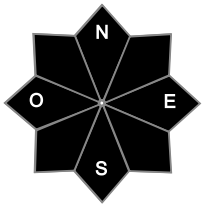

Indice de risque fort.

Départs spontanés : Nombreuses avalanches possibles sous les chutes de neige

Déclenchements provoqués : Formation de nombreuses plaques sous les chutes de neige ventées, parfois faciles à déclencher

Indices de risque : 5 très fort - 4 fort - 3 marqué - 2 limité - 1 faible -- En noir : les pentes les plus dangereuses

Stabilité du manteau neigeux

Situation avalancheuse typique : neige fraîche — neige ventée

Conditions hivernales en montagne, avec des cumuls de neige importants jusqu'à basse altitude, sous un vent de Nord sensible. D'ici jeudi soir : 30 cm possibles dés 800m, localement 40-50cm en altitude.

Déclenchements provoqués : De nombreuses plaques se forment sous les chutes de neige ventées. Elles sont présentes en tout versants, parfois loin des crêtes et sont difficiles à identifier car de tout aspect (parfois en neige poudreuse, parfois en neige dure). Elles sont souvent faciles à déclencher, et dans les secteurs d'accumulation les cassures peuvent être localement épaisses.Toutefois d'éventuelles éclaircies dans la journée pourraient rendre le manteau neigeux moins instable par tassement de la neige fraîche.

Départs spontanés : Au fil de la journée et des chutes de neige, des avalanches (souvent de tailles moyennes, parfois de grandes tailles) pourraient partir spontannément. Elle sont plus nombreuses et plus épaisses dans les pentes chargées par le vent.

Qualité de la neige

Qualification de l'enneigement : L'enneigement est bon pour la saison, même à basse altitude avec les nouvelles chutes de neige. Peu de sous couche en plein Sud et sous les sapins.

Limites skiables : Vers 1200/1600m, s'abaissant vers 1000m avec les nouveaux cumuls.

Qualité de la neige jeudi : Neige fraîche souvent déjà densifiée par le vent. Sous-couche humide dans la plupart des versants, n'ayant parfois pas encore eu le temps de regeler. En altitude, crêtes dégarnies par le vent, formations de corniches.

Aperçu météo pour le jeudi 26 mars

	nuit	matin	après-midi	soir
Giboulées de mars soutenus toute la journée, sous un vent de Nord sensible et très froid.				
Pluie-Neige	600 m	300 m	600 m	400 m
Iso 0 °C	1 100 m	800 m	1 000 m	700 m
Vent 1500 m	60 km/h	65 km/h	70 km/h	60 km/h
Vent 2000 m	65 km/h	70 km/h	75 km/h	70 km/h

Épaisseur de neige hors-piste

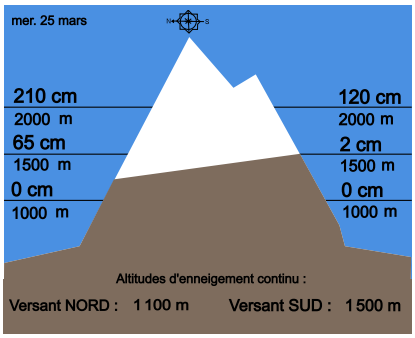

Précipitations à 1800 m

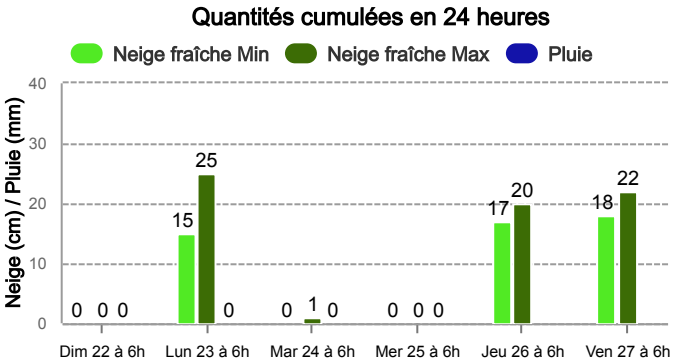

Tendance du vendredi 27 mars

Indice de risque fort

Vendredi, risque fort avec encore de nombreuses plaques qui se forment sous le vent en matinée. Légère stabilisation en journée, notamment en cas d'éclaircies.

Pour consulter la vigilance en cours, veuillez vous rendre sur le site https://vigilance.meteofrance.fr/fr

Météo-France - 73 avenue de Paris, 94165 Saint-Mandé cedex - Contact : contact@meteo.fr

Rédigé par Météo-France avec la contribution des observateurs du réseau nivo-météorologiques. Partenariat : ANMSM (Maires de Stations de Montagne), DSF (Domaines Skiables de France), ADSP (Directeurs de Pistes et de la Sécurité des Stations de Sports d'Hiver) et autres acteurs de la montagne.

Bulletin neige & avalanches par téléphone au 0 892 68 10 20 Service 0,35 € / min + prix appel

RÉPUBLIQUE FRANÇAISE
Liberté Égalité Fraternité

METEO FRANCE
À VOS CÔTÉS, DANS UN CLIMAT QUI CHANGE

Bulletin d'estimation du risque d'avalanche
(valable en dehors des pistes balisées et ouvertes)

MASSIF : Vercors

Rédigé le mercredi 25 mars 2026 à 16h

Conditions nivo-météo des 7 derniers jours

	jeu. 19/03				ven. 20/03				sam. 21/03				dim. 22/03				lun. 23/03				mar. 24/03				mer. 25/03			
	03h	09h	15h	21h	03h	09h	15h	21h	03h	09h	15h	21h	03h	09h	15h	21h	03h	09h	15h	21h	03h	09h	15h	21h	03h	09h	15h	21h
Météo																												
Vent (km/h)	20	15	20	15	20	15	15	5	10	15	5	20	20	5	15	20	25	30	30	35	30	15	15	10	20	40	65	65
à 2000m																												
Vent (km/h)	10	15	15	15	15	10	15	0	5	5	10	5	10	5	10	10	15	15	25	20	20	15	15	10	10	20	55	60
à 1500m																												

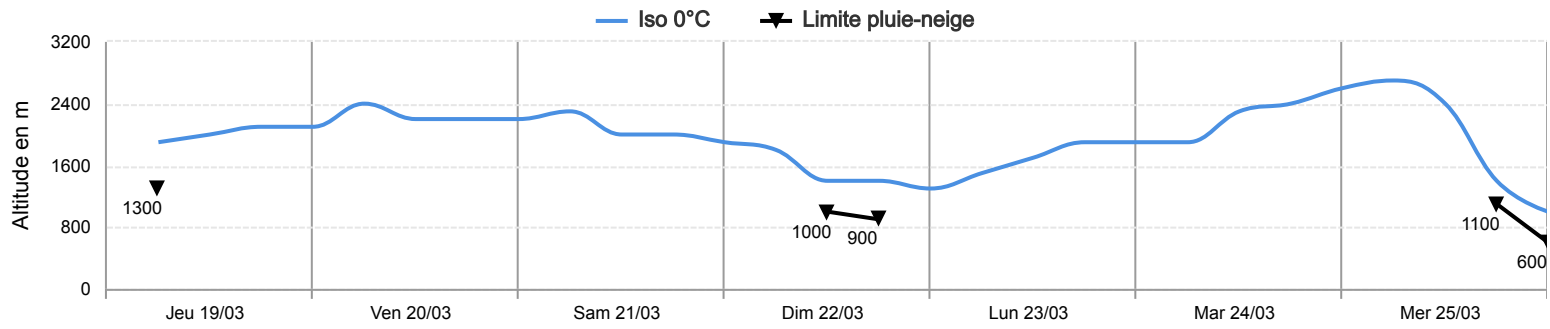

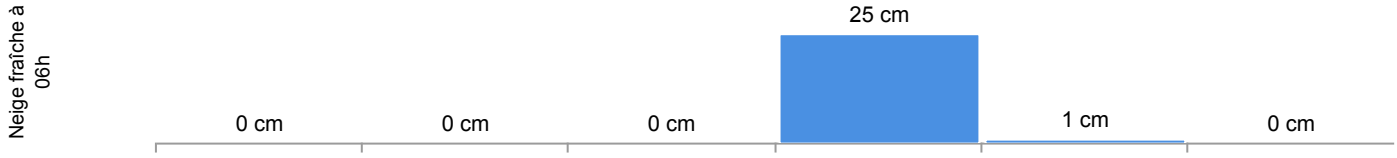

Risque d'avalanche	jeu. 19/03	ven. 20/03	sam. 21/03	dim. 22/03	lun. 23/03	mar. 24/03	mer. 25/03
	2	1	1	2	2	2	2

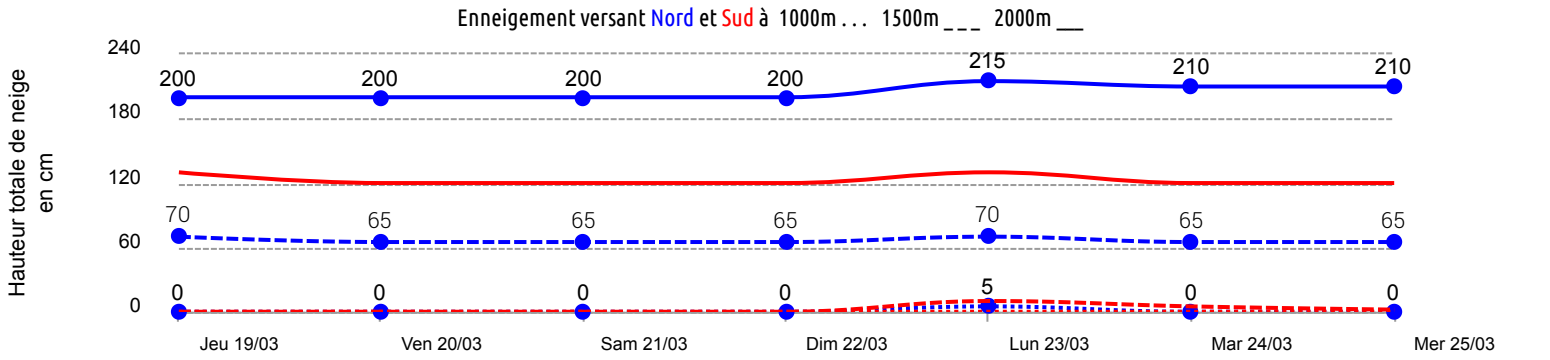

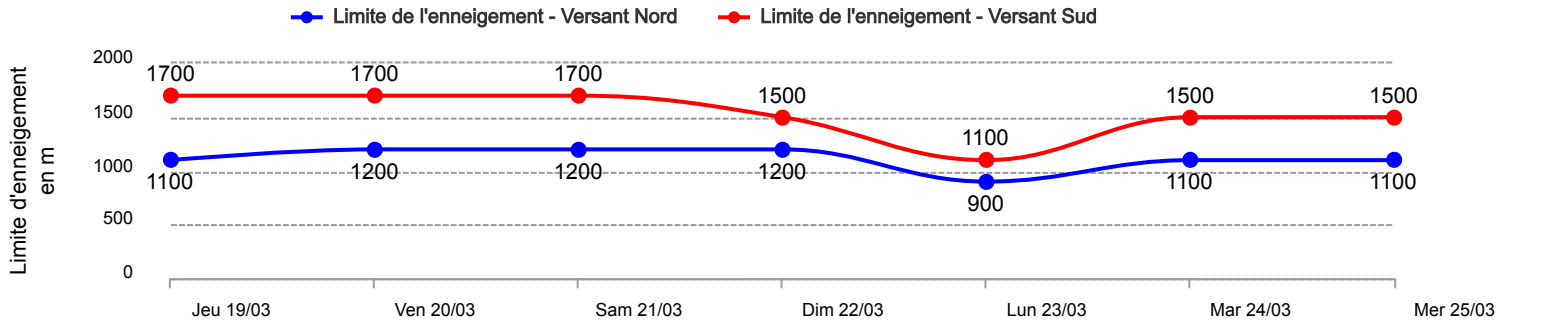

Pour consulter la vigilance en cours, veuillez vous rendre sur le site https://vigilance.meteofrance.fr/fr

Météo-France - 73 avenue de Paris, 94165 Saint-Mandé cedex - Contact : contact@meteo.fr

Rédigé par Météo-France avec la contribution des observateurs du réseau nivo-météorologiques. Partenariat : ANMSM (Maires de Stations de Montagne), DSF (Domaines Skiables de France), ADSP (Directeurs de Pistes et de la Sécurité des Stations de Sports d'Hiver) et autres acteurs de la montagne.

Bulletin neige & avalanches par téléphone au
0 892 68 10 20 Service 0,35 € / min + prix appel