GOBIERNO DE ESPAÑA
VICEPRESIDENCIA TERCERA DEL GOBIERNO
MINISTERIO PARA LA TRANSICIÓN ECOLÓGICA Y EL RETO DEMOGRÁFICO

Boletín de información nivológica y de peligro de aludes

# Pirineo Navarro y Aragonés

aemet Agencia Estatal de Meteorología

## jueves, 26 de marzo de 2026

## Pronóstico hasta las 24 horas del viernes, día 27 de marzo

(Válido fuera de pistas de esquí balizadas y abiertas)

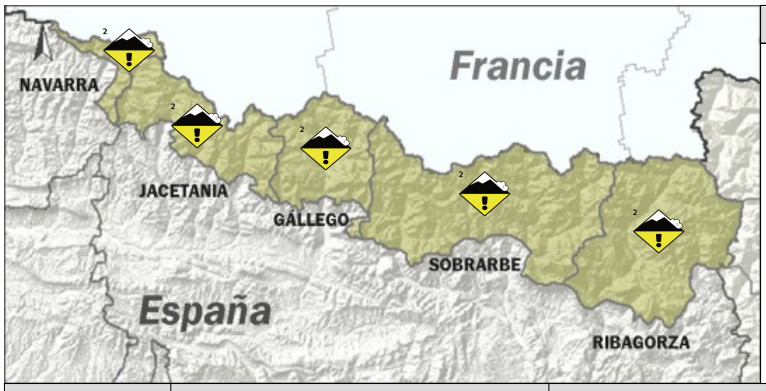


### Problemas de aludes

Capas débiles persistentes

Placas de viento

| Macizo | Peligro | Problemas de aludes, cota, orientación, tamaño | Innivación observada (m) |
|---|---|---|---|
| Navarra | 2<br>Limitado<br>2 / 1 / 2200 | **Placas de viento**<br>1800 · N O E S · 2 | 2026-03-26<br>N S<br>Cota más baja caras N |
| Jacetania | 2<br>Limitado<br>2 / 1 / 2200 | **Capas débiles persistentes**<br>2400 · N O E S · 2<br>**Placas de viento**<br>1800 · N O E S · 2 | 2026-03-26<br>N S<br>Cota más baja caras N |
| Gállego | 2<br>Limitado<br>2 / 1 / 2200 | **Capas débiles persistentes**<br>2400 · N O E S · 2<br>**Placas de viento**<br>1800 · N O E S · 1 | 2026-03-26<br>N S<br>Cota más baja caras N |
| Sobrarbe | 2<br>Limitado<br>2 / 1 / 2200 | **Capas débiles persistentes**<br>2400 · N O E S · 2<br>**Placas de viento**<br>1800 · N O E S · 1 | 2026-03-26<br>N S<br>Cota más baja caras N |


AEMET. Se autoriza la reproducción de su contenido citando la fuente.

Boletín de información nivológica y de peligro de aludes

# Pirineo Navarro y Aragonés



| | | | | | | |
|---|---|---|---|---|---|---|
| **Ribagorza** | **Limitado** | **Capas débiles persistentes** | | | 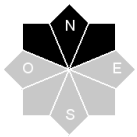  |   |
| | | **Placas de viento** | | 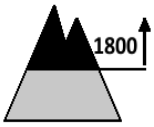  | | 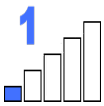  |

2026-03-26

Cota más baja caras N

## Estado del manto y observaciones recientes

La nueva situación meteorológica, caracterizada por un intenso flujo del norte y la irrupción de una masa de aire procedente de latitudes altas, ha supuesto un cambio significativo en las condiciones del manto con el cese de los procesos de fusión y el inicio de los de transporte de la nieve seca en cotas altas.

En cotas medias, la nieve húmeda previa se ha estabilizado en superficie al quedar dura o encostrada de manera generalizada, aunque en zonas a resguardo del viento se ha podido depositar una delgada capa de nieve reciente por encima. En cotas altas, se están formando nuevas placas de viento, preferentemente en orientaciones sur y este, al tiempo que en las umbrías, una antigua capa débil persistente puede mantenerse todavía activa a no demasiada profundidad.

En cuanto a la continuidad del manto, este se inicia en cotas medias, algo más arriba en laderas norte (1600 m) que en las sur (1800 m). Los espesores siguen estando por encima de lo habitual para la época, con valores de 150-200 cm en cota 2200.

## Evolución del manto y peligro de aludes para el viernes, día 27

Problema de placas de viento y capas débiles persistentes en cotas altas.

Las nuevas placas de viento permanecerán muy frágiles, y serán generalmente visibles, aisladas y pequeñas, algo más grandes y frecuentes en los macizos occidentales. Además de en cotas altas, podrán encontrarse también en cotas medias. Del Alto Gállego hacia el este, estas quedarán muy limitadas al entorno de la divisoria fronteriza.

En umbrías de cotas altas, las capas débiles persistentes pueden mantenerse todavía activas a no demasiada profundidad, siendo susceptibles de colapsar al paso de una persona en algunos puntos y dar lugar a aludes de tamaño mediano.

## Predicción meteorológica para el viernes, día 27

Pirineo navarro:
Muy nuboso o cubierto y con visibilidad localmente reducida de madrugada, tendiendo a poco nuboso con nubes altas a lo largo de la mañana. Probables precipitaciones débiles a primeras horas en la divisoria fronteriza. Cota de nieve en torno a 600-700 metros. Temperaturas sin cambios o en ligero ascenso. Heladas débiles, moderadas en cotas altas. Viento fuerte del norte y nordeste, con rachas muy fuertes en cotas altas y zonas expuestas.


AEMET. Se autoriza la reproducción de su contenido citando la fuente.

Pirineo aragonés:
Poco nuboso con nubes altas, salvo por intervalos de nubes bajas a primeras y últimas horas en la divisoria con Francia, que localmente podrán reducir la visibilidad. Al final del día, tenderá a aumentar la nubosidad. No se descartan algunas nevadas débiles y ocasionales en algunos puntos la divisoria con Francia a primeras horas. Temperaturas sin cambios o en ligero ascenso. Heladas débiles, moderadas en cotas altas, donde podrán ser localmente fuertes y persistentes. Viento moderado o fuerte de componente norte, con rachas muy fuertes en cotas altas y zonas expuestas que podrán superar los 100 km/h.

Datos en la atmósfera libre:

Altitud de la isoterma de 0 ºC: 1400 m
Altitud de la isoterma de -10 ºC: 5000 m

Viento a 1500 m: N 20 km/h
Viento a 3000 m: N 100 km/h

## Evolución para el sábado día 28

Nivel de peligro en ligero ascenso durante la segunda mitad del día, con el incremento de los problemas de nieve seca.

(Información elaborada a partir de los datos recibidos de los refugios de Linza, Lizara, Panticosa, Bachimaña, Pineta, Estós, Angel Orús, La Renclusa, Cap de Llauset y Belagua y de Ordesa Pradera)

Escala europea de peligro de aludes

Débil | Limitado | Notable | Fuerte | Muy Fuerte

Problemas de aludes

Nieve reciente | Placas de viento | Capas débiles persistentes | Nieve húmeda | Deslizamientos basales | Sin problema evidente

Nota1: Se recuerda que, siempre que haya nieve, la ausencia total de peligro no existe. Hay que tener presente que en circunstancias desfavorables, con aludes de tamaño 1 (alud pequeño o colada) y tamaño 2 (alud mediano), se pueden sufrir severos daños personales.

Nota2: Los BPA se elaboran en base a información meteorológica así como al estado del manto nivoso a través de sondeos puntuales. Se advierte a los usuarios de la variabilidad de esta información al extrapolarla a zonas extensas de montaña. Por ello, AEMET no se hace responsable de su uso para la toma de decisiones que conciernen a la seguridad personal, ni de los riesgos físicos o materiales de ellas derivadas.


AEMET. Se autoriza la reproducción de su contenido citando la fuente.