ICGC Institut Cartogràfic i Geològic de Catalunya

Servei Meteorològic de Catalunya meteo.cat

Boletín de peligro de aludes para el Pirineo de Catalunya
Del 26/03/2026 al 27/03/2026

(Válido fuera pistas de esquí y zonas no controladas)

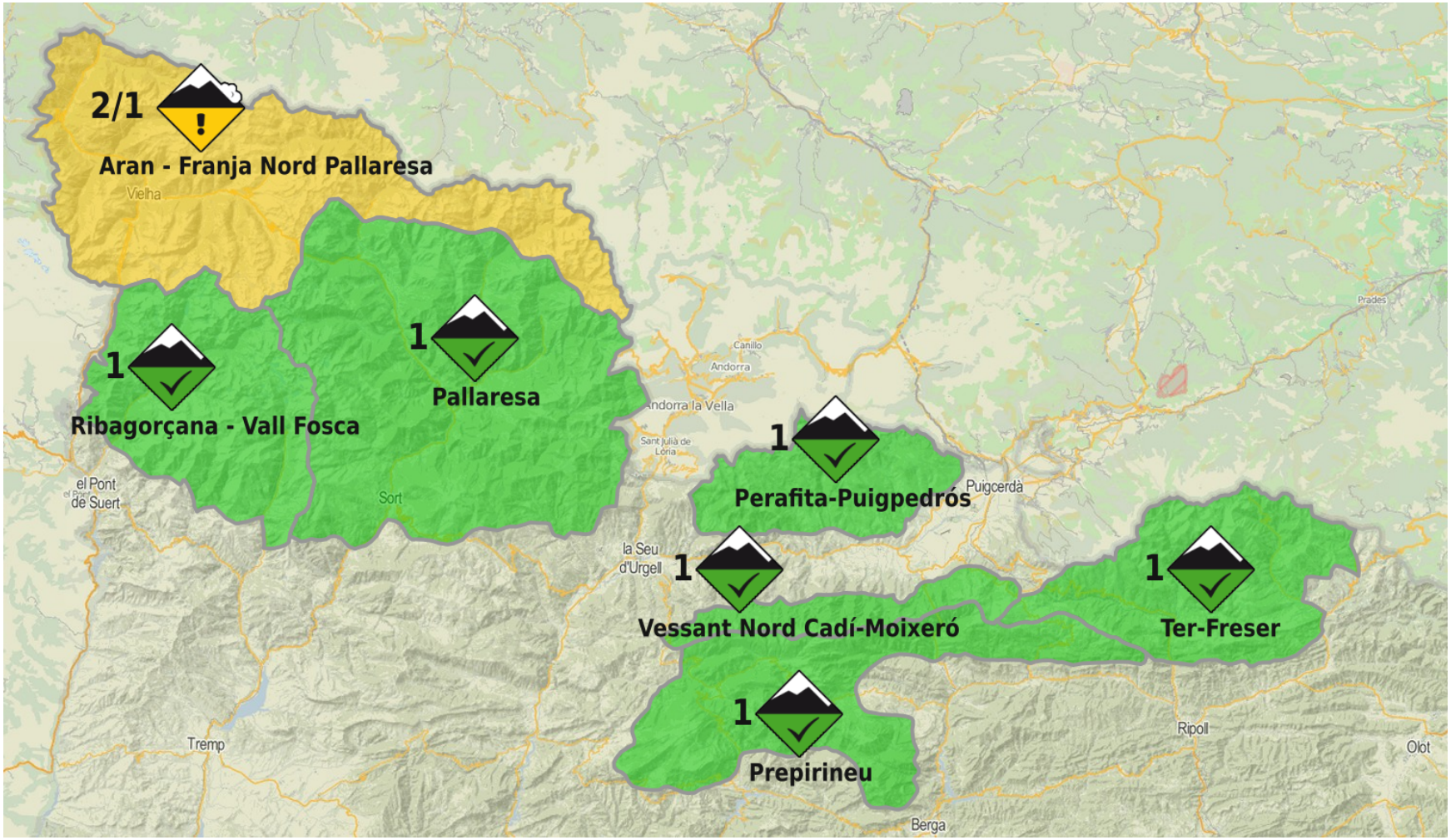

5 MUY FUERTE	4 FUERTE	3 NOTABLE	2 LIMITADO	1 DÉBIL

ICGC Institut Cartogràfic i Geològic de Catalunya

Servei Meteorològic de Catalunya

Boletín de peligro de aludes Aran - Franja Nord Pallaresa Del 26/03/2026 al 27/03/2026

(Válido fuera pistas de esquí y zonas no controladas)

LIMITADO (2), por encima de 2.200 m.
DÉBIL (1), por debajo.

Situación primaria

Nieve venteada

Distribución

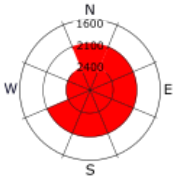

Tamaño

Origen

Tendencia

Situación secundaria

Capas débiles persistentes

Distribución

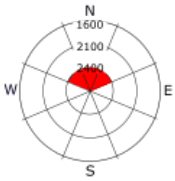

Tamaño

Origen

Tendencia

Estado del manto nivoso

El viento entre fuerte y moderado de NW y N del miércoles ha transportado la nieve reciente caída y la nieve seca del manto presente en umbrías de cota alta principalmente. Se han formado nuevas placas de pequeño tamaño, y generalmente locales, por encima del límite del bosque, bajo collados y crestas, y sectores más resguardados, posibles en cualquier orientación pero preferentemente en S y E. El viernes, sin precipitación prácticamente, y con la continuación de viento moderado-fuerte, podrá continuar la formación de pequeñas nuevas placas, en orientaciones S sobretodo.

A umbrías altas, por encima de unos 2.300 m, es posible todavía encontrar alguna placa antigua que descanse sobre niveles débiles, inestables, y por sobrecarga fuerte pueda romper y caer, generando aludes que pueden ser de tamaño pequeño o medio.

Distribución del manto nivoso

Hay nieve por encima de unos 1.600 m en umbrías y 1.900 m en solanas. Los espesores a unos 2.200 m son ligeramente superiores a los normales en la Franja Nord de la Pallaresa y en la mitad sur de Arán, donde rondan los 180-220 cm. En la mitad norte de Arán son los normales por estas fechas con unos 120-140 cm de espesor total.

Tendencia para las próximas 48-72h

Las placas de viento podrán continuar sensibles y podrán formarse nuevas. Peligro: en ligero AUMENTO.

El próximo boletín será emitido el día 2026-03-27

5 MUY FUERTE	4 FUERTE	3 NOTABLE	2 LIMITADO	1 DÉBIL

EAWS EUROPEAN AVALANCHE WARNING SERVICES

ICGC Institut Cartogràfic i Geològic de Catalunya

meteo.cat Servei Meteorològic de Catalunya

Boletín de peligro de aludes Ribagorçana - Vall Fosca Del 26/03/2026 al 27/03/2026

(Válido fuera pistas de esquí y zonas no controladas)

DÉBIL (1)

Situación primaria

Nieve venteada

Distribución

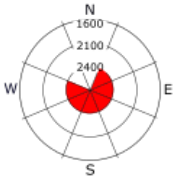

Tamaño

Origen

Tendencia

Situación secundaria

Capas débiles persistentes

Distribución

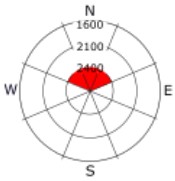

Tamaño

Origen

Tendencia

Estado del manto nivoso

El fuerte viento de NW y N ha movilizado la nieve superficial que todavía se mantiene seca en umbrías de cota alta así como la reciente que ha caído débilmente en el N del sector. Es probable la formación y presencia de nuevas placas en cota alta, pequeñas y locales, bajo collados y cordales, y sectores más resguardados donde el viento no haya barrido la nieve, sobre todo en orientaciones S y E. Las placas podrán ser sensibles y ceder al paso de una persona provocando aludes de tamaño 1, pequeño. En umbrías muy altas es posible todavía encontrar alguna placa antigua que descanse sobre niveles débiles y por sobrecarga fuerte pueda romper y caer, generando aludes de pequeño tamaño en general. En solanas principalmente, nos encontraremos un manto encostrado y endurecido, y habrá que tener cuidado con los resbalones.

Distribución del manto nivoso

Hay nieve en el suelo a 1.700 m en N, y a unos 2.100 m en S de forma discontinua, pasando a ser continua a partir de unos 2.300 m. Los grosores alcanzan los 100-120 cm a unos 2.200 m. Estos valores se acercan a los normales para la época.

Tendencia para las próximas 48-72h

Las placas de viento podrán continuar sensibles y se formarán nuevas, pequeñas. Peligro: en ligero AUMENTO.

El próximo boletín será emitido el día 2026-03-27

5 MUY FUERTE	4 FUERTE	3 NOTABLE	2 LIMITADO	1 DÉBIL

EAWS EUROPEAN AVALANCHE WARNING SERVICES

ICGC Institut Cartogràfic i Geològic de Catalunya

Servei Meteorològic de Catalunya

Boletín de peligro de aludes Pallaresa
Del 26/03/2026 al 27/03/2026

(Válido fuera pistas de esquí y zonas no controladas)

1 DÉBIL (1)

Situación primaria

Nieve venteada

Distribución

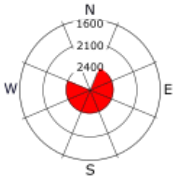

Tamaño

Origen

Tendencia

Situación secundaria

Capas débiles persistentes

Distribución

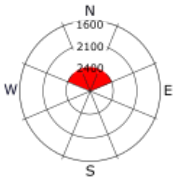

Tamaño

Origen

Tendencia

Estado del manto nivoso

El fuerte viento de NW y N ha movilizado la nieve superficial que todavía se mantiene seca en umbrías de cota alta así como la reciente que ha caído débilmente en el N del sector. Es probable la formación y presencia de nuevas placas en cota alta, pequeñas y locales, bajo collados y cordales, y sectores más resguardados donde el viento no haya barrido la nieve, sobre todo en orientaciones S y E. Las placas podrán ser sensibles y ceder al paso de una persona provocando aludes de tamaño 1, pequeño. En umbrías muy altas es posible todavía encontrar alguna placa antigua que descanse sobre niveles débiles y por sobrecarga fuerte pueda romper y caer, generando aludes de pequeño tamaño en general. En solanas principalmente, nos encontraremos un manto encostrado y endurecido, y habrá que tener cuidado con los resbalones.

Distribución del manto nivoso

Hay nieve en el suelo a 1.700 m en N, y a unos 2.100 m en S de forma discontinua, pasando a ser continua a partir de unos 2.300 m. Los espesores alcanzan los 110-150 cm en cotas medias, puntualmente más, variable según los efectos del viento.

Tendencia para las próximas 48-72h

Las placas de viento podrán continuar sensibles y se formarán nuevas, pequeñas. Peligro: en ligero AUMENTO.

El próximo boletín será emitido el día 2026-03-27

5 MUY FUERTE	4 FUERTE	3 NOTABLE	2 LIMITADO	1 DÉBIL

EAWS EUROPEAN AVALANCHE WARNING SERVICES

ICGC Institut Cartogràfic i Geològic de Catalunya

Servei Meteorològic de Catalunya

Boletín de peligro de aludes Perafita-Puigpedrós Del 26/03/2026 al 27/03/2026

(Válido fuera pistas de esquí y zonas no controladas)

DÉBIL (1)

Situación primaria

Nieve venteada

Distribución

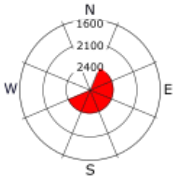

Tamaño

Origen

Tendencia

Estado del manto nivoso

El viento fuerte de N y NW ha transportado y continuará transportando, débil o moderadamente, la nieve seca superficial que se encuentra en umbrías de cota alta. La disponibilidad de nieve movilizable es baja o bastante limitada. Con estas condiciones se han podido formar placas de viento, locales y pequeñas, bajo collados y cordales y sectores resguardados de cota alta, y el viernes podrá continuar esta dinámica. Las placas se localizarán principalmente en orientaciones S y E, menos probables y frecuentes al resto, y podrán ser sensibles al paso de una persona y ceder y provocar aludes a su paso, de tamaño 1, pequeño, sin capacidad de colgarla pero si derribarla. En las solanas, nos encontraremos un manto encostrado y endurecido y habrá que tener cuidado con los resbalones. A mediodía puede ablandarse ligeramente en superficie.

Distribución del manto nivoso

Hay nieve por encima de unos 1.900 m, discontinua hasta 2.200 m en solanas. Es esquiable a partir de unos 2.000 m en N. Los espesores, aunque irregulares, rondan los 70-100 cm en umbrías, a 2.300 m. Son grosores por encima de los habituales en esta época.

Tendencia para las próximas 48-72h

Las placas de viento continuarán sensibles y se podrá formar alguna nueva. Peligro: en leve AUMENTO.

El próximo boletín será emitido el día 2026-03-27

5 MUY FUERTE	4 FUERTE	3 NOTABLE	2 LIMITADO	1 DÉBIL

EAWS EUROPEAN AVALANCHE WARNING SERVICES

ICGC Institut Cartogràfic i Geològic de Catalunya

Servei Meteorològic de Catalunya

Boletín de peligro de aludes
Vessant Nord Cadí-Moixeró
Del 26/03/2026 al 27/03/2026

(Válido fuera pistas de esquí y zonas no controladas)

DÉBIL (1)

Situación primaria

Nieve venteada

Distribución

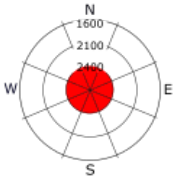

Tamaño

Origen

Tendencia

Estado del manto nivoso

Se ha observado transporte de nieve en cimas y cordales el jueves, y podrá continuar el viernes con la persistencia de viento fuerte de N y NW, aunque de forma limitada porque la nieve movilizable es reducida y localizable sólo en umbrías de cota alta. Con estas condiciones se han podido formar placas de viento, locales y pequeñas, bajo collados y cordales y sectores resguardados de cota alta. Las placas de nueva formación podrán estar presentes en cualquier orientación pero principalmente en S y E, menos probables al resto, y podrán ser sensibles al paso de una persona y ceder, provocando aludes a su paso, de tamaño 1, pequeño, sin capacidad de colgarla pero si derribarla. Sin embargo, hay que prestar atención al terreno trampa, sobre todo a las canales y torrentes, donde un alud pequeño podría llegar a enterrarnos. En las solanas, nos encontraremos un manto encostrado y endurecido y habrá que tener cuidado con los resbalones.

Distribución del manto nivoso

En umbrías hay presencia discontinua de nieve por encima de unos 1.700 m y es esquiable por encima de unos 1.900 m. Los grosores están alrededor de 160-180 cm a 2.200 m. Estos valores son muy excedentarios para la época del año.

Tendencia para las próximas 48-72h

Las placas de viento podrán continuar sensibles y se formarán nuevas, pequeñas. Peligro: en ligero AUMENTO.

El próximo boletín será emitido el día 2026-03-27

5 MUY FUERTE	4 FUERTE	3 NOTABLE	2 LIMITADO	1 DÉBIL

EAWS EUROPEAN AVALANCHE WARNING SERVICES

ICGC Institut Cartogràfic i Geològic de Catalunya

meteo.cat Servei Meteorològic de Catalunya

Boletín de peligro de aludes Prepirineu
Del 26/03/2026 al 27/03/2026

(Válido fuera pistas de esquí y zonas no controladas)

DÉBIL (1).

Situación primaria

Nieve venteada

Distribución

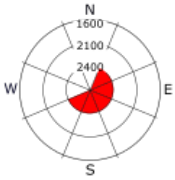

Tamaño

Origen

Tendencia

Estado del manto nivoso

A pesar de la escasa disponibilidad de nieve seca movilizable del manto, restringida a umbrías de cota alta, se ha observado transporte de nieve y podrá continuar esta situación el viernes con la continuidad de viento fuerte de N y NW. Se han podido formar nuevas, locales y pequeñas placas de viento, que pueden ser duras, bajo collados y cordales y sectores resguardados de cota alta. Las placas se localizarán principalmente en orientaciones S y E, menos probables y frecuentes al resto, y podrán ser sensibles al paso de una persona y ceder y provocar aludes a su paso, de tamaño 1, pequeño, sin capacidad de colgarla pero si derribarla. En las solanas, nos encontraremos un manto encostrado y endurecido y habrá que tener cuidado con los resbalones.

Distribución del manto nivoso

En umbrías hay nieve por encima de unos 1.700 m. En solanas la nieve está presente por encima de unos 1.900 m, discontinua. Los espesores, aunque irregulares, rondan los 90-120 cm a 2.300 m.

Tendencia para las próximas 48-72h

Las placas de viento, locales y pequeñas, podrán mantenerse reactivas. Peligro: ESTACIONARIO.

El próximo boletín será emitido el día 2026-03-27

5 MUY FUERTE	4 FUERTE	3 NOTABLE	2 LIMITADO	1 DÉBIL

EAWS EUROPEAN AVALANCHE WARNING SERVICES

ICGC Institut Cartogràfic i Geològic de Catalunya

Servei Meteorològic de Catalunya

Boletín de peligro de aludes Ter-Freser Del 26/03/2026 al 27/03/2026

(Válido fuera pistas de esquí y zonas no controladas)

DÉBIL (1)

Situación primaria

Nieve venteada

Distribución

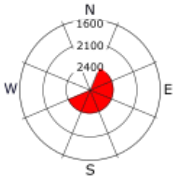

Tamaño

Origen

Tendencia

Estado del manto nivoso

El viento fuerte de N y NW ha transportado y continuará transportando la nieve seca superficial que se encuentra en umbrías de cota alta. La disponibilidad de nieve movilizable es baja o bastante limitada. Con estas condiciones se han podido formar placas de viento, locales y pequeñas, que pueden ser duras, bajo collados y cordales y sectores resguardados de cota alta, y el viernes podrá continuar esta dinámica. Las placas se localizarán principalmente en orientaciones S y E, menos probables y frecuentes al resto, y podrán ser sensibles al paso de una persona y ceder y provocar aludes a su paso, de tamaño 1, pequeño, sin capacidad de colgarla pero si derribarla. En las solanas, nos encontraremos un manto encostrado y endurecido y habrá que tener cuidado con los resbalones.

Distribución del manto nivoso

Hay nieve en el suelo por encima de unos 1.700 m. El manto es esquiable a umbrías a partir de unos 1.800 m. Los grosores son muy excedentarios para la época del año y en lugares no afectados por el viento oscilan entre 70-90 cm a unos 2.000 my más de 150 cm por encima de 2.400 m.

Tendencia para las próximas 48-72h

Las placas de viento continuarán sensibles y se puede formar alguna nueva. Peligro: en ligero AUMENTO.

El próximo boletín será emitido el día 2026-03-27

5 MUY FUERTE	4 FUERTE	3 NOTABLE	2 LIMITADO	1 DÉBIL

EAWS EUROPEAN AVALANCHE WARNING SERVICES