BUTLLETÍ DEL PERILL D'ALLAUS DEL PRINCIPAT D'ANDORRA

Elaborat el 26/03/2026 16:00
Propera actualització 27/03/2026 a les 16h

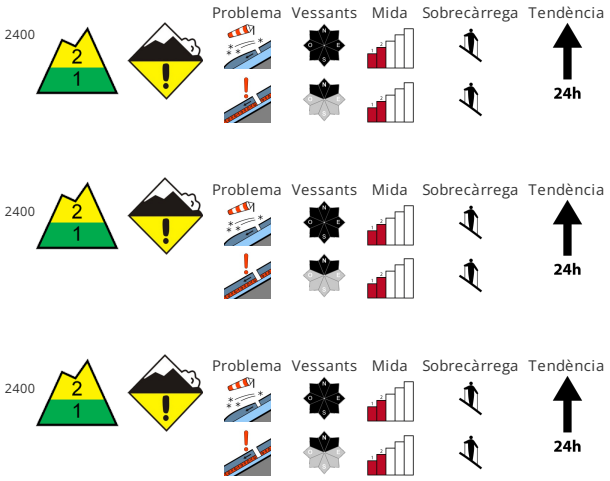

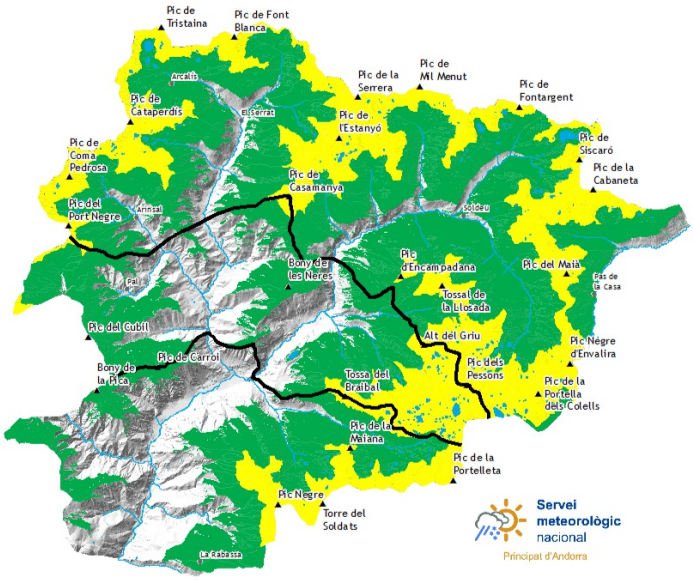

ESTABILITAT DEL MANTELL NIVAL

El vent del nord ha transportat la neu recent i, en part, també la neu vella. En el transcurs de la jornada les plaques de vent augmentaran de mida addicionalment. Els indrets perillosos es troben en totes les orientacions prop del límit del bosc. Les plaques de vent poden ser desencadenades fàcilment i assolir mida mitjana. Encara als vessants inclinats orientats a nord-oest, nord i nord-est a la part superior del mantell de neu hi ha capes febles pronunciades. A més del perill de ser enterrat per una allau, cal tenir en compte el perill de ser arrossegat cap a una trampa del terreny. Es recomana mantenir la distància entre els components.

QUALITAT DE LA NEU

El vent serà localment de moderat a fort. El mantell de neu esdevindrà cada cop més extremadament variable en pocs metres de manera generalitzada. A causa de la crosta dura hi ha el perill de relliscar i caure als vessants inclinats. Prop de les carenes els gruixos de neu varien molt per la influència del vent.

GRUIXOS DEL MANTELL NIVAL FORA DE PISTA

Zona nord		Gruix neu		
Mantell Nival		1500m	2000m	2500m
N	1600 m	0 cm	150 cm	200 cm
S	1900 m	0 cm	100 cm	150 cm

Zona centre		Gruix neu		
Mantell Nival		1500m	2000m	2500m
N	1600 m	0 cm	150 cm	200 cm
S	1900 m	0 cm	100 cm	150 cm

Zona sud		Gruix neu		
Mantell Nival		1500m	2000m	2500m
N	1600 m	0 cm	120 cm	150 cm
S	1900 m	0 cm	60 cm	100 cm

Govern d'Andorra

Aquest butlletí ha estat elaborat seguint les normes i recomanacions de l'**European Avalanche Warning Services**, del qual el **Servei meteorològic Nacional** n'és membre

BUTLLETÍ DEL PERILL D'ALLAUS DEL PRINCIPAT D'ANDORRA

Servei meteorològic nacional
Principat d'Andorra

Informació detallada per espais naturals protegits

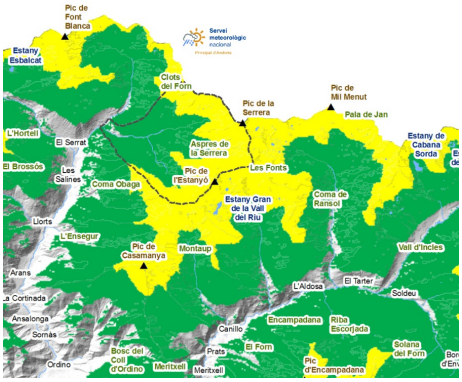

SORTENY

El vent de nord ha canviat l´escenari de perill i la gestió que n´hem de fer. S´han creat noves plaques a prop del límit del bosc degut al vent turbulent i poden continuar creixent durant les properes hores. A més, als vessants nord encara hi ha capes febles que poden desencadenar plaques i que ens han de fer mantenir la prudència amb la distància de seguretat. A partir de dissabte a la tarda tindrem un retorn del temps plenament hivernal.

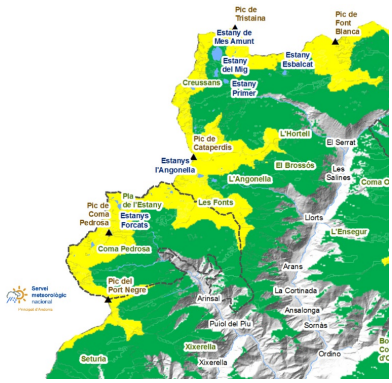

COMAPEDROSA

El vent ha afectat tot el país i les plaques s´han format sobretot en altura i al límit del bosc degut al vent turbulent. Podrem distingir la neu vella de la nova pel color, i la neu vella serà més dura i regelada.

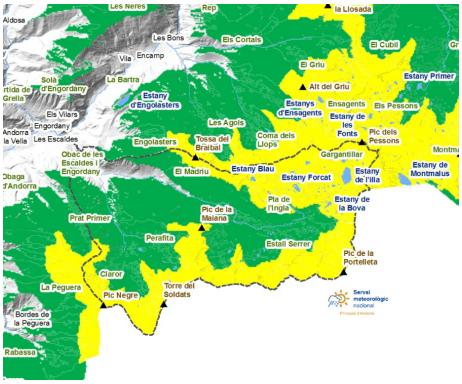

MADRIU-PERAFITA-CLAROR

Haurem d´evitar les acumulacions de neu ventada, per tant, serà més segur circular per la neu vella una mica més fosca i gelada que no pas per la neu nova. El fred dels propers dies, amb ambient hivernal a partir de dissabte, gelarà la neu a cotes baixes i mitges.

Govern d'Andorra

EAWS
EUROPEAN AVALANCHE WARNING SERVICES

Aquest butlletí ha estat elaborat seguint les normes i recomanacions de l'**European Avalanche Warning Services**, del qual el **Servei meteorològic Nacional** n'és membre

BUTLLETÍ DEL PERILL D'ALLAUS DEL PRINCIPAT D'ANDORRA

Servei meteorològic nacional
Principat d'Andorra

Gruixos de neu nova dels darrers dies (de les últimes 24h mesurat a les 06:00h UTC)

	22/03/2026	23/03/2026	24/03/2026	25/03/2026
FEDA (Central)	0 cm	0 cm	0 cm	0 cm
Engolasters - FEDA	0 cm	0 cm	0 cm	0 cm
Bony de les Neres	3 cm	0 cm	0 cm	0 cm
Sorteny	4 cm	0 cm	0 cm	2 cm
Les Fonts d'Arinsal	7 cm	0 cm	0 cm	1 cm
Perafita	7 cm	0 cm	0 cm	0 cm
Tossa Espiolets	3 cm	0 cm	0 cm	0 cm
Grau Roig - FEDA	7 cm	0 cm	0 cm	0 cm
Fontverd	0 cm	0 cm	0 cm	0 cm
Ransol - FEDA	2 cm	0 cm	0 cm	0 cm
Caborreu	0 cm	0 cm	0 cm	0 cm
La Solana	10 cm	0 cm	0 cm	2 cm
Coll Pa	0 cm	0 cm	0 cm	4 cm
Envalira Antenes	6 cm	0 cm	0 cm	0 cm
Vall del Riu FEDA	5 cm	0 cm	0 cm	2 cm