BUTLLETÍ DEL PERILL D'ALLAUS DEL PRINCIPAT D'ANDORRA

Elaborado el 26/03/2026 16:00
Proxima actualización 27/03/2026 a las 16h

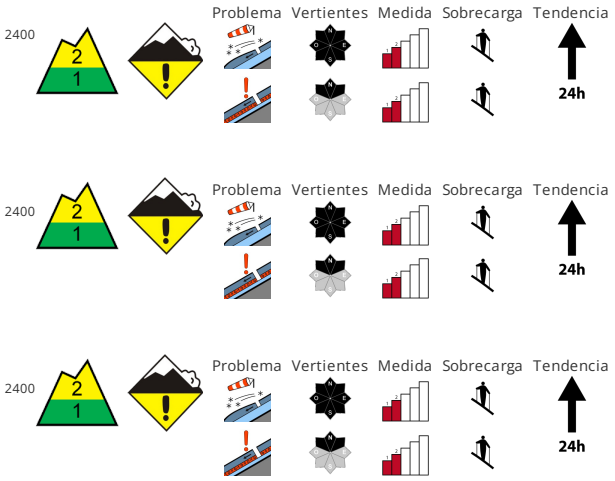

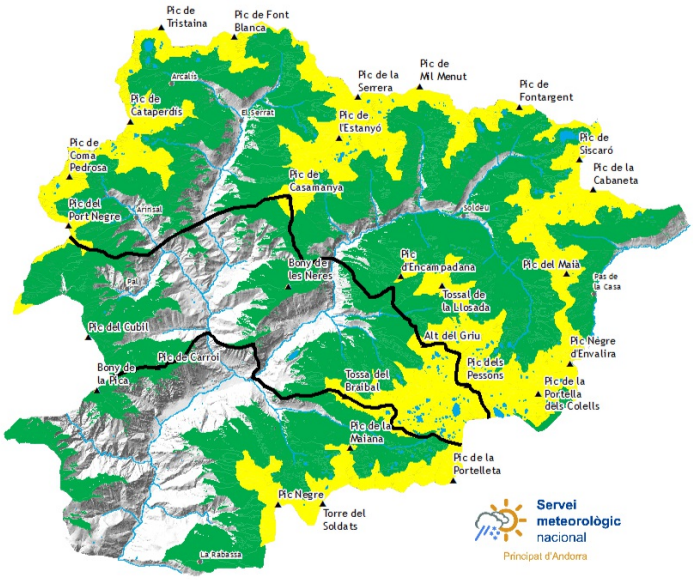

CALIDAD DE LA NIEVE

El viento del norte ha transportado la nieve reciente y, en parte, la nieve antigua. En el transcurso de la jornada las placas de viento aumentarán de tamaño adicionalmente. Los lugares peligrosos se encuentran en todas las orientaciones cerca del límite del bosque. Las placas de viento pueden ser desencadenadas fácilmente y alcanzar un tamaño mediano. Todavía en las laderas inclinadas orientadas a noroeste, norte y nordeste en la parte superior del manto de nieve hay capas débiles pronunciadas. Además del peligro de ser enterrado por un alud, se debe tener en cuenta el peligro de ser arrastrado hacia una trampa del terreno. Se recomienda mantener la distancia de seguridad entre los miembros del grupo.

ESTABILIDAD DEL MANTO NIVOSO

El viento soplará localmente de moderado a fuerte. El manto de nieve se volverá cada vez más extremadamente variable en pocos metros en general. Debido a la costra dura hay el peligro de resbalar y caer en las laderas inclinadas. Cerca de los cordales los espesores de nieve varían mucho por la influencia del viento.

ESPESORES DEL MANTO NIVOSO FUERA DE PISTA

Zona norte		Espesor nieve		
Manto Nival		1500m	2000m	2500m
N	1600 m	0 cm	150 cm	200 cm
S	1900 m	0 cm	100 cm	150 cm

zona centro		Espesor nieve		
Manto Nival		1500m	2000m	2500m
N	1600 m	0 cm	150 cm	200 cm
S	1900 m	0 cm	100 cm	150 cm

Zona sur		Espesor nieve		
Manto Nival		1500m	2000m	2500m
N	1600 m	0 cm	120 cm	150 cm
S	1900 m	0 cm	60 cm	100 cm

Govern d'Andorra

EAWS
EUROPEAN AVALANCHE WARNING SERVICES

Aquest butlletí ha estat elaborat seguint les normes i recomanacions de l'**European Avalanche Warning Services**, del qual el **Servei meteorològic Nacional** n'és membre

BUTLLETÍ DEL PERILL D'ALLAUS DEL PRINCIPAT D'ANDORRA

Servei meteorològic nacional
Principat d'Andorra

Información detallada por espacios naturales protegidos

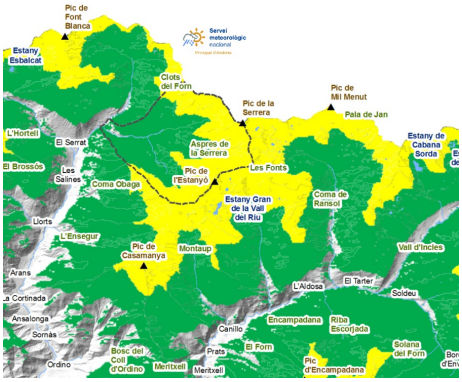

SORTENY

El viento de norte ha cambiado el escenario de peligro y la gestión que debemos hacer. Se han creado nuevas placas cerca del límite del bosque debido al viento turbulento y pueden seguir creciendo en las próximas horas. Además, en las vertientes norte todavía hay capas débiles que pueden desencadenar placas y que deben hacernos mantener la prudencia con la distancia de seguridad. A partir del sábado por la tarde tendremos un regreso del tiempo plenamente invernal.

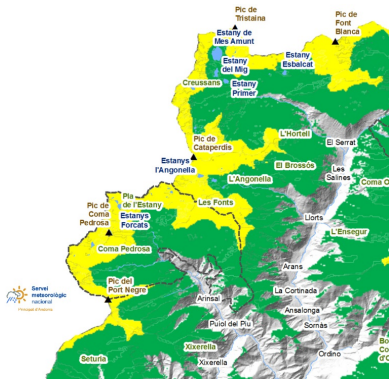

COMAPEDROSA

El viento ha afectado a todo el país y las placas se han formado sobre todo en altura y al límite del bosque debido al viento turbulento. Podremos distinguir la nieve vieja de la nueva por su color, y la nieve vieja será más dura y rehelada.

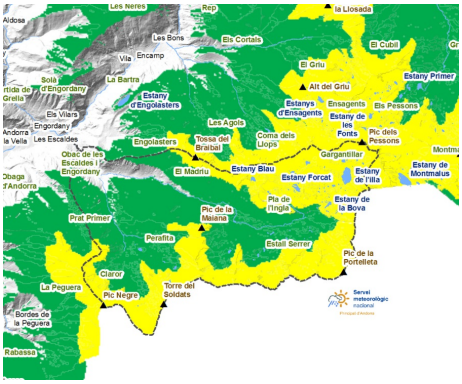

MADRIU-PERAFITA-CLAROR

Deberemos evitar las acumulaciones de nieve venteada, por tanto, será más seguro circular por la nieve vieja algo más oscura y helada que por la nieve nueva. El frío de los próximos días, con ambiente invernal a partir del sábado, helará la nieve en cotas bajas y medias.

Govern d'Andorra

EAWS
EUROPEAN AVALANCHE WARNING SERVICES

Aquest butlletí ha estat elaborat seguint les normes i recomanacions de l'**European Avalanche Warning Services**, del qual el **Servei meteorològic Nacional** n'és membre

BUTLLETÍ DEL PERILL D'ALLAUS DEL PRINCIPAT D'ANDORRA

Servei meteorològic nacional
Principat d'Andorra

Espesores de nieve nueva de los últimos días (de las ultimas 24h mesurado a las 06:00h UTC)

	22/03/2026	23/03/2026	24/03/2026	25/03/2026
FEDA (Central)	0 cm	0 cm	0 cm	0 cm
Engolasters - FEDA	0 cm	0 cm	0 cm	0 cm
Bony de les Neres	3 cm	0 cm	0 cm	0 cm
Sorteny	4 cm	0 cm	0 cm	2 cm
Les Fonts d'Arinsal	7 cm	0 cm	0 cm	1 cm
Perafita	7 cm	0 cm	0 cm	0 cm
Tossa Espiolets	3 cm	0 cm	0 cm	0 cm
Grau Roig - FEDA	7 cm	0 cm	0 cm	0 cm
Fontverd	0 cm	0 cm	0 cm	0 cm
Ransol - FEDA	2 cm	0 cm	0 cm	0 cm
Caborreu	0 cm	0 cm	0 cm	0 cm
La Solana	10 cm	0 cm	0 cm	2 cm
Coll Pa	0 cm	0 cm	0 cm	4 cm
Envalira Antenes	6 cm	0 cm	0 cm	0 cm
Vall del Riu FEDA	5 cm	0 cm	0 cm	2 cm