BUTLLETÍ DEL PERILL D'ALLAUS DEL PRINCIPAT D'ANDORRA

Préparé le 26/03/2026 16:00
Prochaine mise à jour le 27/03/2026 à 16h

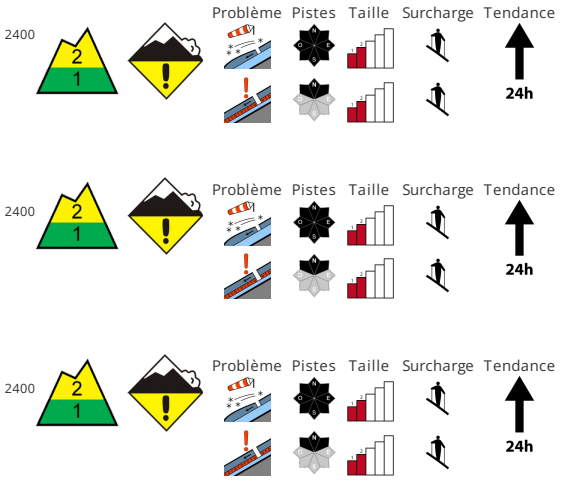

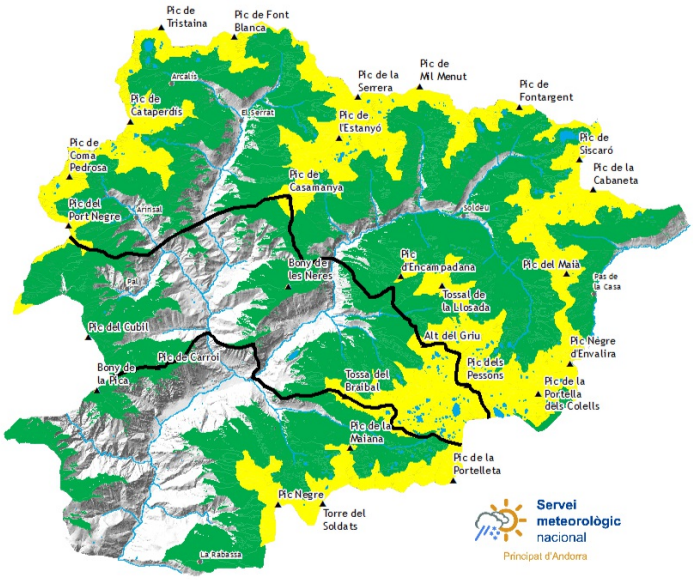

STABILITÉ DU MANTEAU NEIGEUX

Le vent du nord a transporté la neige fraîche, et partiellement aussi la neige ancienne.. En cours de journée les accumulations de neige soufflée se développent encore. Les endroits dangereux se situent à toutes les expositions dans la zone de la limite de la forêt. Les accumulations de neige soufflée peuvent peut être déchaîné facilement et atteindre une taille moyenne.. Dans la partie supérieure du manteau neigeux des couches fragiles importantes sont présentes ils se rencontrent , aussi sur les pentes raides exposées au nord-ouest , au nord et au nord-est. A côté du danger d'ensevelissement, il faut penser au danger d'être emporté et de chuter.. Des distances de délestage sont recommandées..

QUALITÈ DE LA NEIGE

Le vent souffle localement modérément à fortement. De manière généralisée le manteau neigeux sera progressivement très variable à petite échelle.. Sur la croûte dure il existe en terrain raide un risque de chute.. À proximité des crêtes on trouve suivant l'influence du vent des hauteurs de neiges très différentes.

EPAISSEUR DE NEIGE HORS PISTE

Zone nord		Epaisseur de neige		
Nival manteau		1500m	2000m	2500m
N	1600 m	0 cm	150 cm	200 cm
S	1900 m	0 cm	100 cm	150 cm

Zone centre		Epaisseur de neige		
Nival manteau		1500m	2000m	2500m
N	1600 m	0 cm	150 cm	200 cm
S	1900 m	0 cm	100 cm	150 cm

Zone sud		Epaisseur de neige		
Nival manteau		1500m	2000m	2500m
N	1600 m	0 cm	120 cm	150 cm
S	1900 m	0 cm	60 cm	100 cm

BUTLLETÍ DEL PERILL D'ALLAUS DEL PRINCIPAT D'ANDORRA

Servei meteorològic nacional
Principat d'Andorra

Des informations détaillées par espace naturel protégé

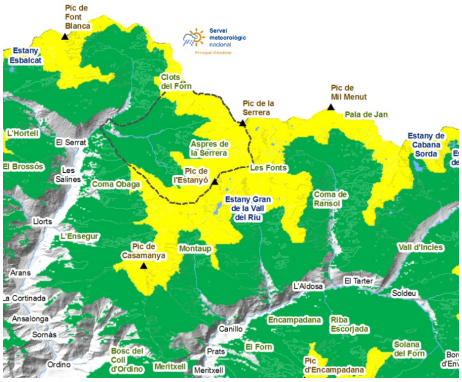

SORTENY

Le vent du nord a changé le scénario de danger et la gestion que nous devons faire. De nouvelles parcelles ont été créées près de la lisière de la forêt en raison des vents turbulents et pourraient continuer à s'étendre au cours des prochaines heures. De plus, sur les versants nord, il existe encore des couches faibles qui peuvent déclencher des plaques et qui doivent nous inciter à rester prudents quant à la distance de sécurité. Dès samedi après-midi nous aurons un retour d'un temps pleinement hivernal. , , , , , , ,

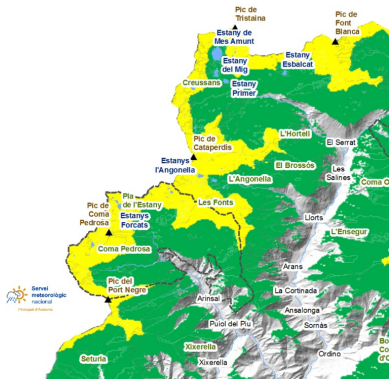

COMAPEDROSA

Le vent a touché tout le pays et les plaques se sont formées principalement en hauteur et en lisière de forêt à cause du vent turbulent. Nous pourrons distinguer la vieille neige de la nouvelle par la couleur, et la vieille neige sera plus dure et gelée. , , ,

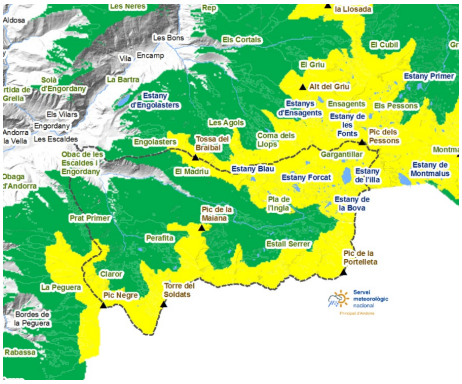

MADRIU-PERAFITA-CLAROR

Nous devrons éviter les accumulations de neige soufflée par le vent, il sera donc plus sûr de conduire sur de la vieille neige un peu plus foncée et plus froide que sur de la nouvelle neige. Le froid des prochains jours, avec une ambiance hivernale dès samedi, va geler la neige à basse et moyenne altitude. , , ,

Govern d'Andorra

EAWS
EUROPEAN AVALANCHE WARNING SERVICES

Aquest butlletí ha estat elaborat seguint les normes i recomanacions de l'**European Avalanche Warning Services**, del qual el **Servei meteorològic Nacional** n'és membre

BUTLLETÍ DEL PERILL D'ALLAUS DEL PRINCIPAT D'ANDORRA

Servei meteorològic nacional
Principat d'Andorra

Couche de neige fraiche des derniers jours (De 24 h mesurée à 06:00 h UTC)

	22/03/2026	23/03/2026	24/03/2026	25/03/2026
FEDA (Central)	0 cm	0 cm	0 cm	0 cm
Engolasters - FEDA	0 cm	0 cm	0 cm	0 cm
Bony de les Neres	3 cm	0 cm	0 cm	0 cm
Sorteny	4 cm	0 cm	0 cm	2 cm
Les Fonts d'Arinsal	7 cm	0 cm	0 cm	1 cm
Perafita	7 cm	0 cm	0 cm	0 cm
Tossa Espiolets	3 cm	0 cm	0 cm	0 cm
Grau Roig - FEDA	7 cm	0 cm	0 cm	0 cm
Fontverd	0 cm	0 cm	0 cm	0 cm
Ransol - FEDA	2 cm	0 cm	0 cm	0 cm
Caborreu	0 cm	0 cm	0 cm	0 cm
La Solana	10 cm	0 cm	0 cm	2 cm
Coll Pa	0 cm	0 cm	0 cm	4 cm
Envalira Antenes	6 cm	0 cm	0 cm	0 cm
Vall del Riu FEDA	5 cm	0 cm	0 cm	2 cm