MINISTERO DELLA DIFESA

meteomont
Servizio Nazionale di previsione neve e valanghe

EAWS EUROPEAN AVALANCHE WARNING SERVICES

CARABINIERI

MAJELLA

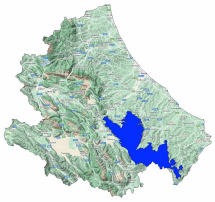

Bollettino Valanghe N. 373/2026 del 26/03/2026 ore 14.00
Validità 48 ore prossima emissione 27/03/2026

A cura del Servizio METEOMONT dell'ARMA dei CARABINIERI
In collaborazione con Servizio Meteorologico dell'Aeronautica militare

SITUAZIONE alle 14:00 del 26/03/2026

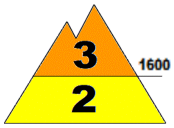

SITUAZIONE TIPO: neve a debole coesione e vento.

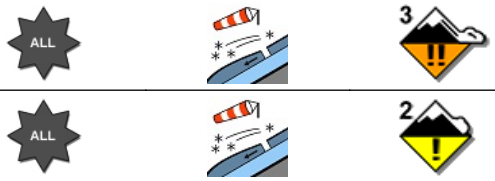

SITUAZIONE TIPO: neve a debole coesione e vento.

Quota neve (mslm)	Nord	Sud
	1200	1200

Altezza Neve (cm)	Neve al suolo	Neve Fresca	Quota (mslm)
	056	000	1650
	007	001	1200

VALANGHE OSSERVATE: Nessuna valanga.

PREVISIONI 27/03/2026

GRADO DI PERICOLO: MARCATO 3

SITUAZIONE TIPO: neve a debole coesione e vento.

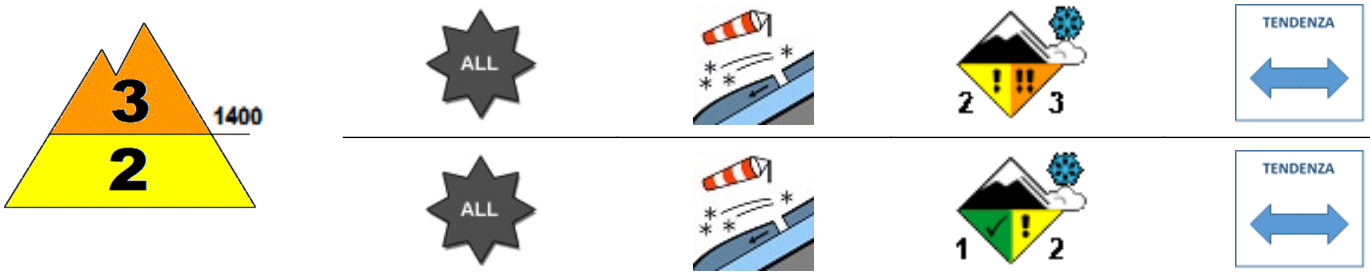

SITUAZIONE TIPO: neve a debole coesione e vento.

MANTO NEVOSO: La stabilità del manto nevoso è scarsa su alcuni punti (aree) per tutte le esposizioni al di sopra di 1400 mslm, possibili valanghe di dimensioni grandi.
La stabilità del manto nevoso è discreta su alcuni punti (aree) per tutte le esposizioni al di sotto di 1400 mslm, possibili valanghe di dimensioni medie.

AVVERTENZE

A seguito dell'attività eolica registrata sono da evitare le zone di accumulo, conche, canaloni, cambi di pendenza e pendii sotto vento in genere.

SCALA EUROPEA DEL GRADO DI PERICOLO VALANGHE

LEGENDA PROBLEMA

Bollettino realizzato su scala sinottica-regionale (standard EAWS). La sua valutazione non può escludere in alcun modo la necessità di una seria e capace valutazione locale del pericolo (singolo pendio) che può essere anche sensibilmente diverso. Le previsioni meteorologiche sono relative all'orario UTC (per l'Italia +1 in inverno e +2 in estate).

MINISTERO DELLA DIFESA

meteomont
Servizio Nazionale di previsione neve e valanghe

EAWS EUROPEAN AVALANCHE WARNING SERVICES

CARABINIERI

MAJELLA

PREVISIONE METEO

Quota		27/03/2026 h6:00	27/03/2026 h12:00	27/03/2026 h18:00
1000	Venti	08 Nodi da Nord	06 Nodi da Nord	06 Nodi da Nord
	Temperature	-07 °C	-06 °C	-05 °C
	Temp.percepita	-13 °C	-11 °C	-10 °C
2000	Venti	17 Nodi da Nord	14 Nodi da Nord	13 Nodi da Nord
	Temperature	-09 °C	-08 °C	-06 °C
	Temp.percepita	-18 °C	-16 °C	-13 °C
3000	Venti	16 Nodi da Nord	13 Nodi da Nord	12 Nodi da Nord
	Temperature	-16 °C	-14 °C	-13 °C
	Temp.percepita	-27 °C	-24 °C	-22 °C
Zero termico		0500-0700 m.	0700-0900 m.	0900-1100 m.
Fenomeno				
Stato del cielo				

LEGENDA FENOMENI

Assenza Fenomeni — Nebbia — Foschia — Pioggia debole — Pioggia moderata — Pioggia forte — Temporali

Nevicata debole — Nevicata moderata — Nevicata forte

STATO DEL CIELO

Sereno — Poco nuvoloso — Nuvoloso — Molto nuvoloso — Coperto

Parametri meteonivometrici registrati presso i campi di rilevamento il 26/03/2026.

Località	Comune	Quota (m.s.l.m.)	Altezza neve (cm)	Neve caduta nelle 24 ore (cm)	Temp. Min (°C)	Temp. Max (°C)	Condizioni del tempo
QUARTARANA	Campo di Giove (AQ)	1200	7	1	0	+13	Nevicata moderata
PASSOLANCIANO	Lettomanoppello (PE)	1300	32	1	0	+11	Assenza di precipitazioni
VALICO DELLA FORCHETTA	Palena (CH)	1270	5	0	+1	+5	Pioggia debole intermittente
VALLE DEL SOLE	Pizzoferrato (CH)	1440	5	Tracce di neve	-1	+8	Nevicata debole intermittente
MAIELETTA MAMMA ROSA	Pretoro (CH)	1650	56	Tracce di neve	-4	0	Nevicata debole continua
PASSO SAN LEONARDO	Sant'Eufemia a Maiella (PE)	1145	0	0	+0	+12	Nevicata debole intermittente

(*) Rilievi fuori campo

L'INFORMAZIONE E' PREVENZIONE - LEGGI L'ATTUALE GRADO DI PERICOLO VALANGHE!

IL CAPO DEL CENTRO NAZIONALE METEOMONT
(Ten. Col. RFI Emanuela Gini)
FIRMA AUTOGRAFA OMESSA AI SENSI
DELL'ART.3 DEL D.LGS N.39/1993

Bollettino realizzato su scala sinottica-regionale (standard EAWS). La sua valutazione non può escludere in alcun modo la necessità di una seria e capace valutazione locale del pericolo (singolo pendio) che può essere anche sensibilmente diverso. Le previsioni meteorologiche sono relative all'orario UTC (per l'Italia +1 in inverno e +2 in estate).