Bulletin d'estimation du risque d'avalanche
(valable en dehors des pistes balisées et ouvertes)

MASSIF : Champsaur

Rédigé le jeudi 26 mars 2026 à 15h

Estimation des risques pour le : VENDREDI 27 MARS

NOMBREUSES INSTABILITÉS FORMÉES PAR LE VENT DE NORD

3

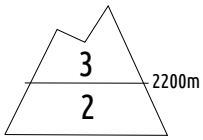

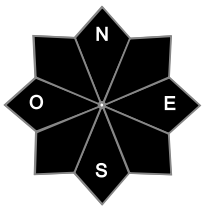

Au-dessus de 2200m indice de risque marqué, plus bas indice limité.

Départs spontanés : parfois de taille moyenne sous l'effet du vent jeudi soir

Déclenchements provoqués : nombreuses instabilités, plus épaisses en altitude

Indices de risque : 5 très fort - 4 fort - 3 marqué - 2 limité - 1 faible -- En noir : les pentes les plus dangereuses

Stabilité du manteau neigeux

Situation avalancheuse typique : neige ventée

Déclenchements provoqués : instabilités sur de nombreuses pentes. Possibles en toute orientation, même loin des crêtes, elles sont déclenchables par un seul skieur et peuvent générer des avalanches de taille petite à moyenne (taille 1 à 2). Ces instabilités formées sous l'effet du fort vent de nord jeudi sont généralement d'aspect dur, avec cassure peu large mais localement épaisse, notamment sur le nord du massif.
En allant vers le sud du massif et sous 2000 m d'altitude environ, ces instabilités sont un peu moins épaisses, généralement de taille 1.

Départs spontanés : avalanche de taille moyenne encore possible jeudi soir dans les secteurs de plus forte accumulation par le vent à haute altitude. Peu probables vendredi en journée.

Qualité de la neige

L'enneigement est proche des normales ou excédentaire pour une fin mars.
Hauteurs de neige observées : 130 cm à la Nivôse d'Orcières à 2280 m, et 188 cm au-dessus de Prapic à 2480 m.

Limite d'enneigement skiable : dès 1400 m en ubacs favorables (terrains herbeux, pistes forestières), 1700/1800 m en adrets pas trop raides.

État de la neige de surface : neige récente fortement travaillée par le vent. Nombreuses congères dans les pentes. Sur les crêtes, d'épaisses corniches côtoient des zones dégarnies voire pelées par le vent.
Petite humidification de surface au soleil jusqu'à 2200/2400 m environ.

Aperçu météo pour le vendredi 27 mars

nuit	matin	après-midi	soir

Rapidement beau et peu venté. Timide redoux en altitude, max 0/+2°C à 2000 m, -4/-6 à 3000 m.

Pluie-Neige				
Iso 0 °C	1 100 m	1 300 m	1 800 m	2 000 m
Vent 2000 m	↓ 50 km/h	↘ 10 km/h	↘ 10 km/h	← 10 km/h
Vent 3000 m	↓ 65 km/h	↓ 50 km/h	← 30 km/h	← 20 km/h

Épaisseur de neige hors-piste

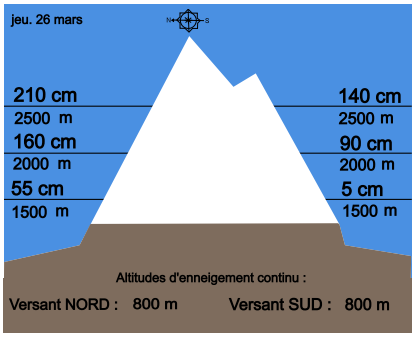

Précipitations à 1800 m

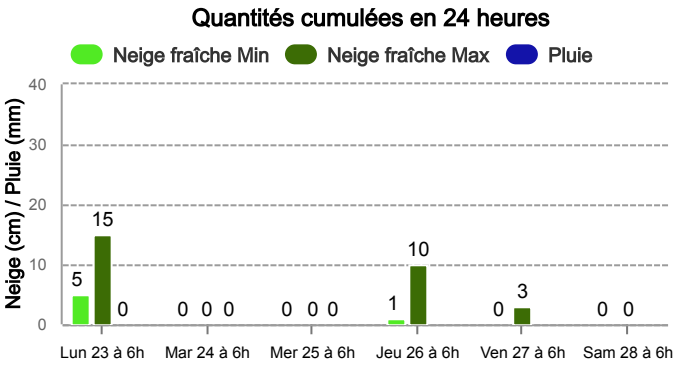

Tendance du samedi 28 mars

2

Indice de risque limité

Risque en baisse. Instabilités résiduelles dans la neige ventée. Risque limité.

Pour consulter la vigilance en cours, veuillez vous rendre sur le site https://vigilance.meteofrance.fr/fr

Météo-France - 73 avenue de Paris, 94165 Saint-Mandé cedex - Contact : contact@meteo.fr

Rédigé par Météo-France avec la contribution des observateurs du réseau nivo-météorologiques. Partenariat : ANMSM (Maires de Stations de Montagne), DSF (Domaines Skiables de France), ADSP (Directeurs de Pistes et de la Sécurité des Stations de Sports d'Hiver) et autres acteurs de la montagne.

Bulletin neige & avalanches par téléphone au 0 892 68 10 20 Service 0,35 € / min + prix appel

RÉPUBLIQUE FRANÇAISE
Liberté Égalité Fraternité

METEO FRANCE
À VOS CÔTÉS, DANS UN CLIMAT QUI CHANGE

Bulletin d'estimation du risque d'avalanche

(valable en dehors des pistes balisées et ouvertes)

MASSIF : Champsaur

Rédigé le jeudi 26 mars 2026 à 15h

Conditions nivo-météo des 7 derniers jours

	ven. 20/03				sam. 21/03				dim. 22/03				lun. 23/03				mar. 24/03				mer. 25/03				jeu. 26/03			
	03h	09h	15h	21h	03h	09h	15h	21h	03h	09h	15h	21h	03h	09h	15h	21h	03h	09h	15h	21h	03h	09h	15h	21h	03h	09h	15h	21h
Météo																												
Vent (km/h)	15	10	10	10	10	10	10	10	15	20	30	30	25	15	15	15	15	10	10	10	20	35	60	70	70	70	70	70
à 3000m																												
Vent (km/h)	10	5	10	5	5	5	10	5	5	10	25	25	15	10	15	10	10	10	10	5	5	15	50	55	50	40	50	60
à 2000m																												

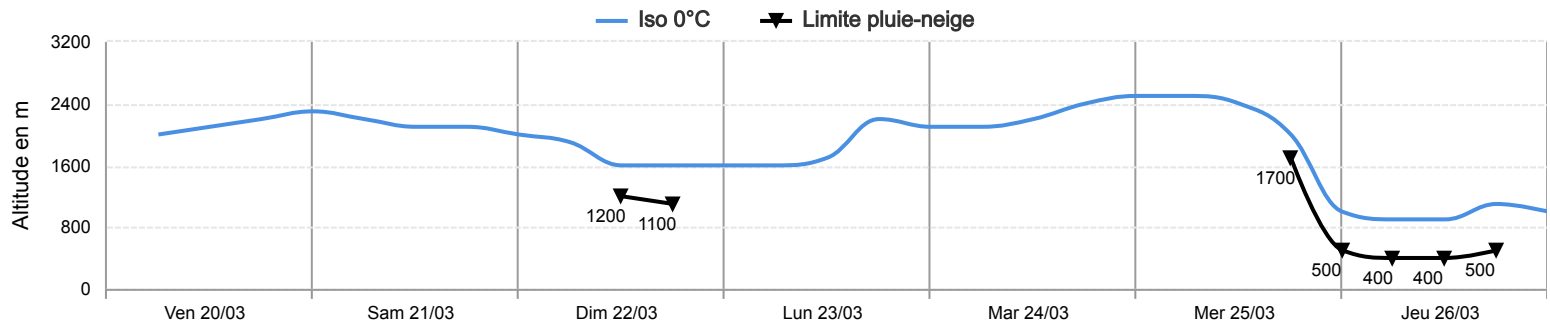

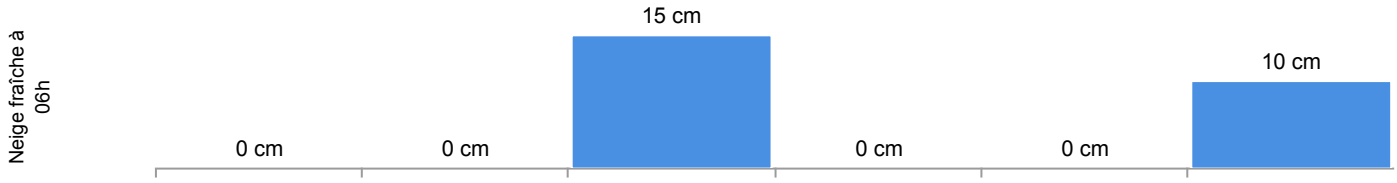

Risque d'avalanche	ven. 20/03	sam. 21/03	dim. 22/03	lun. 23/03	mar. 24/03	mer. 25/03	jeu. 26/03
	2	2	2	2	2	2	3

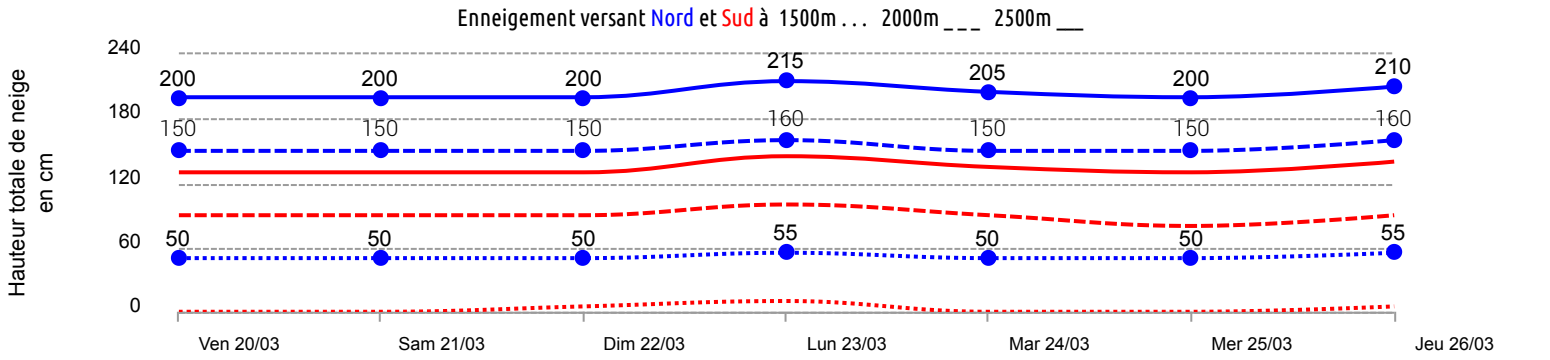

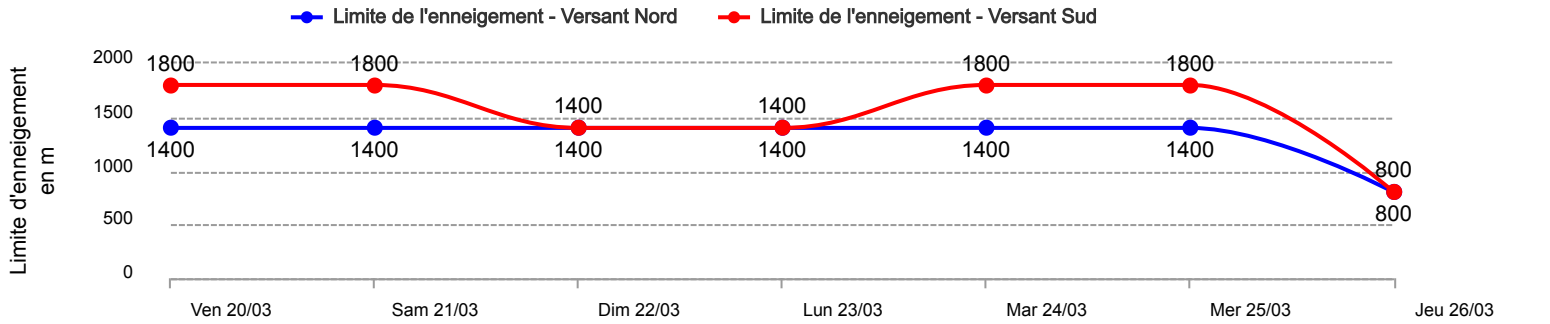

Pour consulter la vigilance en cours, veuillez vous rendre sur le site https://vigilance.meteofrance.fr/fr

Météo-France - 73 avenue de Paris, 94165 Saint-Mandé cedex - Contact : contact@meteo.fr

Bulletin neige & avalanches par téléphone au

0 892 68 10 20 Service 0,35 € / min + prix appel

Rédigé par Météo-France avec la contribution des observateurs du réseau nivo-météorologiques. Partenariat : ANMSM (Maires de Stations de Montagne), DSF (Domaines Skiables de France), ADSP (Directeurs de Pistes et de la Sécurité des Stations de Sports d'Hiver) et autres acteurs de la montagne.