Bulletin d'estimation du risque d'avalanche

(valable en dehors des pistes balisées et ouvertes)

MASSIF : Cinto Rotondo

Rédigé le jeudi 26 mars 2026 à 15h

Estimation des risques pour le : VENDREDI 27 MARS

INSTABILITÉS EN ALTITUDE DANS LA NEIGE FRAICHE VENTÉE

2

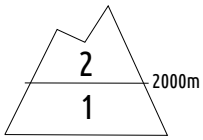

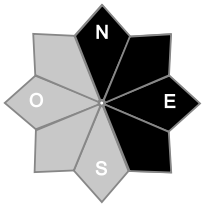

Au-dessus de 2000m indice de risque limité, plus bas indice faible.

Départs spontanés : rares coulées de neige fraîche

Déclenchements provoqués : plaques à vent difficilement sollicitables, encore présentes en altitude au-dessus de 2000 m

Indices de risque : 5 très fort - 4 fort - 3 marqué - 2 limité - 1 faible -- En noir : les pentes les plus dangereuses

Stabilité du manteau neigeux

Situation avalancheuse typique : neige ventée

Déclenchements provoqués : De nouvelles plaques se sont formées en altitude dans les pentes Nord à Est, au-dessus de 2000 m environ. Certaines instabilités peuvent céder au passage d'un skieur dans les pentes raides, souvent cachées sous une couche de neige fraîche. Elles peuvent engendrer des avalanches de taille petite à moyenne (taille 1 à 2). En dessous de 2000 m, la neige fraîche repose sur une sous-couche regelée et plus stable.
Départs spontanés : rares coulées, la couche de neige fraîche n'est pas suffisamment importante pour générer des départs spontanés.
Autres : Nombreuses surfaces dures et glacées, pouvant être recouvertes de quelques centimètres de neige fraîche.
Présence de corniches parfois volumineuses, dont certaines commencent à se détacher (apparition de fissures).

Qualité de la neige

Qualification de l'enneigement : L'enneigement est excellent pour la saison au-dessus de 1600 m. Sur la Maniccia, à 2400 m d'altitude dans le massif du Rotondo, on relève 3m17 de hauteur de neige totale.
Limite d'enneigement skiable : 1400 à 1500 m selon le versant.
État de la neige : Une fine couche de neige fraîche, localement de la neige roulée, recouvre le plus souvent des croûtes épaisses et les surfaces dures. A haute altitude, dans les pentes N à E, la neige reste froide et assez légère, ou bien densifiée ou durcie sur les zones qui ont été exposées au vent. À noter également la présence de corniches parfois volumineuses.

Aperçu météo pour le vendredi 27 mars

nuit	matin	après-midi	soir

Temps sec et peu nuageux. Persistance de l'air froid avec un vent modéré.

Pluie-Neige				
Iso 0 °C	1100 m	1100 m	1300 m	1300 m
Vent 1500 m	35 km/h	10 km/h	25 km/h	30 km/h
Vent 3000 m	50 km/h	40 km/h	35 km/h	50 km/h

Épaisseur de neige hors-piste

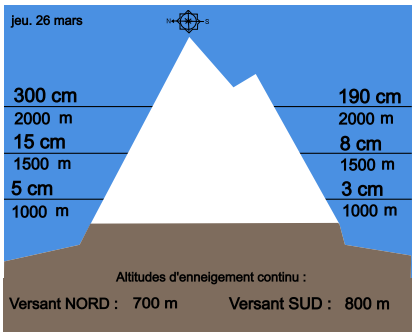

Précipitations à 1800 m

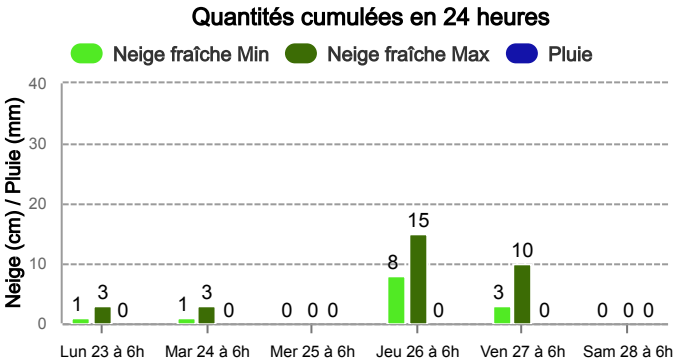

Tendance du samedi 28 mars

2

Indice de risque limité

Les températures demeurent froides avec un ciel clair. Maintien d'un risque limité.

Pour consulter la vigilance en cours, veuillez vous rendre sur le site https://vigilance.meteofrance.fr/fr

Météo-France - 73 avenue de Paris, 94165 Saint-Mandé cedex - Contact : contact@meteo.fr

Rédigé par Météo-France avec la contribution des observateurs du réseau nivo-météorologiques. Partenariat : ANMSM (Maires de Stations de Montagne), DSF (Domaines Skiables de France), ADSP (Directeurs de Pistes et de la Sécurité des Stations de Sports d'Hiver) et autres acteurs de la montagne.

Bulletin neige & avalanches par téléphone au
0 892 68 10 20 Service 0,35 € / min + prix appel

RÉPUBLIQUE FRANÇAISE
Liberté Égalité Fraternité

METEO FRANCE
À VOS CÔTÉS, DANS UN CLIMAT QUI CHANGE

Bulletin d'estimation du risque d'avalanche

(valable en dehors des pistes balisées et ouvertes)

MASSIF : Cinto Rotondo

Rédigé le jeudi 26 mars 2026 à 15h

Conditions nivo-météo des 7 derniers jours

	ven. 20/03				sam. 21/03				dim. 22/03				lun. 23/03				mar. 24/03				mer. 25/03				jeu. 26/03			
	03h	09h	15h	21h	03h	09h	15h	21h	03h	09h	15h	21h	03h	09h	15h	21h	03h	09h	15h	21h	03h	09h	15h	21h	03h	09h	15h	21h
Météo																												
Vent (km/h)	80	80	40	50	50	30	15	20	15	20	15	10	10	15	20	40	30	25	20	20	20	60	80	120	110	85	90	90
à 3000m																												
Vent (km/h)	30	30	25	25	25	15	10	10	5	10	5	5	5	10	15	30	5	10	10	10	10	30	50	80	85	60	60	60
à 1500m																												

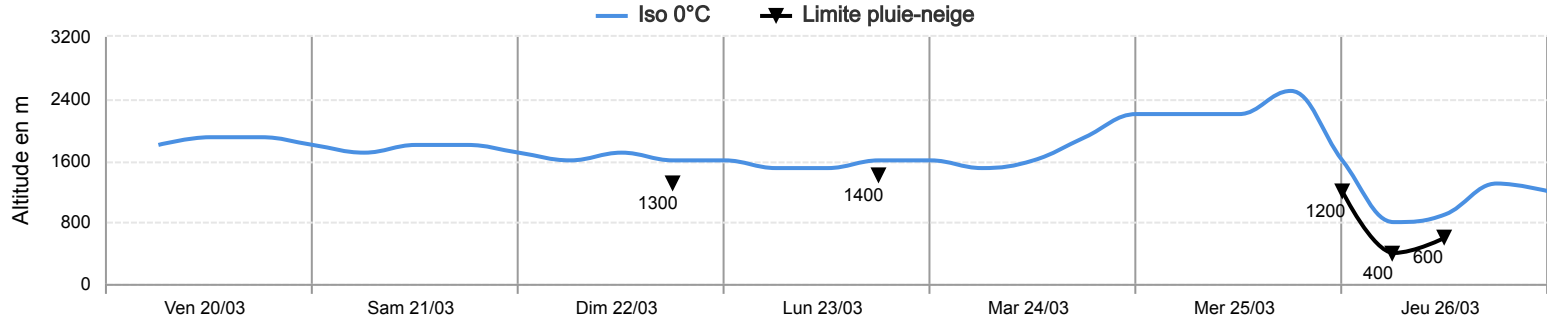

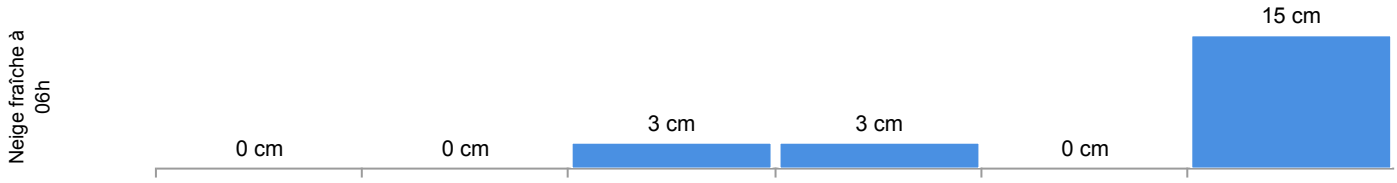

Risque d'avalanche							
	ven. 20/03	sam. 21/03	dim. 22/03	lun. 23/03	mar. 24/03	mer. 25/03	jeu. 26/03

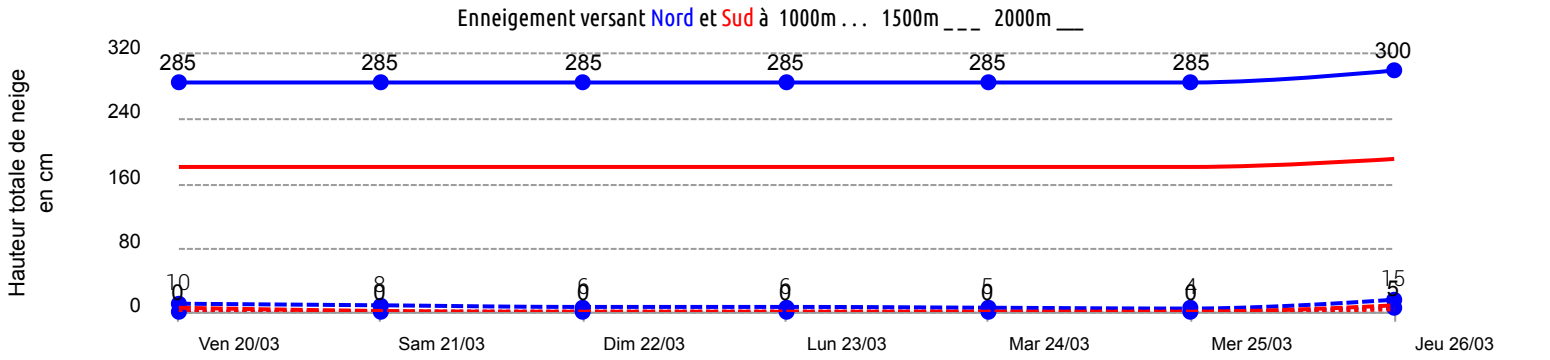

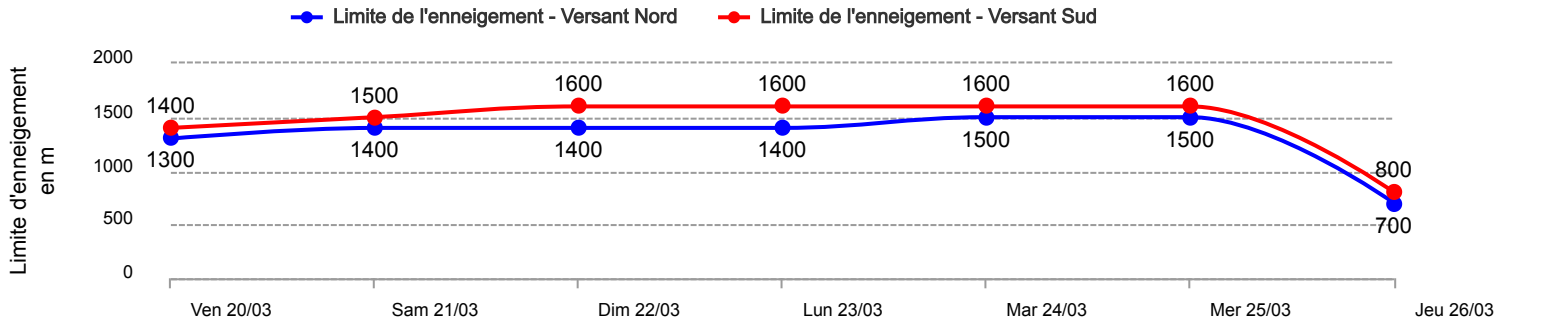

Pour consulter la vigilance en cours, veuillez vous rendre sur le site https://vigilance.meteofrance.fr/fr

Météo-France - 73 avenue de Paris, 94165 Saint-Mandé cedex - Contact : contact@meteo.fr

Rédigé par Météo-France avec la contribution des observateurs du réseau nivo-météorologiques. Partenariat : ANMSM (Maires de Stations de Montagne), DSF (Domaines Skiables de France), ADSP (Directeurs de Pistes et de la Sécurité des Stations de Sports d'Hiver) et autres acteurs de la montagne.

Bulletin neige & avalanches par téléphone au
0 892 68 10 20 Service 0,35 € / min + prix appel