Bulletin d'estimation du risque d'avalanche
(valable en dehors des pistes balisées et ouvertes)

MASSIF : Embrunais Parpaillon

Rédigé le jeudi 26 mars 2026 à 15h

Estimation des risques pour le : VENDREDI 27 MARS

INSTABILITÉS LOCALISÉES EN ALTITUDE

2

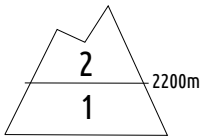

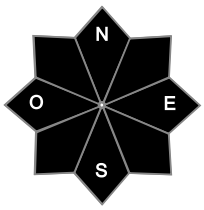

Au-dessus de 2200m indice de risque limité, plus bas indice faible.

Départs spontanés : rares et de petite taille sous l'effet du vent jeudi soir

Déclenchements provoqués : instabilités peu épaisses en altitude

Indices de risque : 5 très fort - 4 fort - 3 marqué - 2 limité - 1 faible -- En noir : les pentes les plus dangereuses

Stabilité du manteau neigeux

Situation avalancheuse typique : neige ventée

Déclenchements provoqués : instabilités disséminées en altitude, au-dessus de 2000 m. Possibles en toute orientation, même loin des crêtes, elles sont déclenchables par un seul skieur mais génèrent des avalanches de taille petite à moyenne (taille 1 à 2). Ces instabilités formées sous l'effet du fort vent de nord jeudi sont généralement d'aspect dur, localement épaisses mais restent peu larges.
Sous 2000 m d'altitude environ, instabilités rares et restant minces, disparaissant en cours de journée grâce au net redoux.

Départs spontanés : avalanche de petite taille encore possible jeudi soir dans les secteurs de plus forte accumulation par le vent à haute altitude. Peu probables vendredi en journée.

Qualité de la neige

L'enneigement est proche des normales pour une fin mars.
Hauteurs de neige observées : 108 cm à la nivôse du Parpaillon à 2500 m.

Limite d'enneigement skiable : au plus bas à 1400/1500 m en ubacs bien protégés ou sur pistes forestières, plutôt 2000/2100 m en adrets.

État de la neige de surface : neige fortement travaillée par le vent, crêtes parfois décapées.En journée, humidification en surface jusque 2200/2400 m environ.

Aperçu météo pour le vendredi 27 mars

	nuit	matin	après-midi	soir

Rapidement peu venté. Net redoux en altitude, max +2/+4°C à 2000 m, -2/-4 à 3000 m.

Pluie-Neige				
Iso 0 °C	1 100 m	1 400 m	1 700 m	1 900 m
Vent 2000 m	↓ 45 km/h	↓ 40 km/h	→ 20 km/h	↓ 10 km/h
Vent 3000 m	↓ 50 km/h	↙ 40 km/h	↙ 30 km/h	↙ 10 km/h

Épaisseur de neige hors-piste

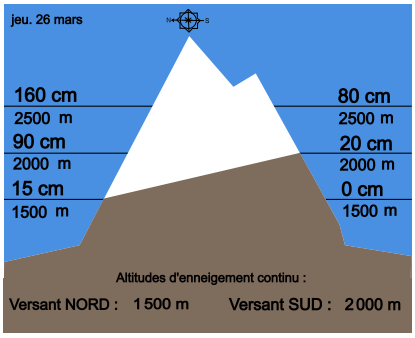

Précipitations à 1800 m

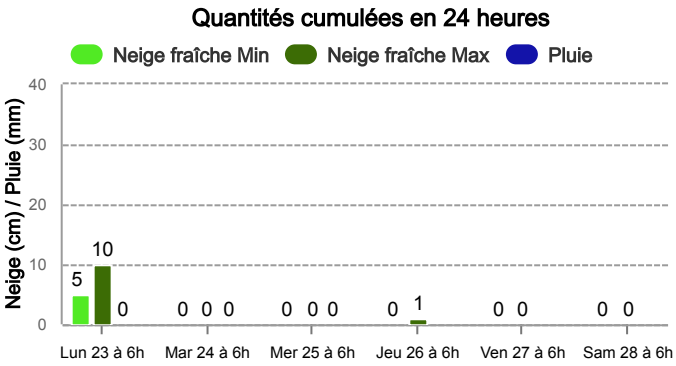

Tendance du samedi 28 mars

2

Indice de risque limité

Risque en lente baisse. Risque limité en altitude.

Pour consulter la vigilance en cours, veuillez vous rendre sur le site https://vigilance.meteofrance.fr/fr

Météo-France - 73 avenue de Paris, 94165 Saint-Mandé cedex - Contact : contact@meteo.fr

Rédigé par Météo-France avec la contribution des observateurs du réseau nivo-météorologiques. Partenariat : ANMSM (Maires de Stations de Montagne), DSF (Domaines Skiables de France), ADSP (Directeurs de Pistes et de la Sécurité des Stations de Sports d'Hiver) et autres acteurs de la montagne.

Bulletin neige & avalanches par téléphone au
0 892 68 10 20 Service 0,35 € / min + prix appel

RÉPUBLIQUE FRANÇAISE
Liberté Égalité Fraternité

METEO FRANCE
À VOS CÔTÉS, DANS UN CLIMAT QUI CHANGE

Bulletin d'estimation du risque d'avalanche
(valable en dehors des pistes balisées et ouvertes)
MASSIF : Embrunais Parpaillon

Rédigé le jeudi 26 mars 2026 à 15h

Conditions nivo-météo des 7 derniers jours

	ven. 20/03				sam. 21/03				dim. 22/03				lun. 23/03				mar. 24/03				mer. 25/03				jeu. 26/03			
	03h	09h	15h	21h	03h	09h	15h	21h	03h	09h	15h	21h	03h	09h	15h	21h	03h	09h	15h	21h	03h	09h	15h	21h	03h	09h	15h	21h
Météo																												
Vent (km/h)	25	20	15	10	15	10	10	5	15	25	30	30	25	25	25	30	25	15	15	15	30	50	60	70	30	60	70	70
à 3000m																												
Vent (km/h)	10	10	15	5	5	10	10	10	15	20	25	25	15	15	15	10	10	10	20	5	10	15	50	30	20	50	60	50
à 2000m																												

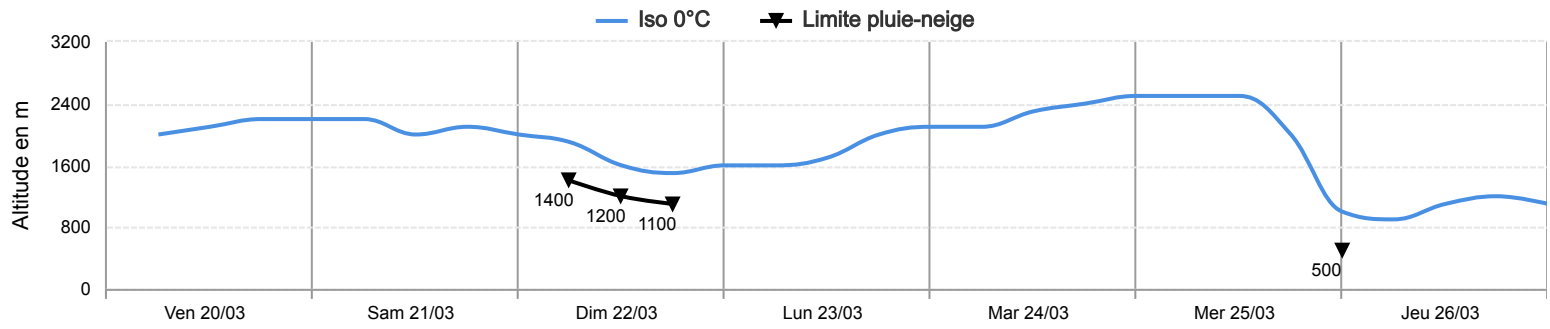

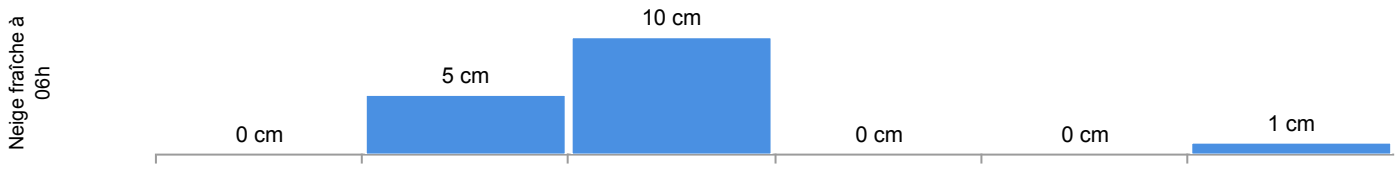

Risque d'avalanche	ven. 20/03	sam. 21/03	dim. 22/03	lun. 23/03	mar. 24/03	mer. 25/03	jeu. 26/03
	2	2	2	2	2	2	3

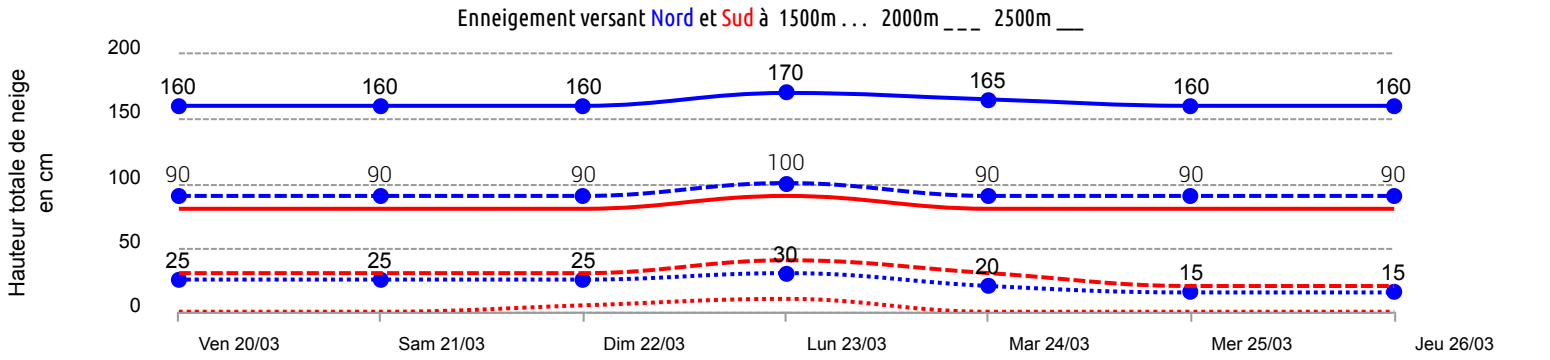

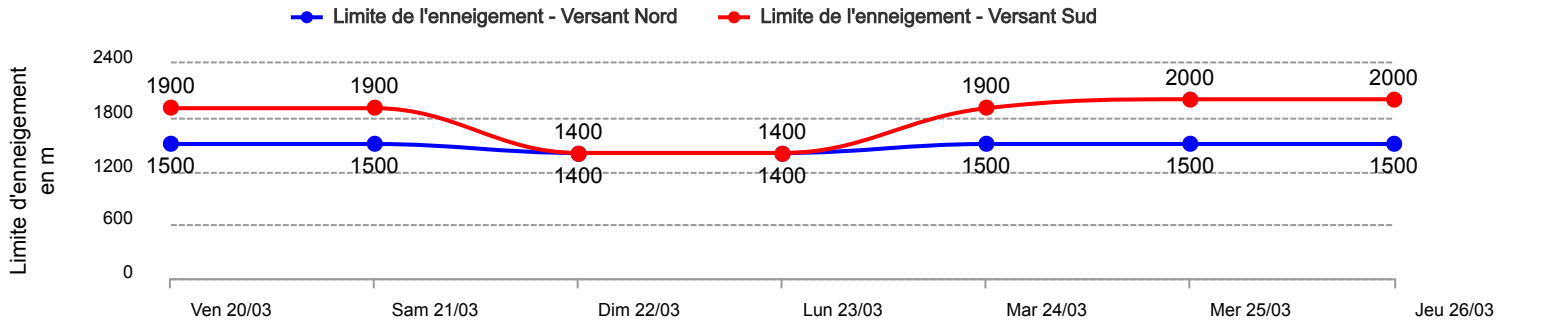

Pour consulter la vigilance en cours, veuillez vous rendre sur le site https://vigilance.meteofrance.fr/fr

Météo-France - 73 avenue de Paris, 94165 Saint-Mandé cedex - Contact : contact@meteo.fr

Rédigé par Météo-France avec la contribution des observateurs du réseau nivo-météorologiques. Partenariat : ANMSM (Maires de Stations de Montagne), DSF (Domaines Skiables de France), ADSP (Directeurs de Pistes et de la Sécurité des Stations de Sports d'Hiver) et autres acteurs de la montagne.

Bulletin neige & avalanches par téléphone au
0 892 68 10 20 Service 0,35 € / min + prix appel