Bulletin d'estimation du risque d'avalanche
(valable en dehors des pistes balisées et ouvertes)
MASSIF : Aspe Ossau

Rédigé le jeudi 26 mars 2026 à 16h

Estimation des risques pour le : VENDREDI 27 MARS

PLAQUES À VENT EN ALTITUDE DANS LA NEIGE RÉCENTE, FROID.

2

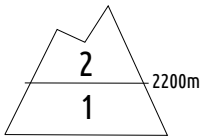

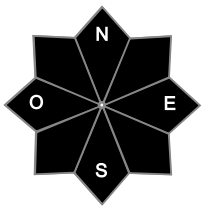

Plaques en altitude

Au-dessus de 2200m indice de risque limité, plus bas indice faible.

Départs spontanés : Départs ponctuels de plaques en altitude, sinon dans la neige récente.

Déclenchements provoqués : Plaques peu épaisses en altitude, couche fragile persistante.

Indices de risque : 5 très fort - 4 fort - 3 marqué - 2 limité - 1 faible -- En noir : les pentes les plus dangereuses

Stabilité du manteau neigeux

Situation avalancheuse typique : neige ventée couche fragile persistante

Déclenchements provoqués :
- **Au-dessus de 2000m**, quelques fines plaques à vent peuvent persister dans les pentes raides, issues des chutes de neige de la nuit de mercredi à jeudi ainsi que jeudi, accompagnées d'un vent fort de Nord. Leur déclenchement par un simple skieur peut engendrer de petites avalanches.
- **Au-dessus de 2200m**, dans les pentes raides allant principalement du Nord au Sud-Ouest, des plaques à vent sont présentes, issues des chutes de neige de la veille. Elles restent facilement déclenchables par un simple skieur. Elles se sont formées sur des plaques anciennes, reposant elles-mêmes sur une couche fragile persistante, situées dans les pentes Nord raides, puis au-dessus de 2400/2500m dans un secteur Nord à Nord-Est plus large. Des cassures linéaires de petites tailles sont attendues, parfois des moyennes, dans les zones d'accumulation les plus importantes, mais aussi par sollicitations plus importantes. Il n'est pas exclu de trouver de fines plaques à vent dans les pentes raides des secteur Ouest et Nord-Ouest, leur déclenchement engendrant de petites avalanches, parfois des moyennes dans les plus fortes accumulations.

Départs spontanés :
Au-dessus de 2000m, des départs ponctuels des plaques décrites ci-dessus restent possibles par surcharge par le vent, engendrant de petites avalanches. Des départs ponctuels des plaques décrites ci-dessus **au-dessus de 2200m** sont aussi possibles, par surcharge par le vent. Des avalanches de petites tailles sont possibles, parfois moyennes notamment dans les zones d'accumulations importantes.
Sinon, des départs ponctuels dans la neige récente restent possibles dans les pentes raides où se sont faites de petites accumulations, petites avalanches possibles.

Qualité de la neige

Enneigement : Correct pour la saison au-dessus de 2000m, mais restant assez maigre en versants exposés au vent d'ouest. Maigre et hétérogène plus bas, débutant entre 1500 et 1600m en Nord, mais skiable à partir de 1700m, plutôt 1800 à 1900m en Sud.
État de la neige : Quelques petits centimètres supplémentaires de neige au petit matin, venant se superposer à ceux de la veille. Cette neige récente vient reposer sur un manteau bien regelé, dur et glissant sous 2100m. La neige est bien travaillée par le vent en gagnant en altitude.

Aperçu météo pour le vendredi 27 mars

	nuit	matin	après-midi	soir

Rares flocons dès 800m le matin sous un relief bouché. Quelques éclaircies ensuite. Du vent fort sur les crêtes frontières de Nord à Nord-Est.

Pluie-Neige	800 m			
Iso 0 °C	1 000 m	1 500 m	1 700 m	1 500 m
Vent 1500 m	35 km/h	35 km/h	35 km/h	20 km/h
Vent 3000 m	75 km/h	60 km/h	50 km/h	30 km/h

Épaisseur de neige hors-piste

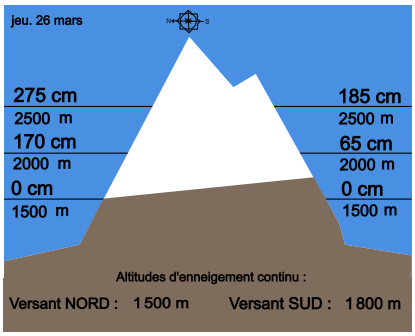

Précipitations à 1800 m

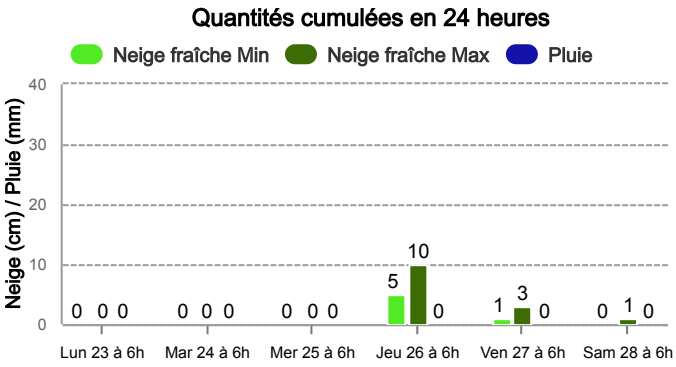

Tendance du samedi 28 mars

3

Indice de risque marqué

Risque en augmentation au fil de la journée (évolution vers un risque marqué) avec de nouvelles chutes de neige à venir dès samedi après-midi accompagnées de vent fort de Nord à Nord-Ouest.

Pour consulter la vigilance en cours, veuillez vous rendre sur le site https://vigilance.meteofrance.fr/fr

Météo-France - 73 avenue de Paris, 94165 Saint-Mandé cedex - Contact : contact@meteo.fr

Rédigé par Météo-France avec la contribution des observateurs du réseau nivo-météorologiques. Partenariat : ANMSM (Maires de Stations de Montagne), DSF (Domaines Skiables de France), ADSP (Directeurs de Pistes et de la Sécurité des Stations de Sports d'Hiver) et autres acteurs de la montagne.

Bulletin neige & avalanches par téléphone au
0 892 68 10 20 Service 0,35 € / min + prix appel

RÉPUBLIQUE FRANÇAISE
Liberté Égalité Fraternité

METEO FRANCE
À VOS CÔTÉS, DANS UN CLIMAT QUI CHANGE

Bulletin d'estimation du risque d'avalanche

(valable en dehors des pistes balisées et ouvertes)

MASSIF : Aspe Ossau

Rédigé le jeudi 26 mars 2026 à 16h

Conditions nivo-météo des 7 derniers jours

	ven. 20/03				sam. 21/03				dim. 22/03				lun. 23/03				mar. 24/03				mer. 25/03				jeu. 26/03			
	03h	09h	15h	21h	03h	09h	15h	21h	03h	09h	15h	21h	03h	09h	15h	21h	03h	09h	15h	21h	03h	09h	15h	21h	03h	09h	15h	21h
Météo																												
Vent (km/h)	15	15	20	15	15	10	10	15	5	10	25	35	35	25	20	15	10	10	20	60	70	70	75	80	90	80	75	80
à 3000m																												
Vent (km/h)	10	10	15	10	10	5	5	5	5	5	20	25	20	15	15	10	5	5	10	10	10	20	25	25	35	40	35	45
à 1500m																												

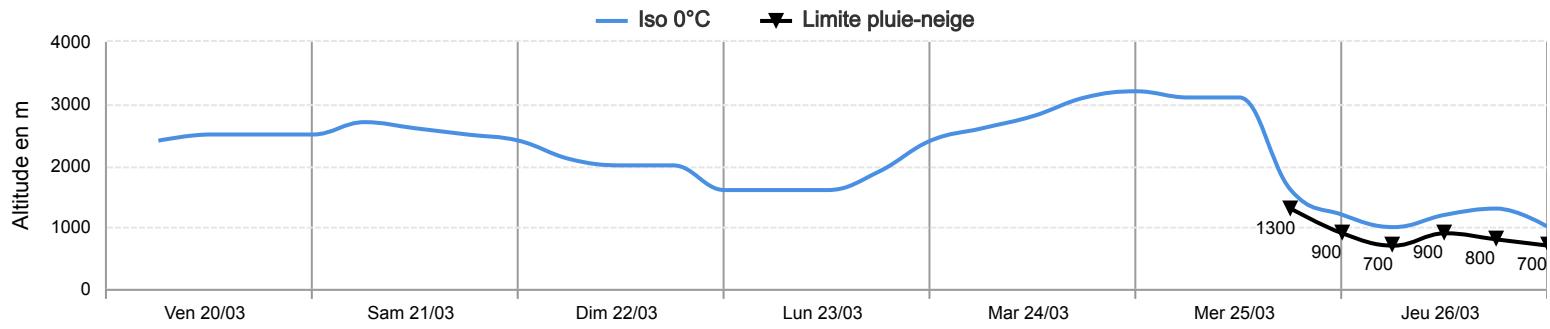

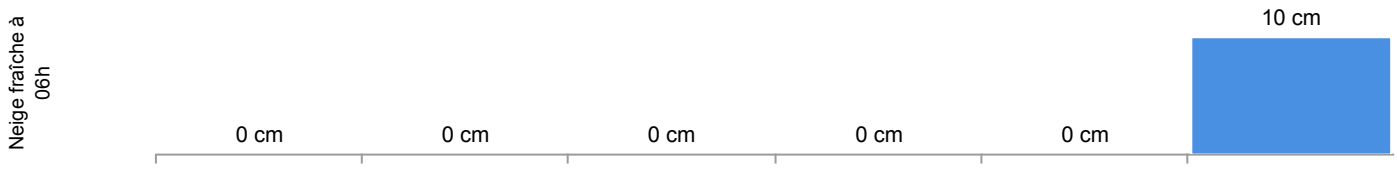

Risque d'avalanche	ven. 20/03	sam. 21/03	dim. 22/03	lun. 23/03	mar. 24/03	mer. 25/03	jeu. 26/03
	2	2	2	2	2	2	2

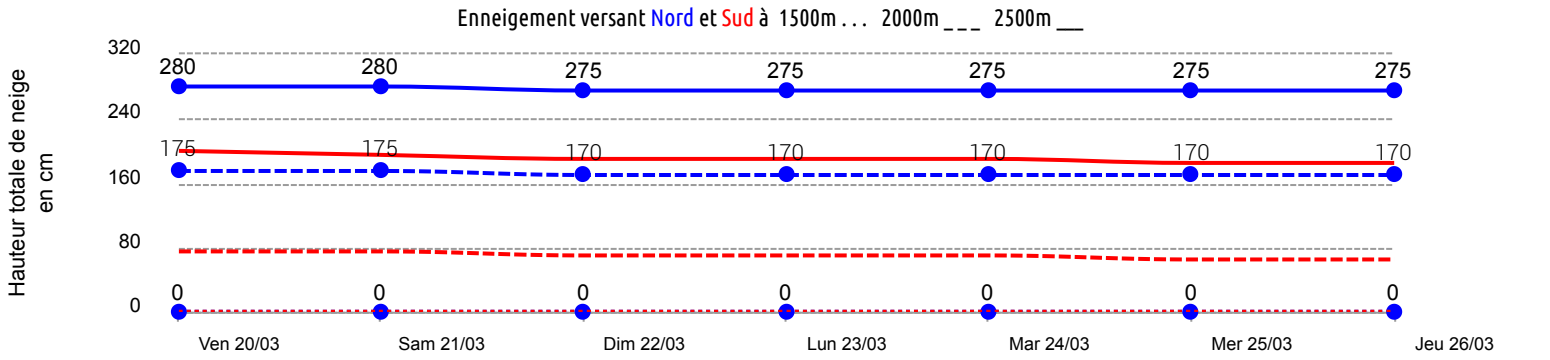

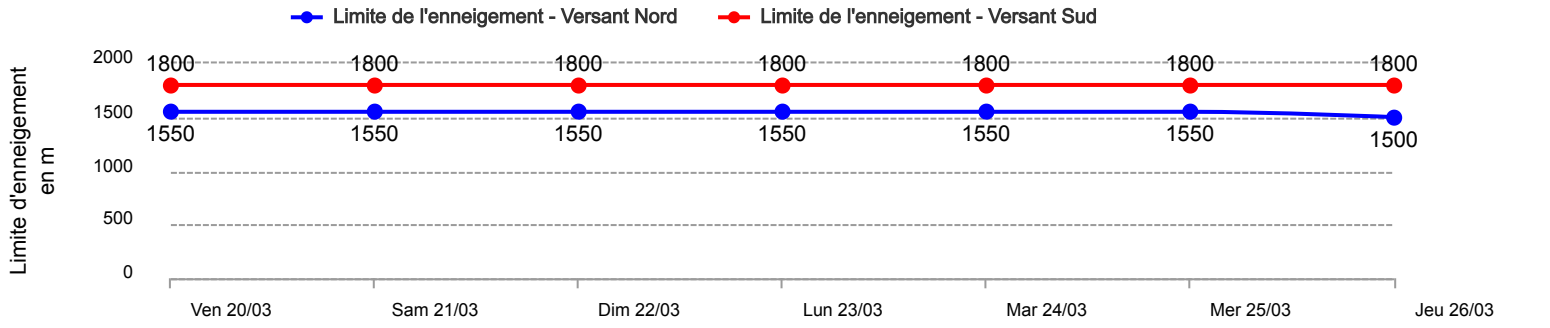

Pour consulter la vigilance en cours, veuillez vous rendre sur le site https://vigilance.meteofrance.fr/fr

Météo-France - 73 avenue de Paris, 94165 Saint-Mandé cedex - Contact : contact@meteo.fr

Rédigé par Météo-France avec la contribution des observateurs du réseau nivo-météorologiques. Partenariat : ANMSM (Maires de Stations de Montagne), DSF (Domaines Skiables de France), ADSP (Directeurs de Pistes et de la Sécurité des Stations de Sports d'Hiver) et autres acteurs de la montagne.

Bulletin neige & avalanches par téléphone au
0 892 68 10 20 Service 0,35 € / min + prix appel