Bulletin d'estimation du risque d'avalanche

(valable en dehors des pistes balisées et ouvertes)

MASSIF : Belledonne

Rédigé le jeudi 26 mars 2026 à 16h

Estimation des risques pour le : VENDREDI 27 MARS

NOMBREUSES PLAQUES SUITE AUX CHUTES DE NEIGE RECENTES FORTEMENT VENTEES

3

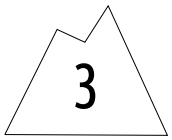

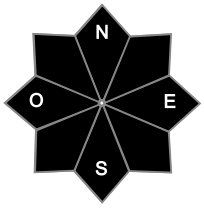

Indice de risque marqué.

Départs spontanés : Quelques ruptures de plaques sous le vent de Nord en journée. L'après-midi, rares coulées humides sous les rochers.

Déclenchements provoqués : Nombreuses plaques en neige ventée.

Indices de risque : 5 très fort - 4 fort - 3 marqué - 2 limité - 1 faible -- En noir : les pentes les plus dangereuses

Stabilité du manteau neigeux

Situation avalancheuse typique : neige ventée neige humide

Depuis mercredi soir, les chutes de neige ont été abondantes, avec 20 à 50cm de neige fraîche, voire plus de 60cm sur le Nord du massif. Le vent tempétueux a toutefois fortement travaillé le manteau, avec alternance de zones dégarnies et zones d'accumulation.

Déclenchements provoqués : De nombreuses plaques se sont formées et se forment encore en journée sous l'effet du vent. Elles se retrouvent en tout versant, mais peuvent être de plus grandes ampleurs en versants Est et Sud, qui sont généralement plus chargés (notamment secteur Belle Etoile / Cabottes / vallée des Villards / Allemond où les cumuls sont les plus importants). Les plaques se retrouvent souvent loin des crêtes, jusqu'en bas de pentes (les croûpes et sommets sont souvent dégarnis). Elles sont d'aspect variables, souvent en neige ferme / dure, parfois en neige plus poudreuse en secteurs abrités. Dans les secteurs où le vent tombe, le manteau se stabilise assez rapidement au soleil.

Observables : Transport en cours, zones d'accumulations, fissures devant les skis, test du bâton éventuellement (neige soufflée en surface, reposant sur une neige plus meuble).

Déclenchements spontanés : Principalement en versants Sud d'altitude, quelques ruptures de plaques (de tailles petites à moyennes en général) sont possibles dans les pentes chargées par le vent. Le risque diminue l'après-midi avec l'affaiblissement du vent. Le retour du soleil engendre des coulées dans les pentes raides ayant trop chauffées, sous les rôchers / corniches, plutôt en fin de journée, donc dans les pentes Sud à Ouest.

Qualité de la neige

Qualification de l'enneigement : L'enneigement est bon à basse altitude, et même excellent dés 1800 / 2000m. Peu de sous couche sous 1700m en plein Sud.

Limites skiables : Vers 1000 / 1200m, avec prudence en Sud / sous les sapins

Qualité de la neige vendredi : Manteau très hétérogène. La neige récente a été fortement travaillée par le vent, de qualité irrégulière / souvent cartonnée. Certains secteurs ont été totalement dégarnis et on ski sur la vieille croûte de regel. On peut toutefois retrouver des secteurs en neige poudreuse agréable, notamment en bas de pentes / dans les arbres (souvent en neige roulée).

Aperçu météo pour le vendredi 27 mars

	nuit	matin	après-midi	soir

Vent de Nord encore soutenu en matinée, se calmant l'après-midi. Retour d'éclaircies en journée, mais globalement encore assez nuageux.

Pluie-Neige	400 m			
Iso 0 °C	800 m	900 m	1 300 m	1 200 m
Vent 2000 m	↓ 55 km/h	↓ 50 km/h	↓ 40 km/h	← 15 km/h
Vent 3000 m	↓ 90 km/h	↓ 70 km/h	↙ 35 km/h	↙ 25 km/h

Épaisseur de neige hors-piste

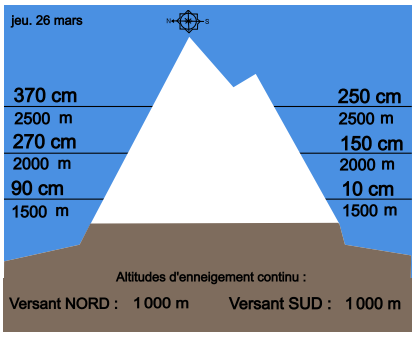

Précipitations à 1800 m

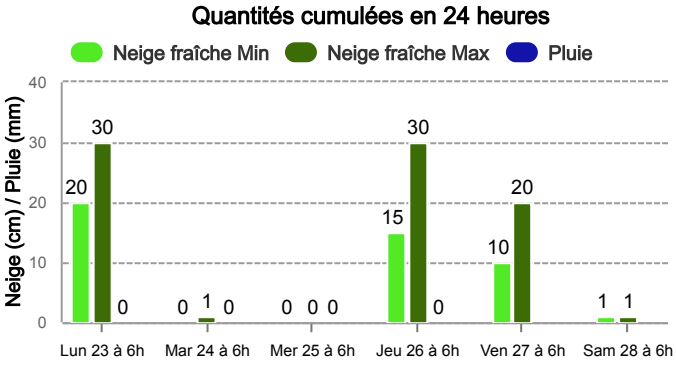

Tendance du samedi 28 mars

Indice de risque limité

Samedi, le vent faiblit nettement et la matinée est bien ensoleillée, avant le retour de nuages en journée. Le manteau se stabilise rapidement au soleil, plus lentement dans les ubacs.

Pour consulter la vigilance en cours, veuillez vous rendre sur le site https://vigilance.meteofrance.fr/fr

Météo-France - 73 avenue de Paris, 94165 Saint-Mandé cedex - Contact : contact@meteo.fr

Rédigé par Météo-France avec la contribution des observateurs du réseau nivo-météorologiques. Partenariat : ANMSM (Maires de Stations de Montagne), DSF (Domaines Skiables de France), ADSP (Directeurs de Pistes et de la Sécurité des Stations de Sports d'Hiver) et autres acteurs de la montagne.

Bulletin neige & avalanches par téléphone au

0 892 68 10 20 Service 0,35 € / min + prix appel

RÉPUBLIQUE FRANÇAISE
Liberté Égalité Fraternité

METEO FRANCE
À VOS CÔTÉS, DANS UN CLIMAT QUI CHANGE

Bulletin d'estimation du risque d'avalanche

(valable en dehors des pistes balisées et ouvertes)

MASSIF : Belledonne

Rédigé le jeudi 26 mars 2026 à 16h

Conditions nivo-météo des 7 derniers jours

	ven. 20/03				sam. 21/03				dim. 22/03				lun. 23/03				mar. 24/03				mer. 25/03				jeu. 26/03			
	03h	09h	15h	21h	03h	09h	15h	21h	03h	09h	15h	21h	03h	09h	15h	21h	03h	09h	15h	21h	03h	09h	15h	21h	03h	09h	15h	21h
Météo																												
Vent (km/h)	25	25	15	10	15	25	25	15	15	15	15	15	20	30	25	25	20	25	15	15	25	55	80	100	95	90	80	80
à 3000m																												
Vent (km/h)	10	10	5	5	10	15	10	5	15	10	20	15	15	20	15	15	15	10	10	10	10	30	55	70	65	60	65	60
à 2000m																												

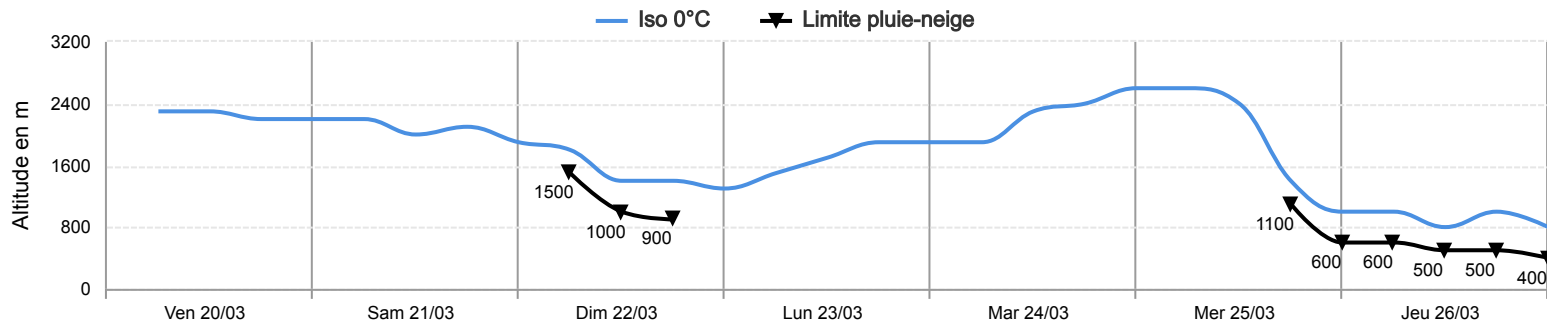

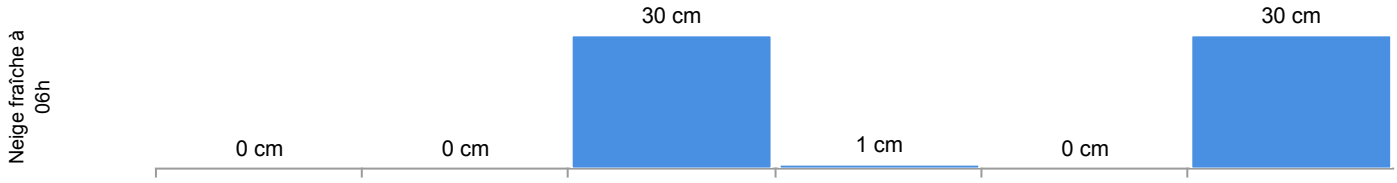

Risque d'avalanche	ven. 20/03	sam. 21/03	dim. 22/03	lun. 23/03	mar. 24/03	mer. 25/03	jeu. 26/03
	2	2	2	2	2	3	4

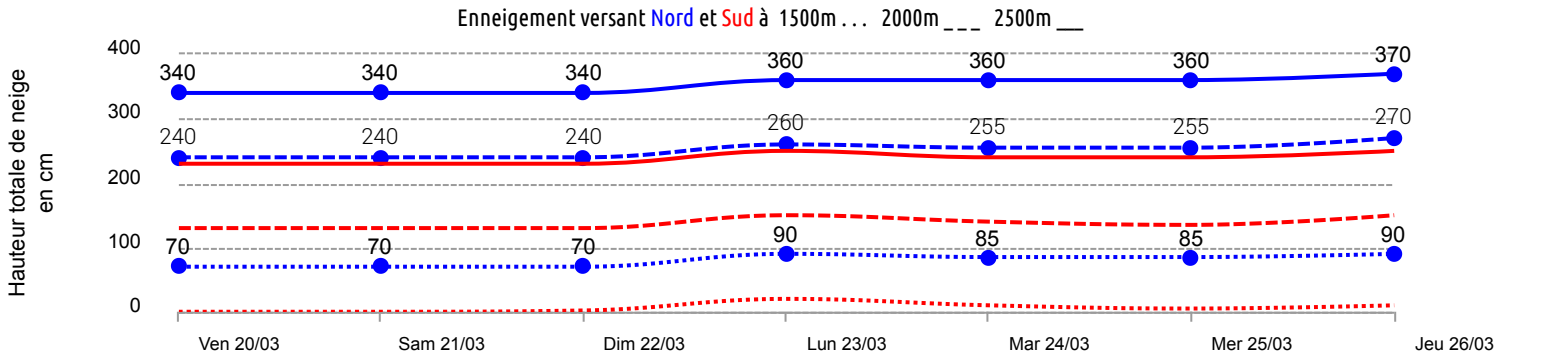

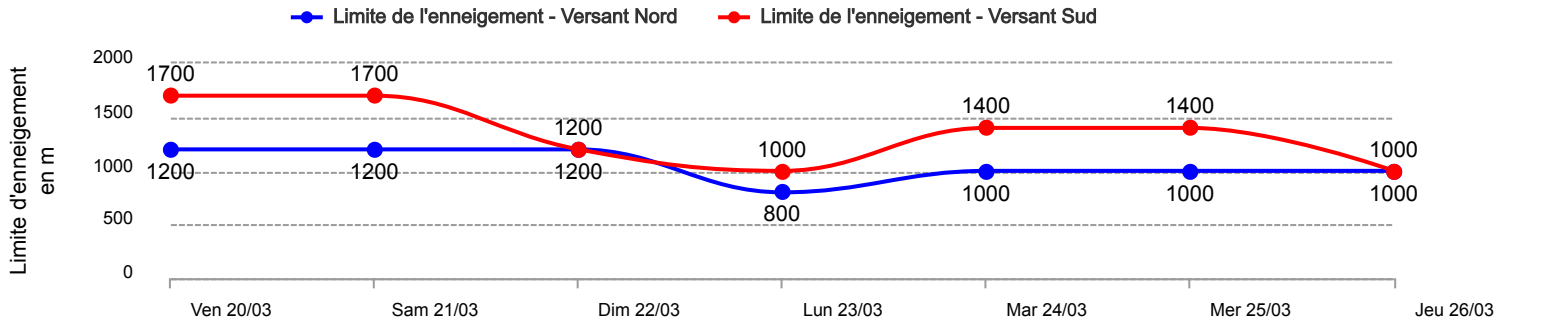

Pour consulter la vigilance en cours, veuillez vous rendre sur le site https://vigilance.meteofrance.fr/fr

Météo-France - 73 avenue de Paris, 94165 Saint-Mandé cedex - Contact : contact@meteo.fr

Rédigé par Météo-France avec la contribution des observateurs du réseau nivo-météorologiques. Partenariat : ANMSM (Maires de Stations de Montagne), DSF (Domaines Skiables de France), ADSP (Directeurs de Pistes et de la Sécurité des Stations de Sports d'Hiver) et autres acteurs de la montagne.

Bulletin neige & avalanches par téléphone au

0 892 68 10 20 Service 0,35 € / min + prix appel