RÉPUBLIQUE FRANÇAISE
Liberté Égalité Fraternité

METEO FRANCE
À VOS CÔTÉS, DANS UN CLIMAT QUI CHANGE

Bulletin d'estimation du risque d'avalanche
(valable en dehors des pistes balisées et ouvertes)
MASSIF : Capcir Puymorens

Rédigé le jeudi 26 mars 2026 à 16h

Estimation des risques pour le : VENDREDI 27 MARS

HIVERNAL, QUELQUES PLAQUES À VENT PLUS ÉPAISSES EN ALTITUDE.

2

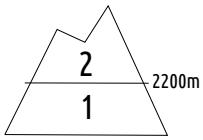

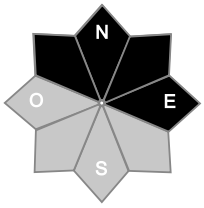

Au-dessus de 2200m indice de risque limité, plus bas indice faible.

Départs spontanés : Rares petits départs en neige récente dans des couloirs très raides.

Déclenchements provoqués : Anciennes plaques en versants nord sur sous couches fragiles persistantes et plaques peu épaisses en neige récente

Indices de risque : 5 très fort - 4 fort - 3 marqué - 2 limité - 1 faible -- En noir : les pentes les plus dangereuses

Stabilité du manteau neigeux

Situation avalancheuse typique : couche fragile persistante neige ventée

Déclenchements provoqués :
- Quelques structures de plaques remontant à plus d'une semaine sont possiblement présentes, au plus bas vers 2200/2300 m, mais surtout au-delà de 2400/2500 m, reposant sur des couches fragiles persistantes (givres de surface ou neige roulée).
Elles sont localisées dans les pentes sommitales des sommets frontaliers dans un large secteur nord et peuvent être masquées par les petites chutes de neige récente. Elles donnent des avalanches de taille 1 à 2, avec des cassures de 30/40 cm éventuellement possibles.
Observables : neige récente travaillée par le vent, enfoncement des bâtons supérieur à 20/30 cm, fissures devant les skis.
- Le vent associé aux petites chutes de neige récentes a déjà formé et va continuer de former quelques accumulations instables atteignant au maximum 15/20 cm par endroits. Déclenchables dans les pentes raides par un skieur elles donnent des avalanche de taille 1 (pouvant potentiellement entrainer un randonneur sur quelques mètres ou le faire glisser sur l'ancienne neige dure, sans l'ensevelir).

Départs spontanés :
Avec le net refroidissement effectif depuis jeudi, l'activité avalancheuse spontanée s'annonce faible. Tout au plus quelques petites avalanches ou coulées mobilisant les 10/15 cm de neige récente accumulés dans des couloirs très raides.

Autre :
Peu de neige fraîche sur un manteau neigeux regelé, dur et glissant sous 2200m.
Refroidissement éolien important.

Qualité de la neige

Enneigement :
L'enneigement est excellent pour la saison, après plusieurs hivers déficitaires.
En altitude, les cumuls sont très conséquents, mais les crêtes et sommets exposés au vent d'ouest à nord-ouest sont parfois complètement déneigés.
On peut encore chausser les skis dans les secteurs ombragés au mieux vers 1500/1600 m sur des pentes herbeuses.

Qualité de la neige :
Encore un peu de neige dans la nuit de jeudi à vendredi, quelques cm tout au plus, venant s'ajouter aux quelques cm de la veille. C'est une neige légère, pouvant être facilement balayée par le vent et s'accumuler contre les obstacles.
En surface, la neige récente reste froide, légère dans les secteurs protégés du vent. Neige très dure, voire glacée dans les secteurs balayés par le vent.

Aperçu météo pour le vendredi 27 mars

	nuit	matin	après-midi	soir
	hivernal avec vent de nord sensible			
Pluie-Neige	900 m			
Iso 0 °C	1 100 m	1 800 m	2 100 m	2 100 m
Vent 2000 m	↘ 75 km/h	↓ 75 km/h	↘ 65 km/h	↘ 60 km/h
Vent 3000 m	↘ 95 km/h	↓ 95 km/h	↓ 85 km/h	↘ 70 km/h

Pour consulter la vigilance en cours, veuillez vous rendre sur le site https://vigilance.meteofrance.fr/fr

Météo-France - 73 avenue de Paris, 94165 Saint-Mandé cedex - Contact : contact@meteo.fr

Rédigé par Météo-France avec la contribution des observateurs du réseau nivo-météorologiques. Partenariat : ANMSM (Maires de Stations de Montagne), DSF (Domaines Skiables de France), ADSP (Directeurs de Pistes et de la Sécurité des Stations de Sports d'Hiver) et autres acteurs de la montagne.

Bulletin neige & avalanches par téléphone au
0 892 68 10 20 Service 0,35 € / min + prix appel

RÉPUBLIQUE FRANÇAISE
Liberté Égalité Fraternité

METEO FRANCE
À VOS CÔTÉS, DANS UN CLIMAT QUI CHANGE

Bulletin d'estimation du risque d'avalanche

(valable en dehors des pistes balisées et ouvertes)

MASSIF : Capcir Puymorens

Rédigé le jeudi 26 mars 2026 à 16h

Épaisseur de neige hors-piste

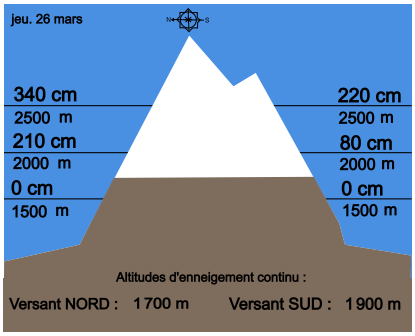

Précipitations à 1800 m

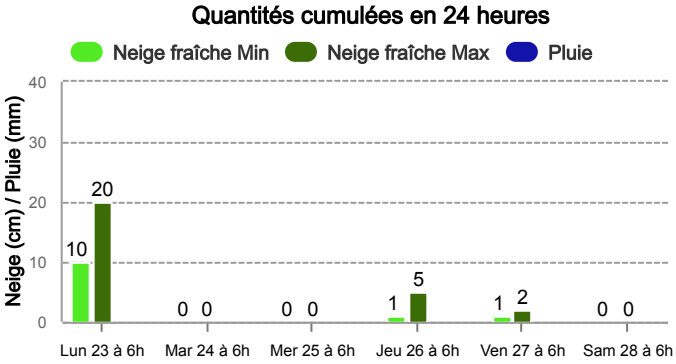

Tendance du samedi 28 mars

Indice de risque limité

Risque en augmentation avec de nouvelles précipitations ventées plus significatives qui débutent samedi après-midi.

Pour consulter la vigilance en cours, veuillez vous rendre sur le site https://vigilance.meteofrance.fr/fr

Météo-France - 73 avenue de Paris, 94165 Saint-Mandé cedex - Contact : contact@meteo.fr

Rédigé par Météo-France avec la contribution des observateurs du réseau nivo-météorologiques. Partenariat : ANMSM (Maires de Stations de Montagne), DSF (Domaines Skiables de France), ADSP (Directeurs de Pistes et de la Sécurité des Stations de Sports d'Hiver) et autres acteurs de la montagne.

Bulletin neige & avalanches par téléphone au

0 892 68 10 20 Service 0,35 € / min + prix appel

RÉPUBLIQUE FRANÇAISE
Liberté Égalité Fraternité

METEO FRANCE
À VOS CÔTÉS, DANS UN CLIMAT QUI CHANGE

Bulletin d'estimation du risque d'avalanche

(valable en dehors des pistes balisées et ouvertes)

MASSIF : Capcir Puymorens

Rédigé le jeudi 26 mars 2026 à 16h

Conditions nivo-météo des 7 derniers jours

	ven. 20/03				sam. 21/03				dim. 22/03				lun. 23/03				mar. 24/03				mer. 25/03				jeu. 26/03			
	03h	09h	15h	21h	03h	09h	15h	21h	03h	09h	15h	21h	03h	09h	15h	21h	03h	09h	15h	21h	03h	09h	15h	21h	03h	09h	15h	21h
Météo																												
Vent (km/h)	30	25	20	20	10	10	20	15	25	25	35	50	50	40	35	25	20	20	20	20	30	55	75	90	90	100	95	105
à 3000m																												
Vent (km/h)	15	10	10	5	5	5	15	10	15	20	35	35	35	35	30	20	15	10	10	10	15	35	50	70	75	80	80	85
à 2000m																												

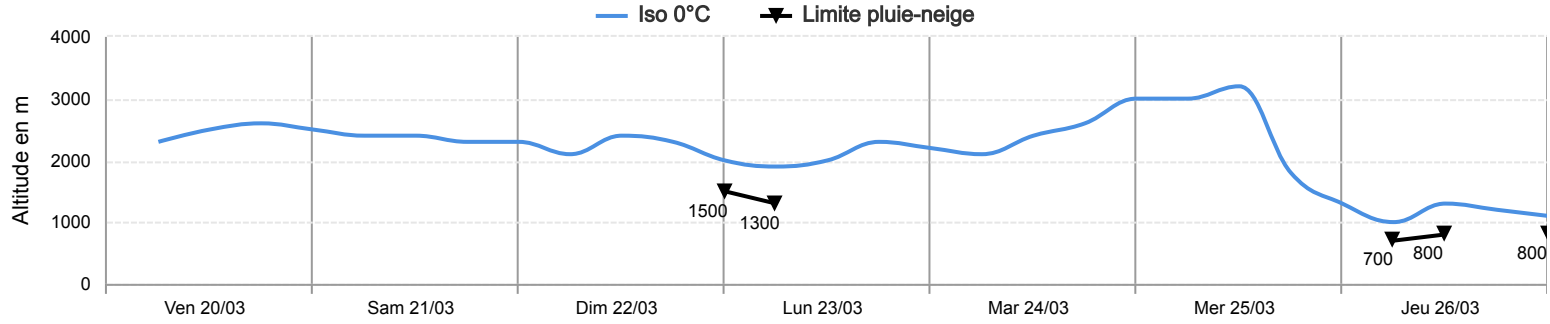

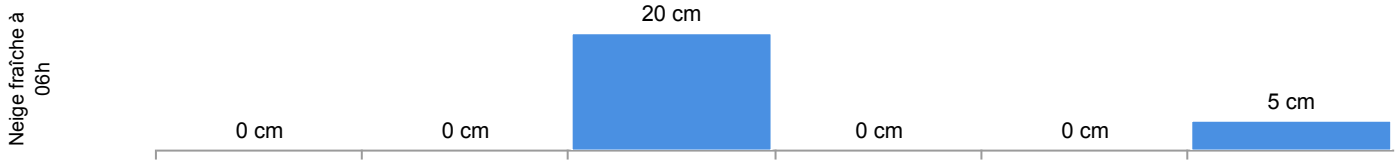

Risque d'avalanche	ven. 20/03	sam. 21/03	dim. 22/03	lun. 23/03	mar. 24/03	mer. 25/03	jeu. 26/03
	2	2	2	3	3	2	2

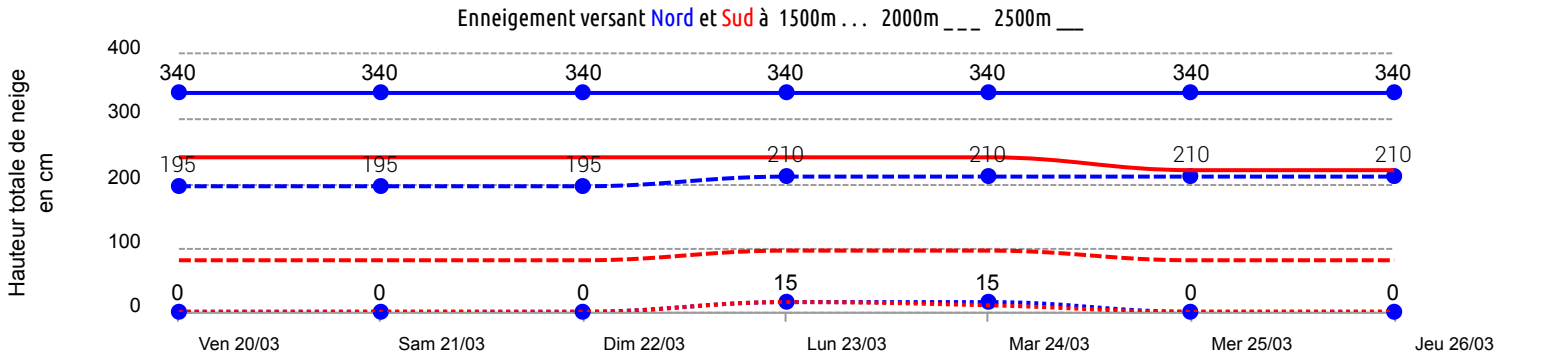

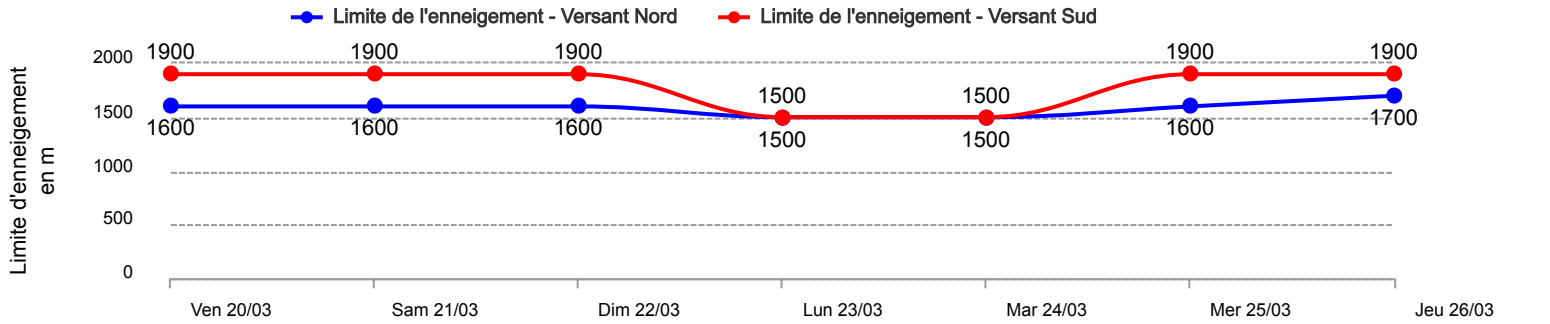

Pour consulter la vigilance en cours, veuillez vous rendre sur le site https://vigilance.meteofrance.fr/fr

Météo-France - 73 avenue de Paris, 94165 Saint-Mandé cedex - Contact : contact@meteo.fr

Bulletin neige & avalanches par téléphone au

0 892 68 10 20 Service 0,35 € / min + prix appel

Rédigé par Météo-France avec la contribution des observateurs du réseau nivo-météorologiques. Partenariat : ANMSM (Maires de Stations de Montagne), DSF (Domaines Skiables de France), ADSP (Directeurs de Pistes et de la Sécurité des Stations de Sports d'Hiver) et autres acteurs de la montagne.