Bulletin d'estimation du risque d'avalanche
(valable en dehors des pistes balisées et ouvertes)

MASSIF : Pays-Basque

Rédigé le jeudi 26 mars 2026 à 16h

Estimation des risques pour le : VENDREDI 27 MARS

PLAQUES À VENT EN ALTITUDE DANS LA NEIGE RÉCENTE, FROID.

2

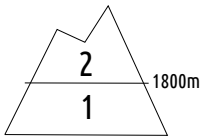

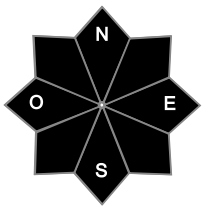

Plaques en altitude.

Au-dessus de 1800m indice de risque limité, plus bas indice faible.

Départs spontanés : Départs ponctuels de plaques en altitude, sinon dans la neige récente.

Déclenchements provoqués : Plaques peu épaisses en altitude.

Indices de risque : 5 très fort - 4 fort - 3 marqué - 2 limité - 1 faible -- En noir : les pentes les plus dangereuses

Stabilité du manteau neigeux

Situation avalancheuse typique : neige ventée

Déclenchements provoqués :
- **Au-dessus de 1800m**, quelques plaques à vent peu épaisses peuvent persister dans les pentes raides, issues des chutes de neige de la nuit de mercredi à jeudi ainsi que jeudi, accompagnées d'un vent fort de Nord. Elles restent facilement déclenchables par un simple skieur, et leur sollicitation peut engendrer de petites avalanches, parfois des moyennes dans les zones d'accumulations plus importantes. Ces plaques à vent peuvent être présentes en tous versants sous l'effet du vent fort de Nord à Nord-Est ce vendredi.
- **Sous 1800m**, la neige récente est plus ou moins travaillée par le vent. Un simple skieur peut engendrer de petites avalanches dans cette neige récente.

Départs spontanés :
- **Au-dessus de 1800m**, des départs ponctuels des plaques décrites ci-dessus restent possibles par surcharge par le vent, engendrant de petites avalanches, parfois des moyennes.
- **Sous 1800m**, des départs ponctuels dans la neige récente restent possibles dans les pentes raides où se sont faites de petites accumulations, petites avalanches possibles.

Qualité de la neige

Enneigement : Correct pour la saison au-dessus de 1800m, mais restant assez maigre en versants exposés au vent d'ouest. Maigre et hétérogène plus bas, débutant entre 1500 et 1600m en Nord, mais skiable à partir de 1700m, plutôt 1800 à 1900m en Sud.
État de la neige : Quelques petits centimètres supplémentaires de neige au petit matin, venant se superposer à ceux de la veille. Cette neige récente vient reposer sur un manteau bien regelé, dur et glissant. La neige est bien travaillée par le vent en gagnant en altitude.

Aperçu météo pour le vendredi 27 mars

	nuit	matin	après-midi	soir

Rares flocons dès 800m le matin sous un relief bouché. Quelques éclaircies ensuite. Du vent fort sur les crêtes frontières de Nord à Nord-Est.

Pluie-Neige	700 m			
Iso 0 °C	900 m	1 200 m	1 300 m	1 200 m
Vent 1000 m	↓ 35 km/h	↓ 35 km/h	↓ 35 km/h	↙ 25 km/h
Vent 2000 m	↓ 75 km/h	↙ 65 km/h	↓ 55 km/h	↙ 50 km/h

Épaisseur de neige hors-piste

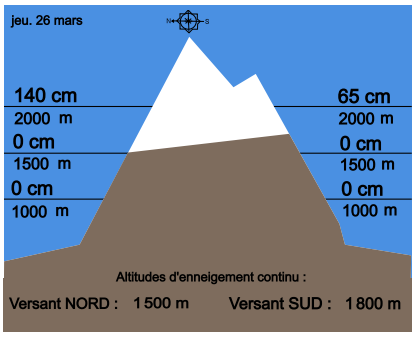

Précipitations à 1800 m

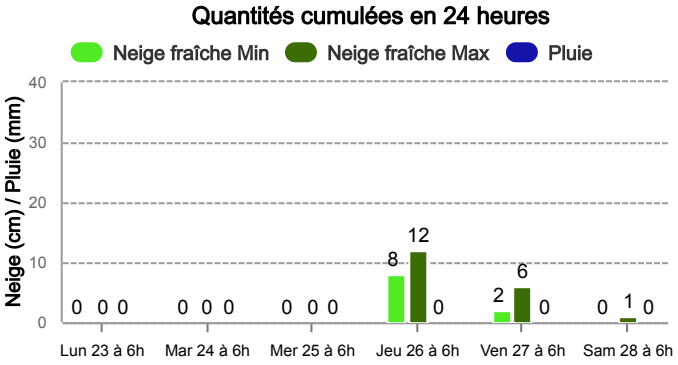

Tendance du samedi 28 mars

Indice de risque marqué

Risque en augmentation au fil de la journée (évolution vers un risque marqué) avec de nouvelles chutes de neige à venir dès samedi après-midi accompagnées de vent fort de Nord à Nord-Ouest.

Pour consulter la vigilance en cours, veuillez vous rendre sur le site https://vigilance.meteofrance.fr/fr

Météo-France - 73 avenue de Paris, 94165 Saint-Mandé cedex - Contact : contact@meteo.fr

Rédigé par Météo-France avec la contribution des observateurs du réseau nivo-météorologiques. Partenariat : ANMSM (Maires de Stations de Montagne), DSF (Domaines Skiables de France), ADSP (Directeurs de Pistes et de la Sécurité des Stations de Sports d'Hiver) et autres acteurs de la montagne.

Bulletin neige & avalanches par téléphone au
0 892 68 10 20 Service 0,35 € / min + prix appel

RÉPUBLIQUE FRANÇAISE
Liberté Égalité Fraternité

METEO FRANCE
À VOS CÔTÉS, DANS UN CLIMAT QUI CHANGE

Bulletin d'estimation du risque d'avalanche
(valable en dehors des pistes balisées et ouvertes)
MASSIF : Pays-Basque

Rédigé le jeudi 26 mars 2026 à 16h

Conditions nivo-météo des 7 derniers jours

	ven. 20/03				sam. 21/03				dim. 22/03				lun. 23/03				mar. 24/03				mer. 25/03				jeu. 26/03			
	03h	09h	15h	21h	03h	09h	15h	21h	03h	09h	15h	21h	03h	09h	15h	21h	03h	09h	15h	21h	03h	09h	15h	21h	03h	09h	15h	21h
Météo																												
Vent (km/h)	30	25	30	30	25	30	30	25	15	25	35	35	40	35	30	25	25	15	5	15	15	10	50	65	75	80	85	85
à 2000m																												
Vent (km/h)	15	10	10	10	10	10	15	10	5	15	30	25	25	25	25	15	10	10	2	5	5	2	15	25	35	40	50	50
à 1000m																												

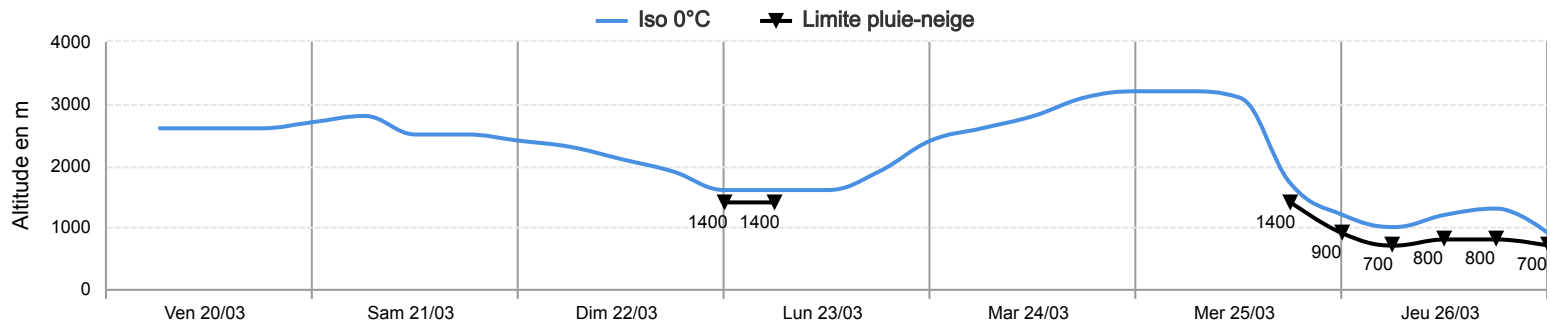

Risque d'avalanche	ven. 20/03	sam. 21/03	dim. 22/03	lun. 23/03	mar. 24/03	mer. 25/03	jeu. 26/03
	2	2	2	2	2	2	2

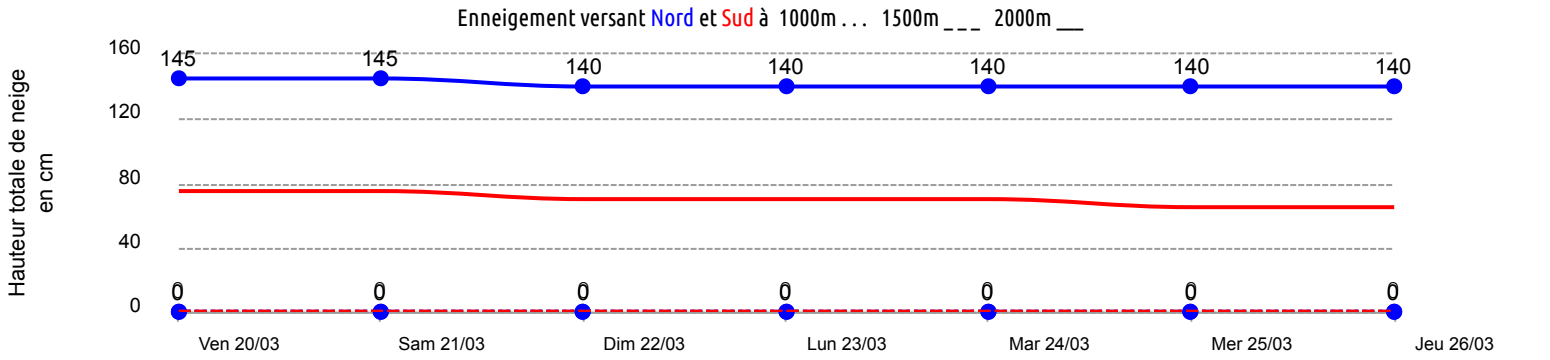

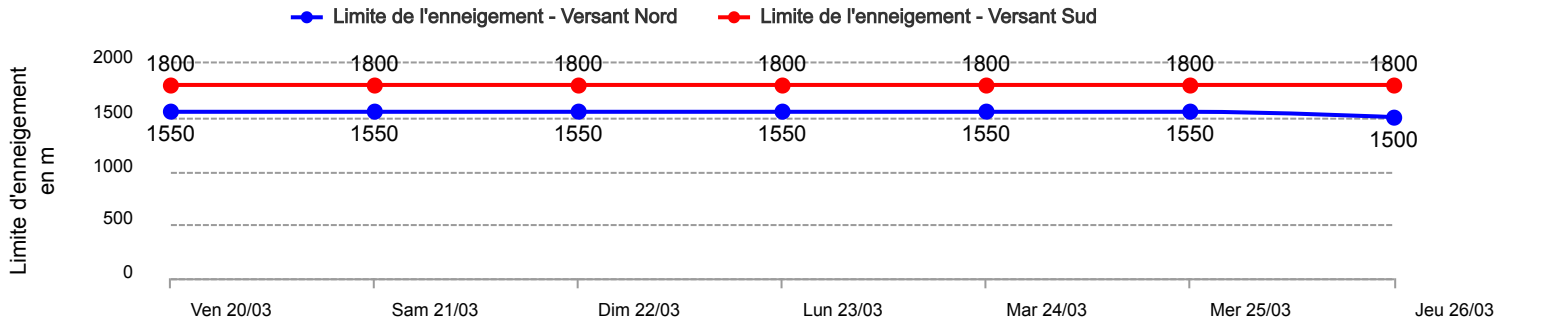

Pour consulter la vigilance en cours, veuillez vous rendre sur le site https://vigilance.meteofrance.fr/fr

Météo-France - 73 avenue de Paris, 94165 Saint-Mandé cedex - Contact : contact@meteo.fr

Rédigé par Météo-France avec la contribution des observateurs du réseau nivo-météorologiques. Partenariat : ANMSM (Maires de Stations de Montagne), DSF (Domaines Skiables de France), ADSP (Directeurs de Pistes et de la Sécurité des Stations de Sports d'Hiver) et autres acteurs de la montagne.

Bulletin neige & avalanches par téléphone au
0 892 68 10 20 Service 0,35 € / min + prix appel