Bulletin d'estimation du risque d'avalanche
(valable en dehors des pistes balisées et ouvertes)

MASSIF : Beaufortain

Rédigé le jeudi 26 mars 2026 à 17h

Estimation des risques pour le : VENDREDI 27 MARS

CONDITIONS HIVERNALES EN MONTAGNE. NOMBREUSES PLAQUES POUDREUSES.

3

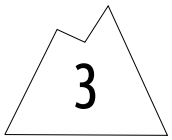

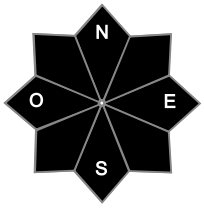

Loin des crêtes

Indice de risque marqué.

Départs spontanés : possibles en journée.

Déclenchements provoqués : nombreuses plaques.

Indices de risque : 5 très fort - 4 fort - 3 marqué - 2 limité - 1 faible -- En noir : les pentes les plus dangereuses

Stabilité du manteau neigeux

Situation avalancheuse typique : neige fraîche neige ventée

Déclenchements provoqués : nombreuses plaques en place en tous versants et à toutes altitudes. Elles sont réactives au matin avec une tendance à la stabilisation au fil des heures. Elles engendrent des avalanches de taille 1 à 2 (petit à moyenne). D'aspect poudreux, leur identification visuelle n'est pas forcément possible. **Observables :** neige densifiée par le vent, fissures devant les skis, accumulation de neige fraîche.

Départs spontanés : la baisse du vent en matinée met fin au risque de départs naturels de plaques dans les zones d'accumulations sous le vent. Le retour du Soleil engendre des coulées dans les pentes raides ayant trop chauffées, au départ des rochers/des corniches, plutôt en fin de journée donc dans les pentes Sud à Ouest. Taille 1 à 2.

Qualité de la neige

Enneigement : Encore un peu au dessus de la moyenne, sauf aux plus basses altitudes où les hauteurs de neige sont tout juste correctes pour la saison.

Limite skiable : 1100 m au mieux en Nord. Plutôt 1400/1500 m en sud pas trop raide.

Qualité de la neige : 20 cm de neige fraîche à 1500 m, 30 à 50 cm au-dessus de 2000 m. La répartition est variable avec de belles accumulations possibles mais la neige reste dans l'ensemble poudreuse. La qualité se dégrade à l'approche des crêtes. D'ailleurs ces dernières, ainsi que les croupes exposées au vent sont « sèches » et laissent ressortir la vieille neige dure, la glace, les rochers…
En journée, les pentes très exposées au Soleil chauffent. La neige botte et devient lourde/collante après plusieurs heures d'ensoleillement. En haute montagne ensoleillée, le vent de Nord ralentie le réchauffement dans les pentes ensoleillées.

Aperçu météo pour le vendredi 27 mars

	nuit	matin	après-midi	soir
Conditions de plus en plus calmes au fil des heures.				
Pluie-Neige	400 m			
Iso 0 °C	800 m	900 m	1 500 m	1 300 m
Vent 2000 m	↘ 50 km/h	↘ 35 km/h	↘ 20 km/h	↙ 10 km/h
Vent 3000 m	↓ 60 km/h	↙ 50 km/h	↙ 30 km/h	↙ 20 km/h

Épaisseur de neige hors-piste

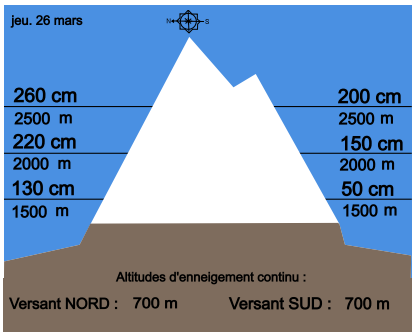

Précipitations à 1800 m

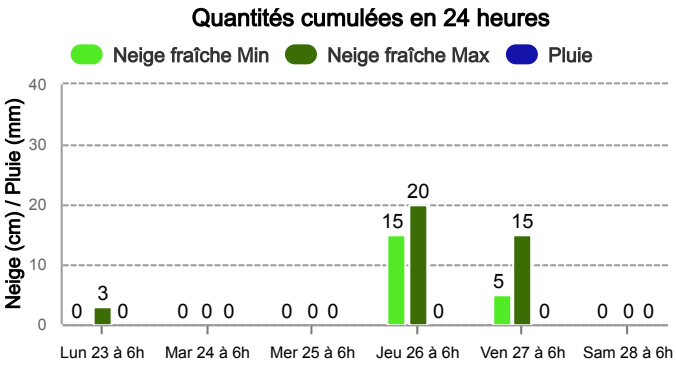

Tendance du samedi 28 mars

2

Indice de risque limité

Stabilisation rapide du manteau neigeux.

Pour consulter la vigilance en cours, veuillez vous rendre sur le site https://vigilance.meteofrance.fr/fr

Météo-France - 73 avenue de Paris, 94165 Saint-Mandé cedex - Contact : contact@meteo.fr

Rédigé par Météo-France avec la contribution des observateurs du réseau nivo-météorologiques. Partenariat : ANMSM (Maires de Stations de Montagne), DSF (Domaines Skiables de France), ADSP (Directeurs de Pistes et de la Sécurité des Stations de Sports d'Hiver) et autres acteurs de la montagne.

Bulletin neige & avalanches par téléphone au **0 892 68 10 20** Service 0,35 € / min + prix appel

Bulletin d'estimation du risque d'avalanche

(valable en dehors des pistes balisées et ouvertes)

MASSIF : Beaufortain

Rédigé le jeudi 26 mars 2026 à 17h

Conditions nivo-météo des 7 derniers jours

	ven. 20/03				sam. 21/03				dim. 22/03				lun. 23/03				mar. 24/03				mer. 25/03				jeu. 26/03			
	03h	09h	15h	21h	03h	09h	15h	21h	03h	09h	15h	21h	03h	09h	15h	21h	03h	09h	15h	21h	03h	09h	15h	21h	03h	09h	15h	21h
Météo																												
Vent (km/h)	25	25	15	10	15	25	20	15	15	25	20	10	20	25	20	20	20	25	35	40	50	60	80	80	75	65	70	65
à 3000m																												
Vent (km/h)	5	5	0	0	5	10	20	10	10	30	25	15	10	10	20	10	5	5	15	25	30	40	65	65	60	50	55	55
à 2000m																												

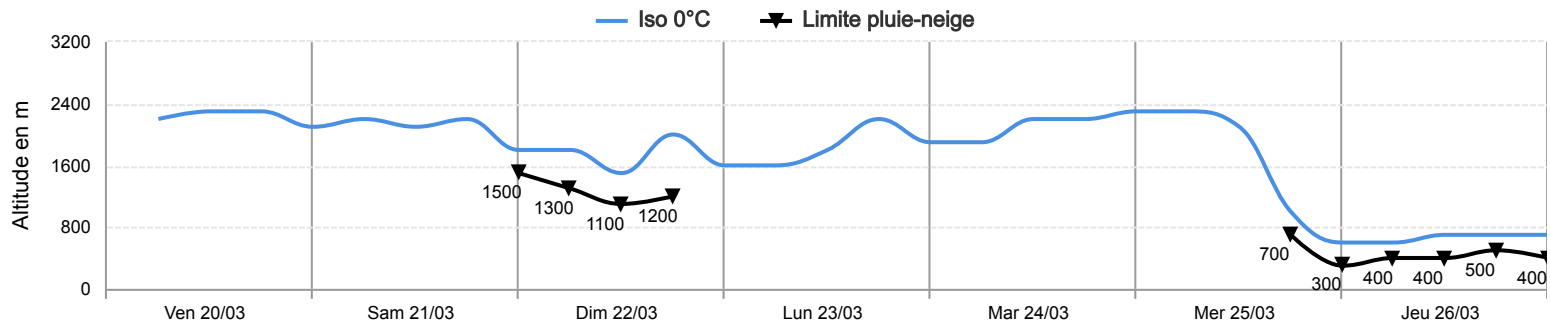

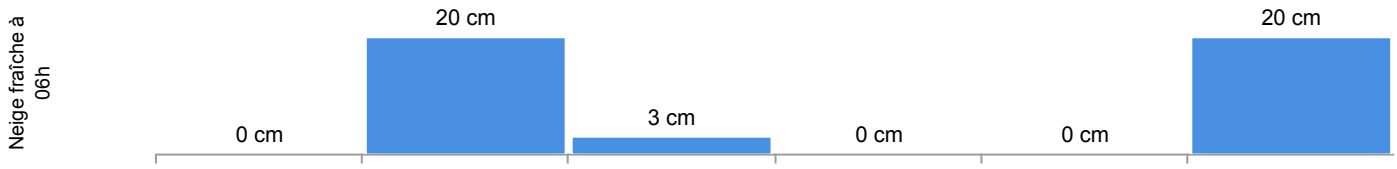

Risque d'avalanche	ven. 20/03	sam. 21/03	dim. 22/03	lun. 23/03	mar. 24/03	mer. 25/03	jeu. 26/03
	2	2	2	2	2	3	3

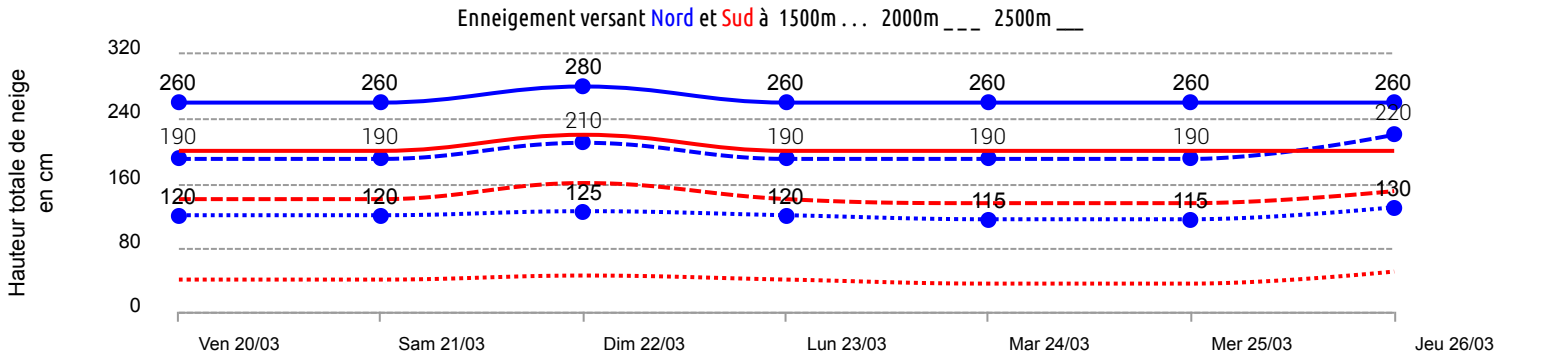

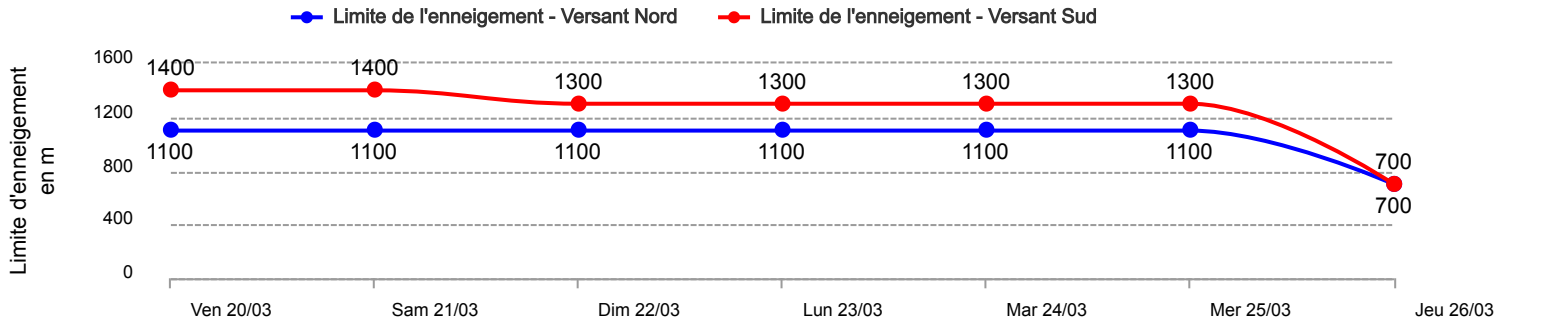

Pour consulter la vigilance en cours, veuillez vous rendre sur le site https://vigilance.meteofrance.fr/fr

Météo-France - 73 avenue de Paris, 94165 Saint-Mandé cedex - Contact : contact@meteo.fr

Rédigé par Météo-France avec la contribution des observateurs du réseau nivo-météorologiques. Partenariat : ANMSM (Maires de Stations de Montagne), DSF (Domaines Skiables de France), ADSP (Directeurs de Pistes et de la Sécurité des Stations de Sports d'Hiver) et autres acteurs de la montagne.

Bulletin neige & avalanches par téléphone au

0 892 68 10 20 Service 0,35 € / min + prix appel