RÉPUBLIQUE FRANÇAISE
Liberté Égalité Fraternité

METEO FRANCE
À VOS CÔTÉS, DANS UN CLIMAT QUI CHANGE

Bulletin d'estimation du risque d'avalanche
(valable en dehors des pistes balisées et ouvertes)
MASSIF : Haute-Maurienne

Rédigé le jeudi 26 mars 2026 à 17h

Estimation des risques pour le : VENDREDI 27 MARS

TEMPETE EN MONTANGE. VENT TRES FORT.

3

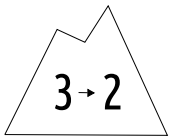

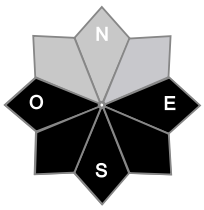

Indice de risque marqué évoluant en limité.

Départs spontanés : toute la journée.

Déclenchements provoqués : quelques plaques très réactives.

Indices de risque : 5 très fort - 4 fort - 3 marqué - 2 limité - 1 faible -- En noir : les pentes les plus dangereuses

Stabilité du manteau neigeux

Situation avalancheuse typique : neige ventée

Déclenchements provoqués : le vent tempétueux créer des plaques dures partout où la neige arrive à se déposer. On le trouve en tous versants, aussi bien aux **abords des crêtes qu'en bas de pentes**. Elles sont **réactives** car en cours de formation (vent de Nord soutenu en cours) et d'épaisseur très variable. Les avalanches engendrées sont de taille petite à moyenne (taille 2).
Observables : transport de neige en cours, accumulation, fissures devant les skis.

Départs spontanés : tant que le vent transporte la neige, des plaques se décrochent dans les pentes/talus raides (sous le vent). Activité possible toute la journée. Avalanches petites à moyennes (taille 1 à 2).

Qualité de la neige

Enneigement : Encore un peu au dessus de la moyenne, sauf aux plus basses altitudes où les hauteurs de neige sont tout juste correctes pour la saison.

Limite skiable : 1300 m au mieux en Nord. Plutôt 1600 m en sud pas trop raide.

Qualité de la neige :
En ubac, la neige est très travaillée par le vent. Cartonnée, irrégulière, durcie... tout y est. La poudre est en voie de disparition.
En adret, la neige de printemps se fait recouvrir localement par de la neige transportée depuis les ubacs. Le vent glacial empêche la neige de ramollir en journée.

Aperçu météo pour le vendredi 27 mars

	nuit	matin	après-midi	soir
Tempête de vent. 70-100 km sur les crêtes.				
Pluie-Neige				
Iso 0 °C	800 m	1 000 m	1 600 m	1 900 m
Vent 2500 m	↘ 55 km/h	↘ 45 km/h	↘ 10 km/h	↘ 10 km/h
Vent 3500 m	↓ 70 km/h	↙ 60 km/h	↓ 30 km/h	↓ 30 km/h

Épaisseur de neige hors-piste

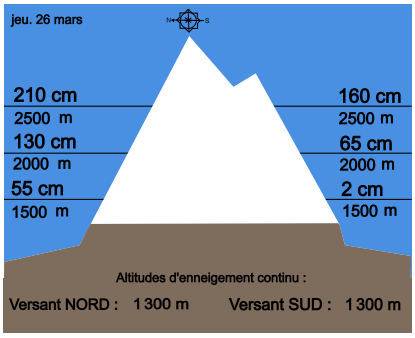

Précipitations à 1800 m

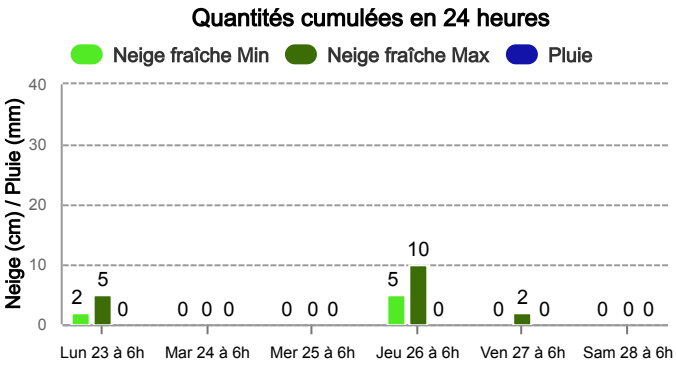

Tendance du samedi 28 mars

Indice de risque limité

Stabilisation rapide des plaques à vent récemment formées.

Pour consulter la vigilance en cours, veuillez vous rendre sur le site https://vigilance.meteofrance.fr/fr

Météo-France - 73 avenue de Paris, 94165 Saint-Mandé cedex - Contact : contact@meteo.fr

Rédigé par Météo-France avec la contribution des observateurs du réseau nivo-météorologiques. Partenariat : ANMSM (Maires de Stations de Montagne), DSF (Domaines Skiables de France), ADSP (Directeurs de Pistes et de la Sécurité des Stations de Sports d'Hiver) et autres acteurs de la montagne.

Bulletin neige & avalanches par téléphone au
0 892 68 10 20 Service 0,35 € / min + prix appel

RÉPUBLIQUE FRANÇAISE
Liberté Égalité Fraternité

METEO FRANCE
À VOS CÔTÉS, DANS UN CLIMAT QUI CHANGE

Bulletin d'estimation du risque d'avalanche
(valable en dehors des pistes balisées et ouvertes)
MASSIF : Haute-Maurienne

Rédigé le jeudi 26 mars 2026 à 17h

Conditions nivo-météo des 7 derniers jours

	ven. 20/03				sam. 21/03				dim. 22/03				lun. 23/03				mar. 24/03				mer. 25/03				jeu. 26/03			
	03h	09h	15h	21h	03h	09h	15h	21h	03h	09h	15h	21h	03h	09h	15h	21h	03h	09h	15h	21h	03h	09h	15h	21h	03h	09h	15h	21h
Météo																												
Vent (km/h)	20	20	15	10	15	20	15	20	15	20	20	10	15	20	20	20	20	20	15	35	50	65	85	100	100	95	90	75
à 3500m																												
Vent (km/h)	10	10	5	5	10	10	20	10	10	25	25	15	15	10	15	10	10	10	10	15	25	45	70	85	90	80	75	55
à 2500m																												

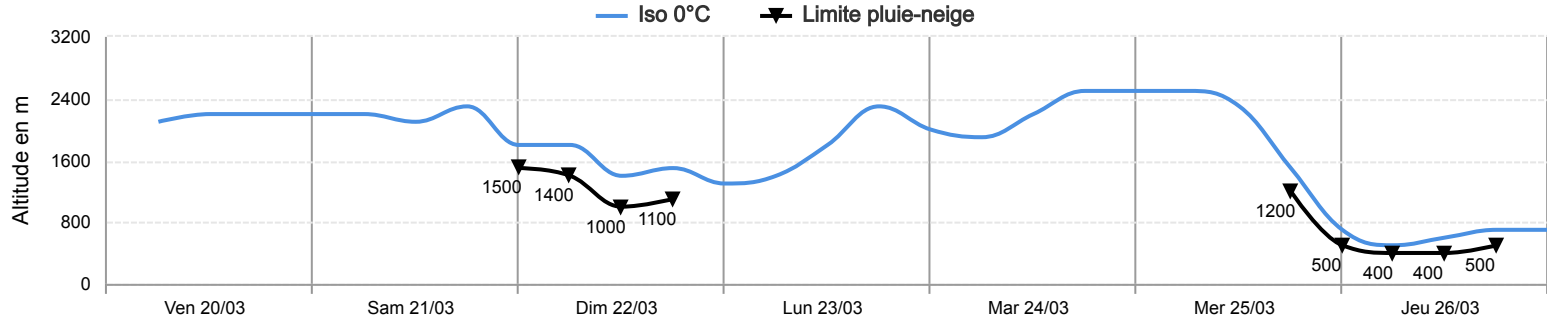

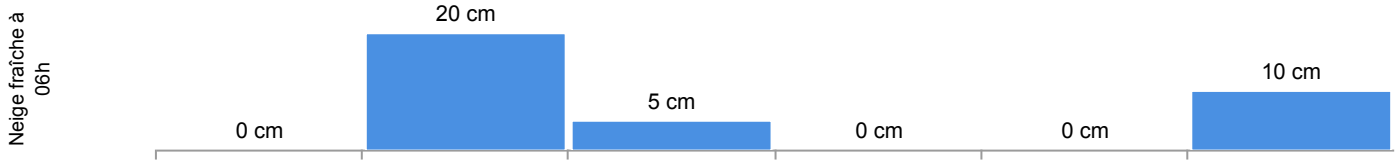

Risque d'avalanche	ven. 20/03	sam. 21/03	dim. 22/03	lun. 23/03	mar. 24/03	mer. 25/03	jeu. 26/03
	2	2	3	3	2	3	3

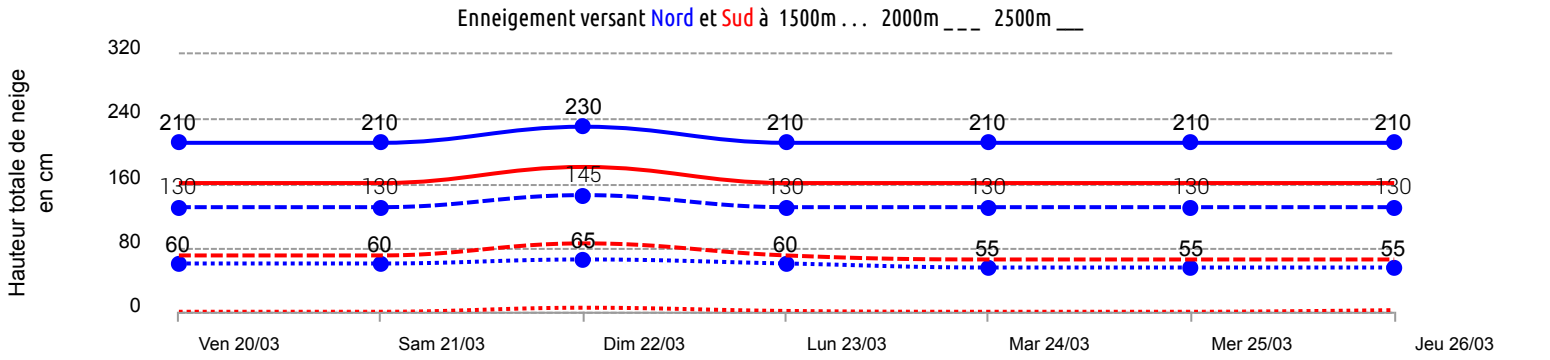

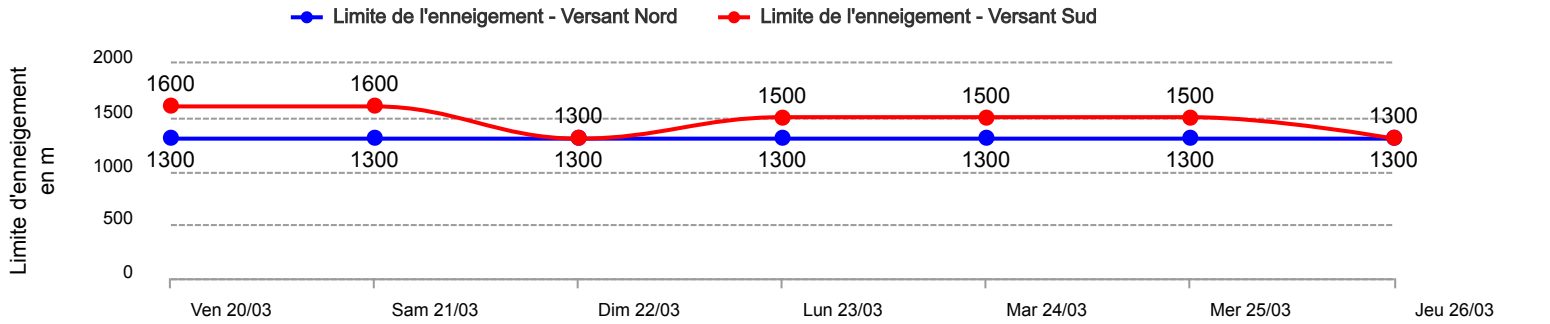

Pour consulter la vigilance en cours, veuillez vous rendre sur le site https://vigilance.meteofrance.fr/fr

Météo-France - 73 avenue de Paris, 94165 Saint-Mandé cedex - Contact : contact@meteo.fr

Rédigé par Météo-France avec la contribution des observateurs du réseau nivo-météorologiques. Partenariat : ANMSM (Maires de Stations de Montagne), DSF (Domaines Skiables de France), ADSP (Directeurs de Pistes et de la Sécurité des Stations de Sports d'Hiver) et autres acteurs de la montagne.

Bulletin neige & avalanches par téléphone au
0 892 68 10 20 Service 0,35 € / min + prix appel