Bulletin d'estimation du risque d'avalanche
(valable en dehors des pistes balisées et ouvertes)

MASSIF : Vanoise

Rédigé le jeudi 26 mars 2026 à 17h

Estimation des risques pour le : VENDREDI 27 MARS

MANTEAU NEIGEUX HIVERNAL, TRÈS VENTÉ.

3

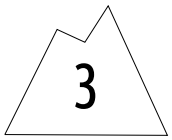

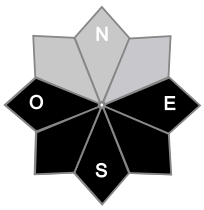

Loin des crêtes

Indice de risque marqué.

Départs spontanés : plutôt faible activité.

Déclenchements provoqués : nombreuses plaques dures en montagne.

Indices de risque : 5 très fort - 4 fort - 3 marqué - 2 limité - 1 faible -- En noir : les pentes les plus dangereuses

Stabilité du manteau neigeux

Situation avalancheuse typique : neige ventée

Déclenchements provoqués : nombreuses plaques dans ce contexte venté. On les trouve en tous versants, **plutôt loin des crêtes, jusqu'en bas de pentes,** derrières les bosses et les croupes. Elles sont réactives au matin avec une tendance à la stabilisation au fil des heures. D'épaisseur très variable, les plaques sont souvent en neige ferme/dure et engendrent des avalanches moyennes (taille 2).
Secteur Lauzière : les cumuls de neige sont plus importants qu'ailleurs, les avalanches sont plus nombreuses et généralement de plus grandes tailles.
Observables : accumulations visibles derrière les ruptures de pente.

Départs spontanés : la baisse du vent en matinée met fin au risque de départs naturels de plaques dans les zones d'accumulations sous le vent. Le retour du Soleil engendre des coulées dans les pentes raides ayant trop chauffées, au départ des rochers/des corniches, plutôt en fin de journée donc dans les pentes Sud à Ouest. Taille 1 à 2.

Qualité de la neige

Enneigement : Encore un peu au dessus de la moyenne, sauf aux plus basses altitudes où les hauteurs de neige sont tout juste correctes pour la saison.

Limite skiable : 1300 m au mieux en Nord. Plutôt 1600 m en sud pas trop raide.

Qualité de la neige : c'est en forêt qu'il y a le plus de neige poudreuse. Au-dessus, le vent a fait du grabuge. La neige est au mieux densifiée, sinon elle est cartonnée, irrégulière, dure. Les crêtes et les croupes face au vent de Nord sont pelées, glacées bétonnées.
Les pentes très exposées au Soleil chauffent. La neige botte et devient lourde/collante après plusieurs heures d'ensoleillement. En haute montagne ensoleillée, le vent de Nord ralentie le réchauffement dans les pentes ensoleillées.

Aperçu météo pour le vendredi 27 mars

	nuit	matin	après-midi	soir

Conditions de plus en plus calmes au fil des heures.

Pluie-Neige	400 m			
Iso 0 °C	700 m	900 m	1 400 m	1 500 m
Vent 2500 m	↘ 45 km/h	↘ 45 km/h	→ 15 km/h	↗ 10 km/h
Vent 3500 m	↓ 55 km/h	↙ 55 km/h	↙ 30 km/h	↙ 20 km/h

Épaisseur de neige hors-piste

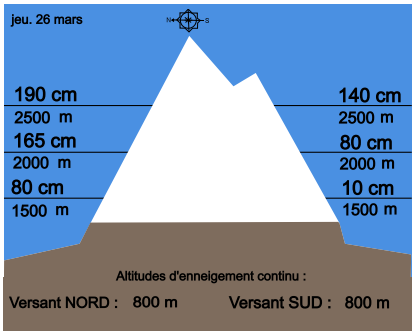

Précipitations à 1800 m

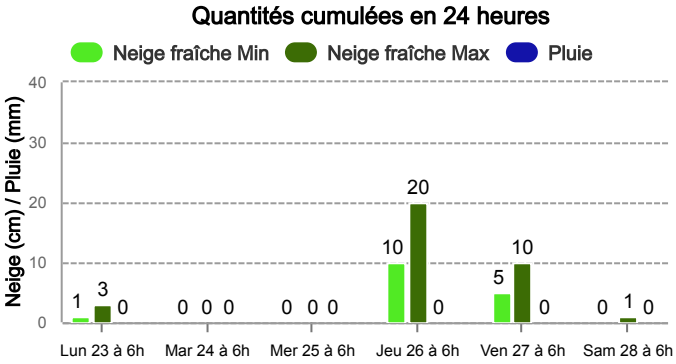

Tendance du samedi 28 mars

2

Indice de risque limité

Stabilisation rapide du manteau neigeux.

Pour consulter la vigilance en cours, veuillez vous rendre sur le site https://vigilance.meteofrance.fr/fr

Météo-France - 73 avenue de Paris, 94165 Saint-Mandé cedex - Contact : contact@meteo.fr

Rédigé par Météo-France avec la contribution des observateurs du réseau nivo-météorologiques. Partenariat : ANMSM (Maires de Stations de Montagne), DSF (Domaines Skiables de France), ADSP (Directeurs de Pistes et de la Sécurité des Stations de Sports d'Hiver) et autres acteurs de la montagne.

Bulletin neige & avalanches par téléphone au **0 892 68 10 20** Service 0,35 € / min + prix appel

RÉPUBLIQUE FRANÇAISE
Liberté Égalité Fraternité

METEO FRANCE
À VOS CÔTÉS, DANS UN CLIMAT QUI CHANGE

Bulletin d'estimation du risque d'avalanche

(valable en dehors des pistes balisées et ouvertes)

MASSIF : Vanoise

Rédigé le jeudi 26 mars 2026 à 17h

Conditions nivo-météo des 7 derniers jours

	ven. 20/03				sam. 21/03				dim. 22/03				lun. 23/03				mar. 24/03				mer. 25/03				jeu. 26/03			
	03h	09h	15h	21h	03h	09h	15h	21h	03h	09h	15h	21h	03h	09h	15h	21h	03h	09h	15h	21h	03h	09h	15h	21h	03h	09h	15h	21h
Météo																												
Vent (km/h)	20	20	15	15	20	25	20	20	15	15	15	10	20	25	20	20	20	25	20	20	40	60	85	85	70	65	70	60
à 3500m																												
Vent (km/h)	10	5	0	5	5	10	15	10	10	20	25	15	10	10	15	10	10	10	10	10	30	45	70	70	60	55	60	50
à 2500m																												

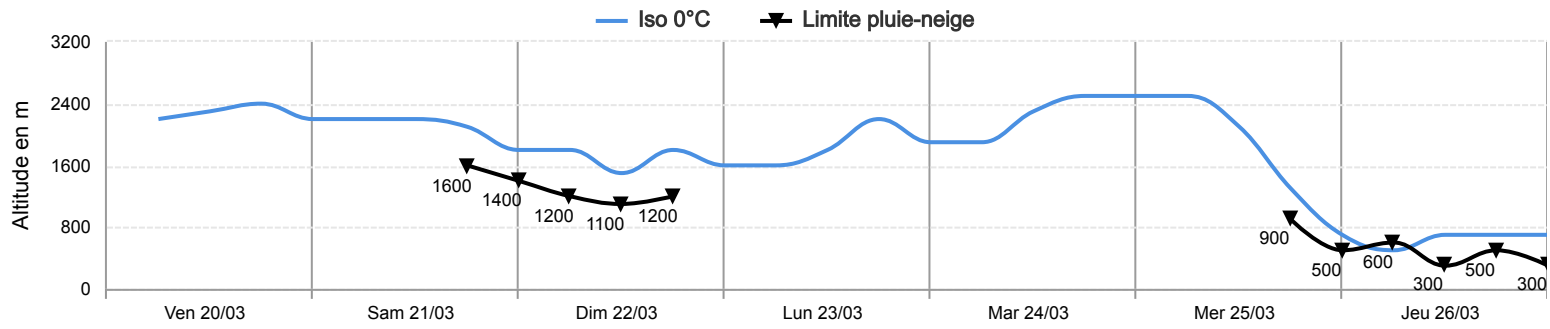

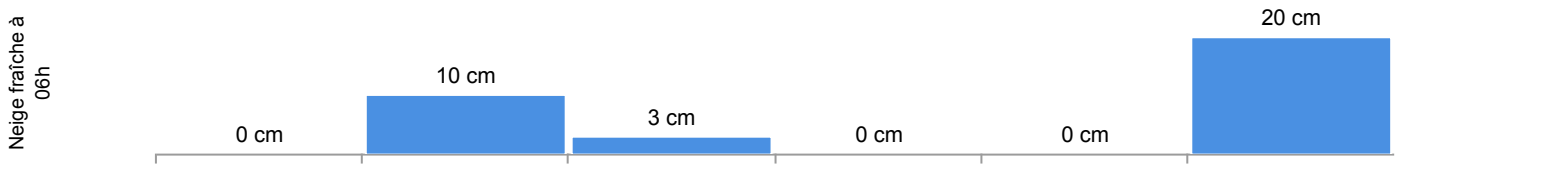

Risque d'avalanche	ven. 20/03	sam. 21/03	dim. 22/03	lun. 23/03	mar. 24/03	mer. 25/03	jeu. 26/03
	2	2	2	2	2	3	3

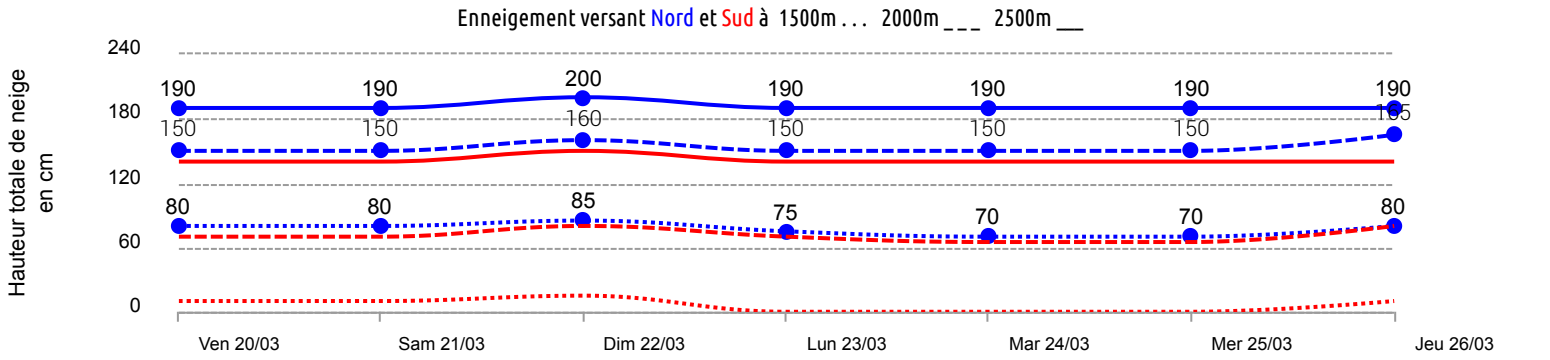

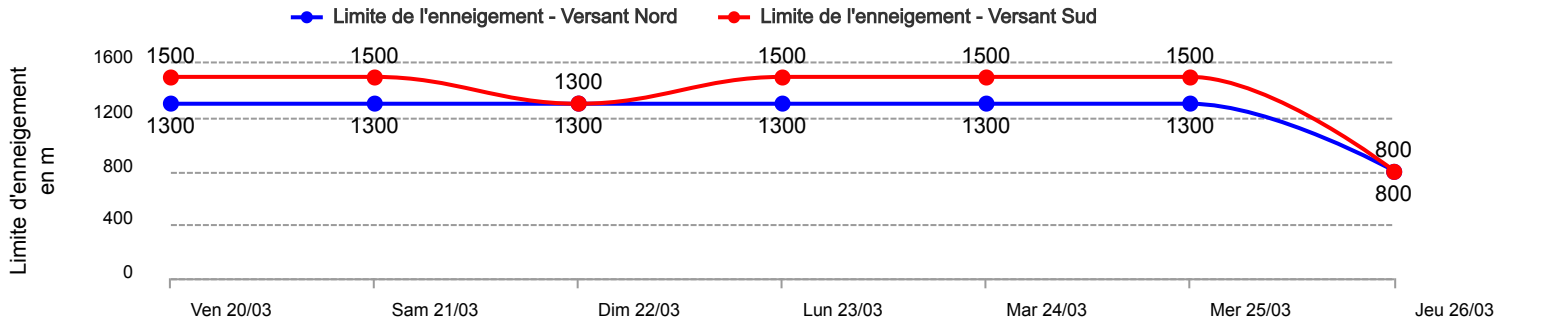

Pour consulter la vigilance en cours, veuillez vous rendre sur le site https://vigilance.meteofrance.fr/fr

Météo-France - 73 avenue de Paris, 94165 Saint-Mandé cedex - Contact : contact@meteo.fr

Bulletin neige & avalanches par téléphone au

0 892 68 10 20 Service 0,35 € / min + prix appel

Rédigé par Météo-France avec la contribution des observateurs du réseau nivo-météorologiques. Partenariat : ANMSM (Maires de Stations de Montagne), DSF (Domaines Skiables de France), ADSP (Directeurs de Pistes et de la Sécurité des Stations de Sports d'Hiver) et autres acteurs de la montagne.