GOBIERNO DE ESPAÑA
VICEPRESIDENCIA TERCERA DEL GOBIERNO
MINISTERIO PARA LA TRANSICIÓN ECOLÓGICA Y EL RETO DEMOGRÁFICO

Boletín de información nivológica y de peligro de aludes

Pirineo Catalán

aemet Agencia Estatal de Meteorología

viernes, 27 de marzo de 2026

Pronóstico hasta las 24 horas del sábado, día 28 de marzo

(Válido fuera de pistas de esquí balizadas y abiertas)

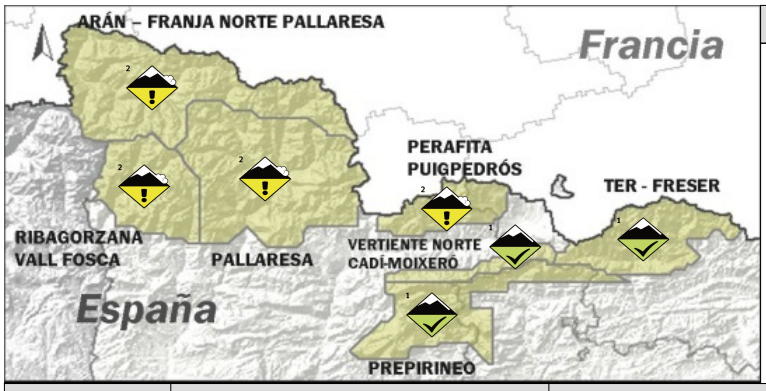

Problemas de aludes

Placas de viento

Nieve reciente

Macizo	Peligro	Problemas de aludes, cota, orientación, tamaño	Innivación observada (m)
Arán - Franja norte Pallaresa	2 2 / 1→2 — 2200 Durante el día **Limitado**	**Placas de viento** — 1800 — N O E S — 2 **Nieve reciente** — N O E S — 2	2026-03-27 N S Cota más baja caras N
Ribagorzana - Vall Fosca	2 2 / 1 — 1800 **Limitado**	**Placas de viento** — 1800 — N O E S — 1 **Nieve reciente** — N O E S — 1	2026-03-27 N S Cota más baja caras N
Pallaresa	2 2 / 1 — 1800 **Limitado**	**Placas de viento** — 1800 — N O E S — 1 **Nieve reciente** — N O E S — 1	2026-03-27 N S Cota más baja caras N

AEMET. Se autoriza la reproducción de su contenido citando la fuente.

Boletín de información nivológica y de peligro de aludes

Pirineo Catalán

Perafita - Puigpedrós	2 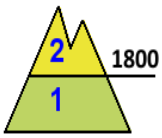 **Limitado**	**Placas de viento** 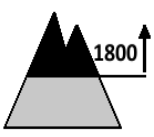 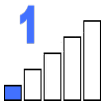 **Nieve reciente** 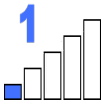	2026-03-27 Cota más baja caras N
Ter - Freser	1 **Débil**	**Placas de viento** 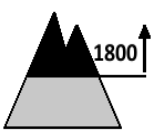 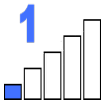	2026-03-27 Cota más baja caras N
Vertiente norte Cadí - Moixeró	1 **Débil**	**Placas de viento** 	2026-03-27 Cota más baja caras N
Prepirineo	1 **Débil**	**Placas de viento** 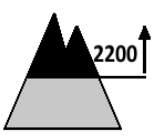 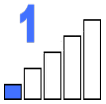	2026-03-27 Cota más baja caras N

Estado del manto y observaciones recientes

Con el flujo intenso de norte, el transporte de la nieve seca y el enfriamiento de la húmeda han sido los procesos más significativos para el manto durante las últimas horas. Este ha quedado endurecido o encostrado de manera generalizada en todas las cotas y orientaciones. Por encima, se han formado pequeñas placas de viento en orientación sur, al tiempo que en los sitios más resguardados se puede encontrar una delgada capa de nieve reciente, todo esto especialmente en el Arán-F.N.Pallaresa. En umbrías de cotas altas, todavía pueden existir capas débiles internas que pueden colapsar ante sobrecargas fuertes.

En cuanto su continuidad, el manto se inicia en cotas medias, algo más arriba en las laderas norte que en las sur. Los espesores siguen estando muy por encima de lo habitual para la época, superándose los 150-200 cm en cota 2200 en la mayoría de zonas.

Evolución del manto y peligro de aludes para el sábado, día 28

Problemas de nieve reciente y de placas de viento en cotas altas.

El peligro aumentará durante la segunda mitad del día, con la llegada de las nevadas. Se irán formando numerosas placas de viento incluso en cotas medias y preferentemente en orientaciones sur, este y oeste. Estas se mantendrán frágiles, capaces de colapsar ante sobrecargas débiles y serán susceptibles de desencadenar aludes de tamaño pequeño o localmente mediano.

AEMET. Se autoriza la reproducción de su contenido citando la fuente.

También en la segunda mitad del día, se irán haciendo más frecuentes las purgas de nieve reciente en laderas con la suficiente inclinación. Estas serán de tamaño pequeño inicialmente, pudiéndose alcanzar el mediano de manera local al final del día.

En umbrías de cotas altas, las capas débiles persistentes todavía podrían colapsar en algunos puntos, aunque generalmente harán falta sobrecargas fuertes. Los aludes provocados por este motivo podrán alcanzar el tamaño mediano.

Predicción meteorológica para el sábado, día 28

Nuboso en el Arán y poco nuboso en el resto, tendiendo a cubrirse por la tarde, algo antes en el Arán. Periodos de visibilidad localmente reducida. Precipitaciones débiles o moderadas en la segunda mitad del día, siendo más probables e intensas en el Arán y resto de la divisoria fronteriza. Cota de nieve en torno a 1200-1300 metros, pudiendo bajar a últimas horas hasta los 700. Temperaturas sin cambios, o máximas en ligero ascenso. Las mínimas se podrán dar al final del día. Heladas débiles, moderadas o fuertes en cotas altas, donde serán localmente persistentes. Viento moderado de componente norte, aumentando a fuerte en el transcurso del día, con rachas muy fuertes en cotas altas y zonas expuestas que podrán superar los 110 km/h en algunos puntos.

Datos en la atmósfera libre:

Altitud de la isoterma de 0 ºC: 1800 m
Altitud de la isoterma de -10 ºC: 4000 m

Viento a 1500 m: N 30 km/h
Viento a 3000 m: N 60 km/h

Evolución para el domingo día 29

Nivel de peligro en ascenso, con el incremento de los problemas de nieve seca.

Escala europea de peligro de aludes

Débil | Limitado | Notable | Fuerte | Muy Fuerte

Problemas de aludes

Nieve reciente | Placas de viento | Capas débiles persistentes | Nieve húmeda | Deslizamientos basales | Sin problema evidente

Nota1: Se recuerda que, siempre que haya nieve, la ausencia total de peligro no existe. Hay que tener presente que en circunstancias desfavorables, con aludes de tamaño 1 (alud pequeño o colada) y tamaño 2 (alud mediano), se pueden sufrir severos daños personales.

Nota2: Los BPA se elaboran en base a información meteorológica así como al estado del manto nivoso a través de sondeos puntuales. Se advierte a los usuarios de la variabilidad de esta información al extrapolarla a zonas extensas de montaña. Por ello, AEMET no se hace responsable de su uso para la toma de decisiones que conciernen a la seguridad personal, ni de los riesgos físicos o materiales de ellas derivadas.

AEMET. Se autoriza la reproducción de su contenido citando la fuente.