GOBIERNO DE ESPAÑA
VICEPRESIDENCIA TERCERA DEL GOBIERNO
MINISTERIO PARA LA TRANSICIÓN ECOLÓGICA Y EL RETO DEMOGRÁFICO

Boletín de información nivológica y de peligro de aludes

Pirineo Navarro y Aragonés

aemet Agencia Estatal de Meteorología

viernes, 27 de marzo de 2026

Pronóstico hasta las 24 horas del sábado, día 28 de marzo

(Válido fuera de pistas de esquí balizadas y abiertas)

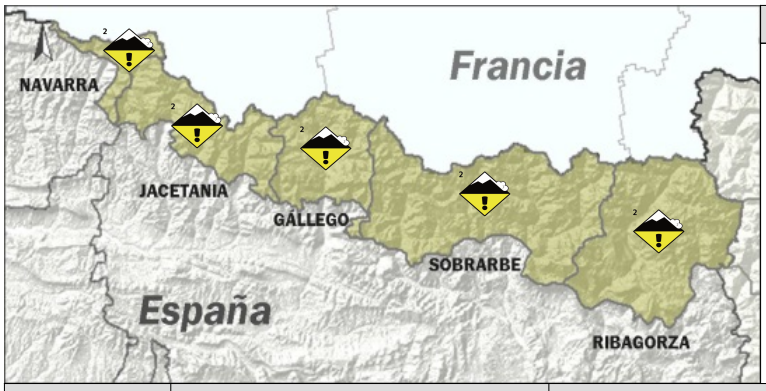

Problemas de aludes

Placas de viento

Nieve reciente

Macizo	Peligro	Problemas de aludes, cota, orientación, tamaño	Innivación observada (m)
Navarra	2 2 / 1→2 / 2200 Durante el día **Limitado**	**Placas de viento** 1800 N O E S 2 **Nieve reciente** N O E S 2	2026-03-27 N S Cota más baja caras N
Jacetania	2 2 / 1→2 / 2200 Durante el día **Limitado**	**Placas de viento** 1800 N O E S 2 **Nieve reciente** N O E S 2	2026-03-27 N S Cota más baja caras N
Gállego	2 2 / 1→2 / 2200 Durante el día **Limitado**	**Placas de viento** 1800 N O E S 2 **Nieve reciente** N O E S 2	2026-03-27 N S Cota más baja caras N

AEMET. Se autoriza la reproducción de su contenido citando la fuente.

Sobrarbe	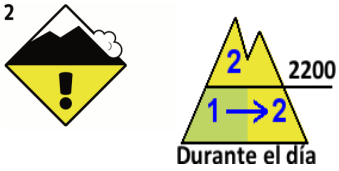 **Limitado**	**Placas de viento** **Nieve reciente** 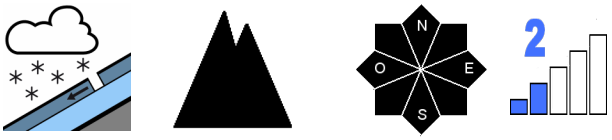	2026-03-27 Cota más baja caras N
Ribagorza	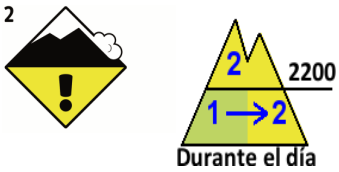 **Limitado**	**Placas de viento** 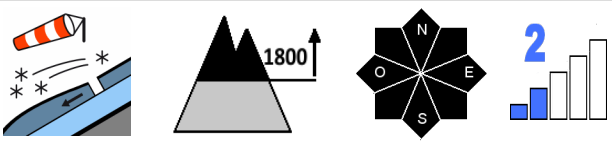 **Nieve reciente** 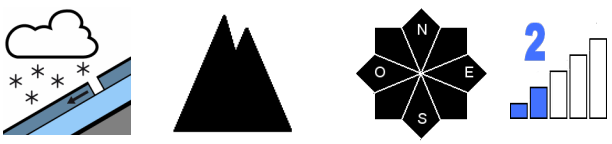	2026-03-27 Cota más baja caras N

Estado del manto y observaciones recientes

Con el flujo intenso de norte, el transporte de la nieve seca y el enfriamiento de la húmeda han sido los procesos más significativos para el manto durante las últimas horas. Este ha quedado endurecido o encostrado de manera generalizada en todas las cotas y orientaciones. Por encima, se han formado pequeñas placas de viento en orientación sur, al tiempo que en los sitios más resguardados se puede encontrar una delgada capa de nieve reciente, todo esto especialmente en Navarra y Jacetania. Las capas débiles internas que persistían en umbrías de cotas altas se muestran más difíciles de desencadenar. Además, se están formando facetas en superficie, asegurando una mala cohesión con la nieve nueva que está por caer a partir de mañana.

En cuanto a su continuidad, el manto se inicia en cotas medias, algo más arriba en laderas norte (1600 m) que en las sur (1800 m). Los espesores siguen estando por encima de lo habitual para la época, con valores de 100-200 cm en cota 2200 y superiores por encima.

Evolución del manto y peligro de aludes para el sábado, día 28

Problemas de nieve reciente y de placas de viento en cotas altas.

El peligro aumentará durante la segunda mitad del día, con la llegada de las nevadas. Se irán formando numerosas placas de viento incluso en cotas medias y preferentemente en orientaciones sur, este y oeste. Estas se mantendrán frágiles, capaces de colapsar ante sobrecargas débiles y serán susceptibles de desencadenar aludes de tamaño localmente mediano.

También en la segunda mitad del día, se irán haciendo más frecuentes las purgas de nieve reciente en laderas con la suficiente inclinación. Estas serán de tamaño pequeño inicialmente, pudiéndose alcanzar el mediano de manera local al final del día.

AEMET. Se autoriza la reproducción de su contenido citando la fuente.

Predicción meteorológica para el sábado, día 28

Pirineo navarro:
Poco nuboso o despejado al inicio, aumentando a muy nuboso o cubierto por la mañana, con nubes bajas y visibilidad localmente reducida. Precipitaciones débiles o moderadas, en la segunda mitad del día. Cota de nieve en torno a 1200 metros, pudiendo bajar a últimas horas hasta los 800. Temperaturas sin cambios o en ligero descenso, pudiendo darse las mínimas al final del día. Heladas débiles, moderadas o incluso fuertes en cotas altas. Viento fuerte de componente norte, con rachas muy fuertes en cotas altas y zonas expuestas.

Pirineo aragonés:
Poco nuboso o despejado a primeras horas, tendiendo a cubrirse, primero en la divisoria y por la tarde en el resto. Al final del día, se podrán abrir grandes claros al sur de la divisoria fronteriza. Periodos de visibilidad localmente reducida.
Precipitaciones débiles o moderadas en la segunda mitad del día, siendo más probables e intensas en la divisoria con Francia. Cota de nieve en torno a 1400 metros, pudiendo bajar a últimas horas hasta los 700. Temperaturas sin cambios o en ligero ascenso. Las mínimas se podrán dar al final del día. Heladas débiles, moderadas o fuertes en cotas altas, donde serán localmente persistentes. Viento flojo o moderado de componente norte, aumentando a fuerte en el transcurso del día, con rachas muy fuertes en cotas altas y zonas expuestas que podrán superar los 110 km/h en algunos puntos.

Datos en la atmósfera libre:

Altitud de la isoterma de 0 ºC: 1800 m
Altitud de la isoterma de -10 ºC: 4000 m

Viento a 1500 m: N 30 km/h
Viento a 3000 m: N 60 km/h

Evolución para el domingo día 29

Nivel de peligro en ascenso, con el incremento de los problemas de nieve seca.

(Información elaborada a partir de los datos recibidos de los refugios de Lizara, Panticosa, Bachimaña, Góriz, Pineta, Estós, Angel Orús, Cap de Llauset y Belagua y de las estaciones de esquí de Candanchú, Astún y Panticosa (lagos))

Escala europea de peligro de aludes

Débil | Limitado | Notable | Fuerte | Muy Fuerte

Problemas de aludes

Nieve reciente | Placas de viento | Capas débiles persistentes | Nieve húmeda | Deslizamientos basales | Sin problema evidente

Nota1: Se recuerda que, siempre que haya nieve, la ausencia total de peligro no existe. Hay que tener presente que en circunstancias desfavorables, con aludes de tamaño 1 (alud pequeño o colada) y tamaño 2 (alud mediano), se pueden sufrir severos daños personales.

Nota2: Los BPA se elaboran en base a información meteorológica así como al estado del manto nivoso a través de sondeos puntuales. Se advierte a los usuarios de la variabilidad de esta información al extrapolarla a zonas extensas de montaña. Por ello, AEMET no se hace responsable de su uso para la toma de decisiones que conciernen a la seguridad personal, ni de los riesgos físicos o materiales de ellas derivadas.

AEMET. Se autoriza la reproducción de su contenido citando la fuente.