Samstag 28.03.2026

Veröffentlicht am 27.03.2026 um 17:00

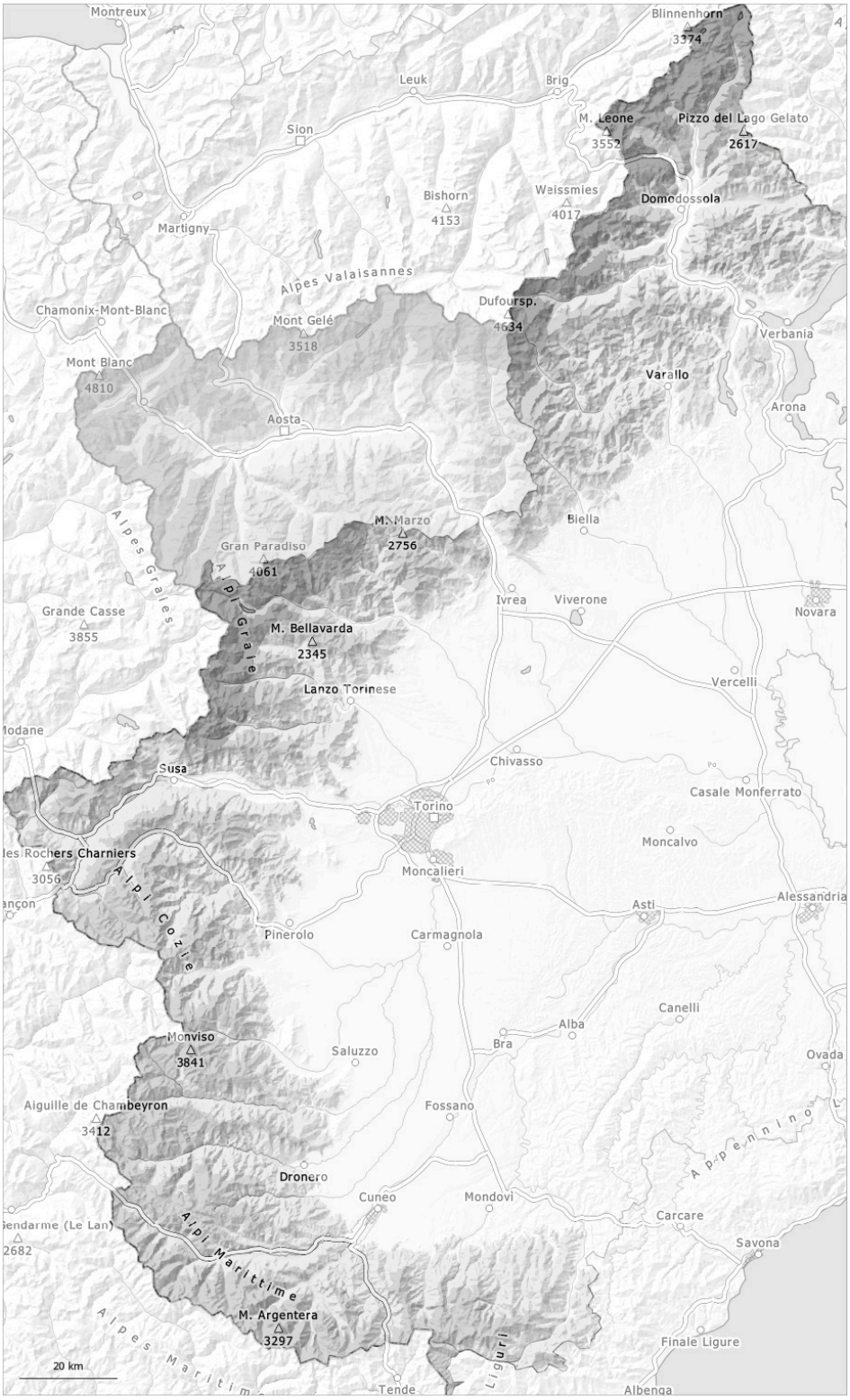

1	2	3	4	5
gering	mäßig	erheblich	groß	sehr groß

Gefahrenstufe 3 - Erheblich

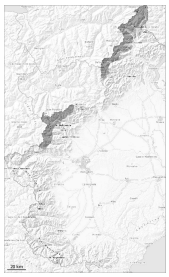

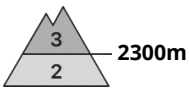

Tendenz: Lawinengefahr nimmt ab
am Sonntag, den 29.03.2026

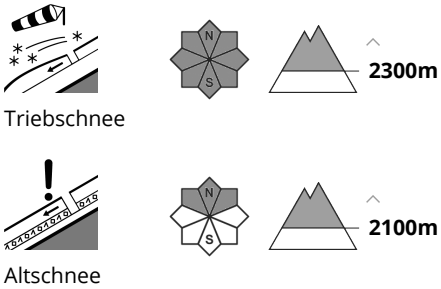

Vorsicht vor Triebschnee.

Der Sturm hat Neu- und Altschnee intensiv verfrachtet.
Die harten Triebschneeansammlungen der letzten drei Tage liegen vor allem an Sonnenhängen und in hohen Lagen auf einer Kruste. Diese können von einzelnen Wintersportlern ausgelöst werden. Die Lawinen können vor allem an steilen Nord-, Nordost- und Nordwesthängen im kantig aufgebauten Altschnee ausgelöst werden und recht groß werden.

Vorsicht an Triebschneehängen und in Rinnen und Mulden.

Schneedecke

Gefahrenmuster gm.6: lockerer schnee und wind

Am Mittwoch fielen gebietsweise 10 bis 15 cm Schnee, lokal bis zu 20 cm.
Der Föhn hat Neu- und Altschnee intensiv verfrachtet. Der Triebschnee liegt verbreitet auf einer harten Kruste.
V.a. in Kammlagen in hohen Lagen liegen je nach Windeinfluss sehr unterschiedliche Schneehöhen.

Mit tiefen Temperaturen kann sich die Schneedecke nicht verfestigen, vor allem an Schattenhängen.

Tendenz

Die Sonneneinstrahlung führt vor allem an Sonnenhängen zu einer allmählichen Verfestigung der Schneedecke.

Gefahrenstufe 2 - Mäßig

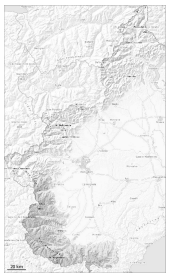

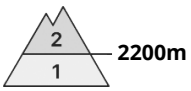

Tendenz: Lawinengefahr steigt
am Sonntag, den 29.03.2026

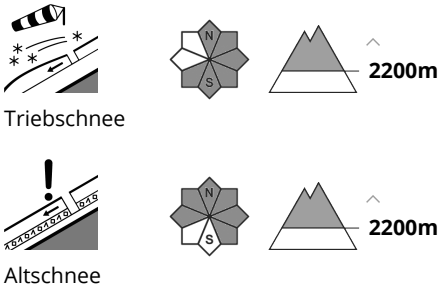

Es sind weiterhin Schneebrettlawinen möglich, auch mittelgroße.

Der Nordwestwind hat den lockeren Altschnee verfrachtet. Triebschneeansammlungen entstanden vor allem an Nordost-, Ost- und Südhängen.
Triebschneeansammlungen können vereinzelt schon von einzelnen Wintersportlern ausgelöst werden und mittlere Größe erreichen. Dies vor allem an Übergängen von wenig zu viel Schnee wie z.B. bei der Einfahrt in Rinnen und Mulden und an Triebschneehängen in der Höhe.

Ungünstig sind steile Hänge, wo frische Triebschneeansammlungen auf Schmelz- und Regenkrusten oder auf glatten, verhärteten Oberflächen liegen, sowie steile Schattenhänge, wo im oberen Teil der Altschneedecke Schwachschichten vorhanden sind.

Schneedecke

Gefahrenmuster gm.6: lockerer schnee und wind

Der Nordwestwind hat den lockeren Altschnee verfrachtet. Mit starkem Föhn entstanden in den letzten drei Tagen Triebschneeansammlungen.
Vor allem in Gipfellagen liegen je nach Windeinfluss sehr unterschiedliche Schneehöhen.

Hohe Lagen und Hochgebirge: Der Triebschnee liegt verbreitet auf einer harten Kruste.
An sonnigeren Hängen, wo die Temperaturen weniger kalt sind, wird die harte Oberfläche der Schneedecke im Tagesverlauf langsam weicher.

In der Altschneedecke sind v.a. an Schattenhängen einzelne Schwachschichten vorhanden.

Tendenz

Mit Neuschnee und Wind nimmt die Anzahl der Gefahrenstellen am Sonntag zu.

Gefahrenstufe 2 - Mäßig

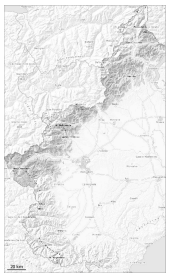

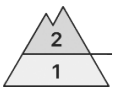

Waldgrenze

Tendenz: Lawinengefahr bleibt gleich
am Sonntag, den 29.03.2026

Triebschnee

Waldgrenze

Altschnee

2200m

Die Triebschneeansammlungen sind vorsichtig zu beurteilen.

Der Nordwestwind hat Neu- und Altschnee intensiv verfrachtet. Die harten Triebschneeansammlungen liegen vor allem an Sonnenhängen und in hohen Lagen auf einer Kruste.
Diese können vereinzelt schon von einzelnen Wintersportlern ausgelöst werden und mittlere Größe erreichen. Die Gefahrenstellen liegen vor allem in Rinnen und Mulden sowie an Triebschneehängen. Entlang der Grenze zu Frankreich ist die Auslösebereitschaft höher.

Auf der harten Schneeoberfläche besteht im Steilgelände Absturzgefahr.

Touren erfordern Vorsicht.

Schneedecke

Gefahrenmuster gm.6: lockerer schnee und wind

Der Föhn hat Neu- und Altschnee intensiv verfrachtet. Der Triebschnee liegt verbreitet auf einer harten Kruste, besonders an Sonnenhängen in allen Höhenlagen und in Kamm- und Passlagen in der Höhe.

Hohe Lagen Schattenhänge: Der untere Teil der Schneedecke ist kantig aufgebaut.
Im mittleren Teil der Schneedecke sind besonders an West-, Nord- und Nordosthängen einzelne Schwachschichten vorhanden.

An sonnigeren Hängen, wo die Temperaturen weniger kalt sind, wird die harte Oberfläche der Schneedecke im Tagesverlauf langsam weicher.

V.a. in Kammlagen in hohen Lagen liegen je nach Windeinfluss sehr unterschiedliche Schneehöhen.