Samstag 28.03.2026

Veröffentlicht am 27.03.2026 um 17:00

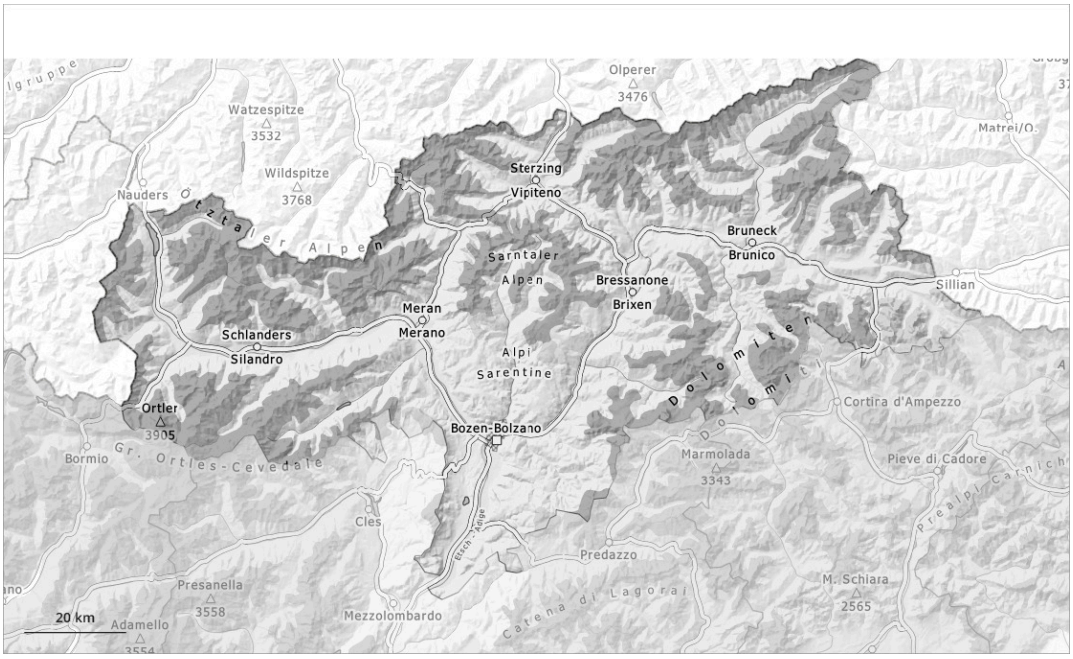

1	2	3	4	5
gering	mäßig	erheblich	groß	sehr groß

Gefahrenstufe 3 - Erheblich

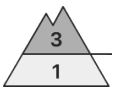

Waldgrenze

Tendenz: Lawinengefahr bleibt gleich
am Sonntag, den 29.03.2026

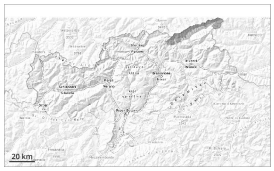

Triebschnee

Waldgrenze

Altschnee

2200m

Abseits gesicherter Pisten ungünstige Lawinensituation.

Die umfangreichen Triebschneeansammlungen sind an allen Expositionen oberhalb der Waldgrenze sehr störanfällig. Diese können in oberflächennahen Schichten ausgelöst werden und mittlere Größe erreichen. Lawinen können auch in bodennahe Schichten der Schneedecke durchreißen und an West-, Nord- und Osthängen groß werden. Wummgeräusche und Risse beim Betreten der Schneedecke sowie frische Lawinen sind Alarmzeichen und weisen auf die Gefahr hin.

Mit der Sonneneinstrahlung sind Lockerschneelawinen möglich. Dies vor allem an sehr steilen Hängen in windgeschützten Lagen.

Schneedecke

Gefahrenmuster gm.6: lockerer schnee und wind | gm.1: bodennahe schwachschicht

In den letzten Tagen fielen 20 bis 50 cm Schnee.
Der Wind blies teils orkanartig. Der Nordwestwind hat den Neuschnee und teilweise auch Altschnee verfrachtet. Es entstanden umfangreiche Triebschneeansammlungen.

Neu- und Triebschnee liegen oberhalb der Waldgrenze auf einer ungünstigen Altschneeoberfläche. Die Altschneedecke ist schwach, besonders an West-, Nord- und Osthängen oberhalb von rund 2200 m und an Südhängen in der Höhe.

Tendenz

Lawinen können leicht ausgelöst werden.

Gefahrenstufe 3 - Erheblich

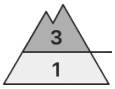

Waldgrenze

Tendenz: Lawinengefahr bleibt gleich
am Sonntag, den 29.03.2026

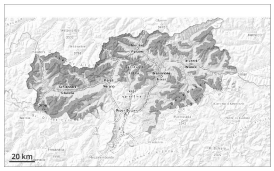

Triebschnee

Waldgrenze

Altschnee

2200m

Abseits der Pisten verbreitet heikle Lawinensituation.

Mit Neuschnee und stürmischem Nordwind entstanden an allen Expositionen teils große Triebschneeansammlungen. Diese können oberhalb der Waldgrenze sehr leicht ausgelöst werden. Lawinen können in oberflächennahen Schichten anreißen. Zudem können stellenweise Lawinen in bodennahe Schichten der Schneedecke durchreißen, besonders an West-, Nord- und Osthängen oberhalb von rund 2200 m.
Die Gefährdung bezieht sich hauptsächlich auf alpines Schneesportgelände. Wummgeräusche und Risse beim Betreten der Schneedecke sind Alarmzeichen und weisen auf die Gefahr hin.

Zudem sind trockene Lockerschneelawinen möglich, besonders an extrem steilen Hängen bei Sonneneinstrahlung.

An diesem ersten sonnigen Tag ist Zurückhaltung angebracht.

Schneedecke

Gefahrenmuster gm.6: lockerer schnee und wind | gm.1: bodennahe schwachschicht

Seit Mittwoch fielen 10 bis 20 cm Schnee, lokal auch mehr.
Der Wind blies teils orkanartig. Der Wind hat Neu- und Altschnee intensiv verfrachtet.

Neu- und Triebschnee liegen oberhalb der Waldgrenze auf einer ungünstigen Altschneeoberfläche. Die Altschneedecke ist schwach, besonders an West-, Nord- und Osthängen oberhalb von rund 2200 m und an Südhängen in der Höhe.

Tendenz

Lawinen können weiterhin leicht ausgelöst werden.

Gefahrenstufe 2 - Mäßig

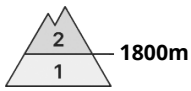

Tendenz: Lawinengefahr bleibt gleich
am Sonntag, den 29.03.2026

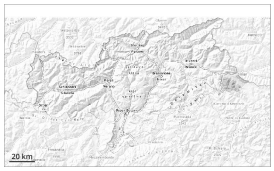

Triebschnee

Altschnee

Vorsicht vor frischem Triebschnee.

Triebschneeansammlungen können an allen Expositionen oberhalb von rund 1800 m von einzelnen Wintersportlern leicht ausgelöst werden. Gefahrenstellen liegen vor allem in Rinnen, Mulden und hinter Geländekanten. Dies auch kammfern sowie in windgeschützten Lagen. Lawinen sind mittelgroß.

Vereinzelt können Lawinen auch in bodennahe Schichten der Schneedecke durchreißen. Vorsicht vor allem an sehr steilen West-, Nord- und Osthängen oberhalb von rund 2200 m und an Südhängen in der Höhe. Ungünstig sind besonders Übergänge von wenig zu viel Schnee.

Schneedecke

Gefahrenmuster gm.6: lockerer schnee und wind | gm.1: bodennahe schwachschicht

In den letzten Tagen fielen 10 bis 15 cm Schnee. Der Nordwestwind hat Neu- und Altschnee intensiv verfrachtet. Mit böigem Wind entstanden störanfällige Triebschneeansammlungen.

Neu- und Triebschnee liegen oberhalb von rund 1800 m auf einer ungünstigen Altschneeoberfläche. Die Altschneedecke ist schwach, besonders an West-, Nord- und Osthängen oberhalb von rund 2200 m und an Südhängen in der Höhe.

Tendenz

Lawinen können von einzelnen Wintersportlern ausgelöst werden.

Gefahrenstufe 2 - Mäßig

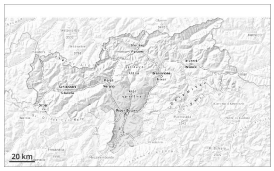

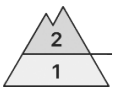

Waldgrenze

Tendenz: Lawinengefahr nimmt ab
am Sonntag, den 29.03.2026

Triebschnee

Waldgrenze

Frischen Triebschnee vorsichtig beurteilen.

Triebschneeansammlungen sind vor allem an den Expositionen West über Nord bis Ost oberhalb der Waldgrenze teils störanfällig. Lawinen können sehr vereinzelt in bodennahe Schichten der Schneedecke durchreißen und mittlere Größe erreichen.

Schneedecke

Gefahrenmuster gm.6: lockerer schnee und wind | gm.1: bodennahe schwachschicht

Der Wind blies teils stürmisch. Der Nordwestwind hat Schnee verfrachtet. Es entstanden störanfällige Triebschneeansammlungen.

Tendenz

Frischen Triebschnee vorsichtig beurteilen.