Samedi 28.03.2026

Publié 27 03 2026, 17:00

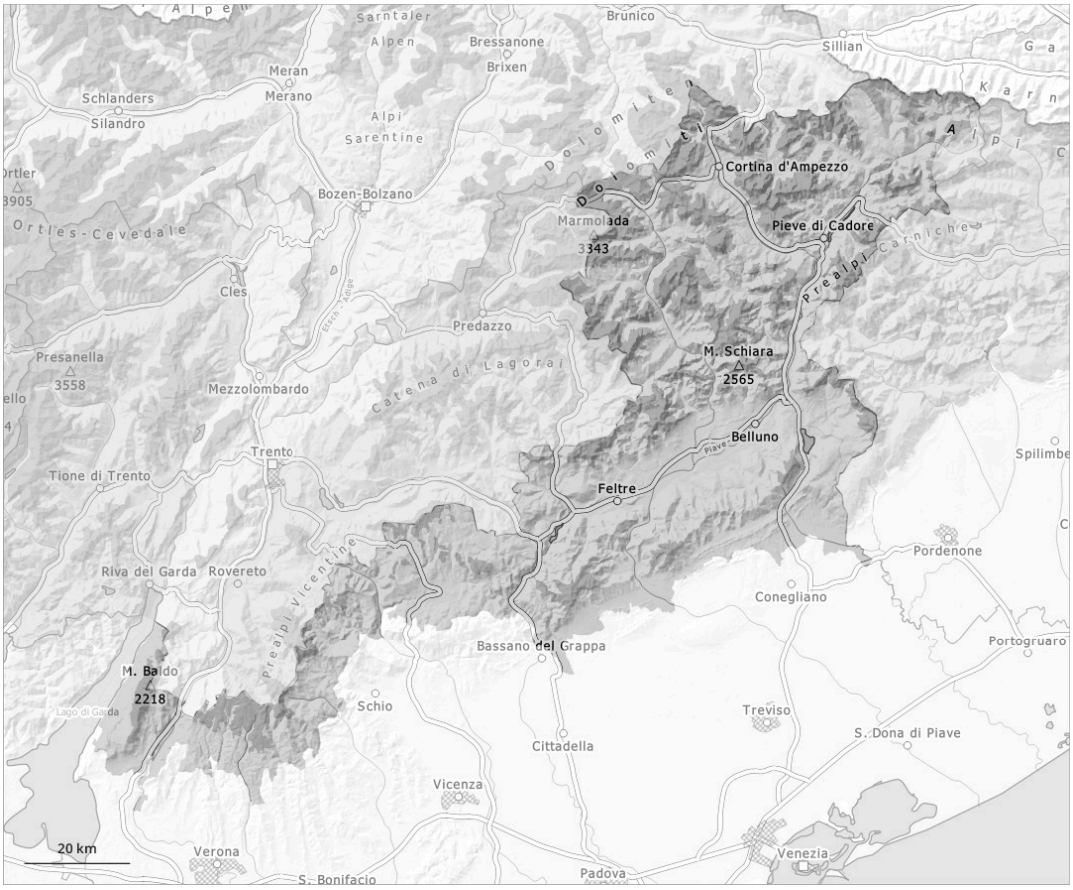

1	2	3	4	5
faible	limité	marqué	fort	très fort

Degré de danger 3 - Marqué

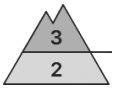

Limite de la forêt

Tendance: danger d'avalanche constant
leDimanche 29 03 2026

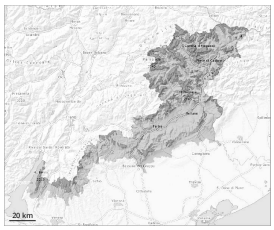

Neige soufflée
(Neige ventée)

Limite de la forêt

Neige
ancienne
(Sous-couche
fragile
persistante)

1800m

En dehors des pistes situation avalancheuse partiellement délicate en général.

Des accumulations de neige soufflée en partie grandes se sont formées avec la neige fraîche et le vent de nord tempétueux à toutes les expositions. Celles-ci peuvent être déclenchées très facilement au-dessus de la limite de la forêt. Des avalanches peuvent se déclencher dans les couches proches de la surface. Des avalanches peuvent aussi par endroits se déclencher dans les couches du manteau neigeux proches du sol, notamment sur les pentes exposées à l'ouest, au nord et à l'est au-dessus d'environ 1800 m.
Des bruits sourds et des fissures lors du passage sur le manteau neigeux sont des signes d'alarme qui attirent l'attention sur le danger.

En outre, des avalanches de neige meuble sèche sont possibles, notamment sur les pentes très raides en cas de rayonnement solaire.

La retenue est de mise pour cette première journée ensoleillée.

Manteau neigeux

Modèles de danger md.6: froid, neige légère et vent | md.1: sous-couche fragile persistante

Depuis mercredi il est tombé de 10 à 25 cm de neige, localement plus.
Le vent a soufflé partiellement en ouragan. Le vent a transporté intensivement la neige fraîche et la neige ancienne.

La neige fraîche et la neige soufflée reposent sur une surface de neige ancienne défavorable au-dessus de la limite de la forêt. Le manteau neigeux ancien est faible, notamment sur les pentes exposées à l'ouest, au nord et à l'est au-dessus d'environ 1800 m et sur les pentes exposées au sud en altitude.

Tendance

Danger d'avalanches toujours marqué. Les avalanches peuvent par endroits être déclenchées facilement.