ICGC Institut Cartogràfic i Geològic de Catalunya

Servei Meteorològic de Catalunya meteo.cat

# Boletín de peligro de aludes para el Pirineo de Catalunya
# Del 27/03/2026 al 28/03/2026

(Válido fuera pistas de esquí y zonas no controladas)

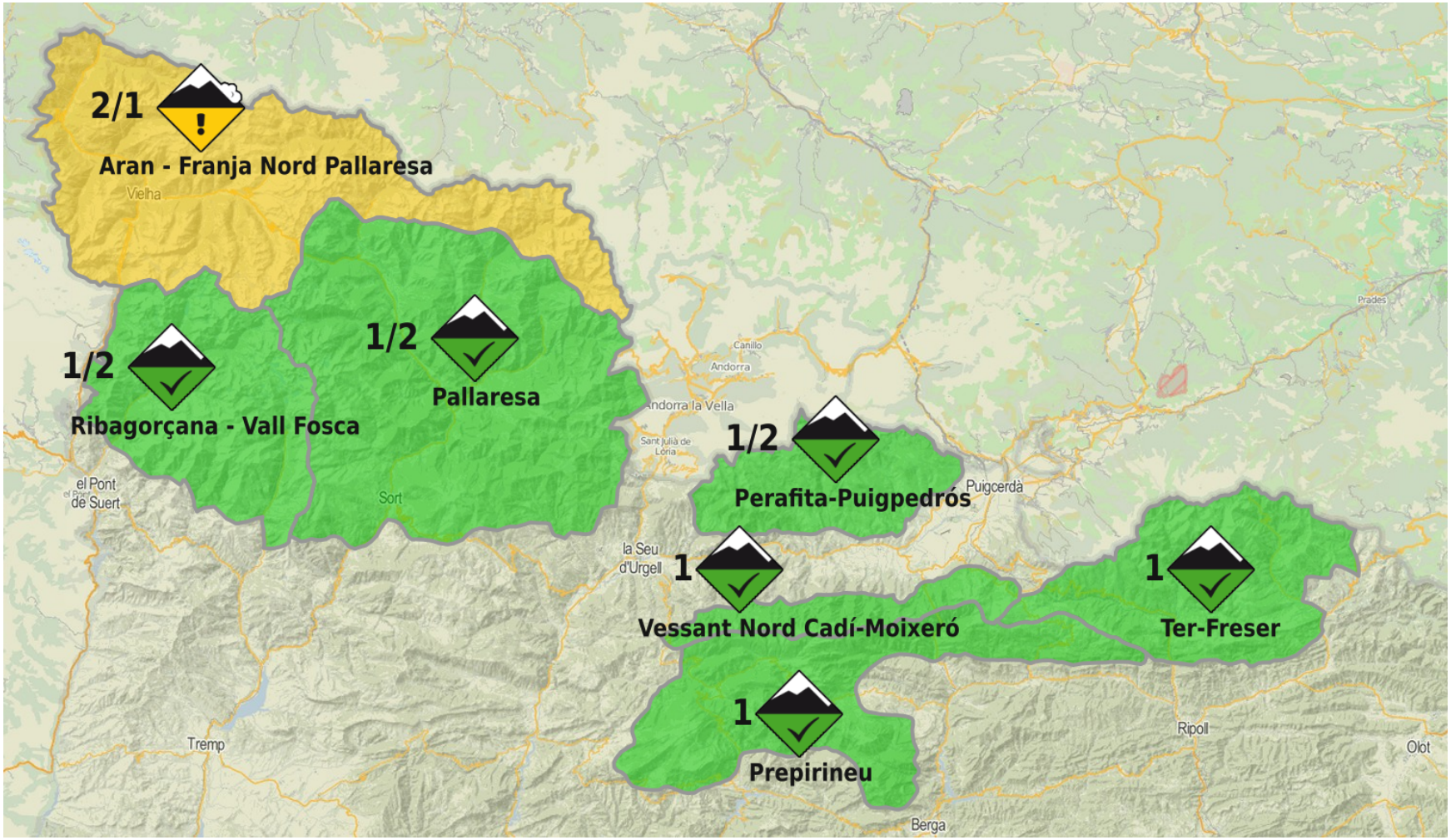


| | | | | |
|---|---|---|---|---|
| 5 MUY FUERTE | 4 FUERTE | 3 NOTABLE | 2 LIMITADO | 1 DÉBIL |

ICGC Institut Cartogràfic i Geològic de Catalunya

Servei Meteorològic de Catalunya

# Boletín de peligro de aludes Aran - Franja Nord Pallaresa Del 27/03/2026 al 28/03/2026

(Válido fuera pistas de esquí y zonas no controladas)

LIMITADO (2), por encima de 2.200 m.
DÉBIL (1), por debajo.

## Situación primaria

**Nieve venteada**

**Distribución**

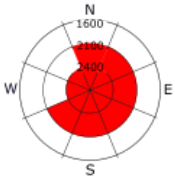


**Tamaño**

**Origen**

**Tendencia**

## Situación secundaria

**Capas débiles persistentes**

**Distribución**

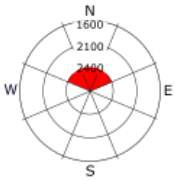


**Tamaño**

**Origen**

**Tendencia**

**Estado del manto nivoso**

Se han registrado aludes pequeños accidentales de placa de viento.
Ha continuado el transporte de nieve por el viento fuerte de N y NW, tanto de la nieve reciente como de la nieve seca superficial del manto presente sobre todo en umbrías de cota alta. Se han formado nuevas placas de pequeño tamaño, y generalmente locales, por encima del límite del bosque, bajo collados y crestas, y sectores más resguardados, en cualquier orientación pero preferentemente en S y E. Estas placas pueden mostrarse sensibles y ceder al paso de una persona provocando aludes accidentales de tamaño 1, pequeño. A partir del sábado por la noche, con las nevadas y viento fuerte, algunas placas podrían llegar a tamaño 2, mediano, y aparecer problemas de nieve reciente.
En umbrías altas, por encima de unos 2.300 m, es posible todavía encontrar alguna placa antigua que descanse sobre niveles débiles, inestables, y por sobrecarga fuerte pueda romper y caer, generando aludes que pueden ser de tamaño pequeño o medio.

**Distribución del manto nivoso**

Hay nieve por encima de unos 1.700 m en umbrías y 2.000 m en solanas. Los espesores a unos 2.200 m son ligeramente superiores a los normales en la Franja Nord de la Pallaresa y en la mitad sur de Arán, donde rondan los 180-220 cm. En la mitad norte de Arán son los normales por estas fechas con unos 120-140 cm de espesor total.

**Tendencia para las próximas 48-72h**

Las nevadas previstas con viento formarán nuevas placas y se añadirá el problema de nieve reciente. Peligro: en AUMENTO.

**El próximo boletín será emitido el día 2026-03-28**

| | | | | |
|---|---|---|---|---|
| 5 MUY FUERTE | 4 FUERTE | 3 NOTABLE | 2 LIMITADO | 1 DÉBIL |

EAWS EUROPEAN AVALANCHE WARNING SERVICES

ICGC Institut Cartogràfic i Geològic de Catalunya

meteo.cat Servei Meteorològic de Catalunya

# Boletín de peligro de aludes Ribagorçana - Vall Fosca Del 27/03/2026 al 28/03/2026

(Válido fuera pistas de esquí y zonas no controladas)

DÉBIL (1) hasta el atardecer, aumentando a LIMITADO (2) a partir de la noche.

## Situación primaria

**Nieve venteada**

**Distribución**

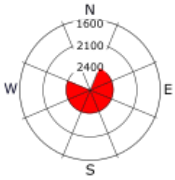


**Tamaño**

**Origen**

**Tendencia**

## Situación secundaria

**Capas débiles persistentes**

**Distribución**

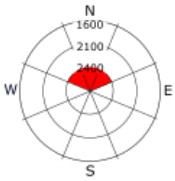


**Tamaño**

**Origen**

**Tendencia**

**Estado del manto nivoso**

El viento fuerte de N y NW de los últimos días ha provocado transporte de nieve efectivo, aunque limitado por la poca disponibilidad de nieve movilizable, que se encuentra restringida a umbrías de cota alta. Las placas más recientes pueden continuar activas, y a partir del sábado por la noche se formarán nuevas por las nevadas moderadas y viento fuerte de N y NW. Se localizan en cota alta, principalmente en S y E, menos probables y frecuentes en otras orientaciones, y bajo collados y crestas y sectores resguardados. Las placas podrán ser sensibles y ceder al paso de una persona provocando aludes de tamaño 1, pequeño. A partir del sábado por la noche, con las nevadas y viento fuerte, las placas podrán alcanzar tamaño medio.
En umbrías muy altas es posible todavía encontrar alguna placa antigua que descanse sobre niveles débiles y por sobrecarga fuerte pueda romper y caer, generando aludes de pequeño tamaño en general.
En solanas encontramos un manto endurecido y resbaladizo.

**Distribución del manto nivoso**

Hay nieve en el suelo a 1.700 m en N, y a unos 2.100 m en S de forma discontinua, pasando a ser continua a partir de unos 2.300 m. Los grosores alcanzan los 100-120 cm a unos 2.200 m. Estos valores se acercan a los normales para la época.

**Tendencia para las próximas 48-72h**

Con el nuevo episodio de nieve y viento se formarán nuevas placas de viento. Peligro: en AUMENTO.

**El próximo boletín será emitido el día 2026-03-28**

| | | | | |
|---|---|---|---|---|
| 5 MUY FUERTE | 4 FUERTE | 3 NOTABLE | 2 LIMITADO | 1 DÉBIL |

EAWS EUROPEAN AVALANCHE WARNING SERVICES

ICGC Institut Cartogràfic i Geològic de Catalunya

Servei Meteorològic de Catalunya meteo.cat

# Boletín de peligro de aludes Pallaresa
# Del 27/03/2026 al 28/03/2026

(Válido fuera pistas de esquí y zonas no controladas)

DÉBIL (1) hasta el atardecer, aumentando a LIMITADO (2) a partir de la noche.

## Situación primaria

**Nieve venteada**

**Distribución**

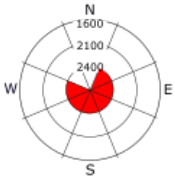


**Tamaño**

**Origen**

**Tendencia**

## Situación secundaria

**Capas débiles persistentes**

**Distribución**

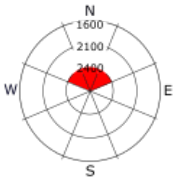


**Tamaño**

**Origen**

**Tendencia**

**Estado del manto nivoso**

El viento fuerte de N y NW de los últimos días ha provocado transporte de nieve efectivo, aunque limitado por la poca disponibilidad de nieve movilizable, que se encuentra restringida a umbrías de cota alta. Las placas más recientes pueden continuar activas, y a partir del sábado por la noche se formarán nuevas por las nevadas moderadas y viento fuerte de N y NW. Se localizan en cota alta, principalmente en S y E, menos probables y frecuentes en otras orientaciones, y bajo collados y crestas y sectores resguardados. Las placas podrán ser sensibles y ceder al paso de una persona provocando aludes de tamaño 1, pequeño. A partir del sábado por la noche, con las nevadas y viento fuerte, las placas podrán alcanzar tamaño medio.
En umbrías muy altas es posible todavía encontrar alguna placa antigua que descanse sobre niveles débiles y por sobrecarga fuerte pueda romper y caer, generando aludes de pequeño tamaño en general. En solanas encontramos un manto endurecido y resbaladizo.

**Distribución del manto nivoso**

Hay nieve en el suelo a 1.700 m en N, y a unos 2.100 m en S de forma discontinua, pasando a ser continua a partir de unos 2.300 m. Los espesores alcanzan los 110-150 cm en cotas medias, puntualmente más, variable según los efectos del viento.

**Tendencia para las próximas 48-72h**

Con el nuevo episodio de nieve y viento se formarán nuevas placas de viento. Peligro: en AUMENTO.

**El próximo boletín será emitido el día 2026-03-28**

| | | | | |
|---|---|---|---|---|
| 5 MUY FUERTE | 4 FUERTE | 3 NOTABLE | 2 LIMITADO | 1 DÉBIL |

EAWS EUROPEAN AVALANCHE WARNING SERVICES

ICGC Institut Cartogràfic i Geològic de Catalunya

Servei Meteorològic de Catalunya meteo.cat

# Boletín de peligro de aludes Perafita-Puigpedrós Del 27/03/2026 al 28/03/2026

(Válido fuera pistas de esquí y zonas no controladas)

DÉBIL (1) hasta el atardecer, aumentando a LIMITADO (2) a partir de la noche.

**Situación primaria**

**Nieve venteada**

**Distribución**

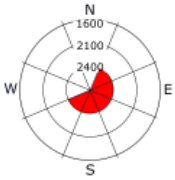


**Tamaño**

**Origen**

**Tendencia**

**Estado del manto nivoso**

En los últimos días se ha observado transporte de nieve a cotas altas por el fuerte viento de N y NW, aunque muy limitado debido a la baja disponibilidad de nieve movilizable, restringida a umbrías de cota alta. Las placas más recientes pueden continuar activas, y a partir del sábado por la noche se formarán nuevas por las nevadas débiles y viento fuerte. Se localizan en cota alta, principalmente en S y E, menos probables y frecuentes en otras orientaciones, y bajo collados y crestas y sectores resguardados. Estas placas son locales y pequeñas, y reactivas al paso de una persona, con las que se pueden desprender y generar aludes de pequeño tamaño, sin capacidad para enterrarla. A partir del sábado por la noche, con las nuevas precipitaciones y viento fuerte, las placas podrán incrementarse y llegar a tamaño 2, medio.

En solanas, el manto se encuentra bastante endurecido y encostrado en general, sobre todo por la mañana, y hay que tener cuidado con los resbalones.

**Distribución del manto nivoso**

Hay nieve por encima de unos 1.900 m, discontinua hasta 2.200 m en solanas. Es esquiable a partir de unos 2.000 m en N. Los espesores, aunque irregulares, rondan los 70-100 cm en umbrías, a 2.300 m. Son grosores por encima de los habituales en esta época.

**Tendencia para las próximas 48-72h**

Con el nuevo episodio de nieve y viento se formarán nuevas placas de viento. Peligro: en AUMENTO.

**El próximo boletín será emitido el día 2026-03-28**

| | | | | |
|---|---|---|---|---|
| 5 MUY FUERTE | 4 FUERTE | 3 NOTABLE | 2 LIMITADO | 1 DÉBIL |

EAWS EUROPEAN AVALANCHE WARNING SERVICES

ICGC Institut Cartogràfic i Geològic de Catalunya

Servei Meteorològic de Catalunya

# Boletín de peligro de aludes
# Vessant Nord Cadí-Moixeró
# Del 27/03/2026 al 28/03/2026

(Válido fuera pistas de esquí y zonas no controladas)

DÉBIL (1)

## Situación primaria

**Nieve venteada**

**Distribución**

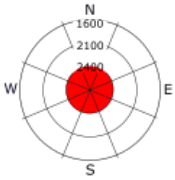


**Tamaño**

**Origen**

**Tendencia**

**Estado del manto nivoso**

El viento fuerte de N y NW de los últimos días ha provocado transporte de nieve efectivo, aunque limitado por la poca disponibilidad de nieve movilizable, que se encuentra restringida a umbrías de cota alta. Con estas condiciones se han formado placas de viento que pueden permanecer sensibles, y a partir del sábado por la noche se formarán nuevas por las nevadas débiles y viento fuerte. Se localizan en cota alta, presentes en cualquier orientación pero principalmente en S y E, menos probables en el resto, y bajo collados y crestas y sectores resguardados, así como en lo alto de las canales. Estas placas son locales y pequeñas, y reactivas al paso de una persona, donde pueden ceder y generar aludes de pequeño tamaño, sin capacidad para enterrarla, pero sí derribarla.

En solanas, el manto se encuentra bastante endurecido y encostrado en general, sobre todo por la mañana, y hay que tener cuidado con los resbalones.

**Distribución del manto nivoso**

En umbrías hay presencia discontinua de nieve por encima de unos 1.700 m y es esquiable por encima de unos 1.900 m. Los grosores están alrededor de 160-180 cm a 2.200 m. Estos valores son muy excedentarios para la época del año.

**Tendencia para las próximas 48-72h**

Con el nuevo episodio de nieve y viento se formarán nuevas placas de viento. Peligro: en AUMENTO.

**El próximo boletín será emitido el día 2026-03-28**

| | | | | |
|---|---|---|---|---|
| 5 MUY FUERTE | 4 FUERTE | 3 NOTABLE | 2 LIMITADO | 1 DÉBIL |

EAWS EUROPEAN AVALANCHE WARNING SERVICES

ICGC Institut Cartogràfic i Geològic de Catalunya

Servei Meteorològic de Catalunya

# Boletín de peligro de aludes Prepirineu
# Del 27/03/2026 al 28/03/2026

(Válido fuera pistas de esquí y zonas no controladas)

DÉBIL (1).

**Situación primaria**

**Nieve venteada**

**Distribución**

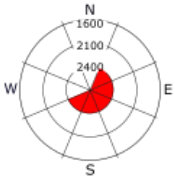


**Tamaño**

**Origen**

**Tendencia**

**Estado del manto nivoso**

Ha continuado el viento fuerte o muy fuerte en cotas altas del sector, de NW y N, que ha podido formar alguna nueva placa de viento, local y pequeña por la limitada disponibilidad de nieve movilizable, restringida a umbrías de cota alta.

Las placas de estos últimos días y las más recientes pueden continuar activas, y a partir del sábado por la noche se formarán nuevas por las nevadas débiles y viento fuerte. Se localizan en cota alta, principalmente en S y E, menos probables y frecuentes en otras orientaciones, y bajo collados y crestas y sectores resguardados. Estas placas, locales y pequeñas, pueden ser reactivas al paso de una persona, desprenderse y generar aludes de pequeño tamaño, sin capacidad para enterrarla.

En solanas, el manto se encuentra bastante endurecido y encostrado en general, sobre todo por la mañana, y hay que tener cuidado con los resbalones.

**Distribución del manto nivoso**

En umbrías hay nieve por encima de unos 1.700 m. En solanas la nieve está presente por encima de unos 1.900 m, discontinua. Los espesores, aunque irregulares, rondan los 90-120 cm a 2.300 m.

**Tendencia para las próximas 48-72h**

Con el nuevo episodio de nieve y viento se formarán nuevas placas de viento. Peligro: en AUMENTO.

**El próximo boletín será emitido el día 2026-03-28**

| | | | | |
|---|---|---|---|---|
| 5 MUY FUERTE | 4 FUERTE | 3 NOTABLE | 2 LIMITADO | 1 DÉBIL |

EAWS EUROPEAN AVALANCHE WARNING SERVICES

ICGC Institut Cartogràfic i Geològic de Catalunya

Servei Meteorològic de Catalunya

# Boletín de peligro de aludes Ter-Freser Del 27/03/2026 al 28/03/2026

(Válido fuera pistas de esquí y zonas no controladas)

DÉBIL (1)

## Situación primaria

**Nieve venteada**

**Distribución**

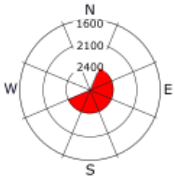


**Tamaño**

**Origen**

**Tendencia**

**Estado del manto nivoso**

El viernes ha continuado el transporte de nieve en cotas altas por el fuerte viento de N y NW, aunque muy limitado debido a la baja disponibilidad de nieve movilizable, restringida a umbrías de cota alta.

Las placas de estos últimos días y las más recientes pueden continuar activas, y a partir del sábado por la noche se formarán nuevas por las nevadas débiles y viento fuerte. Se localizan en cota alta, principalmente en S y E, menos probables y frecuentes en otras orientaciones, y bajo collados y crestas y sectores resguardados. Estas placas son locales y pequeñas, y reactivas al paso de una persona, con las que se pueden desprender y generar aludes de pequeño tamaño, sin capacidad para enterrarla.

En solanas, el manto se encuentra bastante endurecido y encostrado en general, sobre todo por la mañana, y hay que tener cuidado con los resbalones.

**Distribución del manto nivoso**

Hay nieve en el suelo por encima de unos 1.700 m. El manto es esquiable a umbrías a partir de unos 1.800 m. Los grosores son muy excedentarios para la época del año y en lugares no afectados por el viento oscilan entre 70-90 cm a unos 2.000 my más de 150 cm por encima de 2.400 m.

**Tendencia para las próximas 48-72h**

Las placas de viento continuarán sensibles y formarán nuevas. Peligro: en AUMENTO.

**El próximo boletín será emitido el día 2026-03-28**

| | | | | |
|---|---|---|---|---|
| 5 MUY FUERTE | 4 FUERTE | 3 NOTABLE | 2 LIMITADO | 1 DÉBIL |

EAWS EUROPEAN AVALANCHE WARNING SERVICES