# Bulletin d'estimation du risque d'avalanche
(valable en dehors des pistes balisées et ouvertes)

# MASSIF : Devoluy

Rédigé le vendredi 27 mars 2026 à 15h

## Estimation des risques pour le : SAMEDI 28 MARS

**PLAQUES EN PLACE DANS LA NEIGE RÉCENTE, FORMÉES JEUDI PAR LE VENT DE NORD**

2

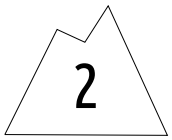


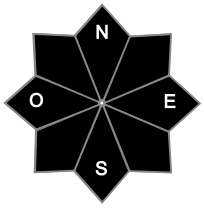


Indice de risque limité.

**Départs spontanés :** peu probables.

**Déclenchements provoqués :** instabilités dans la neige récente ventée.

Indices de risque : 5 très fort - 4 fort - 3 marqué - 2 limité - 1 faible -- En noir : les pentes les plus dangereuses

## Stabilité du manteau neigeux

**Situation avalancheuse typique :** neige ventée

**Déclenchements provoqués :** instabilités en place dans la neige fraiche ventée, plutôt à partir de 1500/1600 m en versants froids, et 2000/2200 m dans les versants ensoleillés du sud du massif. Formées jeudi par le vent tempétueux de nord, ces instabilités restent possibles en toutes orientations, même loin des crêtes, et sont encore déclenchables par un seul skieur. Plaques généralement en neige dure faciles à identifier, générant des avalanches de taille petite à moyenne (taille 1 à 2).

**Départs spontanés :** Peu probables, quelques boulettes au soleil en journée.

## Qualité de la neige

**L'enneigement** est excédentaire pour une fin mars.

**Limite d'enneigement skiable** : dès 1200/1300 m en ubacs favorables (terrains herbeux, pistes forestières), 1700/1800 m en adrets pas trop raides.

**État de la neige de surface** : neige récente fortement travaillée par le vent. Nombreuses congères dans les pentes. Sur les crêtes, d'épaisses corniches côtoient des zones dégarnies voire pelées par le vent.
En versant sud, neige croutée sous 2200/2400, s'humidifiant en journée.

## Aperçu météo pour le samedi 28 mars

| | nuit | matin | après-midi | soir |
|---|---|---|---|---|
| | | | | |
| Temps sec, se voilant progressivement en cours de journée. | | | | |
| **Pluie-Neige** | | | | |
| **Iso 0 °C** | 1 400 m | 1 800 m | 1 900 m | 1 600 m |
| **Vent 2000 m** | ↓ 25 km/h | ↓ 35 km/h | ↓ 65 km/h | ↓ 60 km/h |
| **Vent 3000 m** | ↙ 35 km/h | ↓ 55 km/h | ↓ 65 km/h | ↓ 75 km/h |

## Épaisseur de neige hors-piste

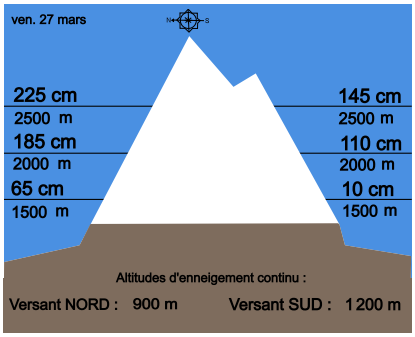


## Précipitations à 1800 m

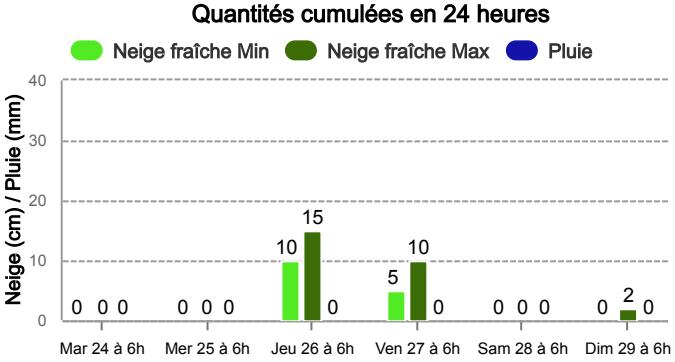


## Tendance du dimanche 29 mars

2

**Indice de risque limité**

Plaques résiduelles en places dans la neige récentes.

Pour consulter la vigilance en cours, veuillez vous rendre sur le site https://vigilance.meteofrance.fr/fr

Météo-France - 73 avenue de Paris, 94165 Saint-Mandé cedex - Contact : contact@meteo.fr

Rédigé par Météo-France avec la contribution des observateurs du réseau nivo-météorologiques. Partenariat : ANMSM (Maires de Stations de Montagne), DSF (Domaines Skiables de France), ADSP (Directeurs de Pistes et de la Sécurité des Stations de Sports d'Hiver) et autres acteurs de la montagne.

Bulletin neige & avalanches par téléphone au **0 892 68 10 20** Service 0,35 € / min + prix appel

RÉPUBLIQUE FRANÇAISE
*Liberté Égalité Fraternité*

METEO FRANCE
À VOS CÔTÉS, DANS UN CLIMAT QUI CHANGE

# Bulletin d'estimation du risque d'avalanche

## (valable en dehors des pistes balisées et ouvertes)

# MASSIF : Devoluy

Rédigé le vendredi 27 mars 2026 à 15h

## Conditions nivo-météo des 7 derniers jours

| | sam. 21/03 | | | | dim. 22/03 | | | | lun. 23/03 | | | | mar. 24/03 | | | | mer. 25/03 | | | | jeu. 26/03 | | | | ven. 27/03 | | | |
|---|---|---|---|---|---|---|---|---|---|---|---|---|---|---|---|---|---|---|---|---|---|---|---|---|---|---|---|---|
| | 03h | 09h | 15h | 21h | 03h | 09h | 15h | 21h | 03h | 09h | 15h | 21h | 03h | 09h | 15h | 21h | 03h | 09h | 15h | 21h | 03h | 09h | 15h | 21h | 03h | 09h | 15h | 21h |
| Météo | | | | | | | | | | | | | | | | | | | | | | | | | | | | |
| Vent (km/h) | 15 | 15 | 15 | 15 | 15 | 25 | 30 | 30 | 20 | 15 | 20 | 15 | 15 | 15 | 20 | 20 | 20 | 50 | 70 | 90 | 100 | 90 | 80 | 70 | 80 | 80 | 30 | 15 |
| à 3000m | | | | | | | | | | | | | | | | | | | | | | | | | | | | |
| Vent (km/h) | 5 | 10 | 15 | 15 | 15 | 20 | 25 | 25 | 15 | 15 | 20 | 15 | 10 | 10 | 10 | 5 | 10 | 20 | 55 | 80 | 90 | 80 | 70 | 70 | 60 | 60 | 20 | 20 |
| à 2000m | | | | | | | | | | | | | | | | | | | | | | | | | | | | |

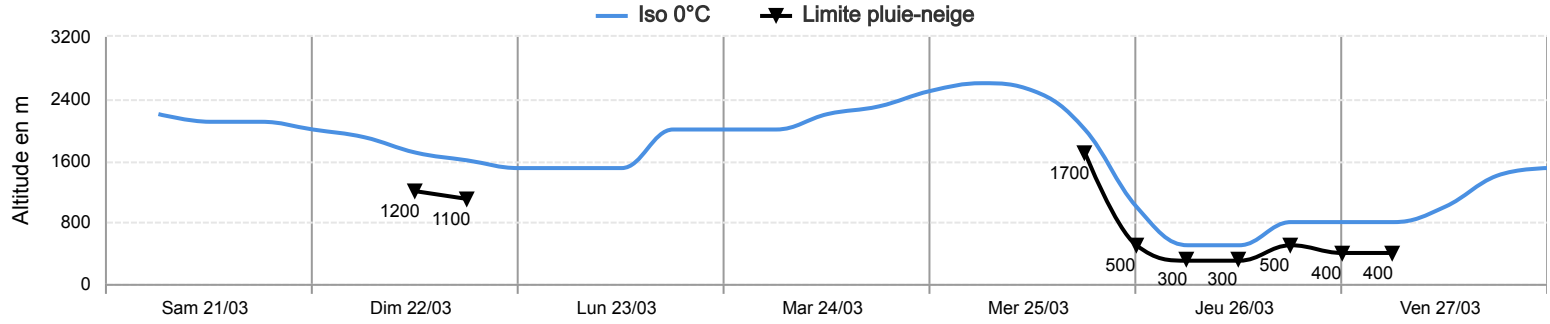


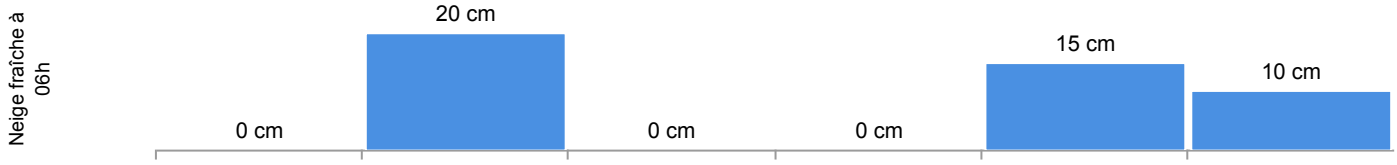


| Risque d'avalanche | sam. 21/03 | dim. 22/03 | lun. 23/03 | mar. 24/03 | mer. 25/03 | jeu. 26/03 | ven. 27/03 |
|---|---|---|---|---|---|---|---|
| | 2 | 2 | 2 | 2 | 2 | 3 | 3 |

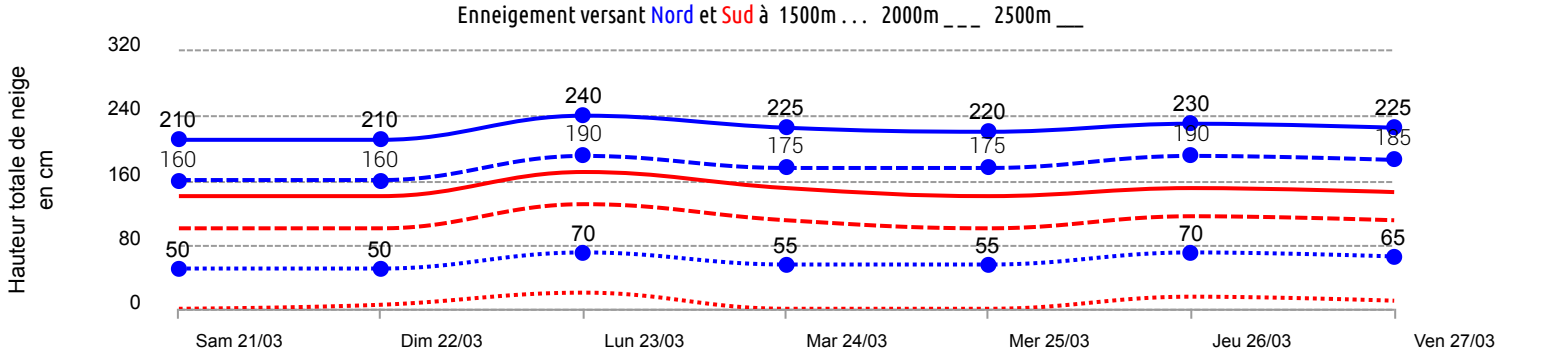


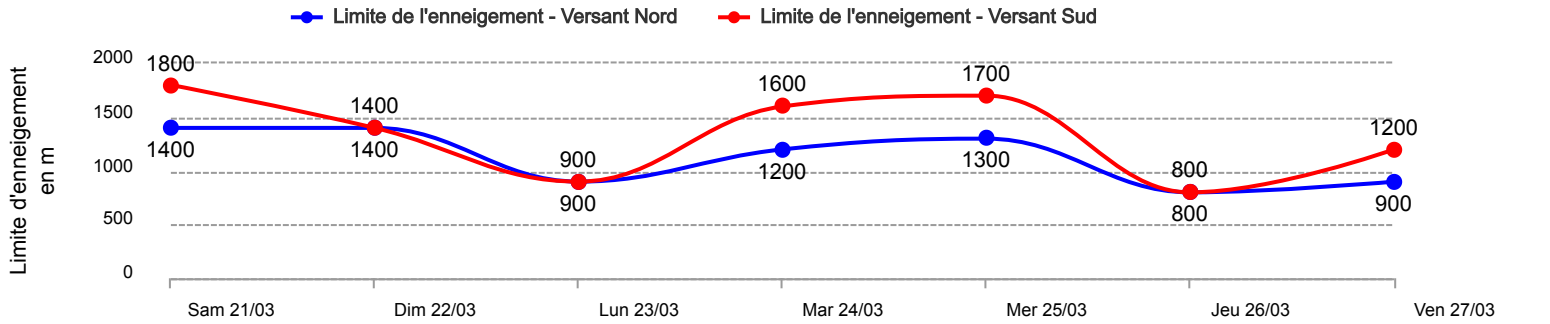


Pour consulter la vigilance en cours, veuillez vous rendre sur le site https://vigilance.meteofrance.fr/fr


Météo-France - 73 avenue de Paris, 94165 Saint-Mandé cedex - Contact : contact@meteo.fr


Bulletin neige & avalanches par téléphone au

**0 892 68 10 20** Service 0,35 € / min + prix appel


Rédigé par Météo-France avec la contribution des observateurs du réseau nivo-météorologiques. Partenariat : ANMSM (Maires de Stations de Montagne), DSF (Domaines Skiables de France), ADSP (Directeurs de Pistes et de la Sécurité des Stations de Sports d'Hiver) et autres acteurs de la montagne.