Bulletin d'estimation du risque d'avalanche
(valable en dehors des pistes balisées et ouvertes)

MASSIF : Queyras

Rédigé le vendredi 27 mars 2026 à 15h

Estimation des risques pour le : SAMEDI 28 MARS

PLAQUES EN PLACE DANS LA NEIGE RÉCENTE, FORMÉES JEUDI PAR LE VENT DE NORD

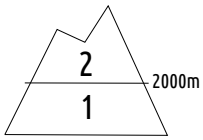

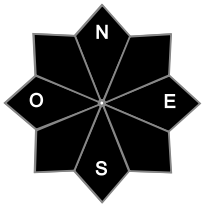

Au-dessus de 2000m indice de risque limité, plus bas indice faible.

Départs spontanés : peu probables.

Déclenchements provoqués : instabilités superficielles dans la neige ventée, plus épaisses autour de Ceillac.

Indices de risque : 5 très fort - 4 fort - 3 marqué - 2 limité - 1 faible -- En noir : les pentes les plus dangereuses

Stabilité du manteau neigeux

Situation avalancheuse typique : neige ventée

Déclenchements provoqués : instabilités en place dans la neige fraiche ventée, plutôt au-dessus de 2000 m en versants froids, et 2200/2400 m en versants ensoleillés. Formées jeudi par le vent tempétueux de nord, ces instabilités restent possibles en toutes orientations, même loin des crêtes, et sont encore déclenchables par un seul skieur. Plaques généralement en neige dure faciles à identifier, générant des avalanches de petite taille (taille 1), voir moyenne (taille 2) autour de Ceillac.

Départs spontanés : Peu probables, quelques boulettes au soleil en journée.

Qualité de la neige

L'enneigement est proche des normales pour une fin mars.
Hauteurs de neige observées : 152 cm en versant nord du col Izoard à 2300 m, 144 cm au-dessus de St Véran à 2700 m, 92 cm à la Nivôse du Col Agnel à 2630 m

Limite d'enneigement skiable : au plus bas à 1400/1500 m en ubacs bien protégés ou sur pistes forestières, plutôt 2000/2100 m en adrets.

État de la neige de surface : neige fraiche fortement travaillée par le vent, mais localement encore légère dans les secteurs bien abrités. Crêtes parfois décapées. En versant sud, neige croutée sous 2200/2400, s'humidifiant en journée.

Aperçu météo pour le samedi 28 mars

	nuit	matin	après-midi	soir
	Temps sec, se voilant progressivement en cours de journée.			
Pluie-Neige				
Iso 0 °C	1 800 m	2 500 m	2 500 m	1 800 m
Vent 2000 m	→ 10 km/h	↓ 15 km/h	↓ 25 km/h	↓ 20 km/h
Vent 3000 m	→ 15 km/h	↘ 20 km/h	↘ 30 km/h	↘ 25 km/h

Épaisseur de neige hors-piste

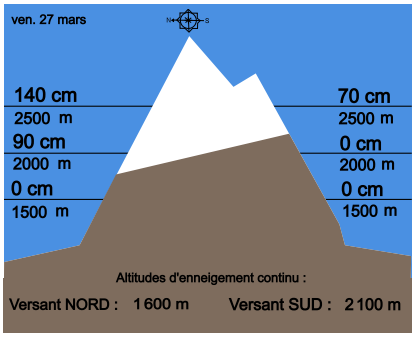

Précipitations à 1800 m

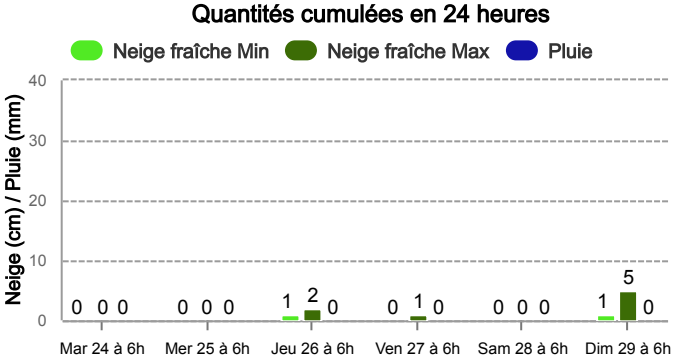

Tendance du dimanche 29 mars

Indice de risque limité

Petite plaques en formation avec les nouvelles chutes de neige faibles.

Pour consulter la vigilance en cours, veuillez vous rendre sur le site https://vigilance.meteofrance.fr/fr

Météo-France - 73 avenue de Paris, 94165 Saint-Mandé cedex - Contact : contact@meteo.fr

Rédigé par Météo-France avec la contribution des observateurs du réseau nivo-météorologiques. Partenariat : ANMSM (Maires de Stations de Montagne), DSF (Domaines Skiables de France), ADSP (Directeurs de Pistes et de la Sécurité des Stations de Sports d'Hiver) et autres acteurs de la montagne.

Bulletin neige & avalanches par téléphone au **0 892 68 10 20** Service 0,35 € / min + prix appel

RÉPUBLIQUE FRANÇAISE
Liberté Égalité Fraternité

METEO FRANCE
À VOS CÔTÉS, DANS UN CLIMAT QUI CHANGE

Bulletin d'estimation du risque d'avalanche

(valable en dehors des pistes balisées et ouvertes)

MASSIF : Queyras

Rédigé le vendredi 27 mars 2026 à 15h

Conditions nivo-météo des 7 derniers jours

	sam. 21/03				dim. 22/03				lun. 23/03				mar. 24/03				mer. 25/03				jeu. 26/03				ven. 27/03			
	03h	09h	15h	21h	03h	09h	15h	21h	03h	09h	15h	21h	03h	09h	15h	21h	03h	09h	15h	21h	03h	09h	15h	21h	03h	09h	15h	21h
Météo																												
Vent (km/h)	15	15	15	15	20	30	40	35	25	20	20	15	15	10	15	10	25	40	70	80	85	75	65	60	50	20	10	10
à 3000m																												
Vent (km/h)	5	10	15	10	15	25	30	30	20	15	20	10	10	10	15	5	10	20	50	60	65	60	50	50	40	20	10	10
à 2000m																												

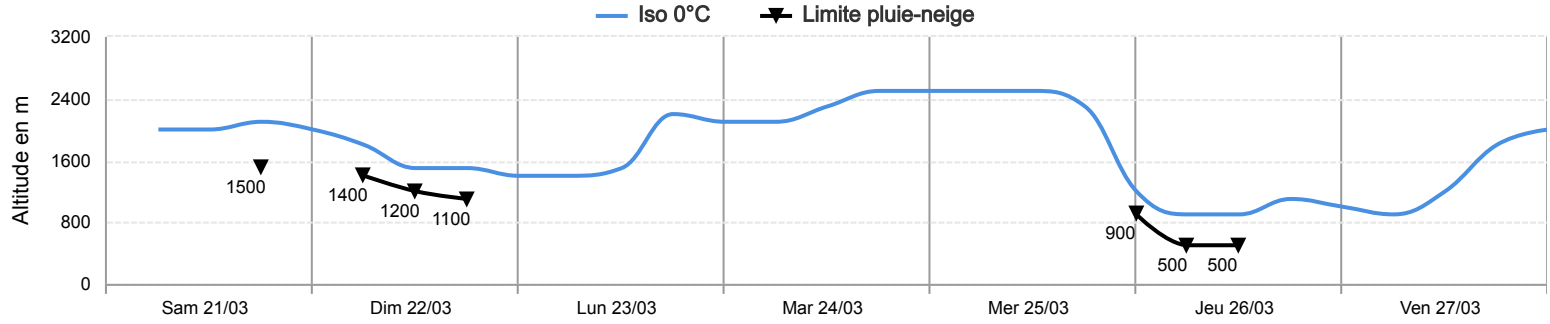

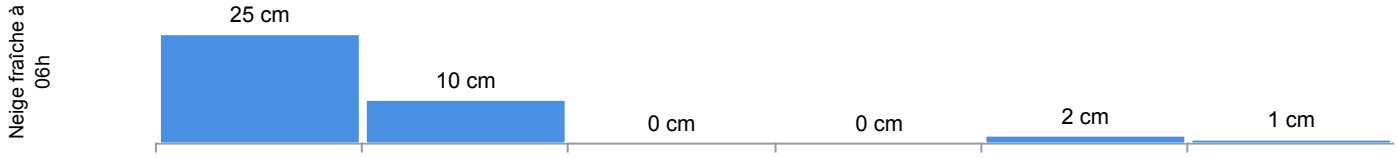

Risque d'avalanche	sam. 21/03	dim. 22/03	lun. 23/03	mar. 24/03	mer. 25/03	jeu. 26/03	ven. 27/03
	2	3	3	2	2	3	2

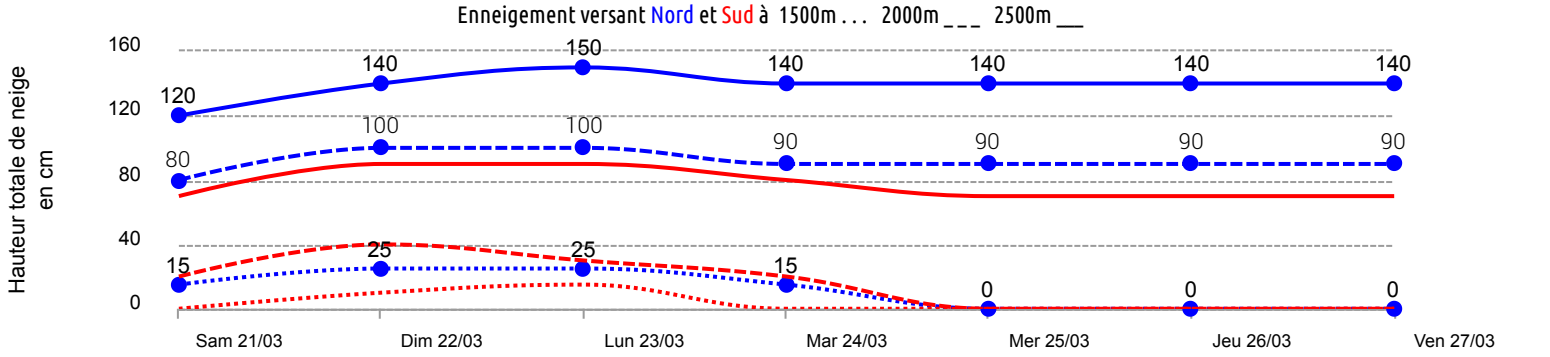

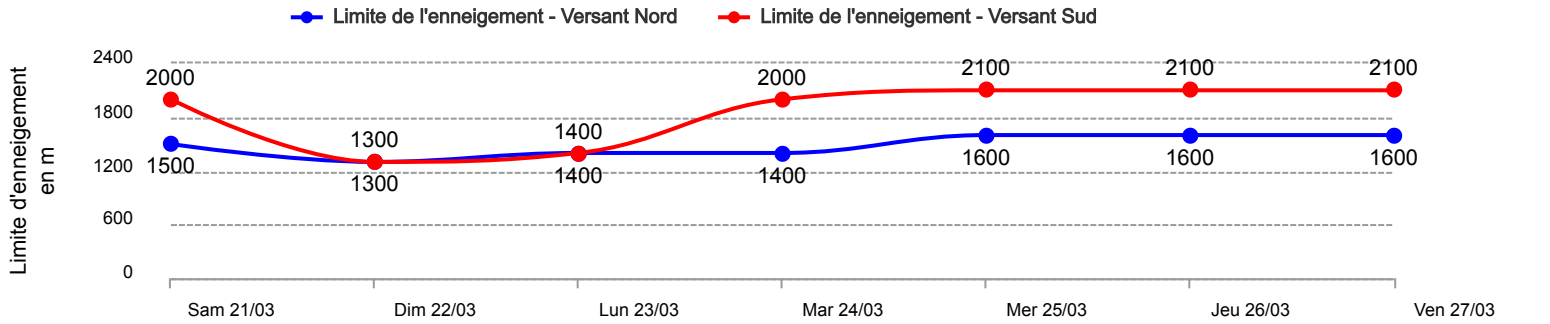

Pour consulter la vigilance en cours, veuillez vous rendre sur le site https://vigilance.meteofrance.fr/fr

Météo-France - 73 avenue de Paris, 94165 Saint-Mandé cedex - Contact : contact@meteo.fr

Rédigé par Météo-France avec la contribution des observateurs du réseau nivo-météorologiques. Partenariat : ANMSM (Maires de Stations de Montagne), DSF (Domaines Skiables de France), ADSP (Directeurs de Pistes et de la Sécurité des Stations de Sports d'Hiver) et autres acteurs de la montagne.

Bulletin neige & avalanches par téléphone au
0 892 68 10 20 Service 0,35 € / min + prix appel