Bulletin d'estimation du risque d'avalanche
(valable en dehors des pistes balisées et ouvertes)

MASSIF : Aure Louron

Rédigé le vendredi 27 mars 2026 à 16h

Estimation des risques pour le : SAMEDI 28 MARS

FINES PLAQUES À VENT EN ALTITUDE EN PLACE, D'AUTRES EN COURS DE FORMATION ET DE PLUS EN PLUS ÉPAISSES.

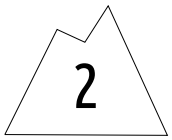

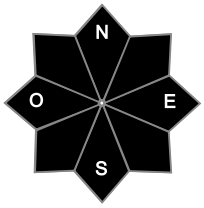

Plaques en formation

Indice de risque limité.

Départs spontanés : Départs ponctuels de plaques en altitude, sinon dans la neige récente et dans les chutes en cours.

Déclenchements provoqués : Plaques en place en altitude et en formation, couche fragile persistante.

Indices de risque : 5 très fort - 4 fort - 3 marqué - 2 limité - 1 faible -- En noir : les pentes les plus dangereuses

Stabilité du manteau neigeux

Situation avalancheuse typique : neige ventée couche fragile persistante

Déclenchements provoqués :
- **Au-dessus de 2000m**, de fines plaques à vent sont en place dans les pentes raides des versants allant du Nord-Ouest au Sud-Ouest en passant par l'Est, issues des chutes de neige précédentes. De nouvelles plaques à vent vont se former au fil des chutes de neige de l'après-midi et sous l'effet du vent de Nord à Nord-Ouest. Elles seront de plus en plus épaisses et facilement déclenchables par un simple skieur. Elles viennent se former sur les fines plaques des chutes de neige précédentes, elles-mêmes reposant sur une couche fragile persistante dans les pentes Nord raides au-dessus de 2200m, et au-dessus de 2400/2500m dans un secteur Nord-Ouest à Nord-Est plus large. Des cassures linéaires de tailles moyennes (taille 2) sont attendues par faible sollicitation, parfois des grandes (taille 3) dans les zones d'accumulation les plus importantes. Il n'est pas exclu de trouver des plaques dans les pentes raides des versants Ouest.
- **Sous 2000m**, un simple skieur peut déclencher en tous versants des départs ponctuels dans la neige récente ainsi que dans la neige tombant dans l'après-midi, des avalanches petites à moyennes (taille 1 à 2) sont généralement attendues, plus rarement des grandes (taille 3).

Départs spontanés :
- **Au-dessus de 2000m**, des départs ponctuels des plaques décrites ci-dessus restent possibles par surcharge par le vent, engendrant des avalanches moyennes (taille 2), parfois des grandes (taille 3) dans les zones d'accumulation les plus importantes.
- **Sous 2000m**, des départs ponctuels dans la neige tombant l'après-midi ainsi que dans la neige récente sont possibles en tous versants, engendrant des avalanches petites à moyennes (taille 1 à 2), plus rarement des grandes (taille 3).

Qualité de la neige

Enneigement : Correct pour la saison au-dessus de 2000m, mais restant assez maigre en versants exposés au vent d'ouest. Maigre et hétérogène plus bas le matin, débutant entre 1500 et 1600m en Nord, mais skiable à partir de 1700m, plutôt 1800 à 1900m en Sud. Des chutes de neige l'après-midi ainsi qu'en soirée samedi descendront la limite d'enneigement entre 1200 et 1500m en Nord, il restera skiable vers 1500m en Nord, 1700/1800m en Sud.

État de la neige :
Quelques centimètres de neige récente le matin, reposant sur un manteau dur et bien regelé sous 2000/2100m. La neige reste bien travaillée par le vent en gagnant en altitude. Des centimètres de neige supplémentaires à venir l'après-midi, de plus en plus importants au fil des chutes, de nouveau bien travaillées par le vent au-dessus de 2000m.

Aperçu météo pour le samedi 28 mars

	nuit	matin	après-midi	soir

Ciel se couvrant progressivement le matin. Des averses l'après-midi, s'intensifiant en soirée et la nuit suivante. Vent de Nord/Nord-Ouest fort.

	nuit	matin	après-midi	soir
Pluie-Neige			1 300 m	900 m
Iso 0 °C	1 300 m	1 600 m	1 600 m	1 100 m
Vent 1500 m	↓ 5 km/h	↓ 15 km/h	↓ 25 km/h	↓ 40 km/h
Vent 3000 m	↙ 55 km/h	↙ 35 km/h	↓ 50 km/h	↓ 75 km/h

Épaisseur de neige hors-piste

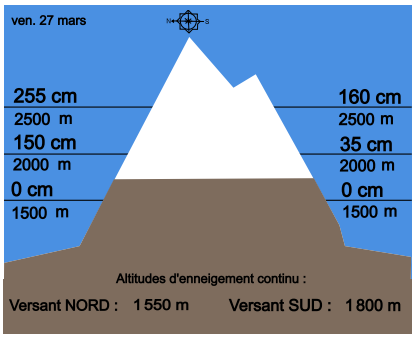

Précipitations à 1800 m

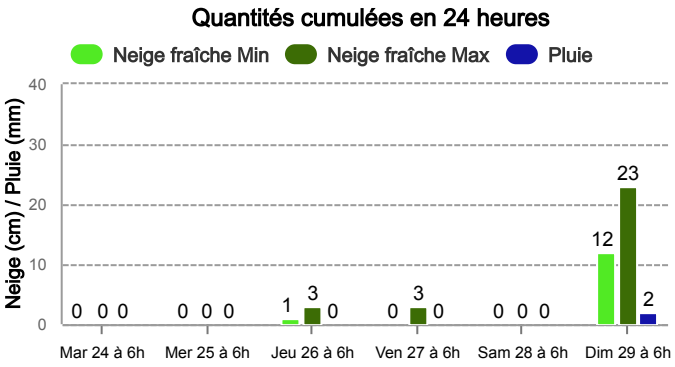

Tendance du dimanche 29 mars

Indice de risque marqué

Passage à un risque marqué avec la poursuite des averses neigeuses dans la nuit de samedi à dimanche ainsi que dimanche en journée. Du vent fort de Nord/Nord-Ouest dans la nuit de samedi à dimanche, plutôt de Nord à Nord-Est dimanche. Formation de plaques de plus en plus épaisses en altitude.

Pour consulter la vigilance en cours, veuillez vous rendre sur le site https://vigilance.meteofrance.fr/fr

Météo-France - 73 avenue de Paris, 94165 Saint-Mandé cedex - Contact : contact@meteo.fr

Rédigé par Météo-France avec la contribution des observateurs du réseau nivo-météorologiques. Partenariat : ANMSM (Maires de Stations de Montagne), DSF (Domaines Skiables de France), ADSP (Directeurs de Pistes et de la Sécurité des Stations de Sports d'Hiver) et autres acteurs de la montagne.

Bulletin neige & avalanches par téléphone au
0 892 68 10 20 Service 0,35 € / min + prix appel

RÉPUBLIQUE FRANÇAISE
Liberté Égalité Fraternité

METEO FRANCE
À VOS CÔTÉS, DANS UN CLIMAT QUI CHANGE

Bulletin d'estimation du risque d'avalanche

(valable en dehors des pistes balisées et ouvertes)

MASSIF : Aure Louron

Rédigé le vendredi 27 mars 2026 à 16h

Conditions nivo-météo des 7 derniers jours

	sam. 21/03				dim. 22/03				lun. 23/03				mar. 24/03				mer. 25/03				jeu. 26/03				ven. 27/03			
	03h	09h	15h	21h	03h	09h	15h	21h	03h	09h	15h	21h	03h	09h	15h	21h	03h	09h	15h	21h	03h	09h	15h	21h	03h	09h	15h	21h
Météo																												
Vent (km/h)	10	10	15	15	30	30	50	55	50	40	30	25	35	20	20	60	70	70	75	80	90	80	75	80	85	85	70	55
à 3000m																												
Vent (km/h)	5	5	10	5	5	10	30	25	20	10	15	10	5	5	10	10	10	20	25	25	35	30	25	30	15	15	25	10
à 1500m																												

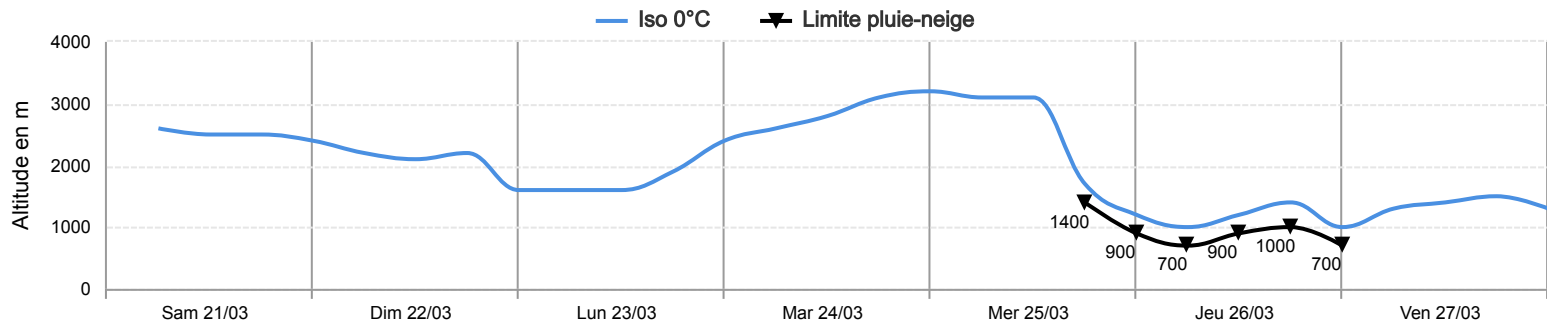

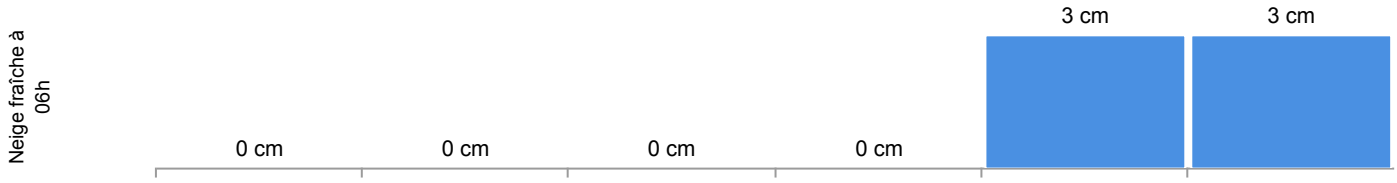

Risque d'avalanche	sam. 21/03	dim. 22/03	lun. 23/03	mar. 24/03	mer. 25/03	jeu. 26/03	ven. 27/03
	2	2	2	2	2	2	2

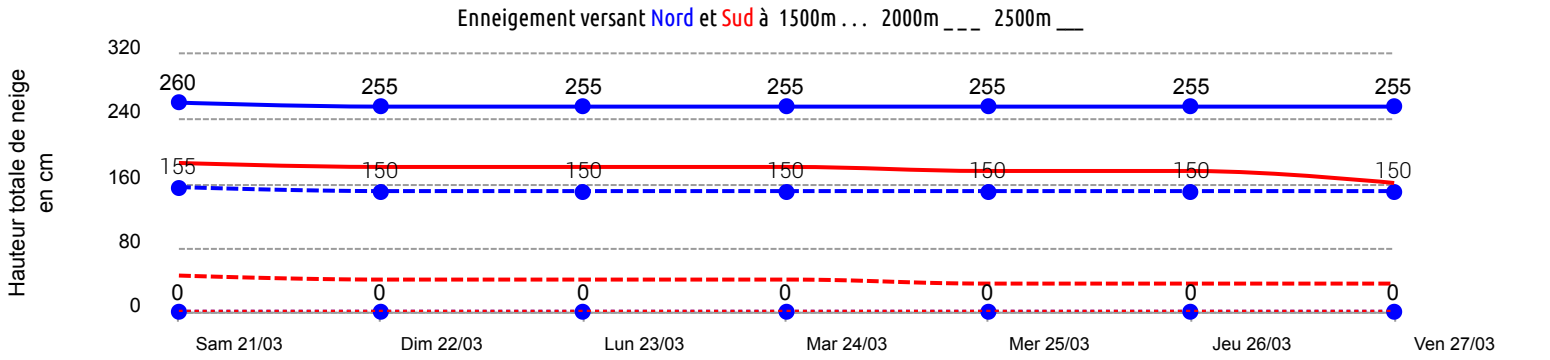

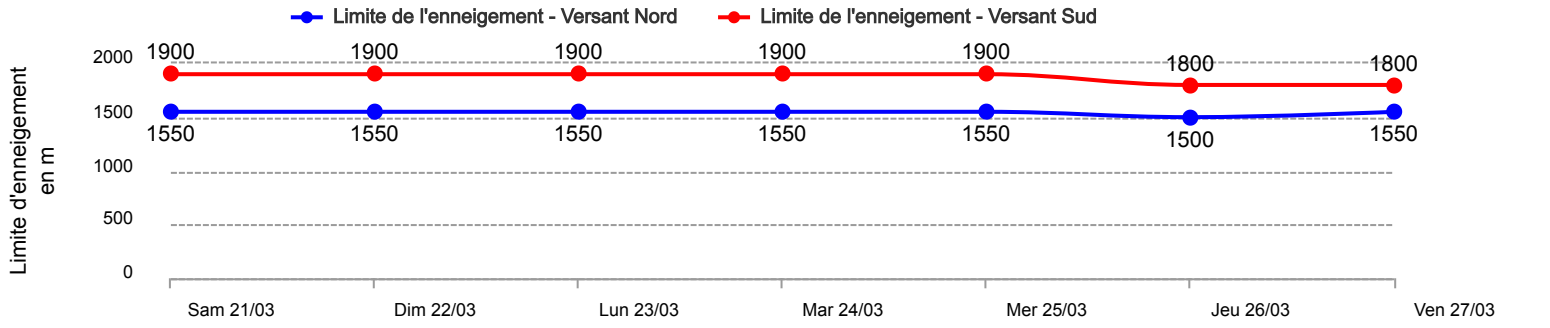

Pour consulter la vigilance en cours, veuillez vous rendre sur le site https://vigilance.meteofrance.fr/fr

Météo-France - 73 avenue de Paris, 94165 Saint-Mandé cedex - Contact : contact@meteo.fr

Rédigé par Météo-France avec la contribution des observateurs du réseau nivo-météorologiques. Partenariat : ANMSM (Maires de Stations de Montagne), DSF (Domaines Skiables de France), ADSP (Directeurs de Pistes et de la Sécurité des Stations de Sports d'Hiver) et autres acteurs de la montagne.

Bulletin neige & avalanches par téléphone au
0 892 68 10 20 Service 0,35 € / min + prix appel