Bulletin d'estimation du risque d'avalanche

(valable en dehors des pistes balisées et ouvertes)

MASSIF : Cinto Rotondo

Rédigé le vendredi 27 mars 2026 à 16h

Estimation des risques pour le : SAMEDI 28 MARS

INSTABILITÉS EN ALTITUDE

2

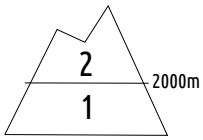

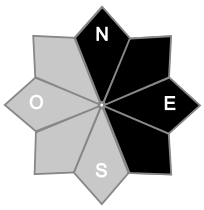

Au-dessus de 2000m indice de risque limité, plus bas indice faible.

Départs spontanés : rares coulées de neige récente

Déclenchements provoqués : plaques à vent difficilement sollicitables, encore présentes en altitude au-dessus de 2000 m

Indices de risque : 5 très fort - 4 fort - 3 marqué - 2 limité - 1 faible -- En noir : les pentes les plus dangereuses

Stabilité du manteau neigeux

Situation avalancheuse typique : neige ventée

Déclenchements provoqués : De nouvelles plaques se sont formées en altitude dans les pentes Nord à Est, au-dessus de 2000 m environ. Certaines instabilités peuvent céder au passage d'un skieur dans les pentes raides, souvent cachées sous une couche de neige récente. Elles peuvent engendrer des avalanches de taille petite à moyenne (taille 1 à 2). En dessous de 2000 m, le manteau neigeux est plus stable.
Départs spontanés : des coulées et avalanches de neige récente sont attendues dans les pentes raides samedi en journée, surtout dans les pentes exposées au soleil.
Autres : Nombreuses surfaces dures et glacées, pouvant être recouvertes de quelques centimètres de neige récente.
Présence de corniches parfois volumineuses, dont certaines commencent à se détacher (apparition de fissures).

Qualité de la neige

Qualification de l'enneigement : L'enneigement est excellent pour la saison au-dessus de 1600 m. Sur la Maniccia, à 2400 m d'altitude dans le massif du Rotondo, on relève pratiquement 3m30 de hauteur de neige totale.
Limite d'enneigement skiable : 1400 à 1500 m selon le versant.
État de la neige : Une fine couche de neige récente, localement de la neige roulée, recouvre le plus souvent des croûtes épaisses et les surfaces dures. A haute altitude, dans les pentes N à E, la neige reste froide et assez légère, ou bien densifiée ou durcie sur les zones qui ont été exposées au vent. À noter également la présence de corniches parfois volumineuses.

Aperçu météo pour le samedi 28 mars

	nuit	matin	après-midi	soir
Temps sec et ensoleillé				
Pluie-Neige				
Iso 0 °C	1700 m	2200 m	2100 m	2200 m
Vent 1500 m	20 km/h	15 km/h	20 km/h	10 km/h
Vent 3000 m	30 km/h	15 km/h	20 km/h	10 km/h

Épaisseur de neige hors-piste

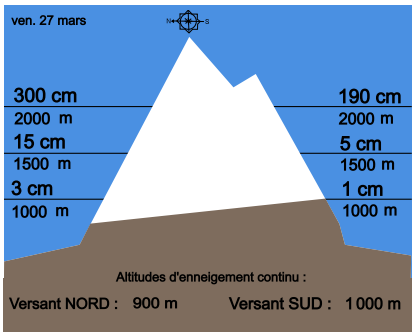

Précipitations à 1800 m

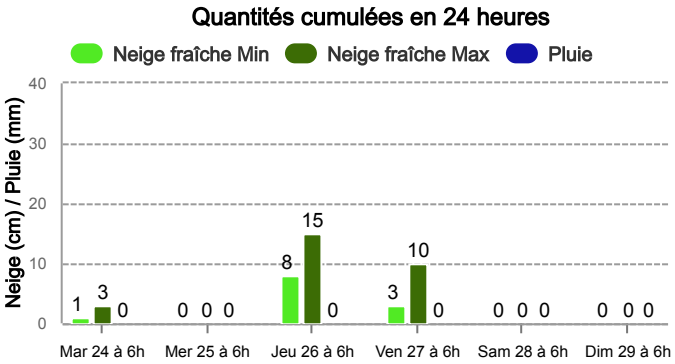

Tendance du dimanche 29 mars

2

Indice de risque limité

Pas dévolution notable en termes de risque.

Pour consulter la vigilance en cours, veuillez vous rendre sur le site https://vigilance.meteofrance.fr/fr

Météo-France - 73 avenue de Paris, 94165 Saint-Mandé cedex - Contact : contact@meteo.fr

Rédigé par Météo-France avec la contribution des observateurs du réseau nivo-météorologiques. Partenariat : ANMSM (Maires de Stations de Montagne), DSF (Domaines Skiables de France), ADSP (Directeurs de Pistes et de la Sécurité des Stations de Sports d'Hiver) et autres acteurs de la montagne.

Bulletin neige & avalanches par téléphone au

0 892 68 10 20 Service 0,35 € / min + prix appel

RÉPUBLIQUE FRANÇAISE
Liberté Égalité Fraternité

METEO FRANCE
À VOS CÔTÉS, DANS UN CLIMAT QUI CHANGE

Bulletin d'estimation du risque d'avalanche

(valable en dehors des pistes balisées et ouvertes)

MASSIF : Cinto Rotondo

Rédigé le vendredi 27 mars 2026 à 16h

Conditions nivo-météo des 7 derniers jours

	sam. 21/03				dim. 22/03				lun. 23/03				mar. 24/03				mer. 25/03				jeu. 26/03				ven. 27/03			
	03h	09h	15h	21h	03h	09h	15h	21h	03h	09h	15h	21h	03h	09h	15h	21h	03h	09h	15h	21h	03h	09h	15h	21h	03h	09h	15h	21h
Météo																												
Vent (km/h)	50	30	15	20	15	20	15	10	10	15	20	40	30	25	20	20	20	60	80	120	110	85	90	90	50	40	35	50
à 3000m																												
Vent (km/h)	25	15	10	10	5	10	5	5	5	10	15	30	5	10	10	10	10	30	50	80	85	60	60	60	35	10	25	30
à 1500m																												

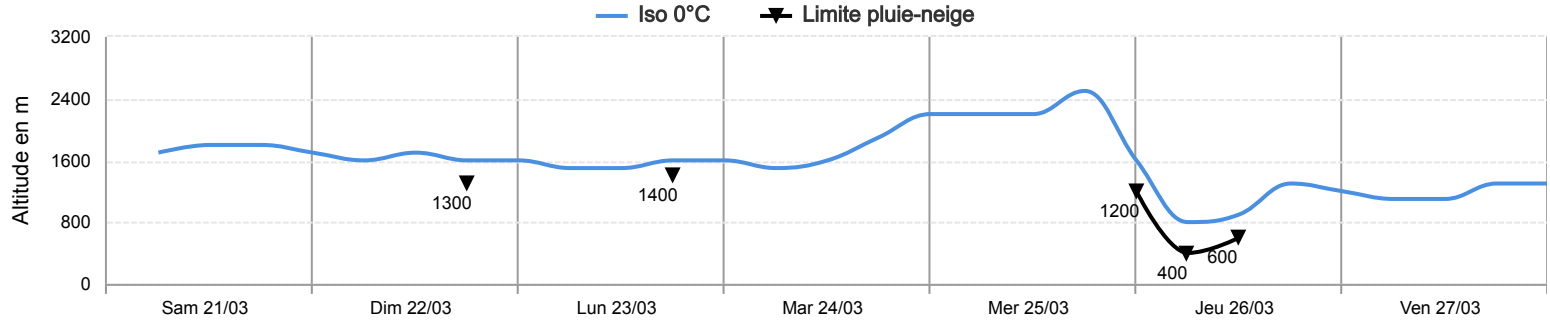

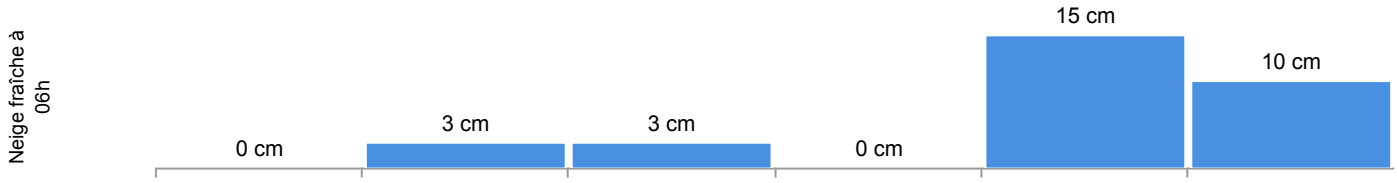

Risque d'avalanche	sam. 21/03	dim. 22/03	lun. 23/03	mar. 24/03	mer. 25/03	jeu. 26/03	ven. 27/03
	2	2	2	2	2	2	2

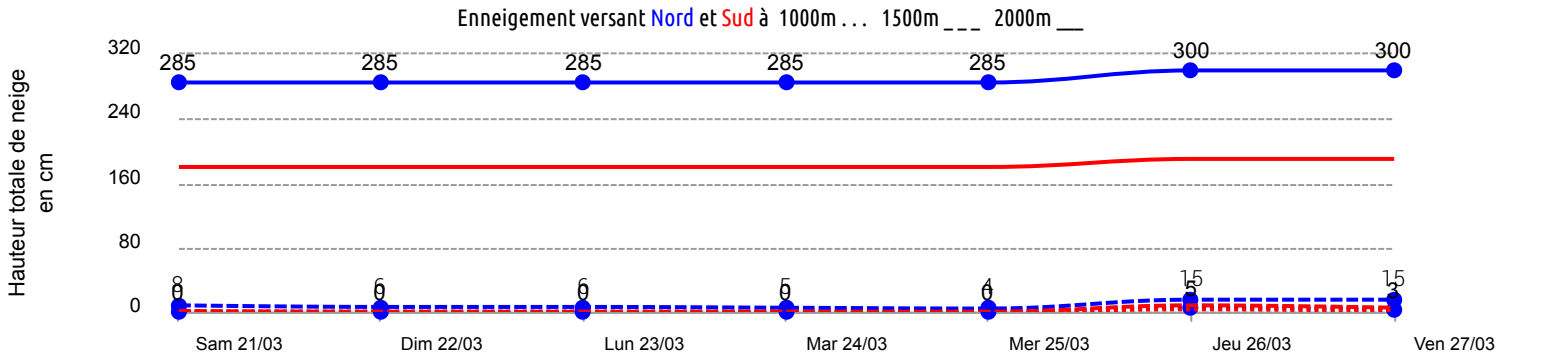

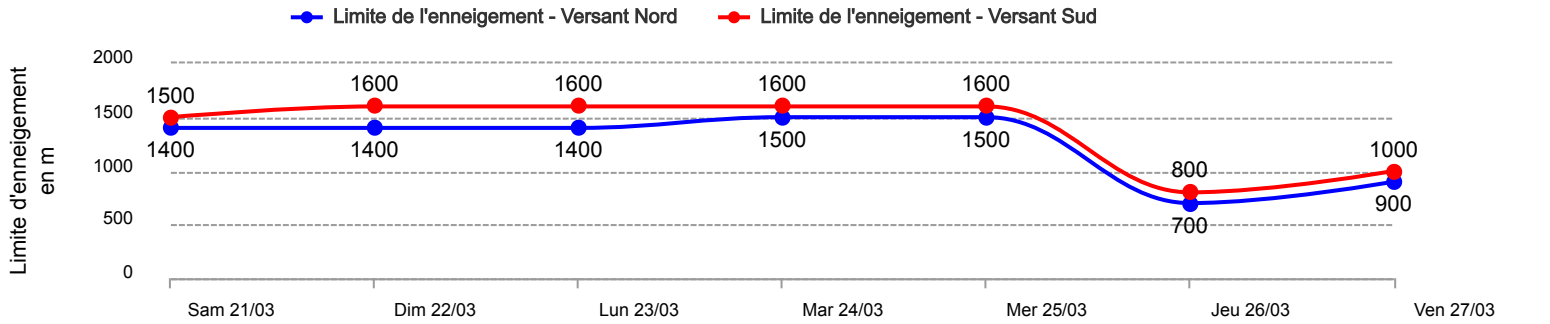

Pour consulter la vigilance en cours, veuillez vous rendre sur le site https://vigilance.meteofrance.fr/fr

Météo-France - 73 avenue de Paris, 94165 Saint-Mandé cedex - Contact : contact@meteo.fr

Bulletin neige & avalanches par téléphone au

0 892 68 10 20 Service 0,35 € / min + prix appel

Rédigé par Météo-France avec la contribution des observateurs du réseau nivo-météorologiques. Partenariat : ANMSM (Maires de Stations de Montagne), DSF (Domaines Skiables de France), ADSP (Directeurs de Pistes et de la Sécurité des Stations de Sports d'Hiver) et autres acteurs de la montagne.