Bulletin d'estimation du risque d'avalanche

(valable en dehors des pistes balisées et ouvertes)

MASSIF : Grandes-Rousses

Rédigé le vendredi 27 mars 2026 à 16h

Estimation des risques pour le : SAMEDI 28 MARS

QUELQUES PLAQUES DANS LA NEIGE RÉCENTE VENTÉE.

2

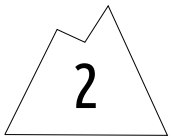

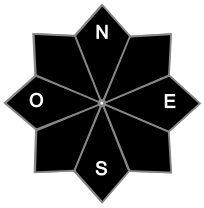

zones d'accumulation

Indice de risque limité.

Départs spontanés : Rare rupture de plaque sous le vent de Nord-Nord-Est en journée. Le matin surtout, de rares coulées humides au soleil.

Déclenchements provoqués : Quelques plaques dans la neige ventée, parfois loin des crêtes.

Indices de risque : 5 très fort - 4 fort - 3 marqué - 2 limité - 1 faible -- En noir : les pentes les plus dangereuses

Stabilité du manteau neigeux

Situation avalancheuse typique : neige ventée

Déclenchements provoqués : Quelques plaques à vent subsistent ce samedi, dans les zones d'accumulations formées par le vent de Nord-Nord-Est qui reste encore assez sensible en altitude ce samedi. Elles peuvent être situées loin des crêtes, parfois même en bas de pente. Elles se retrouvent en tout versant, bien que plus fréquemment dans les versants à composante Sud à Est, qui ont été généralement plus chargés. Souvent difficiles à déclencher et d'aspect dur, mais localement elles peuvent présenter un aspect un peu plus friable voire poudreux, tout en étant plus réactives au passage d'un pratiquant.

Déclenchements spontanés : - Principalement en versant d'un large Sud d'altitude, une rare rupture de plaque de taille 1 à 2 est possible dans les pentes chargées par le vent de Nord-Nord-Est, encore un peu sensible en altitude ce samedi.
- Egalement un risque de rares coulées humides dans les pentes ensoleillées (surtout samedi matin où le ciel sera moins encombré), dans la neige récente qui peut s'humidifier au soleil et près des rochers.

Qualité de la neige

Qualification de l'enneigement : L'enneigement est bon à basse altitude, et même excellent dés 1800 / 2000m. Peu de sous couche sous 1700m en plein Sud.
Limites skiables : Vers 1000 / 1200m, avec prudence en Sud / sous les sapins

Qualité de la neige samedi : La neige récente a été fortement travaillée / soufflée par le vent dans de nombreux secteurs, le manteau neigeux est parfois très irrégulier. Les crêtes et les pentes les plus ventées, où la neige a été arrachée, sont même dégarnies et le ski se fait parfois sur la vieille croûte de regel. Toutefois, on retrouve des secteurs en neige poudreuse plus agréable, notamment en bas de pentes / dans les arbres. A noter que dans certaines pentes exposées au soleil, la neige récente s'est parfois humidifiée (ou s'humidifie un peu ce samedi matin avant que le ciel ne se charge davantage), on peut alors y retrouver des surfaces croûtées glissantes. En fin de journée et soirée, une fine couche de neige fraîche plus ou moins ventée pourrait se déposer par endroits au passage de la nouvelle perturbation.

Aperçu météo pour le samedi 28 mars

	nuit	matin	après-midi	soir
Pluie-Neige				1 000 m
Iso 0 °C	1 500 m	1 400 m	1 400 m	1 300 m
Vent 2000 m	↓ 30 km/h	↓ 35 km/h	↙ 35 km/h	↙ 30 km/h
Vent 3000 m	↙ 40 km/h	↓ 55 km/h	↓ 50 km/h	↙ 45 km/h

Arrivée d'une nouvelle perturbation ce samedi après-midi et soir, d'activité faible à très faible. Vent de Nord restant sensible en altitude.

Épaisseur de neige hors-piste

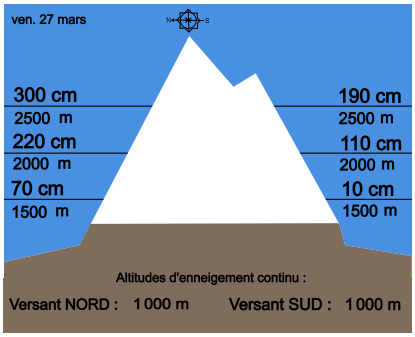

Précipitations à 1800 m

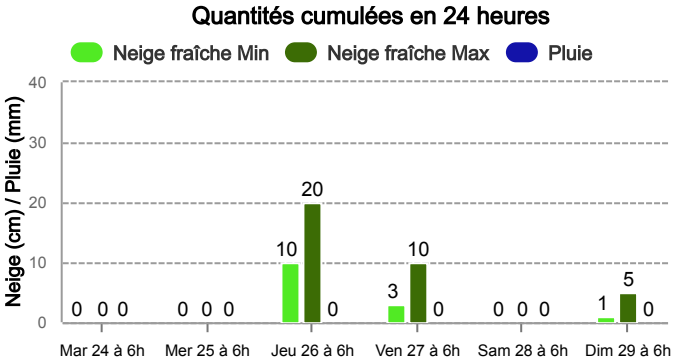

Tendance du dimanche 29 mars

2

Indice de risque limité

Dimanche, le risque serait en légère baisse. Temps frais et sec. Le vent de Nord encore un peu sensible au lever du jour faiblit temporairement en journée, favorisant la stabilisation du manteau neigeux.

Pour consulter la vigilance en cours, veuillez vous rendre sur le site https://vigilance.meteofrance.fr/fr

Météo-France - 73 avenue de Paris, 94165 Saint-Mandé cedex - Contact : contact@meteo.fr

Rédigé par Météo-France avec la contribution des observateurs du réseau nivo-météorologiques. Partenariat : ANMSM (Maires de Stations de Montagne), DSF (Domaines Skiables de France), ADSP (Directeurs de Pistes et de la Sécurité des Stations de Sports d'Hiver) et autres acteurs de la montagne.

Bulletin neige & avalanches par téléphone au
0 892 68 10 20 Service 0,35 € / min + prix appel

RÉPUBLIQUE FRANÇAISE
Liberté Égalité Fraternité

METEO FRANCE
À VOS CÔTÉS, DANS UN CLIMAT QUI CHANGE

Bulletin d'estimation du risque d'avalanche

(valable en dehors des pistes balisées et ouvertes)

MASSIF : Grandes-Rousses

Rédigé le vendredi 27 mars 2026 à 16h

Conditions nivo-météo des 7 derniers jours

	sam. 21/03				dim. 22/03				lun. 23/03				mar. 24/03				mer. 25/03				jeu. 26/03				ven. 27/03			
	03h	09h	15h	21h	03h	09h	15h	21h	03h	09h	15h	21h	03h	09h	15h	21h	03h	09h	15h	21h	03h	09h	15h	21h	03h	09h	15h	21h
Météo																												
Vent (km/h)	15	20	15	20	15	15	15	10	10	30	25	30	25	15	10	10	25	45	70	100	95	90	90	85	80	60	40	25
à 3000m																												
Vent (km/h)	0	0	5	10	10	5	5	5	5	25	20	15	10	10	10	5	10	20	50	70	70	60	65	60	45	45	30	15
à 2000m																												

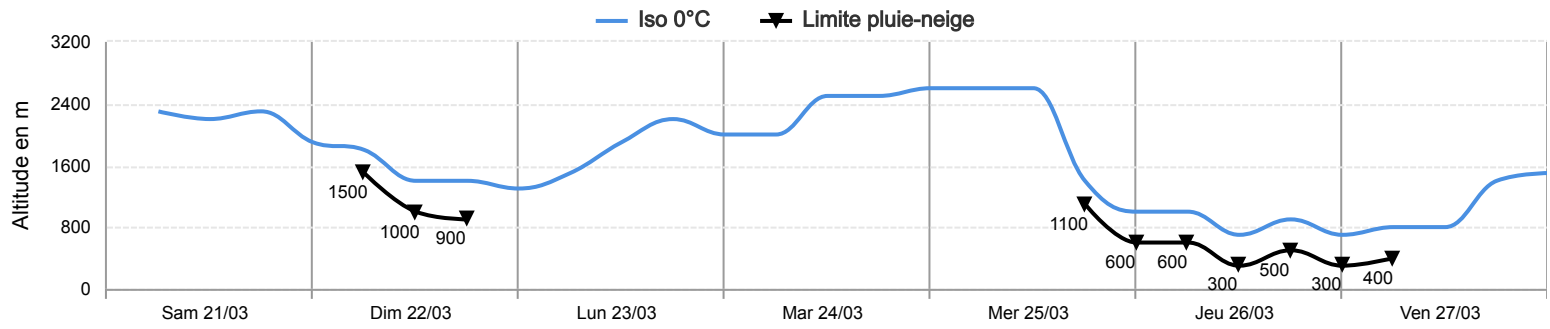

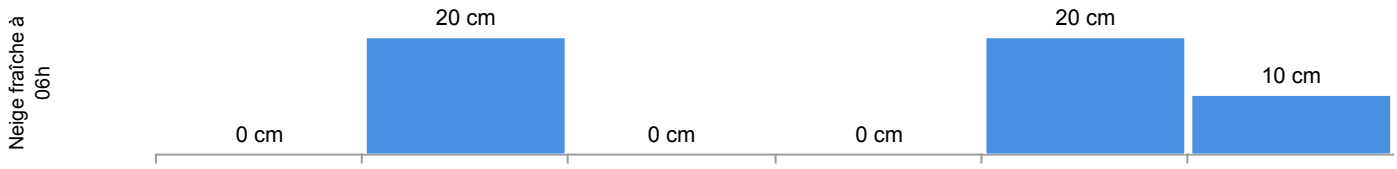

Risque d'avalanche	sam. 21/03	dim. 22/03	lun. 23/03	mar. 24/03	mer. 25/03	jeu. 26/03	ven. 27/03
	2	2	2	2	3	4	3

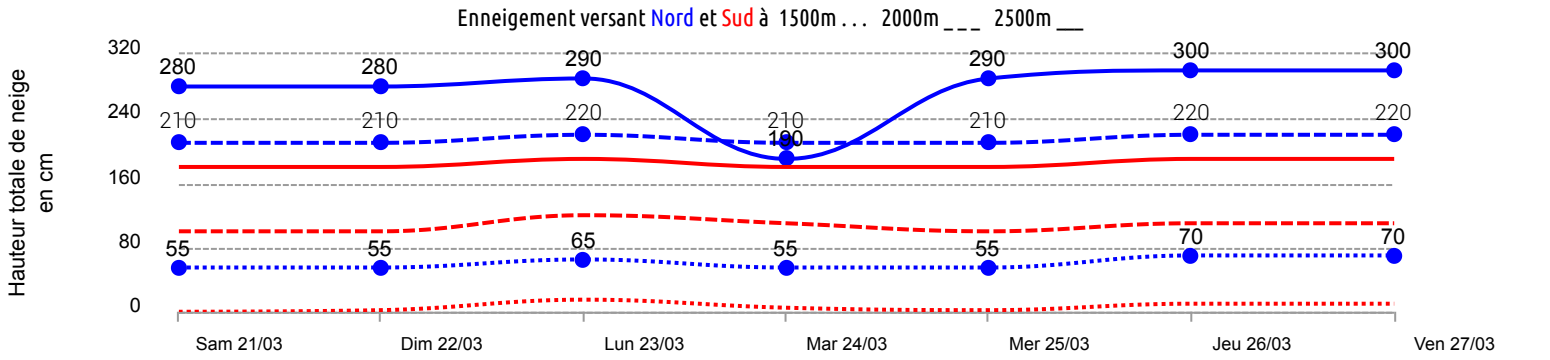

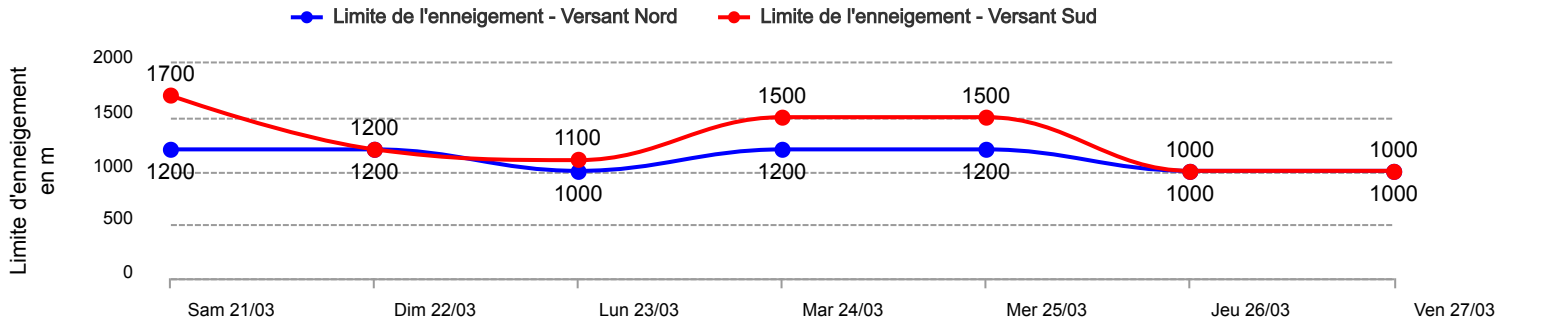

Pour consulter la vigilance en cours, veuillez vous rendre sur le site https://vigilance.meteofrance.fr/fr

Météo-France - 73 avenue de Paris, 94165 Saint-Mandé cedex - Contact : contact@meteo.fr

Bulletin neige & avalanches par téléphone au

0 892 68 10 20 Service 0,35 € / min + prix appel

Rédigé par Météo-France avec la contribution des observateurs du réseau nivo-météorologiques. Partenariat : ANMSM (Maires de Stations de Montagne), DSF (Domaines Skiables de France), ADSP (Directeurs de Pistes et de la Sécurité des Stations de Sports d'Hiver) et autres acteurs de la montagne.