Bulletin d'estimation du risque d'avalanche
(valable en dehors des pistes balisées et ouvertes)

MASSIF : Haute-Ariege

Rédigé le vendredi 27 mars 2026 à 16h

Estimation des risques pour le : SAMEDI 28 MARS

PRÉSENCE DE QUELQUES PLAQUES À VENT EN ALTITUDE; FORMATION EN FIN DE JOURNÉE DE NOUVELLES PLAQUES

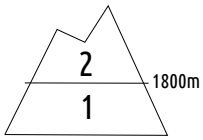

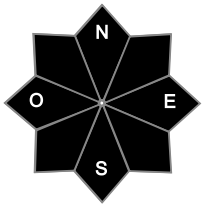

Au-dessus de 1800m indice de risque limité, plus bas indice faible.

Départs spontanés : Rares petits départs en neige récente dans des couloirs très raides.

Déclenchements provoqués : Anciennes plaques en versants nord; formation en fin de journée de nouvelles plaques au fil des chutes de neige ventées

Indices de risque : 5 très fort - 4 fort - 3 marqué - 2 limité - 1 faible -- En noir : les pentes les plus dangereuses

Stabilité du manteau neigeux

Situation avalancheuse typique : couche fragile persistante neige ventée

Déclenchements provoqués :

- Dans un large secteur nord, quelques structures de plaques sont actuellement présentes, au plus bas vers 2000/2200 m, mais surtout au-delà de 2300/2400 m, contenant des couches fragiles persistantes (givre de surface ou neige roulée). Elles peuvent être masquées par les petites chutes de neige de mercredi/jeudi. Elles peuvent donner lieu au passage d'un pratiquant à des déclenchements d'avalanches de taille 1 à 2, avec des cassures de 20/30 cm voire 40 cm.

- En fin de journée, les chutes de neige attendues ce samedi se produisent sous un vent de nord de plus en plus virulent. Des plaques de plus en plus épaisses se forment, plutôt dans les versants sud mais pas seulement. On les trouve dans un premier temps plutôt à proximité des crêtes. Le déclenchement de ces plaques est donc possible avec des cassures de plus en plus importantes. D'ici le début de nuit de samedi à dimanche, au vu des cumuls attendus, les avalanches induites sont généralement de taille 1 (pouvant potentiellement entrainer un randonneur sur quelques mètres ou le faire glisser sur l'ancienne neige dure, sans l'ensevelir).
Facteur aggravant : ces plaques peuvent reposer sur de la neige roulée tombée par endroits dans la nuit de mercredi à jeudi, ou sur une couche de givre voire de grains anguleux qui auraient pu se former dans la nuit de vendredi à samedi.

Observables : neige en surface travaillée par le vent, fissures devant les skis, "woomfs".

Départs spontanés :

- Le matin, d'éventuels départs de coulées spontanés en neige humide sont possibles si le relatif et temporaire redoux samedi matin s'accompagne d'éclaircies un peu durables permettant une humidification de la neige en surface dans les secteurs est puis sud.
- En fin de journée, des départs spontanés en neige sèche de taille 1 à 2 sont possibles par surcharge dans les couloirs raides, pouvant éventuellement mobiliser en cascade les couches fragiles mentionnées plus haut.

Autre :
Très net refroidissement samedi soir accompagné d'un renforcement du vent.

Qualité de la neige

Enneigement :
L'enneigement reste très bon pour la saison, après plusieurs hivers déficitaires.
En altitude, les cumuls sont très conséquents, mais les crêtes et sommets exposés au vent d'ouest à nord-ouest sont parfois complètement déneigés.
On peut encore chausser les skis dans les secteurs ombragés vers 1500/1600 m, voire un peu plus bas dans les endroits les plus froids.

Qualité de la neige :
Samedi matin, on trouvera une neige souvent croûtée en versants sud jusque vers 2200m. En revanche, dans les pentes d'altitude en sud et jusqu'assez bas en nord, la neige devrait être restée légère, avec souvent de multiples couches relativement fines plus ou moins cohésives entre elles. En s'approchant des crêtes, on trouvera des zones de neige très dure voire glacée dans les secteurs balayés par le vent.

Aperçu météo pour le samedi 28 mars

	nuit	matin	après-midi	soir
Froid; à partir de l'après-midi, chutes de neige à altitude de plus en plus basse et renforcement du vent de nord				
Pluie-Neige			1 400 m	1 000 m
Iso 0 °C	1 200 m	1 500 m	1 800 m	1 400 m
Vent 2000 m	20 km/h	20 km/h	30 km/h	55 km/h
Vent 3000 m	40 km/h	45 km/h	65 km/h	85 km/h

Pour consulter la vigilance en cours, veuillez vous rendre sur le site https://vigilance.meteofrance.fr/fr

Météo-France - 73 avenue de Paris, 94165 Saint-Mandé cedex - Contact : contact@meteo.fr

Rédigé par Météo-France avec la contribution des observateurs du réseau nivo-météorologiques. Partenariat : ANMSM (Maires de Stations de Montagne), DSF (Domaines Skiables de France), ADSP (Directeurs de Pistes et de la Sécurité des Stations de Sports d'Hiver) et autres acteurs de la montagne.

Bulletin neige & avalanches par téléphone au
0 892 68 10 20 Service 0,35 € / min + prix appel

Bulletin d'estimation du risque d'avalanche

(valable en dehors des pistes balisées et ouvertes)

MASSIF : Haute-Ariege

Rédigé le vendredi 27 mars 2026 à 16h

Épaisseur de neige hors-piste

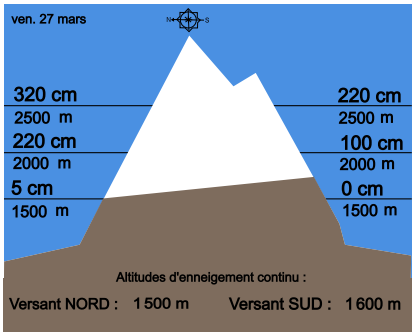

Précipitations à 1800 m

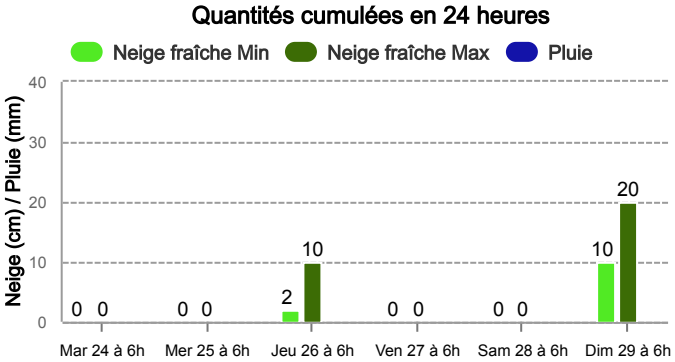

Tendance du dimanche 29 mars

Indice de risque marqué

La poursuite des chutes de neige dans la nuit de samedi à dimanche va conduire à une probable augmentation du risque avalancheux dimanche.

Pour consulter la vigilance en cours, veuillez vous rendre sur le site https://vigilance.meteofrance.fr/fr

Météo-France - 73 avenue de Paris, 94165 Saint-Mandé cedex - Contact : contact@meteo.fr

Rédigé par Météo-France avec la contribution des observateurs du réseau nivo-météorologiques. Partenariat : ANMSM (Maires de Stations de Montagne), DSF (Domaines Skiables de France), ADSP (Directeurs de Pistes et de la Sécurité des Stations de Sports d'Hiver) et autres acteurs de la montagne.

Bulletin neige & avalanches par téléphone au

0 892 68 10 20 Service 0,35 € / min + prix appel

RÉPUBLIQUE FRANÇAISE
Liberté Égalité Fraternité

METEO FRANCE
À VOS CÔTÉS, DANS UN CLIMAT QUI CHANGE

Bulletin d'estimation du risque d'avalanche
(valable en dehors des pistes balisées et ouvertes)
MASSIF : Haute-Ariege

Rédigé le vendredi 27 mars 2026 à 16h

Conditions nivo-météo des 7 derniers jours

	sam. 21/03				dim. 22/03				lun. 23/03				mar. 24/03				mer. 25/03				jeu. 26/03				ven. 27/03			
	03h	09h	15h	21h	03h	09h	15h	21h	03h	09h	15h	21h	03h	09h	15h	21h	03h	09h	15h	21h	03h	09h	15h	21h	03h	09h	15h	21h
Météo																												
Vent (km/h)	10	10	10	10	20	20	40	45	45	35	20	15	15	15	15	15	30	35	45	75	85	85	80	75	80	80	65	45
à 3000m																												
Vent (km/h)	5	5	5	10	10	10	25	35	30	20	10	10	10	10	10	10	10	15	30	45	55	50	50	45	50	50	40	20
à 2000m																												

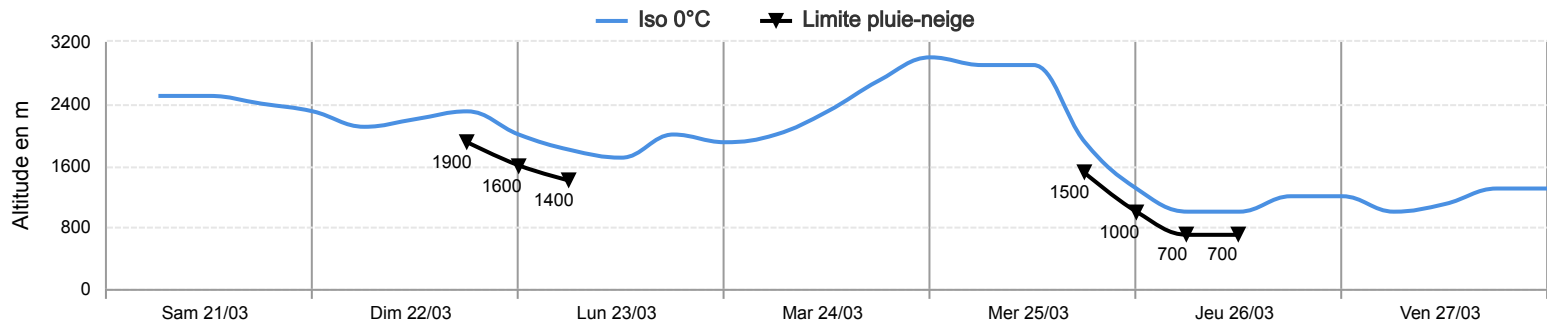

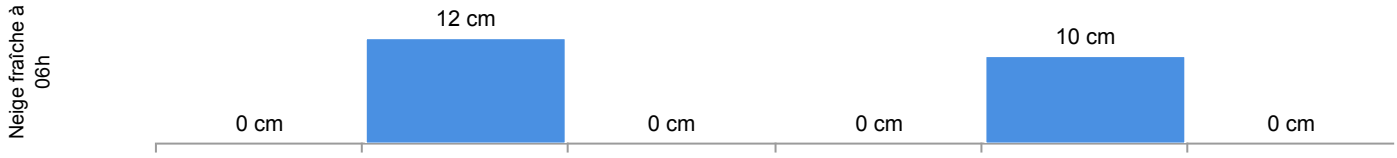

Risque d'avalanche	sam. 21/03	dim. 22/03	lun. 23/03	mar. 24/03	mer. 25/03	jeu. 26/03	ven. 27/03
	2	2	3	2	2	2	2

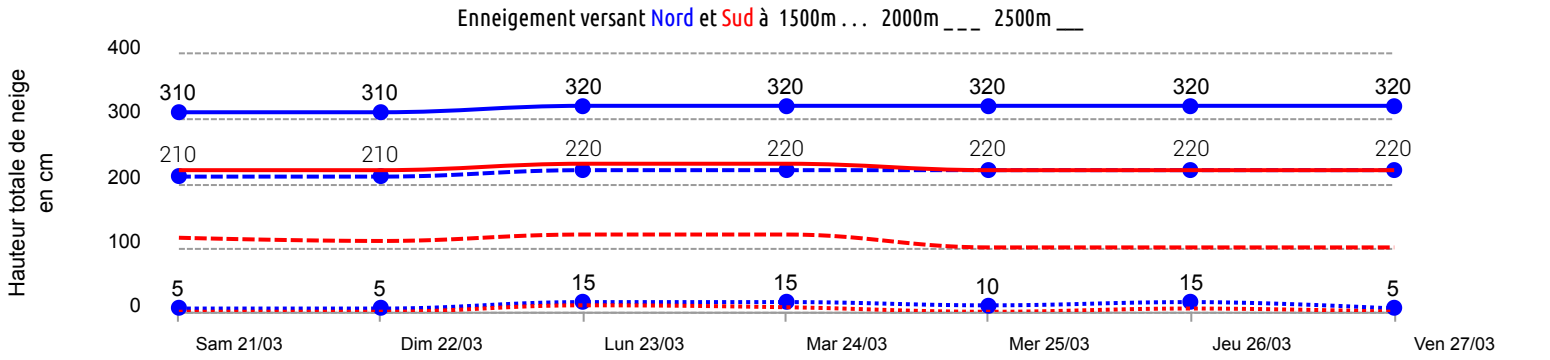

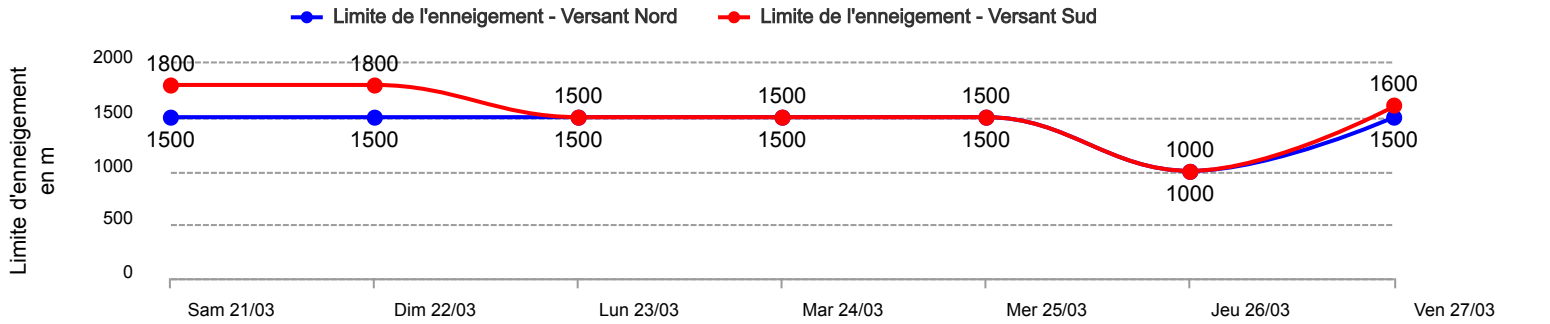

Pour consulter la vigilance en cours, veuillez vous rendre sur le site https://vigilance.meteofrance.fr/fr

Météo-France - 73 avenue de Paris, 94165 Saint-Mandé cedex - Contact : contact@meteo.fr

Bulletin neige & avalanches par téléphone au
0 892 68 10 20 Service 0,35 € / min + prix appel

Rédigé par Météo-France avec la contribution des observateurs du réseau nivo-météorologiques. Partenariat : ANMSM (Maires de Stations de Montagne), DSF (Domaines Skiables de France), ADSP (Directeurs de Pistes et de la Sécurité des Stations de Sports d'Hiver) et autres acteurs de la montagne.