Bulletin d'estimation du risque d'avalanche
(valable en dehors des pistes balisées et ouvertes)

MASSIF : Haute-Tarentaise

Rédigé le vendredi 27 mars 2026 à 16h

Estimation des risques pour le : SAMEDI 28 MARS

ENCORE QUELQUES INSTABILITÉS DANS LA NEIGE RÉCENTE VENTÉE.

2

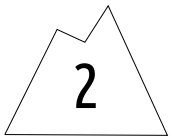

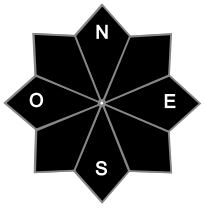

Indice de risque limité.

Départs spontanés : petits départs en neige humide dans les versants ensoleillés.

Déclenchements provoqués : encore quelques plaques dans la neige récente ventée.

Indices de risque : 5 très fort - 4 fort - 3 marqué - 2 limité - 1 faible -- En noir : les pentes les plus dangereuses

Stabilité du manteau neigeux

Situation avalancheuse typique : neige ventée

Déclenchement provoqués : quelques plaques en perte de réactivité, encore un peu entretenues par le vent de nord en altitude. On les trouve **en tout versant, plaques dures près des crêtes, parfois encore d'aspect poudreux dans les pentes**. Épaisseurs des cassures hétérogènes, 20 à 40 cm en moyenne. Elles occasionnent de petites à moyennes avalanches.
De l'Aiguille des Glaciers à la Rosière, les cassures et les volumes mobilisables peuvent être plus importants.
Observables : accumulation de neige, généralement plus dense voire dure.

Départs spontanés :
Quelques avalanches de neige humide dans les versants qui auront bien chauffé avant que le ciel se couvre à la mi-journée, plutôt dans les pentes raides. Généralement de petites avalanches.

Qualité de la neige

Enneigement : Encore un peu au dessus de la moyenne, sauf aux plus basses altitudes où les hauteurs de neige sont tout juste correctes pour la saison.

Limite skiable : 1300 m au mieux en Nord. Plutôt 1600 m en sud pas trop raide.

Qualité de la neige : les secteurs d'altitude, notamment les versants nord, sont soufflés par le vent : la neige est inégalement répartie entre zones dégarnies décapées et accumulations sous le vent.
Pour trouver de la poudreuse, viser plutôt les moyennes/basses altitudes et la forêt.
Dans les versants ensoleillés, notamment Sud à Est, la neige s'humidifie en surface (ça botte). Toutefois en altitude, le vent du nord bien frais concurrence l'action du soleil, limitant le ramollissement de la neige.

Aperçu météo pour le samedi 28 mars

	nuit	matin	après-midi	soir
Pluie-Neige				1 000 m
Iso 0 °C	1 100 m	1 400 m	1 700 m	1 300 m
Vent 2500 m	↑ 20 km/h	→ 30 km/h	↘ 30 km/h	↓ 20 km/h
Vent 3500 m	↙ 30 km/h	↓ 40 km/h	↓ 40 km/h	↙ 30 km/h

Beau temps le matin, se voilant avec jour blanc d'ici la mi-journée. Arrivée d'une perturbation neigeuse peu active en fin d'après midi.

Épaisseur de neige hors-piste

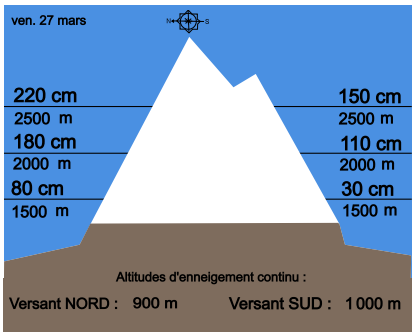

Précipitations à 1800 m

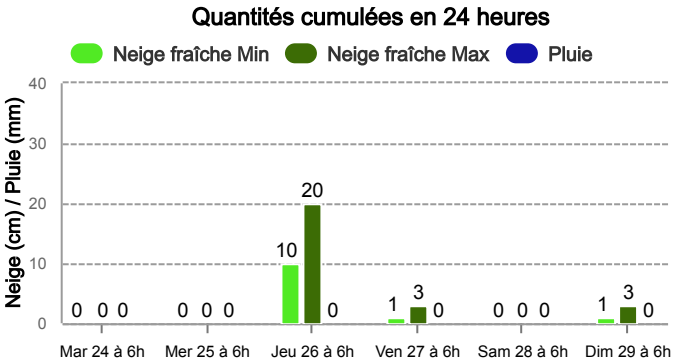

Tendance du dimanche 29 mars

2

Indice de risque limité

Vent faible et chute de neige négligeable la nuit précédente, temps calme plus ou moins nuageux en journée => poursuite de la stabilisation, risque stationnaire.

Pour consulter la vigilance en cours, veuillez vous rendre sur le site https://vigilance.meteofrance.fr/fr

Météo-France - 73 avenue de Paris, 94165 Saint-Mandé cedex - Contact : contact@meteo.fr

Rédigé par Météo-France avec la contribution des observateurs du réseau nivo-météorologiques. Partenariat : ANMSM (Maires de Stations de Montagne), DSF (Domaines Skiables de France), ADSP (Directeurs de Pistes et de la Sécurité des Stations de Sports d'Hiver) et autres acteurs de la montagne.

Bulletin neige & avalanches par téléphone au
0 892 68 10 20 Service 0,35 € / min + prix appel

RÉPUBLIQUE FRANÇAISE
Liberté Égalité Fraternité

METEO FRANCE
À VOS CÔTÉS, DANS UN CLIMAT QUI CHANGE

Bulletin d'estimation du risque d'avalanche
(valable en dehors des pistes balisées et ouvertes)
MASSIF : Haute-Tarentaise

Rédigé le vendredi 27 mars 2026 à 16h

Conditions nivo-météo des 7 derniers jours

	sam. 21/03				dim. 22/03				lun. 23/03				mar. 24/03				mer. 25/03				jeu. 26/03				ven. 27/03			
	03h	09h	15h	21h	03h	09h	15h	21h	03h	09h	15h	21h	03h	09h	15h	21h	03h	09h	15h	21h	03h	09h	15h	21h	03h	09h	15h	21h
Météo																												
Vent (km/h)	20	5	10	20	20	25	20	10	15	20	15	20	15	25	15	35	50	65	85	95	95	85	80	75	60	50	30	30
à 3500m																												
Vent (km/h)	5	10	20	10	10	30	30	20	15	10	15	10	10	10	10	15	25	45	70	85	85	75	70	65	40	30	20	20
à 2500m																												

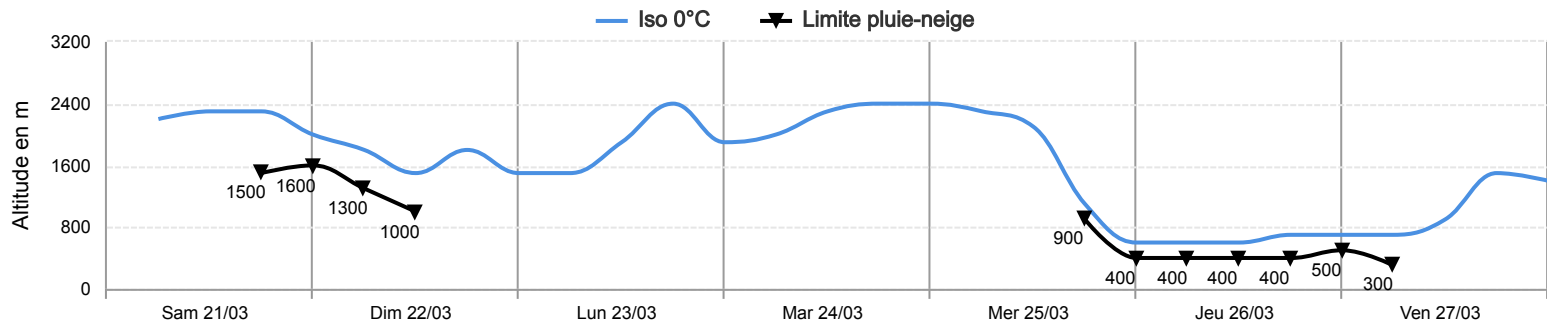

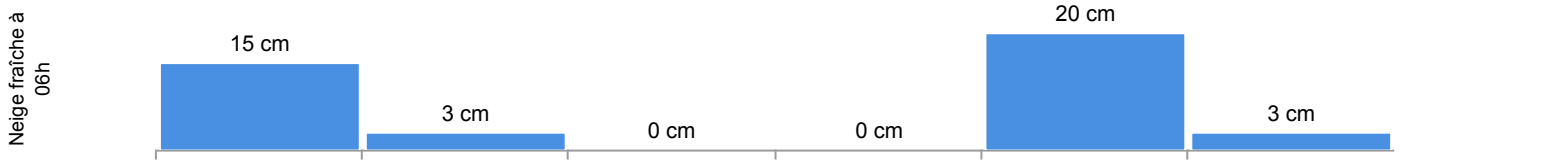

Risque d'avalanche	sam. 21/03	dim. 22/03	lun. 23/03	mar. 24/03	mer. 25/03	jeu. 26/03	ven. 27/03
	2	3	2	2	3	3	3

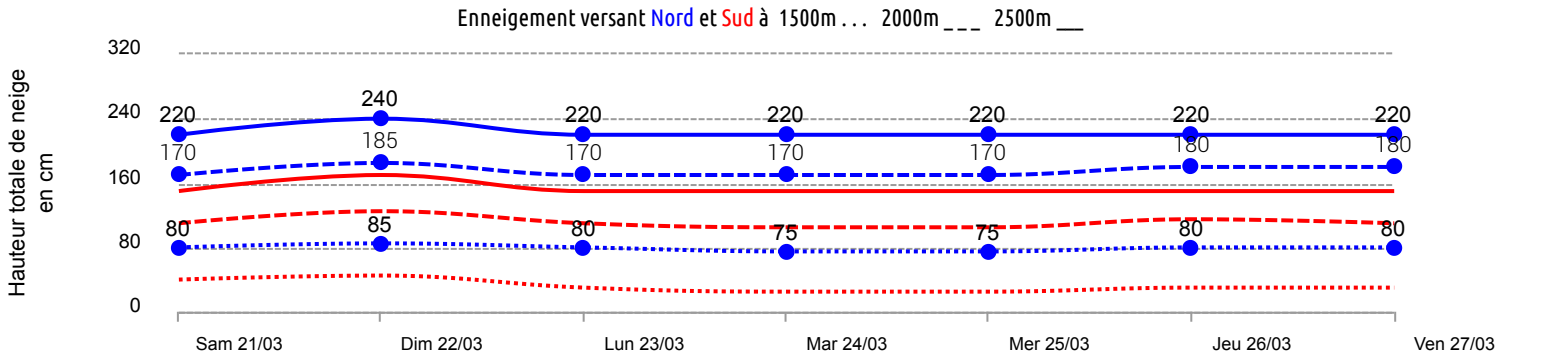

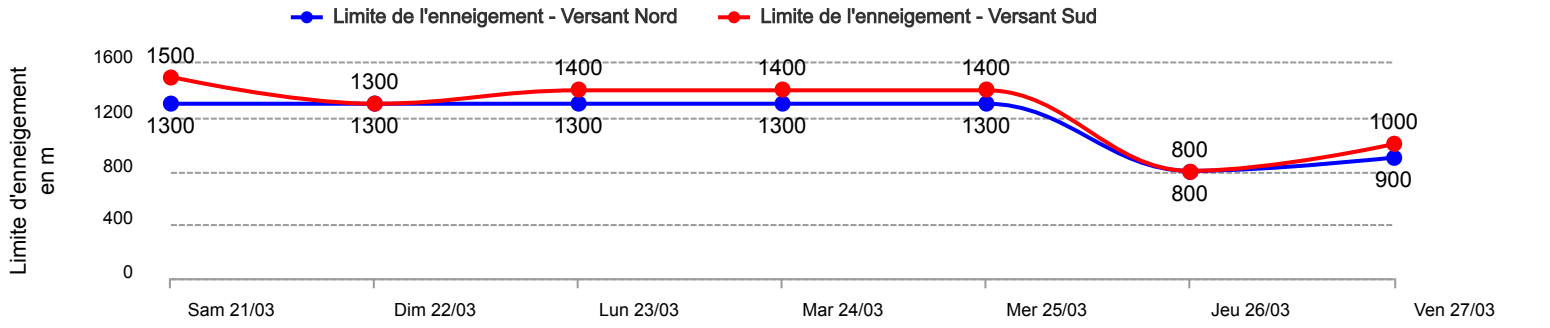

Pour consulter la vigilance en cours, veuillez vous rendre sur le site https://vigilance.meteofrance.fr/fr

Météo-France - 73 avenue de Paris, 94165 Saint-Mandé cedex - Contact : contact@meteo.fr

Rédigé par Météo-France avec la contribution des observateurs du réseau nivo-météorologiques. Partenariat : ANMSM (Maires de Stations de Montagne), DSF (Domaines Skiables de France), ADSP (Directeurs de Pistes et de la Sécurité des Stations de Sports d'Hiver) et autres acteurs de la montagne.

Bulletin neige & avalanches par téléphone au
0 892 68 10 20 Service 0,35 € / min + prix appel