Bulletin d'estimation du risque d'avalanche

(valable en dehors des pistes balisées et ouvertes)

MASSIF : Mercantour

Rédigé le vendredi 27 mars 2026 à 16h

Estimation des risques pour le : SAMEDI 28 MARS

QUELQUES PLAQUES EN PLACE DANS LA NEIGE VENTÉE

2

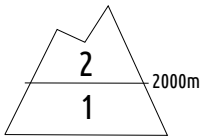

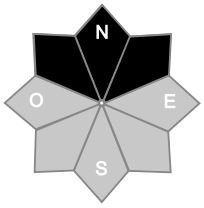

Au-dessus de 2000m indice de risque limité, plus bas indice faible.

Départs spontanés : peu probables, rares départs en neige humide en journée.

Déclenchements provoqués : quelques plaques ventées en place.

Indices de risque : 5 très fort - 4 fort - 3 marqué - 2 limité - 1 faible -- En noir : les pentes les plus dangereuses

Stabilité du manteau neigeux

Situation avalancheuse typique : neige ventée

Déclenchements provoqués : quelques plaques en place, formées jeudi par le transport de neige restée légère en versants ombragés, sous l'action du fort vent de nord. Elles sont présentes essentiellement au dessus de 2000/2200 m, surtout en versants nord, où elles peuvent localement être encore faciles à déclencher au passage d'un skieur. Dans les autres orientations et à plus basse altitude, elles sont rares et généralement difficiles à déclencher, car elles se stabilisent sous l'action du soleil et du redoux. Ces plaques sont généralement d'aspect durci par le vent, et en cas de rupture, peuvent provoquer des avalanches peu étendues, de taille petite à moyenne (taille 1 à 2).

Départs spontanés : peu probables en début de journée après un bon regel nocturne, puis rares départs de petite taille en neige humide. Départs ponctuels en pentes raides ensoleillées, généralement près des rochers.

Qualité de la neige

Enneigement excédentaire dans la Roya, proche des normales sur le reste du massif. Données observées : 157 cm à la Nivôse de Millefonts à 2430 m, 108 cm à Isola 2000 à 1912 m.

Enneigement skiable : vers 1400 m en ubacs, 1700/1800 m en adrets peu pentus.

État de la neige en surface : très bon regel nocturne. En versants ensoleillés, neige souvent croûtée. Dans les versants ombragés, la neige reste froide au dessus de 2000/2200 m environ, encore assez légère dans les combes abritées du vent, mais de plus en plus travaillée et durcie par le vent de nord dans les secteurs exposés.

Aperçu météo pour le samedi 28 mars

	nuit	matin	après-midi	soir
Pluie-Neige				1 600 m
Iso 0 °C	2 100 m	2 300 m	2 400 m	2 100 m
Vent 2000 m	↘ 10 km/h	↙ 15 km/h	↑ 20 km/h	↓ 20 km/h
Vent 3000 m	↘ 25 km/h	↓ 25 km/h	↘ 25 km/h	← 25 km/h

Bien ensoleillé le matin, puis se voilant l'après-midi. Nuageux la nuit suivante avec quelques faibles averses de neige, principalement frontalières.

Épaisseur de neige hors-piste

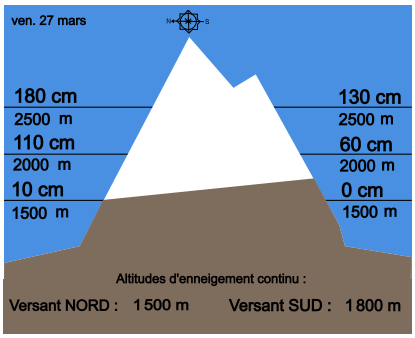

Précipitations à 1800 m

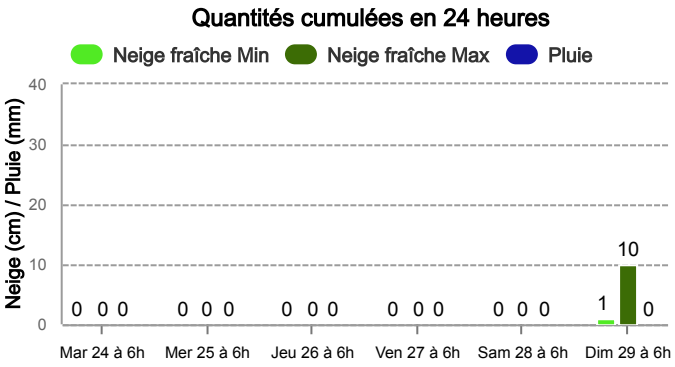

Tendance du dimanche 29 mars

2

Indice de risque limité

Maintien d'un risque limité avec quelques plaques en place, et quelques nouvelles possibles dans la neige fraîche modérément ventée.

Pour consulter la vigilance en cours, veuillez vous rendre sur le site https://vigilance.meteofrance.fr/fr

Météo-France - 73 avenue de Paris, 94165 Saint-Mandé cedex - Contact : contact@meteo.fr

Rédigé par Météo-France avec la contribution des observateurs du réseau nivo-météorologiques. Partenariat : ANMSM (Maires de Stations de Montagne), DSF (Domaines Skiables de France), ADSP (Directeurs de Pistes et de la Sécurité des Stations de Sports d'Hiver) et autres acteurs de la montagne.

Bulletin neige & avalanches par téléphone au 0 892 68 10 20 Service 0,35 € / min + prix appel

RÉPUBLIQUE FRANÇAISE
Liberté Égalité Fraternité

METEO FRANCE
À VOS CÔTÉS, DANS UN CLIMAT QUI CHANGE

Bulletin d'estimation du risque d'avalanche
(valable en dehors des pistes balisées et ouvertes)

MASSIF : Mercantour

Rédigé le vendredi 27 mars 2026 à 16h

Conditions nivo-météo des 7 derniers jours

	sam. 21/03				dim. 22/03				lun. 23/03				mar. 24/03				mer. 25/03				jeu. 26/03				ven. 27/03			
	03h	09h	15h	21h	03h	09h	15h	21h	03h	09h	15h	21h	03h	09h	15h	21h	03h	09h	15h	21h	03h	09h	15h	21h	03h	09h	15h	21h
Météo																												
Vent (km/h)	15	15	20	10	15	20	35	45	40	30	35	40	20	10	15	20	30	40	70	100	100	80	70	60	55	50	40	30
à 3000m																												
Vent (km/h)	5	10	15	5	5	10	25	30	30	20	25	25	20	10	10	10	10	20	50	80	80	65	65	60	60	65	40	25
à 2000m																												

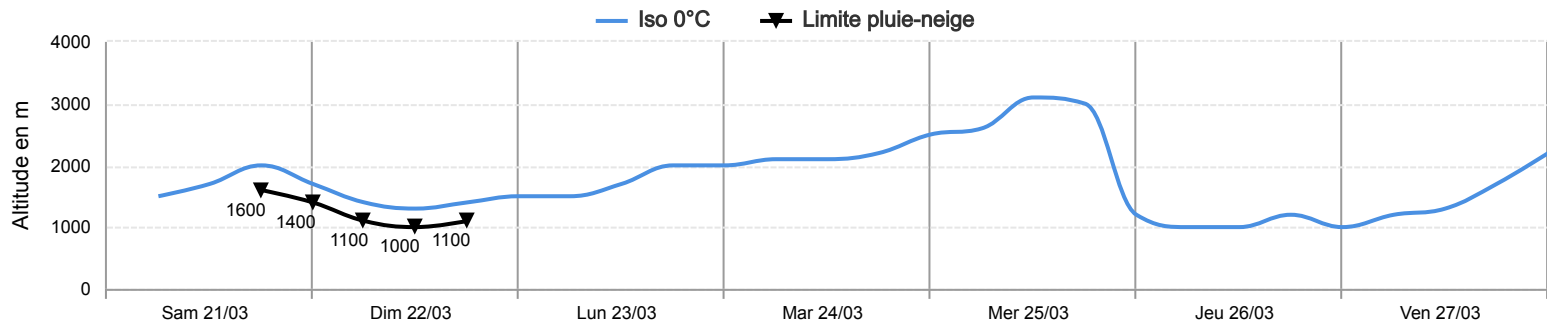

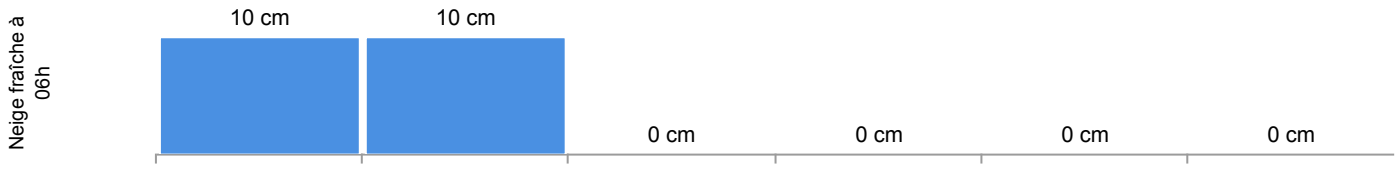

Risque d'avalanche	sam. 21/03	dim. 22/03	lun. 23/03	mar. 24/03	mer. 25/03	jeu. 26/03	ven. 27/03
	2	3	3	2	2	3	2

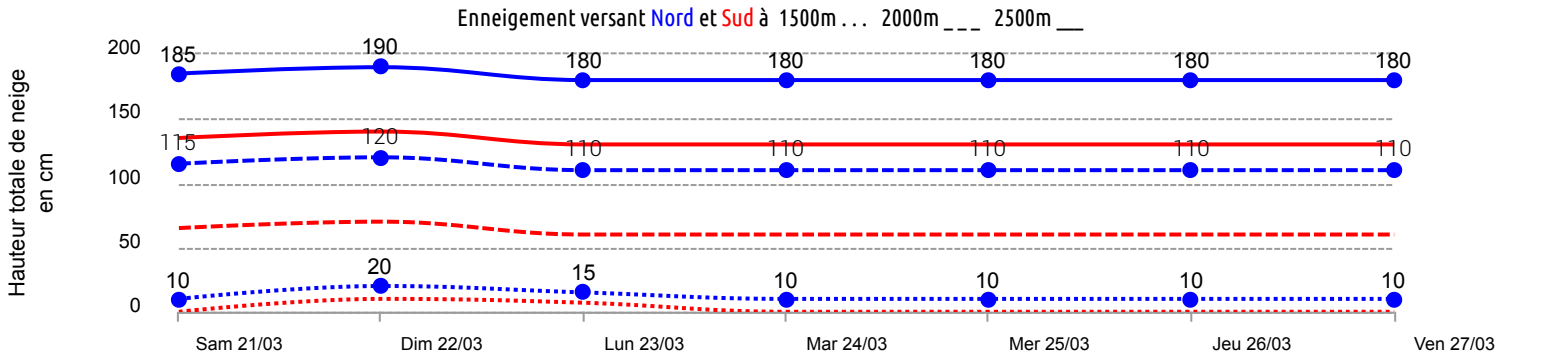

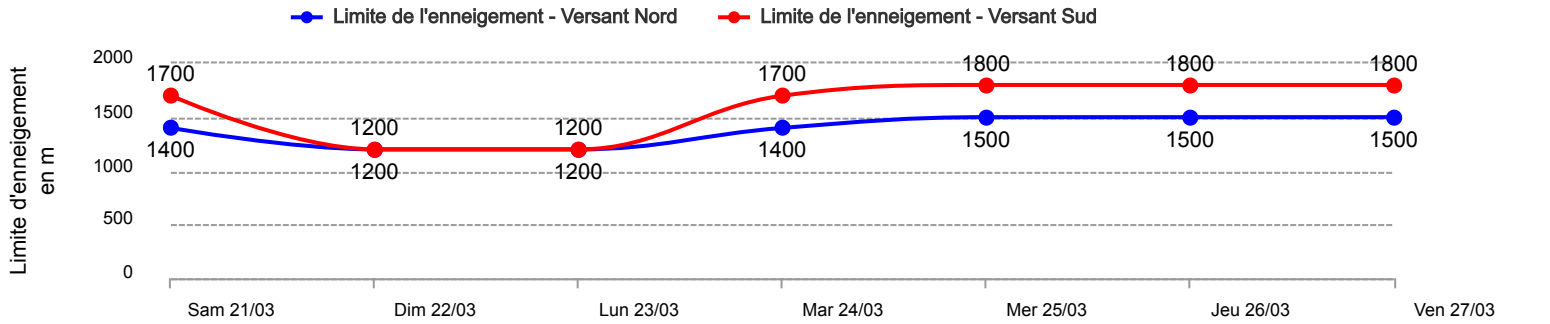

Pour consulter la vigilance en cours, veuillez vous rendre sur le site https://vigilance.meteofrance.fr/fr

Météo-France - 73 avenue de Paris, 94165 Saint-Mandé cedex - Contact : contact@meteo.fr

Bulletin neige & avalanches par téléphone au
0 892 68 10 20 Service 0,35 € / min + prix appel

Rédigé par Météo-France avec la contribution des observateurs du réseau nivo-météorologiques. Partenariat : ANMSM (Maires de Stations de Montagne), DSF (Domaines Skiables de France), ADSP (Directeurs de Pistes et de la Sécurité des Stations de Sports d'Hiver) et autres acteurs de la montagne.