Bulletin d'estimation du risque d'avalanche
(valable en dehors des pistes balisées et ouvertes)

MASSIF : Mont-Blanc

Rédigé le vendredi 27 mars 2026 à 16h

Estimation des risques pour le : SAMEDI 28 MARS

PLAQUES À VENT EN PERTE DE RÉACTIVITÉ

3

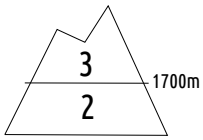

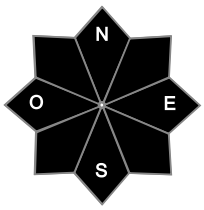

Au-dessus de 1700m indice de risque marqué, plus bas indice limité.

Départs spontanés : Peu probables

Déclenchements provoqués : Plaques à vent dans la neige récente

Indices de risque : 5 très fort - 4 fort - 3 marqué - 2 limité - 1 faible -- En noir : les pentes les plus dangereuses

Stabilité du manteau neigeux

Situation avalancheuse typique : neige ventée

Déclenchements provoqués :

* **Plaques à vent dans la neige récente**, majoritairement au-dessus de 1700 m, formées par le vent de Nord-Ouest à Nord-Est, **facilement déclenchables** par un skieur. Elles sont souvent friables mais peuvent être dures à proximité des crêtes. Taille 1 à 2 (petite à moyenne), rarement 3 (grande) à haute altitude. Cassures de 40/60 cm.
Observables : accumulations de neige, fissures sous les skis, transport de neige par le vent.
* Facteur aggravant : ces plaques à vent reposent parfois sur une sous-couche fragile persistante enfouie, au-dessus de 2200 m. Très difficile à déclencher par un skieur. Départ possible par chutes de corniches, séracs ou avalanches en cascade. Taille 2 (moyenne) et rarement 3 (grande) avec d'épaisses cassures.

Départs spontanés :
Peu probables.

Qualité de la neige

Enneigement :
Pour la saison, l'enneigement est correct.
Samedi matin, les sols sont blancs au-dessus de 900 m, mais il n'y a pas de sous-couches en dessous de 1200/1300 m en nord et 1500/1600 m en sud.

Qualité de la neige ce samedi matin :
30/60 cm de neige fraîche ventée. Souvent poudreuse dans les secteurs abrités du vent de Nord, ventée ailleurs, voire cartonnée ou glacée proche des crêtes ou dans certaines pentes Nord.
Nombreuses corniches, accumulations et congères en toutes orientations.

Aperçu météo pour le samedi 28 mars

	nuit	matin	après-midi	soir
Pluie-Neige				800 m
Iso 0 °C	800 m	1300 m	1300 m	1100 m
Vent 2000 m	↙ 30 km/h	↙ 30 km/h	↓ 20 km/h	↙ 40 km/h
Vent 4000 m	↓ 60 km/h	↓ 50 km/h	↘ 50 km/h	↘ 20 km/h

Le ciel se couvre rapidement en matinée, quelques flocons en deuxième partie d'après-midi. Temps froid.

Épaisseur de neige hors-piste

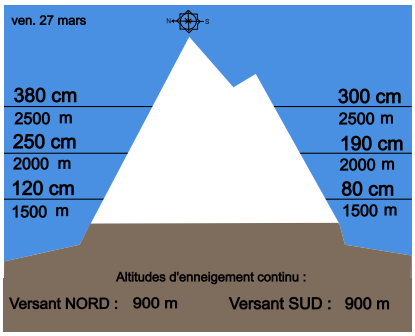

Précipitations à 1800 m

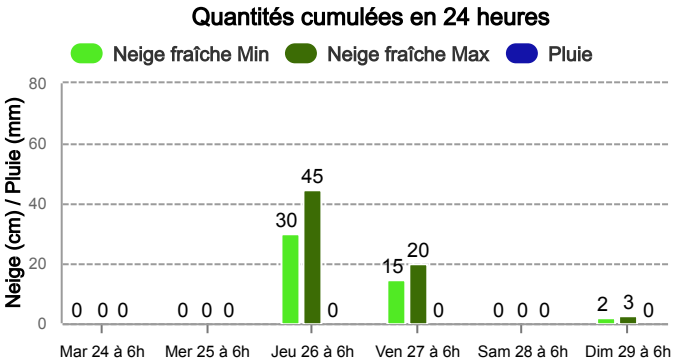

Tendance du dimanche 29 mars

2

Indice de risque limité

Faibles chutes de neige dans la nuit de samedi à dimanche, ne créant pas de nouvelles instabilités. Plaques à vent dans la neige récente toujours présente.

Pour consulter la vigilance en cours, veuillez vous rendre sur le site https://vigilance.meteofrance.fr/fr

Météo-France - 73 avenue de Paris, 94165 Saint-Mandé cedex - Contact : contact@meteo.fr

Rédigé par Météo-France avec la contribution des observateurs du réseau nivo-météorologiques. Partenariat : ANMSM (Maires de Stations de Montagne), DSF (Domaines Skiables de France), ADSP (Directeurs de Pistes et de la Sécurité des Stations de Sports d'Hiver) et autres acteurs de la montagne.

Bulletin neige & avalanches par téléphone au
0 892 68 10 20 Service 0,35 € / min + prix appel

RÉPUBLIQUE FRANÇAISE
Liberté Égalité Fraternité

METEO FRANCE
À VOS CÔTÉS, DANS UN CLIMAT QUI CHANGE

Bulletin d'estimation du risque d'avalanche

(valable en dehors des pistes balisées et ouvertes)

MASSIF : Mont-Blanc

Rédigé le vendredi 27 mars 2026 à 16h

Conditions nivo-météo des 7 derniers jours

	sam. 21/03				dim. 22/03				lun. 23/03				mar. 24/03				mer. 25/03				jeu. 26/03				ven. 27/03			
	03h	09h	15h	21h	03h	09h	15h	21h	03h	09h	15h	21h	03h	09h	15h	21h	03h	09h	15h	21h	03h	09h	15h	21h	03h	09h	15h	21h
Météo																												
Vent (km/h)	20	25	30	30	30	40	50	30	30	40	40	40	40	25	20	15	25	90	110	90	90	90	90	80	60	80	50	70
à 4000m																												
Vent (km/h)	10	10	10	10	15	25	30	20	20	15	10	10	5	5	5	5	10	50	60	50	50	50	40	35	40	50	30	20
à 2000m																												

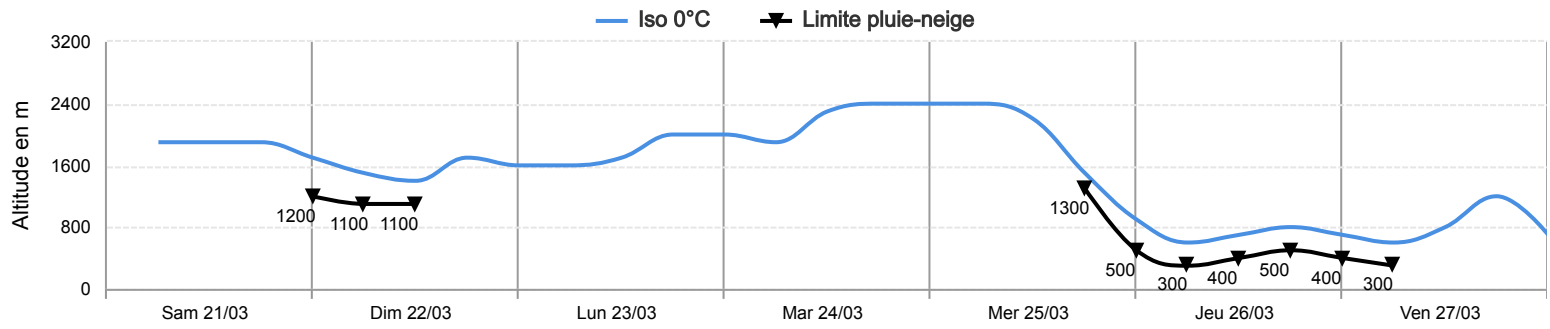

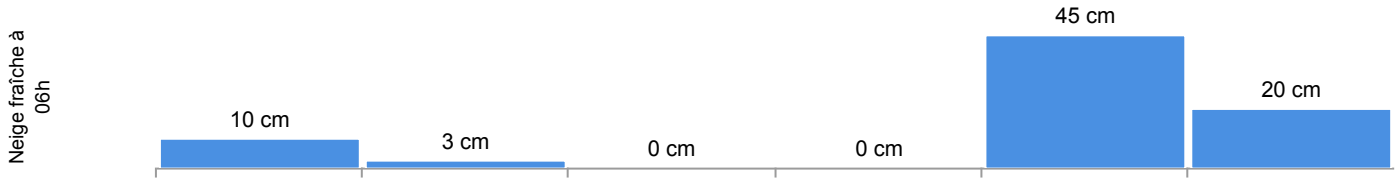

Risque d'avalanche	sam. 21/03	dim. 22/03	lun. 23/03	mar. 24/03	mer. 25/03	jeu. 26/03	ven. 27/03
	2	2	3	2	3	4	4

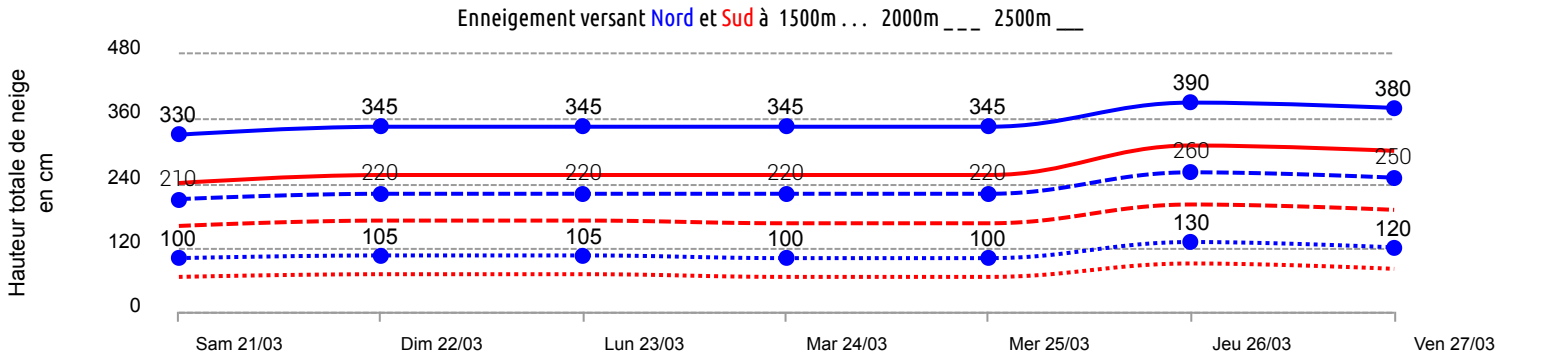

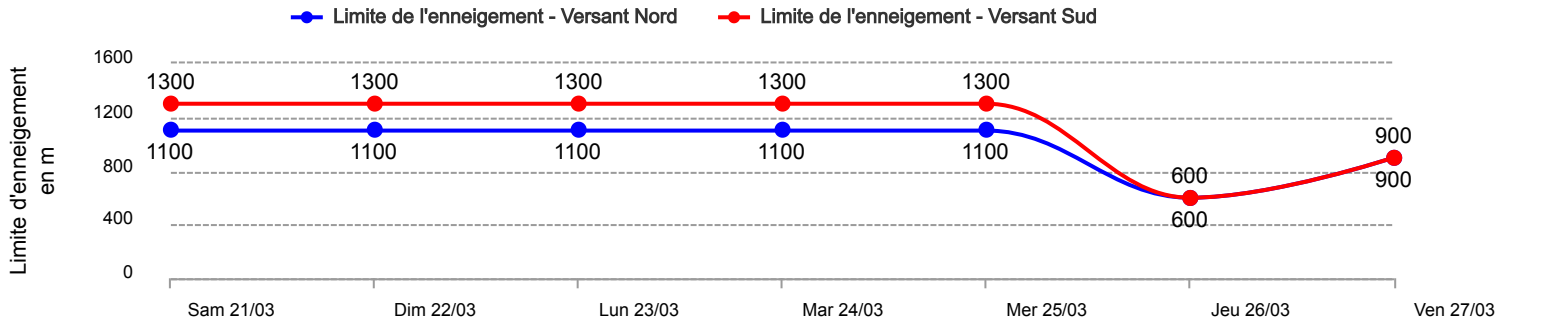

Pour consulter la vigilance en cours, veuillez vous rendre sur le site https://vigilance.meteofrance.fr/fr

Météo-France - 73 avenue de Paris, 94165 Saint-Mandé cedex - Contact : contact@meteo.fr

Rédigé par Météo-France avec la contribution des observateurs du réseau nivo-météorologiques. Partenariat : ANMSM (Maires de Stations de Montagne), DSF (Domaines Skiables de France), ADSP (Directeurs de Pistes et de la Sécurité des Stations de Sports d'Hiver) et autres acteurs de la montagne.

Bulletin neige & avalanches par téléphone au
0 892 68 10 20 Service 0,35 € / min + prix appel