GOBIERNO DE ESPAÑA
VICEPRESIDENCIA TERCERA DEL GOBIERNO
MINISTERIO PARA LA TRANSICIÓN ECOLÓGICA Y EL RETO DEMOGRÁFICO

Boletín de información nivológica y de peligro de aludes

Pirineo Catalán

aemet Agencia Estatal de Meteorología

sábado, 28 de marzo de 2026

Pronóstico hasta las 24 horas del domingo, día 29 de marzo

(Válido fuera de pistas de esquí balizadas y abiertas)

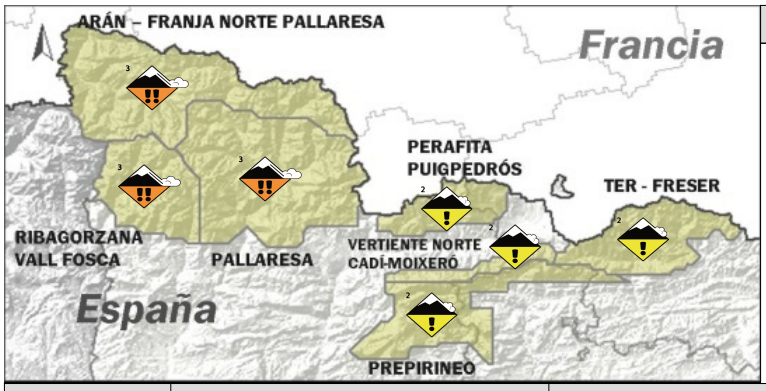

Problemas de aludes

Placas de viento

Nieve reciente

Macizo	Peligro	Problemas de aludes, cota, orientación, tamaño	Innivación observada (m)
Arán - Franja norte Pallaresa	3 Notable	Placas de viento: 2 Nieve reciente: 2	2026-03-28 Cota más baja caras N
Ribagorzana - Vall Fosca	3 Notable 2 → 3 Por la tarde	Placas de viento: 2 Nieve reciente: 2	2026-03-28 Cota más baja caras N
Pallaresa	3 Notable 2 → 3 Por la tarde	Placas de viento: 2 Nieve reciente: 2	2026-03-28 Cota más baja caras N

AEMET. Se autoriza la reproducción de su contenido citando la fuente.

Boletín de información nivológica y de peligro de aludes

Pirineo Catalán

Perafita - Puigpedrós	**Limitado**	**Placas de viento** **Nieve reciente** 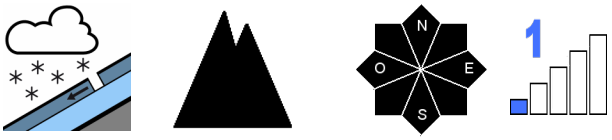	2026-03-28	Cota más baja caras N
Ter - Freser	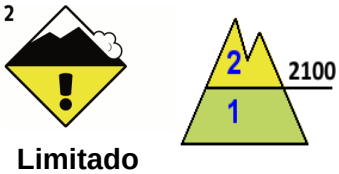 **Limitado**	**Placas de viento**	2026-03-28	Cota más baja caras N
Vertiente norte Cadí - Moixeró	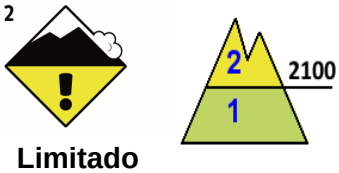 **Limitado**	**Placas de viento** 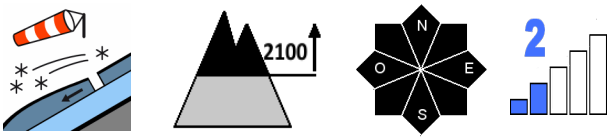	2026-03-28	Cota más baja caras N
Prepirineo	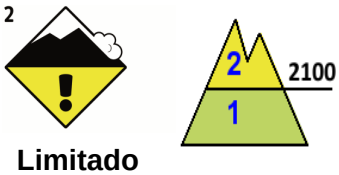 **Limitado**	**Placas de viento**	2026-03-28	Cota más baja caras N

Estado del manto y observaciones recientes

Durante las últimas 24 h solo se han registrado precipitaciones muy débiles en el Arán-F.N Pallaresa, con flujo intenso de norte, transporte de la nieve seca y enfriamiento de la húmeda. El manto ha quedado endurecido o encostrado de manera generalizada en todas las cotas y orientaciones. En cotas altas, se han formado pequeñas placas de viento en orientación sur, al tiempo que en los sitios más resguardados se puede encontrar una delgada capa de nieve reciente, todo esto especialmente en el Arán-F.N.Pallaresa. En umbrías de cotas altas, todavía pueden existir capas débiles internas que pueden colapsar ante sobrecargas fuertes.
En cuanto su continuidad, el manto se inicia en cotas medias, algo más arriba en las laderas norte que en las sur. Los espesores siguen estando muy por encima de lo habitual para la época, superándose los 150-200 cm en cota 2200 en la mayoría de zonas.

Evolución del manto y peligro de aludes para el domingo, día 29

Problemas de nieve reciente y de placas de viento en cotas altas.

A partir de esta tarde se inicia un episodio de nieve acompañado de viento fuerte o muy fuerte de componente norte.
En el Arán-F.N.Pallaresa se espera una acumulación de nieve en 24 h de 20 cm en todas las cotas. En los macizos ilerdenses, de 10 cm por encima de 1000 m en el norte de la zona, pero la cota de nieve bajará hasta 400 m. En cotas altas, acompañadas las nevadas de ventisca, podrán superarse los 30-35 cm en el Arán-F.N. Pallaresa, 15-20 cm en los macizos ilerdenses y 10 cm en el Perafita-Puigpedrós. En el resto, no se esperan acumulaciones superiores a los

AEMET. Se autoriza la reproducción de su contenido citando la fuente.

5 cm.
Con el paso de las horas se irán formando numerosas placas de viento con mal contacto sobre el manto previo endurecido, incluso en cotas medias y en todas las orientaciones, más probables en orientaciones sur, este y oeste. Se irán engrosando y siendo más sensibles, capaces de colapsar accidentalmente ante sobrecargas débiles o de forma natural incluso y serán susceptibles de desencadenar aludes de tamaño pequeño o mediano, localmente grande en el Arán si implican capas débiles internas.
Se esperan también aludes naturales de nieve reciente, en cualquier cota y orientación, en vertientes inclinadas menos expuestas a la acción del viento. Los aludes serán de tamaño pequeño o mediano.

Predicción meteorológica para el domingo, día 29

Predominio de muy nuboso o cubierto en el Pirineo occidental, con visibilidad localmente reducida. Intervalos nubosos en la mitad oriental.
Nevadas débiles o moderadas, más frecuentes e intensas en el Arán y norte de la Pallaresa, donde podrán ser localmente persistentes, y con baja probabilidad en el Ripollés y Prepirineo.
Temperaturas en descenso, ligero o moderado de las mínimas y notable de las máximas. Heladas débiles o moderadas, fuertes y persistentes en cotas altas. Ambiente gélido.
Viento fuerte o muy fuerte de componente norte, con rachas en cotas altas y zonas expuestas que podrán superar los 100 km/h en el Pirineo de Lleida y ser huracanadas en el de Girona y Prepirineo.

Datos en la atmósfera libre:

Altitud de la isoterma de 0 ºC: 1000 m
Altitud de la isoterma de -10 ºC: 2200 m

Viento a 1500 m: N 80 km/h
Viento a 3000 m: N 100 km/h

Evolución para el lunes día 30

Nivel de peligro sin cambios o en ligero ascenso.

Escala europea de peligro de aludes

Débil | Limitado | Notable | Fuerte | Muy Fuerte

Problemas de aludes

Nieve reciente | Placas de viento | Capas débiles persistentes | Nieve húmeda | Deslizamientos basales | Sin problema evidente

Nota1: Se recuerda que, siempre que haya nieve, la ausencia total de peligro no existe. Hay que tener presente que en circunstancias desfavorables, con aludes de tamaño 1 (alud pequeño o colada) y tamaño 2 (alud mediano), se pueden sufrir severos daños personales.
Nota2: Los BPA se elaboran en base a información meteorológica así como al estado del manto nivoso a través de sondeos puntuales. Se advierte a los usuarios de la variabilidad de esta información al extrapolarla a zonas extensas de montaña. Por ello, AEMET no se hace responsable de su uso para la toma de decisiones que conciernen a la seguridad personal, ni de los riesgos físicos o materiales de ellas derivadas.

AEMET. Se autoriza la reproducción de su contenido citando la fuente.