GOBIERNO DE ESPAÑA
VICEPRESIDENCIA TERCERA DEL GOBIERNO
MINISTERIO PARA LA TRANSICIÓN ECOLÓGICA Y EL RETO DEMOGRÁFICO

Boletín de información nivológica y de peligro de aludes

Pirineo Navarro y Aragonés

aemet Agencia Estatal de Meteorología

sábado, 28 de marzo de 2026

Pronóstico hasta las 24 horas del domingo, día 29 de marzo

(Válido fuera de pistas de esquí balizadas y abiertas)

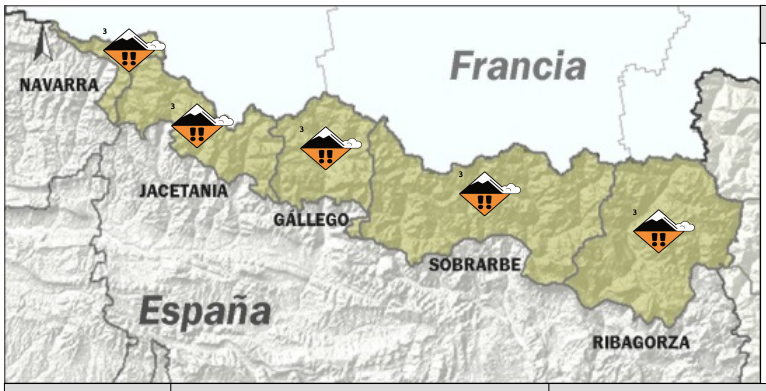

Problemas de aludes

Placas de viento

Nieve reciente

Macizo	Peligro	Problemas de aludes, cota, orientación, tamaño	Innivación observada (m)
Navarra	3 3 / 2 — 1800 Notable	Placas de viento 1800 N O E S 2 Nieve reciente N O E S 2	2026-03-28 N S Cota más baja caras N
Jacetania	3 3 / 2 — 1800 Notable	Placas de viento 1800 N O E S 2 Nieve reciente N O E S 2	2026-03-28 N S Cota más baja caras N
Gállego	3 3 / 2 — 1800 Notable	Placas de viento 1800 N O E S 2 Nieve reciente N O E S 2	2026-03-28 N S Cota más baja caras N

AEMET. Se autoriza la reproducción de su contenido citando la fuente.

Boletín de información nivológica y de peligro de aludes

Pirineo Navarro y Aragonés

Sobrarbe	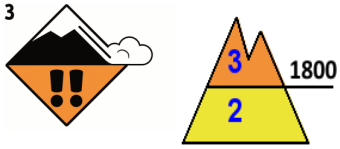 **Notable**	**Placas de viento** **Nieve reciente** 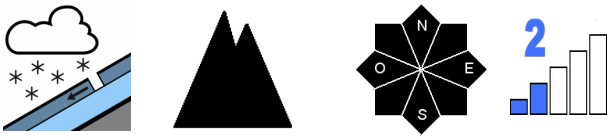	2026-03-28 Cota más baja caras N
Ribagorza	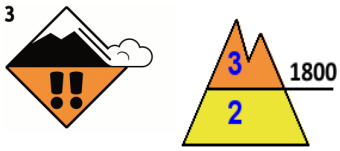 **Notable**	**Placas de viento** 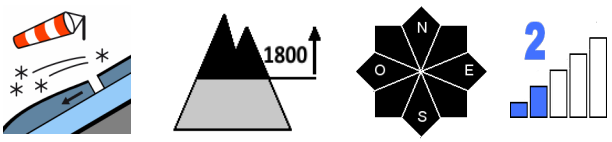 **Nieve reciente** 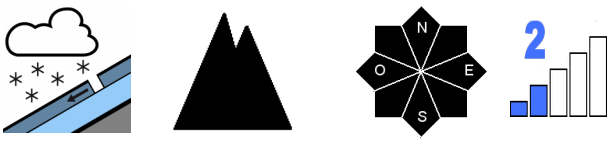	2026-03-28 Cota más baja caras N

Estado del manto y observaciones recientes

Durante las últimas 24 h solo se han registrado precipitaciones muy débiles en la Ribagorza, con flujo intenso de norte, transporte de la nieve seca y enfriamiento de la húmeda. El manto ha quedado endurecido o encostrado de manera generalizada en todas las cotas y orientaciones. En cotas altas, se han formado pequeñas placas de viento en orientación sur, al tiempo que en los sitios más resguardados se puede encontrar una delgada capa de nieve reciente, todo esto especialmente en Navarra y Jacetania. Las capas débiles internas que persistían en umbrías de cotas altas se muestran más difíciles de desencadenar. Además, se están formando facetas en superficie, asegurando una mala cohesión con la nieve nueva que está por caer.
En cuanto a su continuidad, el manto se inicia en cotas medias, algo más arriba en laderas norte (1600 m) que en las sur (1800 m). Los espesores siguen estando por encima de lo habitual para la época, con valores de 100-200 cm en cota 2200 y superiores por encima.
No se han reportado aludes en las últimas 24 h.

Evolución del manto y peligro de aludes para el domingo, día 29

Problemas de nieve reciente y de placas de viento en cotas altas.

A partir de esta tarde se inicia un episodio de nieve acompañado de viento fuerte o muy fuerte de componente norte.
En el Pirineo navarro se espera una acumulación de nieve en 24 h de 5 cm a partir de 800 m. En el sector aragonés, de 10 cm por encima de 1000 m, pero la cota de nieve bajará hasta 500 m. En cotas altas, acompañadas las nevadas de ventisca, podrán superarse los 15 cm en el sector navarro y 20-25 cm en el aragonés.
Con el paso de las horas se irán formando numerosas placas de viento con mal contacto sobre el manto previo endurecido, incluso en cotas medias por encima de los 1800 m y en todas las orientaciones, más probables en orientaciones sur, este y oeste. Se irán engrosando

AEMET. Se autoriza la reproducción de su contenido citando la fuente.

y siendo más sensibles, capaces de colapsar accidentalmente ante sobrecargas débiles o de forma natural incluso y serán susceptibles de desencadenar aludes de tamaño pequeño o mediano, localmente grande si implican capas débiles internas.
Se esperan también aludes naturales de nieve reciente, en cualquier cota y orientación, en vertientes inclinadas menos expuestas a la acción del viento. Los aludes serán de tamaño pequeño o mediano.

Predicción meteorológica para el domingo, día 29

Pirineo navarro:
Predominio de muy nuboso o cubierto, con visibilidad localmente reducida.
Precipitaciones débiles o moderadas, que serán de nieve a cualquier cota, remitiendo al final del día.
Temperaturas en ligero o moderado descenso. Heladas débiles o moderadas, fuertes y persistentes en cotas altas. Ambiente gélido.
Viento fuerte o muy fuerte de componente norte, con rachas en cotas altas y zonas expuestas que podrán superar los 100 km/h.
Pirineo aragonés:
Predominio de muy nuboso o cubierto, con visibilidad localmente reducida, con tendencia abrir claros al sur de la divisoria fronteriza al final del día.
Nevadas débiles o moderadas, más frecuentes e intensas en la divisoria con Francia donde podrán ser localmente persistentes, que tenderán a remitir al final del día.
Temperaturas en descenso, ligero o moderado de las mínimas y notable de las máximas. Heladas débiles o moderadas, fuertes y persistentes en cotas altas. Ambiente gélido.
Viento fuerte o muy fuerte de componente norte, con rachas incluso huracanadas en cotas altas y zonas expuestas.

Datos en la atmósfera libre:

Altitud de la isoterma de 0 ºC: 1000 m
Altitud de la isoterma de -10 ºC: 2000 m

Viento a 1500 m: N 80 km/h
Viento a 3000 m: N 100 km/h

Evolución para el lunes día 30

Nivel de peligro sin cambios o en ligero ascenso.

(Información elaborada a partir de los datos recibidos de los refugios de Lizara, Panticosa, Bachimaña, Góriz, Pineta, Estós, Angel Orús, La Renclusa y Cap de Llauset y de las estaciones de esquí de Astún y Panticosa (lagos))

Escala europea de peligro de aludes

Débil Limitado Notable Fuerte Muy Fuerte

Problemas de aludes

Nieve reciente Placas de viento Capas débiles persistentes Nieve húmeda Deslizamientos basales Sin problema evidente

Nota1: Se recuerda que, siempre que haya nieve, la ausencia total de peligro no existe. Hay que tener presente que en circunstancias desfavorables, con aludes de tamaño 1 (alud pequeño o colada) y tamaño 2 (alud mediano), se pueden sufrir severos daños personales.
Nota2: Los BPA se elaboran en base a información meteorológica así como al estado del manto nivoso a través de sondeos puntuales. Se advierte a los usuarios de la variabilidad de esta información al extrapolarla a zonas extensas de montaña. Por ello, AEMET no se hace responsable de su uso para la toma de decisiones que conciernen a la seguridad personal, ni de los riesgos físicos o materiales de ellas derivadas.

AEMET. Se autoriza la reproducción de su contenido citando la fuente.