Sonntag 29.03.2026

Veröffentlicht am 28.03.2026 um 17:00

Vormittag

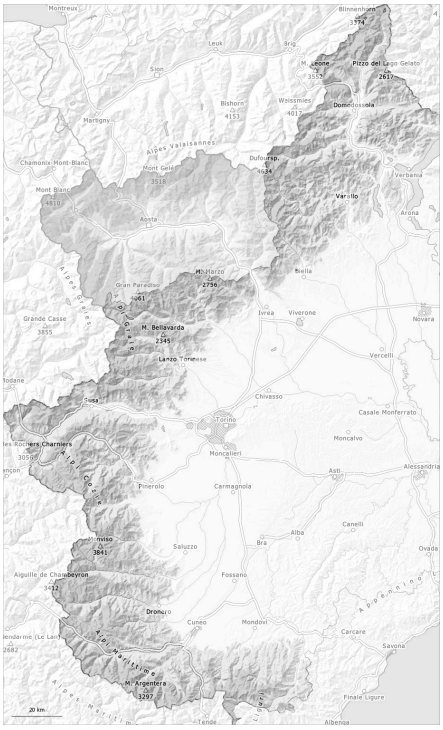

Nachmittag

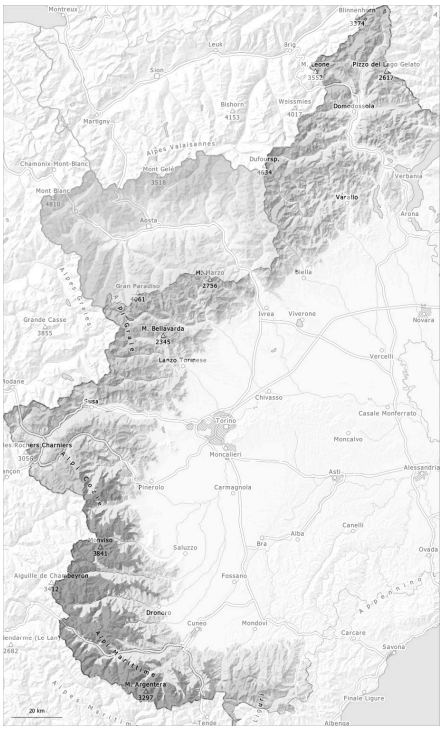

1	2	3	4	5
gering	mäßig	erheblich	groß	sehr groß

Gefahrenstufe 3 - Erheblich

AM:

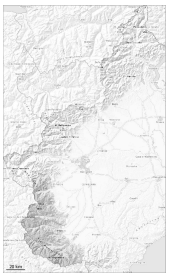

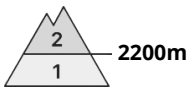

Tendenz: Lawinengefahr steigt
am Montag, den 30.03.2026

Triebschnee

Altschnee

PM:

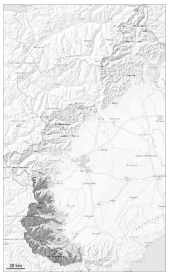

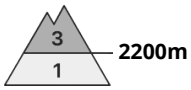

Tendenz: Lawinengefahr steigt
am Montag, den 30.03.2026

Triebschnee

Altschnee

Anstieg der Lawinengefahr mit Neuschnee und Wind.

Mit Neuschnee und mäßigem bis starkem Wind aus nordöstlichen Richtungen entstehen ab dem Vormittag weitere Triebschneeansammlungen. Die alten Triebschneeansammlungen vom Donnerstag werden überschneit und damit schwierig zu erkennen.

Die frischen Triebschneeansammlungen können stellenweise schon von einzelnen Wintersportlern ausgelöst werden. Die Lawinen können vor allem an steilen Hängen in den verschiedenen Triebschneeschichten anreißen und recht groß werden.

Touren erfordern Zurückhaltung.

Schneedecke

Gefahrenmuster gm.6: lockerer schnee und wind

Ab dem Morgen fallen gebietsweise oberhalb von rund 1600 m 10 bis 15 cm Schnee.

Mit Neuschnee und mäßigem bis starkem Wind aus nordöstlichen Richtungen entstehen weitere Triebschneeansammlungen. Hohe Lagen und Hochgebirge: Verschiedene Triebschneeschichten liegen

verbreitet auf einer harten Kruste.

Vor allem in Gipfellagen liegen je nach Windeinfluss sehr unterschiedliche Schneehöhen.

In der Altschneedecke sind v.a. an Schattenhängen kantig aufgebaute Schwachschichten vorhanden.

Tendenz

Mit dem teils starken Nordostwind nimmt die Anzahl der Gefahrenstellen am Montag zu.

Gefahrenstufe 2 - Mäßig

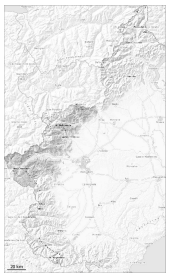

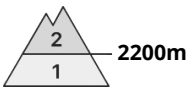

Tendenz: Lawinengefahr bleibt gleich
am Montag, den 30.03.2026

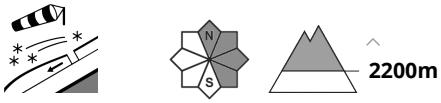

Triebschnee

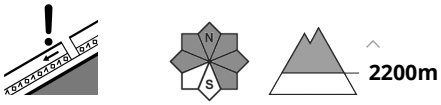

Altschnee

Die Triebschneeansammlungen sind vorsichtig zu beurteilen.

Mit Nordwestwind entstanden bis am Donnerstag, 26. März Triebschneeansammlungen. Die harten Triebschneeansammlungen liegen vor allem an Sonnenhängen und in hohen Lagen auf einer Kruste. Diese können vereinzelt schon von einzelnen Wintersportlern ausgelöst werden und mittlere Größe erreichen.

Die Gefahrenstellen liegen vor allem in Rinnen und Mulden sowie an Triebschneehängen. Entlang der Grenze zu Frankreich ist die Auslösebereitschaft höher.

Schneedecke

Gefahrenmuster gm.6: lockerer schnee und wind

Der Triebschnee liegt verbreitet auf einer harten Kruste, besonders an Sonnenhängen in allen Höhenlagen und in Kamm- und Passlagen in der Höhe.

Hohe Lagen Schattenhänge: Der untere Teil der Schneedecke ist kantig aufgebaut.
Im mittleren Teil der Schneedecke sind besonders an West-, Nord- und Nordosthängen einzelne Schwachschichten vorhanden.

An sonnigeren Hängen, wo die Temperaturen weniger kalt sind, wird die harte Oberfläche der Schneedecke im Tagesverlauf langsam weicher.

V.a. in Kammlagen in hohen Lagen liegen je nach Windeinfluss sehr unterschiedliche Schneehöhen.

Gefahrenstufe 2 - Mäßig

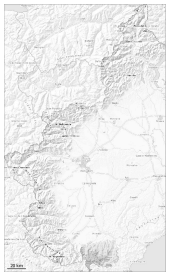

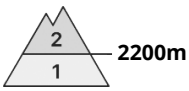

Tendenz: Lawinengefahr bleibt gleich
am Montag, den 30.03.2026

Triebschnee

2200m

Triebschnee ist die Hauptgefahr.

Heute fallen lokal oberhalb von rund 1700 m 5 bis 10 cm Schnee.
Mit Neuschnee und Wind aus nordöstlichen Richtungen entstehen eher kleine Triebschneeansammlungen. Die alten Triebschneeansammlungen der letzten Tage werden teils überschneit und damit schwierig zu erkennen. Diese können stellenweise vor allem mit großer Belastung ausgelöst werden.

Ungünstig sind Triebschneehänge, wo harte Schichten auf schwach verfestigtem Altschnee liegen.

Schneedecke

Gefahrenmuster gm.6: lockerer schnee und wind

Hohe Lagen und Hochgebirge: Neu- und Triebschnee liegen verbreitet auf einer harten Kruste.

Vor allem in Gipfellagen liegen je nach Windeinfluss sehr unterschiedliche Schneehöhen.

In der Altschneedecke sind v.a. an Schattenhängen einzelne Schwachschichten vorhanden.

Gefahrenstufe 2 - Mäßig

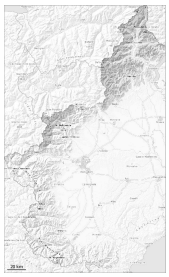

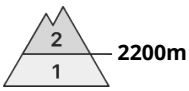

Tendenz: Lawinengefahr bleibt gleich
am Montag, den 30.03.2026

Triebschnee

Altschnee

Vorsicht vor Triebschnee.

Die harten Triebschneeansammlungen der letzten vier Tage liegen vor allem an Sonnenhängen und in hohen Lagen auf einer Kruste. Diese können weiterhin von einzelnen Wintersportlern ausgelöst werden. Die Lawinen können vor allem an steilen Nord-, Nordost- und Nordwesthängen im kantig aufgebauten Altschnee ausgelöst werden und mittlere Größe erreichen.

Vorsicht vor allem an Triebschneehängen und in Rinnen und Mulden in der Höhe.

Schneedecke

Gefahrenmuster gm.6: lockerer schnee und wind

Mit starkem Nordwestwind entstanden in den letzten Tagen Triebschneeansammlungen. Der Triebschnee liegt verbreitet auf einer harten Kruste. Die Schneeoberfläche weicht später auf als am Vortag.

Im unteren Teil der Schneedecke sind v.a. an Schattenhängen kantig aufgebaute Schwachschichten vorhanden.

In Kammlagen in hohen Lagen liegen je nach Windeinfluss sehr unterschiedliche Schneehöhen.