aineva.it

Sonntag 29.03.2026

Veröffentlicht am 28.03.2026 um 17:00

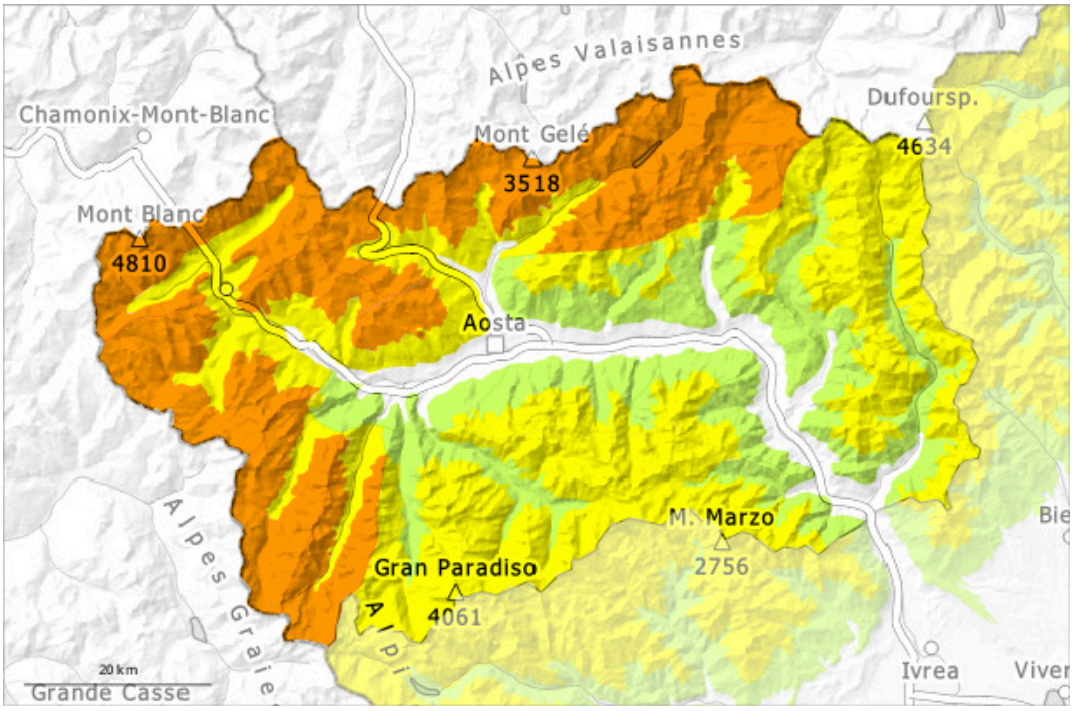

1	2	3	4	5
gering	mäßig	erheblich	groß	sehr groß

Gefahrenstufe 3 - Erheblich

Tendenz: Lawinengefahr bleibt gleich
am Montag, den 30.03.2026

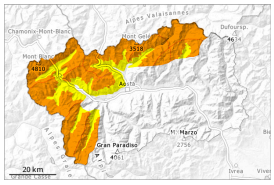

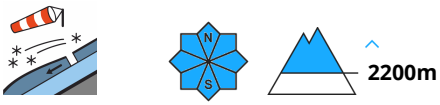

Triebschnee

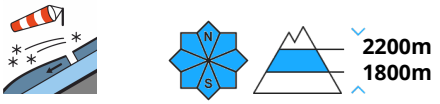

Triebschnee

Triebschnee ist die Hauptgefahr.

Mit Neuschnee und starkem bis stürmischem Wind aus nördlichen Richtungen entstanden auch kammfern umfangreiche Triebschneeansammlungen. Entlang der Grenze zu Frankreich und entlang der Grenze zur Schweiz sind diese Gefahrenstellen häufiger. Sie werden teils überschneit und damit schwierig zu erkennen.
Bis Sonntag fallen lokal oberhalb von rund 1800 m 2 bis 5 cm Schnee, lokal auch mehr. Stellenweise wachsen die Triebschneeansammlungen im Tagesverlauf etwas an. Sie können ausgelöst werden, Vorsicht an Übergängen von wenig zu viel Schnee wie z.B. bei der Einfahrt in Rinnen und Mulden. Wummgeräusche und Risse beim Betreten der Schneedecke können auf die Gefahr hinweisen.
Trockene Lawinen können mittlere Größe erreichen.
Touren erfordern Vorsicht und Zurückhaltung.

Schneedecke

Gefahrenmuster gm.6: lockerer schnee und wind

Am Donnerstag fielen oberhalb von rund 2000 m 20 bis 30 cm Schnee, lokal auch weniger. Der Wind blies verbreitet stark bis stürmisch. Der Wind hat Neu- und Altschnee intensiv verfrachtet. Verbreitet liegen je nach Windeinfluss sehr unterschiedliche Schneehöhen.
Der obere Teil der Schneedecke ist hart, mit einer oft tragfähigen Kruste an der Oberfläche, v.a. in Kamm- und Passlagen.
Der obere Teil der Schneedecke ist weich, mit einer lockeren Oberfläche, besonders in windgeschützten Lagen.
In der Schneedecke sind v.a. an steilen Schattenhängen Schwachschichten vorhanden.

Tendenz

Am Montag fallen lokal oberhalb von rund 1600 m 5 bis 15 cm Schnee. Der Wind bläst stark. Vorsicht vor frischem Triebschnee. Diese Bedingungen verursachen eine leichte Zunahme der Gefahr.

Gefahrenstufe 2 - Mäßig

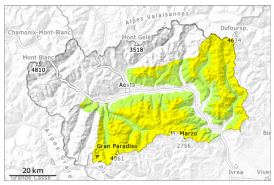

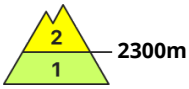

Tendenz: Lawinengefahr bleibt gleich
am Montag, den 30.03.2026

Triebschnee

Triebschnee ist die Hauptgefahr.

Der Nordwestwind hat Neu- und Altschnee intensiv verfrachtet. Triebschneeansammlungen können stellenweise von einzelnen Wintersportlern ausgelöst werden und mittlere Größe erreichen. Bis Sonntag fallen lokal oberhalb von rund 1800 m 2 bis 5 cm Schnee, lokal auch weniger. Die Triebschneeansammlungen werden teils überschneit und damit schwierig zu erkennen, Vorsicht an Übergängen von wenig zu viel Schnee wie z.B. bei der Einfahrt in Rinnen und Mulden.
Touren erfordern Vorsicht.

Schneedecke

Gefahrenmuster gm.6: lockerer schnee und wind

Bis Sonntag fallen lokal oberhalb von rund 1800 m 2 bis 5 cm Schnee, lokal auch weniger.
Am Donnerstag fielen oberhalb von rund 2000 m 5 bis 10 cm Schnee, lokal auch weniger.
Der Wind blies verbreitet stark bis stürmisch. Der Wind hat Neu- und Altschnee intensiv verfrachtet.
Verbreitet liegen je nach Windeinfluss sehr unterschiedliche Schneehöhen.
Der obere Teil der Schneedecke ist hart, mit einer oft tragfähigen Kruste an der Oberfläche, v.a. in Kamm- und Passlagen.
Der obere Teil der Schneedecke ist weich, mit einer lockeren Oberfläche, besonders in windgeschützten Lagen.
In der Schneedecke sind v.a. an steilen Schattenhängen Schwachschichten vorhanden.

Tendenz

Am Montag fallen lokal oberhalb von rund 1600 m 2 bis 5 cm Schnee. Der Wind bläst stark. Triebschnee.
Diese Bedingungen verursachen eine leichte Zunahme der Gefahr von trockenen Lawinen.