ICGC Institut Cartogràfic i Geològic de Catalunya

Servei Meteorològic de Catalunya meteo.cat

Boletín de peligro de aludes para el Pirineo de Catalunya
Del 28/03/2026 al 30/03/2026

(Válido fuera pistas de esquí y zonas no controladas)

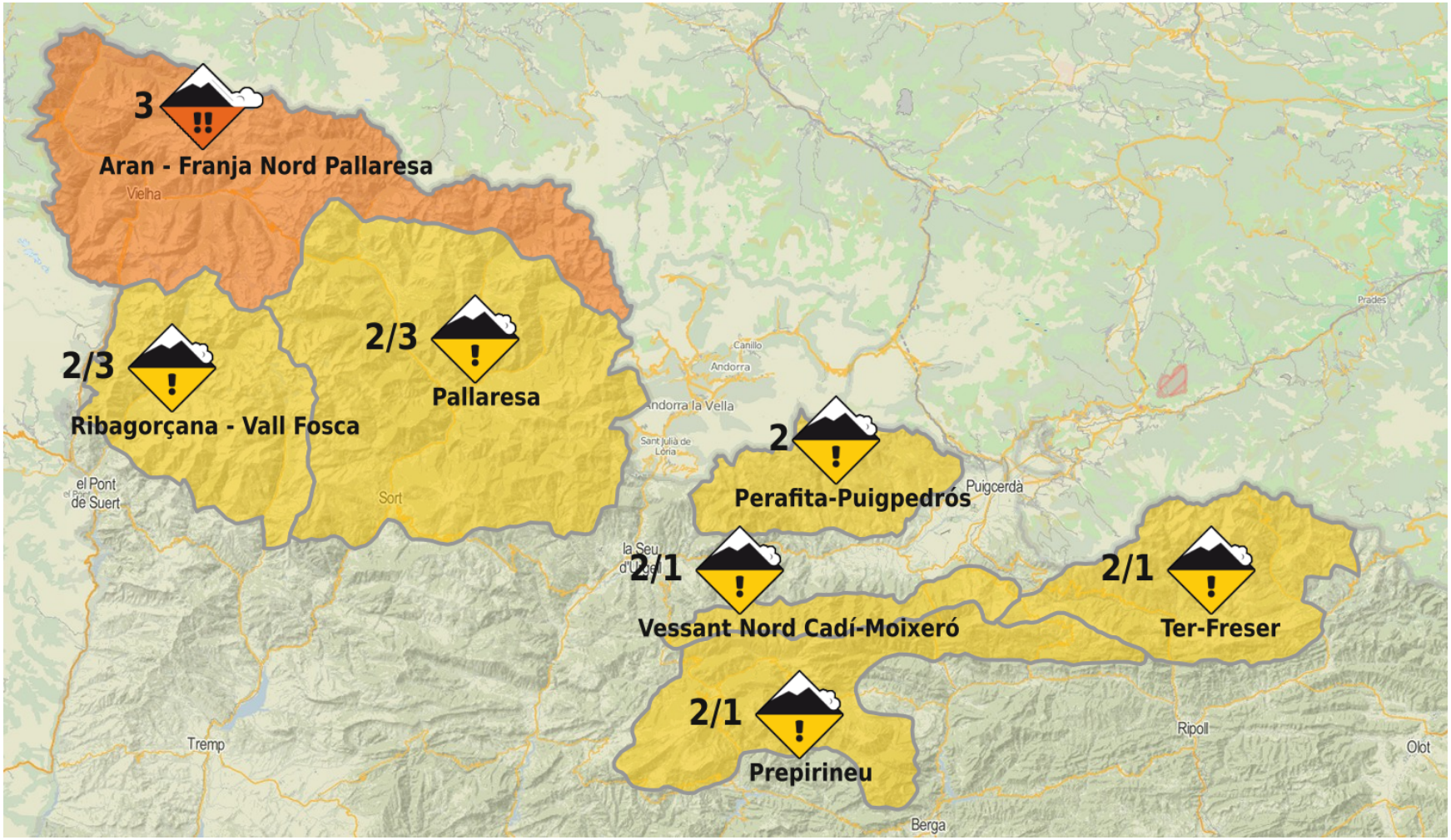

5 MUY FUERTE	4 FUERTE	3 NOTABLE	2 LIMITADO	1 DÉBIL

ICGC Institut Cartogràfic i Geològic de Catalunya

meteo.cat Servei Meteorològic de Catalunya

Boletín de peligro de aludes Aran - Franja Nord Pallaresa Del 28/03/2026 al 30/03/2026

(Válido fuera pistas de esquí y zonas no controladas)

NOTABLE (3)

Situación primaria

Nieve venteada

Distribución

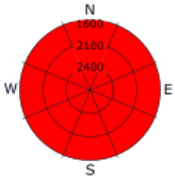

Tamaño

Origen

Tendencia

Situación secundaria

Nieve reciente

Distribución

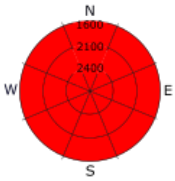

Tamaño

Origen

Tendencia

Estado del manto nivoso

El sábado tarde se inicia un episodio de viento y nieve que se alargará varios días.
El contacto entre la nieve nueva y el manto previo a menudo mantendrá un enlace pobre. Se formarán placas de viento en cualquier cota y orientación, donde el viento no barra la nieve. Las placas serán muy sensibles y se irán engrosando con el paso de las horas en las que irá aumentando la probabilidad de desencadenamiento de aludes, tanto natural como accidental. Los aludes de placa alcanzarán tamaño medio en general, localmente hasta tamaño grande, sobre todo si implican capas débiles internas.
Se esperan también aludes naturales de nieve reciente, en cualquier cota y orientación, en vertientes inclinadas menos expuestas a la acción del viento. Los aludes serán de tamaño pequeño o medio.
Las condiciones para las actividades de alta montaña son desfavorables por la inestabilidad del manto y la ventisca prevista.

Distribución del manto nivoso

Hay nieve por encima de unos 1.700 m en umbrías y 2.000 m en solanas. Los espesores a unos 2.200 m son ligeramente superiores a los normales en la Franja Norte de la Pallaresa y en la mitad sur de Arán, donde rondan los 180-220 cm. En la mitad norte de Arán son los normales por estas fechas con unos 120-140 cm de espesor total.

Tendencia para las próximas 48-72h

Continuarán las nevadas y el viento fuerte para los próximos días, engrosando las placas existentes y formando nuevas, aumentando las acumulaciones de nieve reciente. Peligro: en AUMENTO.

El próximo boletín será emitido el día 2026-03-30

5 MUY FUERTE	4 FUERTE	3 NOTABLE	2 LIMITADO	1 DÉBIL

EAWS EUROPEAN AVALANCHE WARNING SERVICES

ICGC Institut Cartogràfic i Geològic de Catalunya

meteo.cat Servei Meteorològic de Catalunya

Boletín de peligro de aludes Ribagorçana - Vall Fosca Del 28/03/2026 al 30/03/2026

(Válido fuera pistas de esquí y zonas no controladas)

LIMITADO (2) evolucionando a: NOTABLE (3) a final de domingo en el extremo N

Situación primaria

Nieve venteada

Distribución

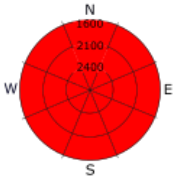

Tamaño

Origen

Tendencia

Situación secundaria

Nieve reciente

Distribución

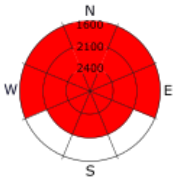

Tamaño

Origen

Tendencia

Estado del manto nivoso

El episodio de nieve que se inicia el sábado tarde irá acompañado de viento fuerte o muy fuerte de N y NW. La nieve reciente que no se lleve el viento caerá mayoritariamente sobre un manto endurecido superficialmente.
Se espera la formación de placas de viento con mal contacto sobre el manto previo. Las placas se podrán localizar en cualquier orientación, más probables en S y E, en cualquier cota, y bajo collados y cordales, y vertientes más resguardadas. Con el paso de las horas, las placas se irán engrosando y siendo más sensibles. Los aludes de placa se podrán desencadenar muy fácilmente de forma accidental, o natural sobre todo a finales del domingo, y serán de hasta tamaño medio en general.
También son posibles aludes naturales de nieve reciente, más probables en cotas medias y altas de cualquier orientación, en vertientes inclinadas no afectadas por viento. Los aludes serían de tamaño pequeño o medio.

Distribución del manto nivoso

Hay nieve en el suelo a 1.700 m en N, y a unos 2.100 m en S de forma discontinua, pasando a ser continua a partir de unos 2.300 m. Los grosores alcanzan los 100-120 cm a unos 2.200 m. Estos valores se acercan a los normales para la época.

Tendencia para las próximas 48-72h

Continuarán las débiles nevadas y el viento fuerte para los próximos días, engrosando levemente las placas existentes y formando nuevas. Peligro: en leve AUMENTO.

El próximo boletín será emitido el día 2026-03-30

5 MUY FUERTE	4 FUERTE	3 NOTABLE	2 LIMITADO	1 DÉBIL

EAWS EUROPEAN AVALANCHE WARNING SERVICES

ICGC Institut Cartogràfic i Geològic de Catalunya

Servei Meteorològic de Catalunya

Boletín de peligro de aludes Pallaresa
Del 28/03/2026 al 30/03/2026

(Válido fuera pistas de esquí y zonas no controladas)

LIMITADO (2) evolucionando a: NOTABLE (3) a final de domingo en el extremo N

Situación primaria

Nieve venteada

Distribución

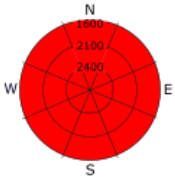

Tamaño

Origen

Tendencia

Situación secundaria

Nieve reciente

Distribución

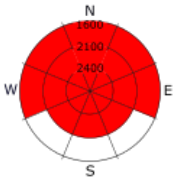

Tamaño

Origen

Tendencia

Estado del manto nivoso

El episodio de nieve que se inicia el sábado tarde irá acompañado de viento fuerte o muy fuerte de N y NW. La nieve reciente que no se lleve el viento caerá mayoritariamente sobre un manto endurecido superficialmente.
Se espera la formación de placas de viento con mal contacto sobre el manto previo. Las placas se podrán localizar en cualquier orientación, más probables en S y E, en cualquier cota, y bajo collados y cordales, y vertientes más resguardadas. Con el paso de las horas, las placas se irán engrosando y siendo más sensibles. Los aludes de placa se podrán desencadenar muy fácilmente de forma accidental, o natural sobre todo a finales del domingo, y serán de hasta tamaño medio en general.
También son posibles aludes naturales de nieve reciente, más probables en cotas medias y altas de cualquier orientación, en vertientes inclinadas no afectadas por viento. Los aludes serían de tamaño pequeño o medio.

Distribución del manto nivoso

Hay nieve en el suelo a 1.700 m en N, y a unos 2.100 m en S de forma discontinua, pasando a ser continua a partir de unos 2.300 m. Los espesores alcanzan los 110-150 cm en cotas medias, puntualmente más, variable según los efectos del viento.

Tendencia para las próximas 48-72h

Continuarán las débiles nevadas y el viento fuerte para los próximos días, engrosando levemente las placas existentes y formando nuevas. Peligro: en leve AUMENTO.

El próximo boletín será emitido el día 2026-03-30

5 MUY FUERTE	4 FUERTE	3 NOTABLE	2 LIMITADO	1 DÉBIL

EAWS EUROPEAN AVALANCHE WARNING SERVICES

ICGC Institut Cartogràfic i Geològic de Catalunya

Servei Meteorològic de Catalunya

Boletín de peligro de aludes Perafita-Puigpedrós Del 28/03/2026 al 30/03/2026

(Válido fuera pistas de esquí y zonas no controladas)

LIMITADO (2)

Situación primaria

Nieve venteada

Distribución

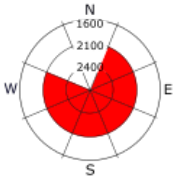

Tamaño

Origen

Tendencia

Estado del manto nivoso

A partir del sábado tarde se inicia un episodio de nieve, poco abundante, y viento fuerte o muy fuerte de N y NW. La nieve reciente que no se lleve el viento, en sectores más resguardados, se depositará sobre un manto endurecido.

Se podrán formar nuevas placas de viento, generalmente pequeñas pero hasta tamaño medio localmente, principalmente en S y E, menos probables en otras orientaciones, en cualquier cota pero más frecuentes en cotas medias y altas, preferentemente bajo collados y crestas y sectores resguardados. Estas placas serán reactivas al paso de una persona, sin descartar desencadenamientos naturales puntuales, provocando aludes de tamaño generalmente pequeño, o mediano en sectores más propicios de sobreacumulación y menos viento.

No se descarta, localmente, en laderas no afectadas por viento algún pequeño alud de nieve reciente.

Las condiciones no son favorables a las excursiones, con previsión de ventisca intensa.

Distribución del manto nivoso

Hay nieve por encima de unos 1.900 m, discontinua hasta 2.200 m en solanas. Es esquiable a partir de unos 2.000 m en N. Los espesores, aunque irregulares, rondan los 70-100 cm en umbrías, a 2.300 m. Son grosores por encima de los habituales en esta época.

Tendencia para las próximas 48-72h

Continuarán las débiles nevadas y el viento fuerte para los próximos días, engrosando levemente las placas existentes y formando nuevas. Peligro: en leve AUMENTO.

El próximo boletín será emitido el día 2026-03-30

5 MUY FUERTE	4 FUERTE	3 NOTABLE	2 LIMITADO	1 DÉBIL

EAWS EUROPEAN AVALANCHE WARNING SERVICES

ICGC Institut Cartogràfic i Geològic de Catalunya

Servei Meteorològic de Catalunya meteo.cat

Boletín de peligro de aludes Vessant Nord Cadí-Moixeró Del 28/03/2026 al 30/03/2026

(Válido fuera pistas de esquí y zonas no controladas)

LIMITADO (2) por encima del límite de bosque, DÉBIL (1) por debajo

Situación primaria

Nieve venteada

Distribución

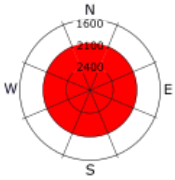

Tamaño

Origen

Tendencia

Estado del manto nivoso

El sábado por la tarde se prevé el inicio de un episodio de nieve y viento fuerte de N y NW que podrá alargarse varios días. Parte de la nieve reciente no se depositará sobre el manto, llevada por el viento, mientras que en lugares resguardados se podrán formar sobreacumulaciones de nieve venteada que descansarán sobre un manto endurecido.

Se podrán formar nuevas placas de viento, generalmente pequeñas pero hasta tamaño medio localmente, en cualquier orientación pero más probables en S y E, preferentemente por encima del límite de bosque y bajo collados y crestas y sectores resguardados, así como en las partes altas de las canales menos venteadas. Estas placas cederán fácilmente al paso de una persona provocando aludes de tamaño generalmente pequeño, o más localmente medio, en sectores más propicios de sobreacumulación y menos viento.

Las condiciones son desfavorables para las excursiones, con previsión de ventisca intensa y un manto endurecido y resbaladizo.

Distribución del manto nivoso

En umbrías hay presencia discontinua de nieve por encima de unos 1.700 m y es esquiable por encima de unos 1.900 m. Los grosores están alrededor de 160-180 cm a 2.200 m. Estos valores son muy excedentarios para la época del año.

Tendencia para las próximas 48-72h

Continuarán las débiles nevadas y el viento fuerte para los próximos días, engrosando levemente las placas existentes y formando nuevas. Peligro: en leve AUMENTO.

El próximo boletín será emitido el día 2026-03-30

5 MUY FUERTE	4 FUERTE	3 NOTABLE	2 LIMITADO	1 DÉBIL

EAWS EUROPEAN AVALANCHE WARNING SERVICES

ICGC Institut Cartogràfic i Geològic de Catalunya

meteo.cat Servei Meteorològic de Catalunya

Boletín de peligro de aludes Prepirineu
Del 28/03/2026 al 30/03/2026

(Válido fuera pistas de esquí y zonas no controladas)

LIMITADO (2) por encima del límite de bosque, DÉBIL (1) por debajo

Situación primaria

Nieve venteada

Distribución

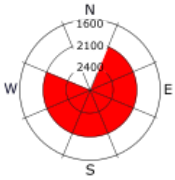

Tamaño

Origen

Tendencia

Estado del manto nivoso

A partir del sábado tarde se inicia un episodio de nieve, poco abundante, y viento fuerte o muy fuerte de N y NW.
La nieve reciente que no se lleve el viento, en sectores más resguardados, se depositará sobre un manto endurecido. Se podrán formar nuevas placas de viento, generalmente pequeñas pero hasta tamaño medio localmente, principalmente en S y E, menos probables y frecuentes en otras orientaciones, preferentemente por encima del límite de bosque y bajo collados y crestas y sectores resguardados. Estas placas se mostrarán reactivas al paso de una persona, pudiendo ceder y provocar aludes de tamaño generalmente pequeño, o más localmente medio, en sectores más propicios de sobreacumulación y menos ventosos.
Las condiciones no son favorables a las excursiones, con previsión de ventisca intensa y un manto endurecido y resbaladizo.

Distribución del manto nivoso

En umbrías hay nieve por encima de unos 1.700 m. En solanas la nieve está presente por encima de unos 1.900 m, discontinua. Los espesores, aunque irregulares, rondan los 90-120 cm a 2.300 m.

Tendencia para las próximas 48-72h

Continuarán las débiles nevadas y el viento fuerte para los próximos días, engrosando levemente las placas existentes y formando nuevas. Peligro: en leve AUMENTO.

El próximo boletín será emitido el día 2026-03-30

5 MUY FUERTE	4 FUERTE	3 NOTABLE	2 LIMITADO	1 DÉBIL

EAWS EUROPEAN AVALANCHE WARNING SERVICES

ICGC Institut Cartogràfic i Geològic de Catalunya

Servei Meteorològic de Catalunya meteo.cat

Boletín de peligro de aludes Ter-Freser
Del 28/03/2026 al 30/03/2026

(Válido fuera pistas de esquí y zonas no controladas)

LIMITADO (2) por encima del límite de bosque, DÉBIL (1) por debajo

Situación primaria

Nieve venteada

Distribución

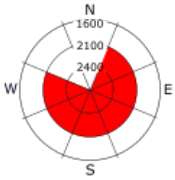

Tamaño

Origen

Tendencia

Estado del manto nivoso

A partir del sábado tarde se inicia un episodio de nieve, poco abundante, y viento fuerte o muy fuerte de N y NW.
La nieve reciente que no se lleve el viento, en sectores más resguardados, se depositará sobre un manto endurecido. Se podrán formar nuevas placas de viento, generalmente pequeñas pero hasta tamaño medio localmente, principalmente en S y E, menos probables y frecuentes en otras orientaciones, preferentemente por encima del límite de bosque y bajo collados y crestas y sectores resguardados. Estas placas se mostrarán reactivas al paso de una persona, pudiendo ceder y provocar aludes de tamaño generalmente pequeño, o más localmente medio, en sectores más propicios de sobreacumulación y menos venteados.
Las condiciones no son favorables a las excursiones, con previsión de ventisca intensa y un manto endurecido y resbaladizo.

Distribución del manto nivoso

Hay nieve en el suelo por encima de unos 1.700 m. El manto es esquiable en umbrías a partir de unos 1.800 m. Los grosores son muy excedentarios para la época del año y en lugares no afectados por el viento oscilan entre 70-90 cm a unos 2.000 m y más de 150 cm por encima de 2.400 m.

Tendencia para las próximas 48-72h

Continuarán las débiles nevadas y el viento fuerte para los próximos días, engrosando levemente las placas existentes y formando nuevas. Peligro: en leve AUMENTO.

El próximo boletín será emitido el día 2026-03-30

5 MUY FUERTE	4 FUERTE	3 NOTABLE	2 LIMITADO	1 DÉBIL

EAWS EUROPEAN AVALANCHE WARNING SERVICES