MINISTERO DELLA DIFESA

meteomont
Servizio Nazionale di previsione neve e valanghe

EAWS EUROPEAN AVALANCHE WARNING SERVICES

CARABINIERI

## ALPI COZIE NORD

Bollettino Valanghe N. 387/2026 del 28/03/2026 ore 14.00
Validità 48 ore prossima emissione 29/03/2026

**A cura del Servizio METEOMONT dell'ARMA dei CARABINIERI**
**In collaborazione con Servizio Meteorologico dell'Aeronautica militare**

## SITUAZIONE alle 14:00 del 28/03/2026

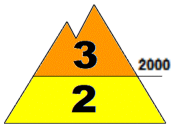


**SITUAZIONE TIPO: neve a debole coesione e vento.**

**SITUAZIONE TIPO: situazione primaverile.**

| Quota neve (mslm) | Nord | Sud |
|---|---|---|
| | 1300 - 1400 | 1600 - 1900 |

| Altezza Neve (cm) | Neve al suolo | Neve Fresca | Quota (mslm) |
|---|---|---|---|
| | 140 | 000 | 2280 |
| | 042 | 000 | 1540 |

**VALANGHE OSSERVATE: Valanghe di piccole dimensioni, Valanghe di neve a debole coesione di superficie.**

## PREVISIONI 29/03/2026

# GRADO DI PERICOLO: MARCATO 3

## SITUAZIONE TIPO: neve a debole coesione e vento.

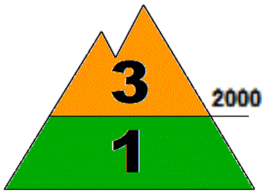





## SITUAZIONE TIPO: situazione primaverile.

**MANTO NEVOSO: La stabilità del manto nevoso è scarsa su molti punti (aree) per versanti da nord a sud compresi al di sopra di 2000 mslm, possibili valanghe di dimensioni medie.**
**La stabilità del manto nevoso è discreta su alcuni punti (aree) per versanti al sole al di sotto di 2000 mslm, possibili valanghe di dimensioni piccole.**

## AVVERTENZE

A seguito dell'attività eolica registrata sono da evitare le zone di accumulo, conche, canaloni, cambi di pendenza e pendii sotto vento in genere.

## SCALA EUROPEA DEL GRADO DI PERICOLO VALANGHE

## LEGENDA PROBLEMA

**Bollettino realizzato su scala sinottica-regionale (standard EAWS). La sua valutazione non può escludere in alcun modo la necessità di una seria e capace valutazione locale del pericolo (singolo pendio) che può essere anche sensibilmente diverso. Le previsioni meteorologiche sono relative all'orario UTC (per l'Italia +1 in inverno e +2 in estate).**

MINISTERO DELLA DIFESA

meteomont
Servizio Nazionale di previsione neve e valanghe

EAWS EUROPEAN AVALANCHE WARNING SERVICES

CARABINIERI

# ALPI COZIE NORD

## PREVISIONE METEO

| Quota | | 29/03/2026 h6:00 | 29/03/2026 h12:00 | 29/03/2026 h18:00 |
|---|---|---|---|---|
| 1000 | Venti | 01 nodi da N-Ovest | 01 Nodi da S-Est | 02 nodi da Ovest |
| | Temperature | -02 °C | +01 °C | +03 °C |
| | Temp.percepita | -2 °C | 1 °C | 3 °C |
| 2000 | Venti | 05 Nodi da N-Est | 02 Nodi da Est | 01 nodi da N-Ovest |
| | Temperature | -05 °C | -03 °C | -01 °C |
| | Temp.percepita | -9 °C | -3 °C | -1 °C |
| 3000 | Venti | 11 Nodi da Est | 05 Nodi da N-Est | 03 Nodi da Nord |
| | Temperature | -12 °C | -11 °C | -09 °C |
| | Temp.percepita | -20 °C | -16 °C | -12 °C |
| Zero termico | | 1200-1400 m. | 1600-1800 m. | 1800-2000 m. |
| Fenomeno | | | — | — |
| Stato del cielo | | | | |

## LEGENDA FENOMENI

— Assenza Fenomeni
Nebbia
Foschia
Pioggia debole
Pioggia moderata
Pioggia forte
Temporali
Nevicata debole
Nevicata moderata
Nevicata forte

## STATO DEL CIELO

Sereno
Poco nuvoloso
Nuvoloso
Molto nuvoloso
Coperto

## Parametri meteonivometrici registrati presso i campi di rilevamento il 28/03/2026.

| Località | Comune | Quota (m.s.l.m.) | Altezza neve (cm) | Neve caduta nelle 24 ore (cm) | Temp. Min (°C) | Temp. Max (°C) | Condizioni del tempo |
|---|---|---|---|---|---|---|---|
| PRINCIPI | Sestriere (TO) | 2000 | 103 | 0 | -2 | +8 | Assenza di precipitazioni |
| PRAGELATO | Pragelato (TO) | 1550 | 0 | 0 | -6 | +5 | Assenza di precipitazioni |
| COL BASSET * | Sestriere (TO) | 2524 | 120 | 0 | N.P. | N.P. | Assenza di precipitazioni |

(*) Rilievi fuori campo

**L'INFORMAZIONE E' PREVENZIONE - LEGGI L'ATTUALE GRADO DI PERICOLO VALANGHE!**

**IL CAPO DEL CENTRO NAZIONALE METEOMONT**
**(Ten. Col. RFI Emanuela Gini)**
**FIRMA AUTOGRAFA OMESSA AI SENSI**
**DELL'ART.3 DEL D.LGS N.39/1993**