MINISTERO DELLA DIFESA

meteomont
Servizio Nazionale di previsione neve e valanghe

EAWS EUROPEAN AVALANCHE WARNING SERVICES

CARABINIERI

AERONAUTICA MILITARE SERVIZIO METEOROLOGICO

GRAN SASSO EST - LAGA EST

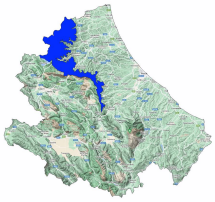

Bollettino Valanghe N. 375/2026 del 27/03/2026 ore 14.00
Validità 48 ore prossima emissione 28/03/2026

A cura del Servizio METEOMONT dell'ARMA dei CARABINIERI
In collaborazione con Servizio Meteorologico dell'Aeronautica militare

SITUAZIONE alle 14:00 del 27/03/2026

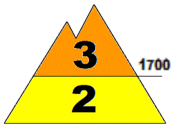

SITUAZIONE TIPO: neve a debole coesione e vento.

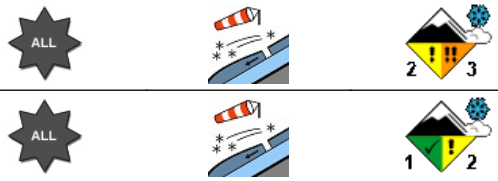

SITUAZIONE TIPO: neve a debole coesione e vento.

	Nord	Sud
Quota neve (mslm)	*700*	*700*

	Neve al suolo	Neve Fresca	Quota (mslm)
Altezza Neve (cm)	*055*	*037*	*1380*
	048	*031*	*1349*

VALANGHE OSSERVATE: -.

PREVISIONI 28/03/2026

GRADO DI PERICOLO: MARCATO 3

SITUAZIONE TIPO: neve a debole coesione e vento.

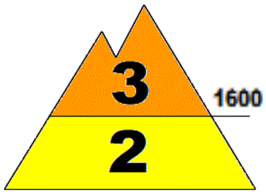

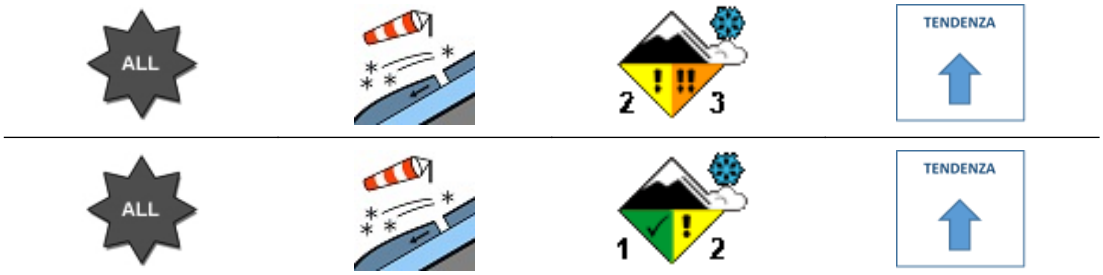

SITUAZIONE TIPO: neve a debole coesione e vento.

MANTO NEVOSO: La stabilità del manto nevoso è scarsa su alcuni punti (aree) per tutte le esposizioni al di sopra di 1600 mslm, possibili valanghe di dimensioni grandi.
La stabilità del manto nevoso è discreta su alcuni punti (aree) per tutte le esposizioni al di sotto di 1600 mslm, possibili valanghe di dimensioni medie.

AVVERTENZE

In considerazione delle avverse condizioni meteorologiche in atto, le attività al di fuori delle piste battute e segnalate sono sconsigliate.

SCALA EUROPEA DEL GRADO DI PERICOLO VALANGHE

LEGENDA PROBLEMA

Bollettino realizzato su scala sinottica-regionale (standard EAWS). La sua valutazione non può escludere in alcun modo la necessità di una seria e capace valutazione locale del pericolo (singolo pendio) che può essere anche sensibilmente diverso. Le previsioni meteorologiche sono relative all'orario UTC (per l'Italia +1 in inverno e +2 in estate).

MINISTERO DELLA DIFESA

meteomont
Servizio Nazionale di previsione neve e valanghe

EAWS EUROPEAN AVALANCHE WARNING SERVICES

CARABINIERI

GRAN SASSO EST - LAGA EST

PREVISIONE METEO

Quota		28/03/2026 h6:00	28/03/2026 h12:00	28/03/2026 h18:00
1000	Venti	08 Nodi da N-Est	07 Nodi da N-Est	05 Nodi da N-Est
	Temperature	-04 °C	-01 °C	-01 °C
	Temp.percepita	-9 °C	-5 °C	-4 °C
2000	Venti	21 Nodi da N-Est	15 Nodi da N-Est	12 Nodi da N-Est
	Temperature	-07 °C	-04 °C	-03 °C
	Temp.percepita	-17 °C	-11 °C	-9 °C
3000	Venti	19 Nodi da N-Est	13 Nodi da N-Est	18 Nodi da Nord
	Temperature	-09 °C	-06 °C	-07 °C
	Temp.percepita	-19 °C	-13 °C	-16 °C
Zero termico		0800-1000 m.	1200-1400 m.	1200-1400 m.
Fenomeno			—	—
Stato del cielo				

LEGENDA FENOMENI

— Assenza Fenomeni · Nebbia · Foschia · Pioggia debole · Pioggia moderata · Pioggia forte · Temporali

Nevicata debole · Nevicata moderata · Nevicata forte

STATO DEL CIELO

Sereno · Poco nuvoloso · Nuvoloso · Molto nuvoloso · Coperto

Parametri meteonivometrici registrati presso i campi di rilevamento il 27/03/2026.

Località	Comune	Quota (m.s.l.m.)	Altezza neve (cm)	Neve caduta nelle 24 ore (cm)	Temp. Min (°C)	Temp. Max (°C)	Condizioni del tempo
FAVACCHIOLE	Crognaleto (TE)	1016	16	16	-1	+5	Nevicata moderata
PRATO SELVA	Fano Adriano (TE)	1355	37	17	-3	+5	Nevicata moderata
PIANO SAN PIETRO	Isola del Gran Sasso d'Italia (TE)	950	20	20	N.P.	N.P.	Nevicata moderata
PRATI DI TIVO	Pietracamela (TE)	1380	55	37	-3	+7	Nevicata moderata
CEPPO	Rocca Santa Maria (TE)	1349	48	31	-3	+6	Nevicata moderata
SAN PAOLO	Acquasanta Terme (AP)	960	25	25	-2	+9	Nevicata moderata
COLLE SAN GIACOMO	Civitella del Tronto (TE)	1075	22	22	-1	+1	Nevicata debole continua

(*) Rilievi fuori campo

L'INFORMAZIONE E' PREVENZIONE - LEGGI L'ATTUALE GRADO DI PERICOLO VALANGHE!

IL CAPO DEL CENTRO NAZIONALE METEOMONT
(Ten. Col. RFI Emanuela Gini)
FIRMA AUTOGRAFA OMESSA AI SENSI
DELL'ART.3 DEL D.LGS N.39/1993