MINISTERO DELLA DIFESA

meteomont Servizio Nazionale di previsione neve e valanghe

EAWS EUROPEAN AVALANCHE WARNING SERVICES

CARABINIERI

AERONAUTICA MILITARE SERVIZIO METEOROLOGICO

# GRAN SASSO EST - LAGA EST

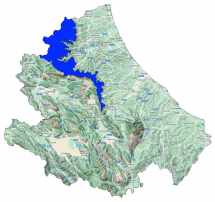

Bollettino Valanghe N. 376/2026 del 28/03/2026 ore 14.00

Validità 48 ore prossima emissione 29/03/2026

**A cura del Servizio METEOMONT dell'ARMA dei CARABINIERI**

**In collaborazione con Servizio Meteorologico dell'Aeronautica militare**

## SITUAZIONE alle 14:00 del 28/03/2026

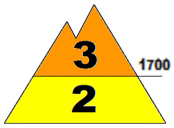


**SITUAZIONE TIPO: neve a debole coesione e vento.**

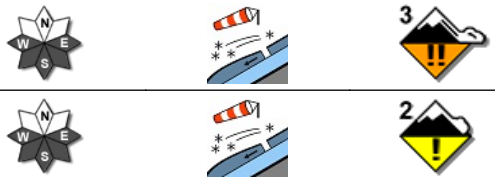


**SITUAZIONE TIPO: neve a debole coesione e vento.**

| Quota neve (mslm) | Nord | Sud |
|---|---|---|
| | 700 | 700 |

| Altezza Neve (cm) | Neve al suolo | Neve Fresca | Quota (mslm) |
|---|---|---|---|
| | 070 | 022 | 1380 |
| | 070 | 030 | 1349 |

**VALANGHE OSSERVATE: -.**

## PREVISIONI 29/03/2026

# GRADO DI PERICOLO: MARCATO 3

## SITUAZIONE TIPO: neve a debole coesione e vento.

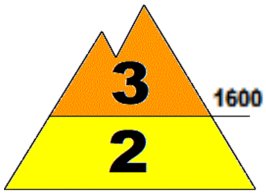


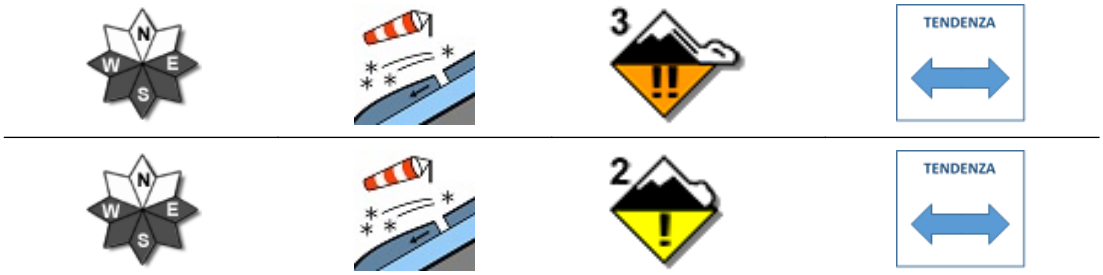


## SITUAZIONE TIPO: neve a debole coesione e vento.

**MANTO NEVOSO: La stabilità del manto nevoso è scarsa su alcuni punti (aree) per versanti da est a ovest al di sopra di 1600 mslm, possibili valanghe di dimensioni grandi.**
**La stabilità del manto nevoso è discreta su alcuni punti (aree) per versanti da est a ovest al di sotto di 1600 mslm, possibili valanghe di dimensioni medie.**

## AVVERTENZE

A seguito dell'attività eolica registrata sono da evitare le zone di accumulo, conche, canaloni, cambi di pendenza e pendii sotto vento in genere.

## SCALA EUROPEA DEL GRADO DI PERICOLO VALANGHE

## LEGENDA PROBLEMA

**Bollettino realizzato su scala sinottica-regionale (standard EAWS). La sua valutazione non può escludere in alcun modo la necessità di una seria e capace valutazione locale del pericolo (singolo pendio) che può essere anche sensibilmente diverso. Le previsioni meteorologiche sono relative all'orario UTC (per l'Italia +1 in inverno e +2 in estate).**

MINISTERO DELLA DIFESA

meteomont
Servizio Nazionale di previsione neve e valanghe

EAWS EUROPEAN AVALANCHE WARNING SERVICES

CARABINIERI

# GRAN SASSO EST - LAGA EST

## PREVISIONE METEO

| Quota | | 29/03/2026 h6:00 | 29/03/2026 h12:00 | 29/03/2026 h18:00 |
|---|---|---|---|---|
| 1000 | Venti | 03 Nodi da N-Est | 04 Nodi da N-Est | 03 Nodi da N-Est |
| | Temperature | -01 °C | +00 °C | +00 °C |
| | Temp.percepita | -3 °C | -3 °C | -2 °C |
| 2000 | Venti | 09 Nodi da Est | 08 Nodi da Est | 07 Nodi da Est |
| | Temperature | -04 °C | -04 °C | -03 °C |
| | Temp.percepita | -10 °C | -9 °C | -8 °C |
| 3000 | Venti | 05 Nodi da N-Est | 02 Nodi da S-Est | 01 Nodi da Est |
| | Temperature | -07 °C | -07 °C | -07 °C |
| | Temp.percepita | -11 °C | -7 °C | -7 °C |
| Zero termico | | 1200-1400 m. | 1300-1500 m. | 1400-1600 m. |
| Fenomeno | | — | | — |
| Stato del cielo | | | | |

## LEGENDA FENOMENI

Assenza Fenomeni · Nebbia · Foschia · Pioggia debole · Pioggia moderata · Pioggia forte · Temporali · Nevicata debole · Nevicata moderata · Nevicata forte

## STATO DEL CIELO

Sereno · Poco nuvoloso · Nuvoloso · Molto nuvoloso · Coperto

## Parametri meteonivometrici registrati presso i campi di rilevamento il 28/03/2026.

| Località | Comune | Quota (m.s.l.m.) | Altezza neve (cm) | Neve caduta nelle 24 ore (cm) | Temp. Min (°C) | Temp. Max (°C) | Condizioni del tempo |
|---|---|---|---|---|---|---|---|
| FAVACCHIOLE | Crognaleto (TE) | 1016 | 18 | 7 | -1 | 0 | Assenza di precipitazioni |
| PIANO SAN PIETRO | Isola del Gran Sasso d'Italia (TE) | 950 | 29 | 10 | N.P. | N.P. | Assenza di precipitazioni |
| PRATI DI TIVO | Pietracamela (TE) | 1380 | 70 | 22 | -3 | -1 | Assenza di precipitazioni |
| CEPPO | Rocca Santa Maria (TE) | 1349 | 70 | 30 | -2 | +5 | Assenza di precipitazioni |
| SAN PAOLO | Acquasanta Terme (AP) | 960 | 41 | 29 | -2 | +6 | Assenza di precipitazioni |
| COLLE SAN GIACOMO | Civitella del Tronto (TE) | 1075 | 38 | 16 | -1 | +4 | Assenza di precipitazioni |

**(*) Rilievi fuori campo**

**L'INFORMAZIONE E' PREVENZIONE - LEGGI L'ATTUALE GRADO DI PERICOLO VALANGHE!**

**IL CAPO DEL CENTRO NAZIONALE METEOMONT**
**(Ten. Col. RFI Emanuela Gini)**
**FIRMA AUTOGRAFA OMESSA AI SENSI**
**DELL'ART.3 DEL D.LGS N.39/1993**

**Bollettino realizzato su scala sinottica-regionale (standard EAWS). La sua valutazione non può escludere in alcun modo la necessità di una seria e capace valutazione locale del pericolo (singolo pendio) che può essere anche sensibilmente diverso. Le previsioni meteorologiche sono relative all'orario UTC (per l'Italia +1 in inverno e +2 in estate).**