MINISTERO DELLA DIFESA

meteomont
Servizio Nazionale di previsione neve e valanghe

EAWS EUROPEAN AVALANCHE WARNING SERVICES

CARABINIERI

AERONAUTICA MILITARE SERVIZIO METEOROLOGICO

## MONTI SIMBRUINI E META

Bollettino Valanghe N. 321/2026 del 27/03/2026 ore 14.00
Validità 48 ore prossima emissione 28/03/2026

**A cura del Servizio METEOMONT dell'ARMA dei CARABINIERI**
**In collaborazione con Servizio Meteorologico dell'Aeronautica militare**

## SITUAZIONE alle 14:00 del 27/03/2026

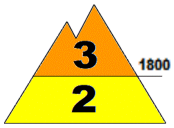


**SITUAZIONE TIPO: neve a debole coesione e vento.**

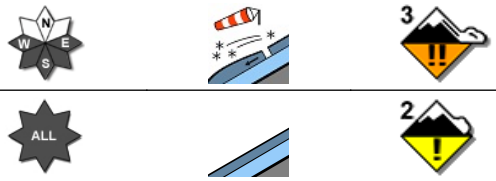


**SITUAZIONE TIPO: nessuna situazione tipo evidente.**

| Quota neve (mslm) | Nord | Sud |
|---|---|---|
| | 1300 - 1500 | 1500 - 1600 |

| Altezza Neve (cm) | Neve al suolo | Neve Fresca | Quota (mslm) |
|---|---|---|---|
| | 098 | 014 | 1790 |
| | 015 | 009 | 1550 |

**VALANGHE OSSERVATE: Nessuna valanga.**

## PREVISIONI 28/03/2026

# GRADO DI PERICOLO: MARCATO 3

## SITUAZIONE TIPO: neve a debole coesione e vento.

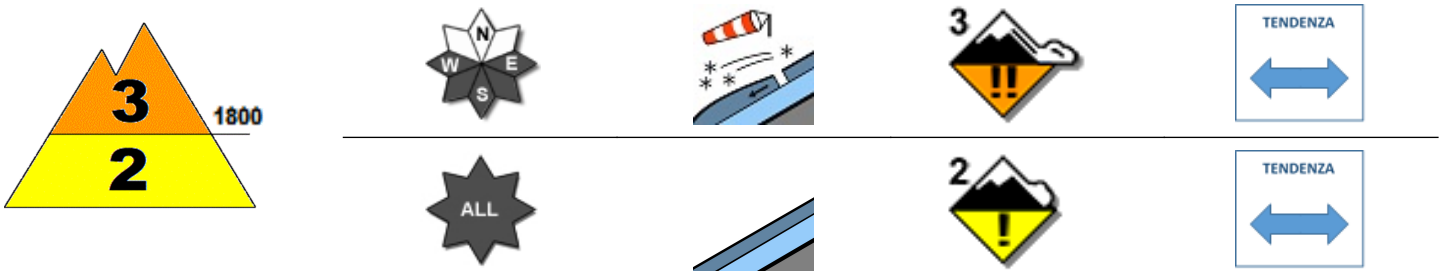


## SITUAZIONE TIPO: nessuna situazione tipo evidente.

**MANTO NEVOSO: La stabilità del manto nevoso è scarsa su alcuni punti (aree) per versanti da est a ovest al di sopra di 1800 mslm, possibili valanghe di dimensioni grandi.**
**La stabilità del manto nevoso è discreta su alcuni punti (aree) per tutte le esposizioni al di sotto di 1800 mslm, possibili valanghe di dimensioni medie.**

## AVVERTENZE

In considerazione dei recenti apporti di neve fresca, è richiesta un'ottima valutazione locale della stabilità ed individuazione dell'itinerario.

## SCALA EUROPEA DEL GRADO DI PERICOLO VALANGHE

## LEGENDA PROBLEMA

**Bollettino realizzato su scala sinottica-regionale (standard EAWS). La sua valutazione non può escludere in alcun modo la necessità di una seria e capace valutazione locale del pericolo (singolo pendio) che può essere anche sensibilmente diverso. Le previsioni meteorologiche sono relative all'orario UTC (per l'Italia +1 in inverno e +2 in estate).**

# MONTI SIMBRUINI E META

## PREVISIONE METEO

| Quota | | 28/03/2026 h6:00 | 28/03/2026 h12:00 | 28/03/2026 h18:00 |
|---|---|---|---|---|
| 1000 | Venti | 05 Nodi da N-Est | 03 Nodi da N-Est | 04 Nodi da N-Est |
| | Temperature | -02 °C | +03 °C | +01 °C |
| | Temp.percepita | -5 °C | 2 °C | -1 °C |
| 2000 | Venti | 20 Nodi da N-Est | 08 Nodi da N-Est | 13 Nodi da N-Est |
| | Temperature | -04 °C | -03 °C | -01 °C |
| | Temp.percepita | -12 °C | -8 °C | -7 °C |
| 3000 | Venti | 19 Nodi da N-Est | 10 Nodi da Nord | 13 Nodi da Nord |
| | Temperature | -07 °C | -05 °C | -03 °C |
| | Temp.percepita | -16 °C | -11 °C | -10 °C |
| Zero termico | | 1000-1200 m. | 1500-1700 m. | 1300-1500 m. |
| Fenomeno | | — | — | — |
| Stato del cielo | | | | |

## LEGENDA FENOMENI

— Assenza Fenomeni · Nebbia · Foschia · Pioggia debole · Pioggia moderata · Pioggia forte · Temporali

Nevicata debole · Nevicata moderata · Nevicata forte

## STATO DEL CIELO

Sereno · Poco nuvoloso · Nuvoloso · Molto nuvoloso · Coperto

## Parametri meteonivometrici registrati presso i campi di rilevamento il 27/03/2026.

| Località | Comune | Quota (m.s.l.m.) | Altezza neve (cm) | Neve caduta nelle 24 ore (cm) | Temp. Min (°C) | Temp. Max (°C) | Condizioni del tempo |
|---|---|---|---|---|---|---|---|
| PRATI DI MEZZO | Picinisco (FR) | 1430 | 13 | 13 | -5 | 0 | Assenza di precipitazioni |
| CAMPO DELL'OSSO | Subiaco (RM) | 1550 | 10 | 9 | -4 | -2 | Assenza di precipitazioni |
| C.STAFFI | Filettino (FR) | 1780 | 81 | 5 | -7 | -1 | Nebbia con cielo visibile |
| CAMPO CATINO | Guarcino (FR) | 1790 | 98 | 14 | -7 | -1 | Assenza di precipitazioni |

**(*) Rilievi fuori campo**

**L'INFORMAZIONE E' PREVENZIONE - LEGGI L'ATTUALE GRADO DI PERICOLO VALANGHE!**

**IL CAPO DEL CENTRO NAZIONALE METEOMONT**
**(Ten. Col. RFI Emanuela Gini)**
**FIRMA AUTOGRAFA OMESSA AI SENSI**
**DELL'ART.3 DEL D.LGS N.39/1993**

**Bollettino realizzato su scala sinottica-regionale (standard EAWS). La sua valutazione non può escludere in alcun modo la necessità di una seria e capace valutazione locale del pericolo (singolo pendio) che può essere anche sensibilmente diverso. Le previsioni meteorologiche sono relative all'orario UTC (per l'Italia +1 in inverno e +2 in estate).**