Bulletin d'estimation du risque d'avalanche
(valable en dehors des pistes balisées et ouvertes)

MASSIF : Aravis

Rédigé le samedi 28 mars 2026 à 16h

Estimation des risques pour le : DIMANCHE 29 MARS

2

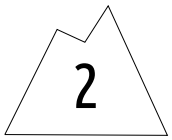

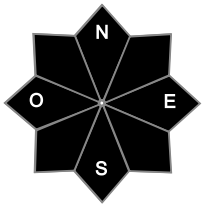

Indice de risque limité.

Départs spontanés : peu probables, quelques accumulations par le vent de N, pouvant céder

Déclenchements provoqués : plaques à vent nouvelles dans la neige récente

Indices de risque : 5 très fort - 4 fort - 3 marqué - 2 limité - 1 faible -- En noir : les pentes les plus dangereuses

Stabilité du manteau neigeux

Situation avalancheuse typique : neige ventée

Déclenchements provoqués :
Plaques à vent nouvelles dans la neige récente : 10 cm de fraîche sur 20/30 cm récents tombés en milieu de semaine, en cours de tassement. Plaques friables pour la plupart, éventuellement dures près des crêtes. Formation sous l'effet du vent de N/NE la nuit de samedi à dimanche, voire dimanche en journée. Plaques plutôt rares de l'Étale au Charvin, un peu plus nombreuses dans les secteurs des Combes, Pointe Percée, Areu, davantage impactés par la Bise. Pas très larges ni épaisses (cassure 30/40 cm) mais localement réactives. Taille 1 à 2 (petite à moyenne).
Observables : accumulations, fissures devant les skis, changement de qualité de neige sur une courte distance.

Départs spontanés :
Quelques accumulations de neige récente peuvent céder dans des pentes très raides, surtout près des crêtes ou sur des hauts de couloirs chargés par le vent de N/NE. Départs ponctuels ou en plaques peu larges. Taille 1, éventuellement 2.

Qualité de la neige

Enneigement :
Bon pour une fin mars. On peut chausser skis ou raquettes dès 1200 m environ. Attention, absence de sous-couches sous 1500/1600 m en versants S.

Qualité de la neige ce dimanche :
10 cm de neige fraîche en surface, irrégulièrement soufflée. Sous-couche hétérogène : froide meuble sur 15/25 cm en versants N abrités des vents, compacte dans les autres orientations, dure ou glacée près des crêtes.
Nombreuses corniches et accumulations.

Aperçu météo pour le dimanche 29 mars

	nuit	matin	après-midi	soir

Très chargé le matin, petites éclaircies l'après-midi. Froid, -6 puis -3 DG à 2000 m.

Pluie-Neige	600 m			
Iso 0 °C	1 000 m	1 300 m	1 500 m	1 200 m
Vent 2000 m	50 km/h	30 km/h	20 km/h	20 km/h
Vent 2500 m	60 km/h	50 km/h	30 km/h	30 km/h

Épaisseur de neige hors-piste

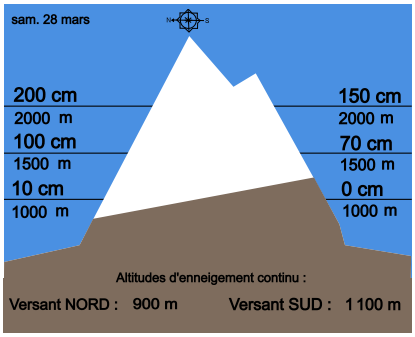

Précipitations à 1800 m

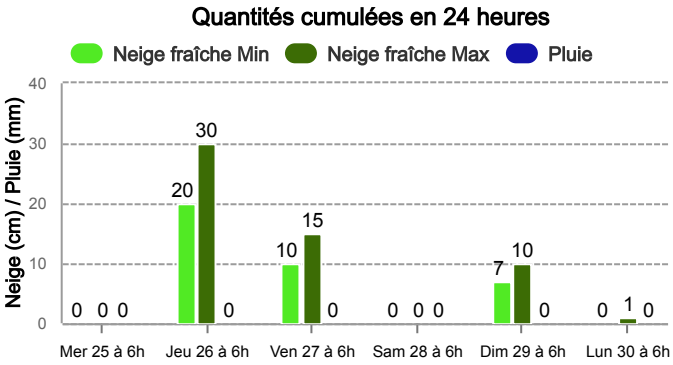

Tendance du lundi 30 mars

2

Indice de risque limité

Danger stationnaire le matin, puis en légère hausse l'après-midi avec de petites chutes de neige et vent d'W 40 km/h.

Pour consulter la vigilance en cours, veuillez vous rendre sur le site https://vigilance.meteofrance.fr/fr

Météo-France - 73 avenue de Paris, 94165 Saint-Mandé cedex - Contact : contact@meteo.fr

Rédigé par Météo-France avec la contribution des observateurs du réseau nivo-météorologiques. Partenariat : ANMSM (Maires de Stations de Montagne), DSF (Domaines Skiables de France), ADSP (Directeurs de Pistes et de la Sécurité des Stations de Sports d'Hiver) et autres acteurs de la montagne.

Bulletin neige & avalanches par téléphone au
0 892 68 10 20 Service 0,35 € / min + prix appel

RÉPUBLIQUE FRANÇAISE
Liberté Égalité Fraternité

METEO FRANCE
À VOS CÔTÉS, DANS UN CLIMAT QUI CHANGE

Bulletin d'estimation du risque d'avalanche

(valable en dehors des pistes balisées et ouvertes)

MASSIF : Aravis

Rédigé le samedi 28 mars 2026 à 16h

Conditions nivo-météo des 7 derniers jours

	dim. 22/03				lun. 23/03				mar. 24/03				mer. 25/03				jeu. 26/03				ven. 27/03				sam. 28/03			
	03h	09h	15h	21h	03h	09h	15h	21h	03h	09h	15h	21h	03h	09h	15h	21h	03h	09h	15h	21h	03h	09h	15h	21h	03h	09h	15h	21h
Météo																												
Vent (km/h)	30	35	40	15	20	30	25	20	10	15	10	10	40	60	70	60	60	60	60	60	60	80	40	30	40	40	30	50
à 2500m																												
Vent (km/h)	20	25	25	5	15	25	20	15	5	5	5	5	30	40	60	45	45	40	50	50	45	60	30	20	30	30	20	40
à 2000m																												

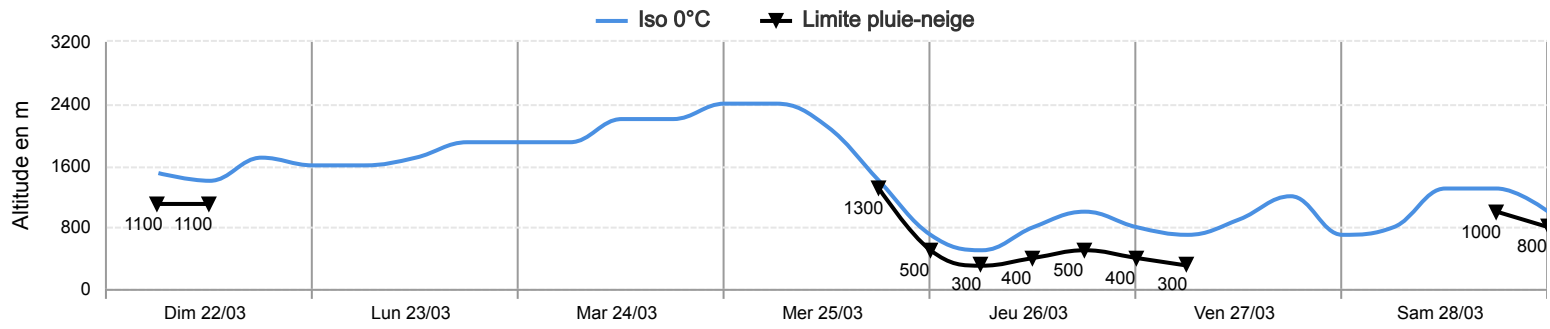

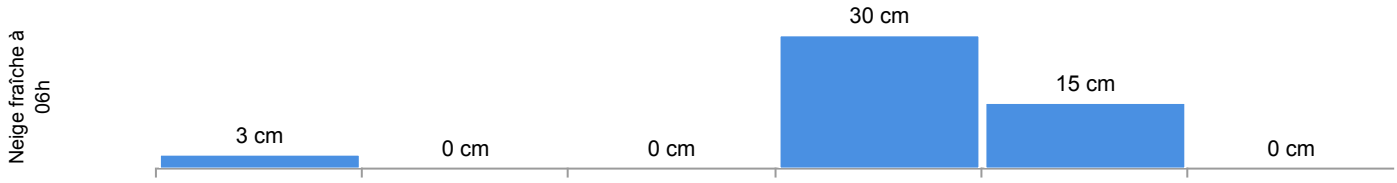

Risque d'avalanche	dim. 22/03	lun. 23/03	mar. 24/03	mer. 25/03	jeu. 26/03	ven. 27/03	sam. 28/03
	2	2	2	3	3	3	2

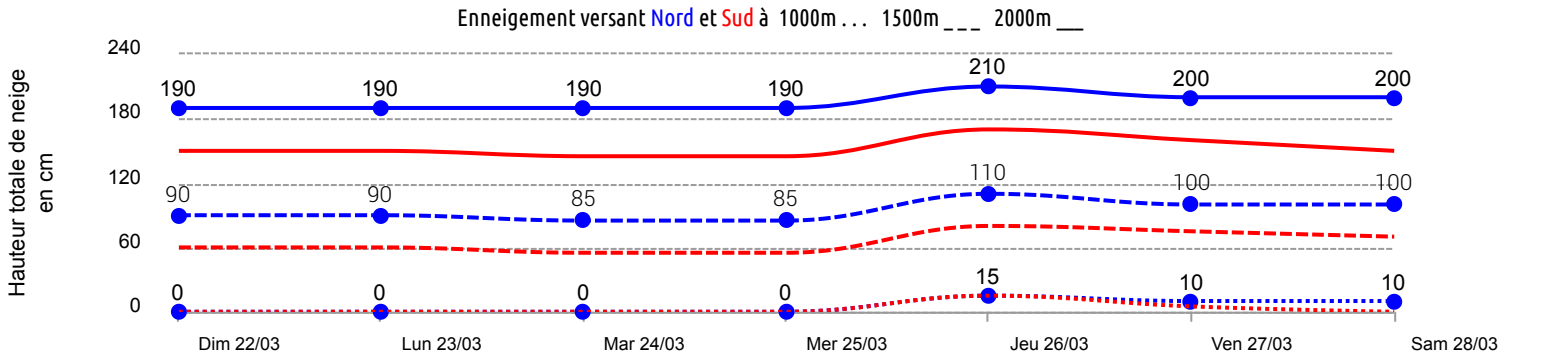

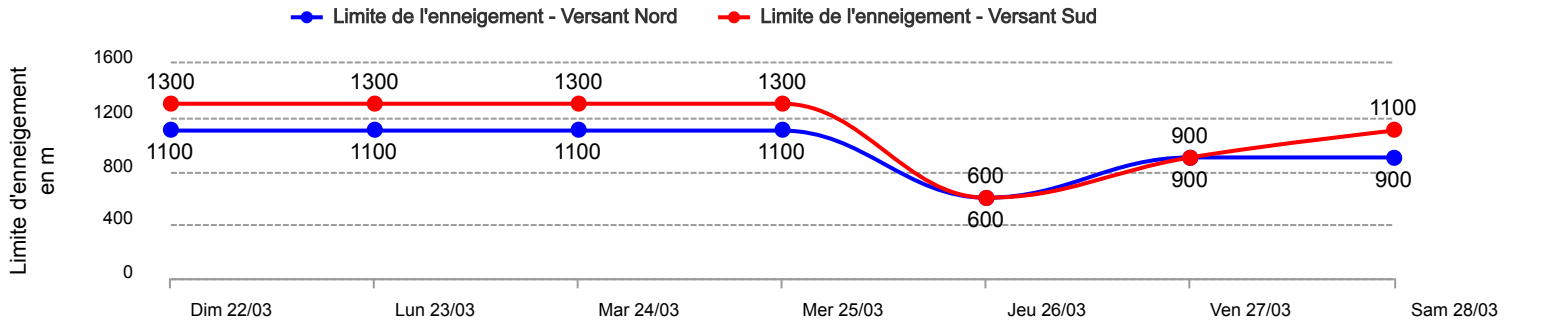

Pour consulter la vigilance en cours, veuillez vous rendre sur le site https://vigilance.meteofrance.fr/fr

Météo-France - 73 avenue de Paris, 94165 Saint-Mandé cedex - Contact : contact@meteo.fr

Bulletin neige & avalanches par téléphone au

0 892 68 10 20 Service 0,35 € / min + prix appel

Rédigé par Météo-France avec la contribution des observateurs du réseau nivo-météorologiques. Partenariat : ANMSM (Maires de Stations de Montagne), DSF (Domaines Skiables de France), ADSP (Directeurs de Pistes et de la Sécurité des Stations de Sports d'Hiver) et autres acteurs de la montagne.