Bulletin d'estimation du risque d'avalanche
(valable en dehors des pistes balisées et ouvertes)

MASSIF : Beaufortain

Rédigé le samedi 28 mars 2026 à 16h

Estimation des risques pour le : DIMANCHE 29 MARS

UN PEU DE NEIGE FRAÎCHE SUR UN MANTEAU GLOBALEMENT STABILISÉ. MÉTÉO HIVERNALE.

2

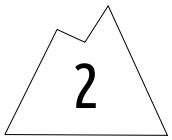

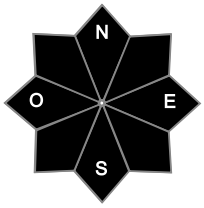

zones d'accumulation

Indices de risque : 5 très fort - 4 fort - 3 marqué - 2 limité - 1 faible -- En noir : les pentes les plus dangereuses

Indice de risque limité.

Départs spontanés : peu probables.

Déclenchements provoqués : quelques plaques en neige ventée, tous versants.

Stabilité du manteau neigeux

Situation avalancheuse typique : neige ventée

Déclenchements provoqués : **quelques plaques** en neige ventée, en **tous versants**. D'une part, la petite chute de neige cette nuit, faiblement ventée, crée de nouvelles petites instabilités, notamment près des crêtes. D'autre part, il subsiste d'anciennes plaques datant du coup de vent mercredi-jeudi, plutôt dures et désormais peu réactives au passage d'un skieur. La neige fraîche tombée dans la nuit aura pour effet de masquer la plupart des indices visuels, compliquant l'identification de ces plaques. Les **cassures sont limitées, généralement 20-30 cm**, jusqu'à 50 cm si une plaque dure un peu plus ancienne est déclenchée, donnant alors une avalanche de taille moyenne.
Observables : fissures sous les skis, accumulation de neige un peu plus dense notamment près des crêtes.

Départs spontanés : peu probables. A la marge, une rare petite plaque peut se décrocher spontanément dans un endroit très défavorable : au pied d'une barre rocheuse sous le petit vent de nord par exemple.

Qualité de la neige

Enneigement : encore un peu au dessus de la moyenne, sauf aux plus basses altitudes où les hauteurs de neige sont tout juste correctes pour la saison.

Limite skiable : avec la petite chute de la nuit, il sera possible de skier dès 800/1000 m dans les prairies. Sous-couche vers 1100 m en Nord, 1500 m en Sud.

Qualité de la neige : 5-10 cm de neige fraîche ce dimanche matin, voire localement un peu plus dans les zones d'accumulation en altitude. Neige poudreuse, légère, sur un fond généralement plus ferme : ski très agréable.
Grâce aux nuages et à la masse d'air froide, la neige reste légère en tous versants et quasiment à toutes les altitudes.

Aperçu météo pour le dimanche 29 mars

nuit	matin	après-midi	soir

Faibles averses de neige possibles jusqu'en début de matinée. Ensuite, ciel restant nuageux avec quelques timides éclaircies. Températures hivernales.

Pluie-Neige	700 m	500 m		
Iso 0 °C	1 000 m	800 m	1 400 m	1 400 m
Vent 2000 m	↙ 20 km/h	↙ 15 km/h	↘ 15 km/h	↘ 15 km/h
Vent 3000 m	↙ 30 km/h	← 20 km/h	↙ 20 km/h	↓ 20 km/h

Épaisseur de neige hors-piste

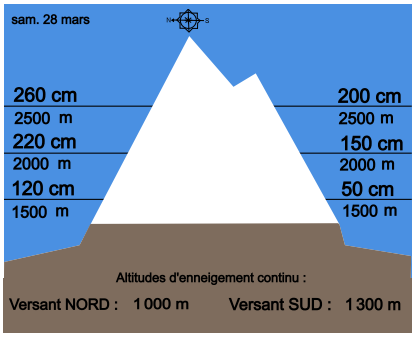

Précipitations à 1800 m

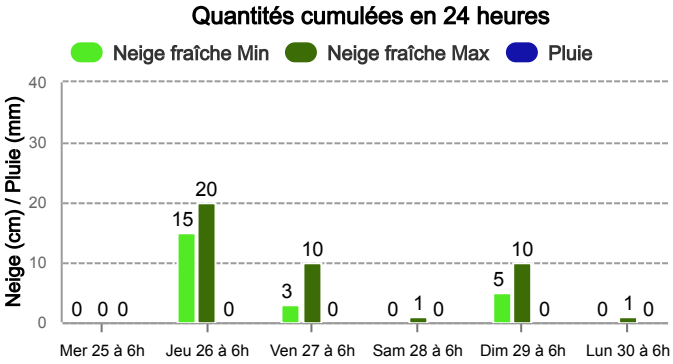

Tendance du lundi 30 mars

3

Indice de risque marqué

Le vent de nord-ouest se lève franchement lundi matin et transporte la neige légère en surface. Par ailleurs, il neige faiblement à partir de la mi-journée. De nouvelles instabilités temporaires vont se former ==> risque en hausse.

Pour consulter la vigilance en cours, veuillez vous rendre sur le site https://vigilance.meteofrance.fr/fr

Météo-France - 73 avenue de Paris, 94165 Saint-Mandé cedex - Contact : contact@meteo.fr

Rédigé par Météo-France avec la contribution des observateurs du réseau nivo-météorologiques. Partenariat : ANMSM (Maires de Stations de Montagne), DSF (Domaines Skiables de France), ADSP (Directeurs de Pistes et de la Sécurité des Stations de Sports d'Hiver) et autres acteurs de la montagne.

Bulletin neige & avalanches par téléphone au 0 892 68 10 20 Service 0,35 € / min + prix appel

Bulletin d'estimation du risque d'avalanche

(valable en dehors des pistes balisées et ouvertes)

MASSIF : Beaufortain

Rédigé le samedi 28 mars 2026 à 16h

Conditions nivo-météo des 7 derniers jours

	dim. 22/03				lun. 23/03				mar. 24/03				mer. 25/03				jeu. 26/03				ven. 27/03				sam. 28/03			
	03h	09h	15h	21h	03h	09h	15h	21h	03h	09h	15h	21h	03h	09h	15h	21h	03h	09h	15h	21h	03h	09h	15h	21h	03h	09h	15h	21h
Météo																												
Vent (km/h)	15	25	20	10	20	25	20	20	20	25	35	40	50	60	80	80	75	65	70	60	50	50	30	30	30	30	30	30
à 3000m																												
Vent (km/h)	10	30	25	15	10	10	20	10	5	5	15	25	30	40	65	65	60	50	55	50	45	30	20	20	20	20	20	20
à 2000m																												

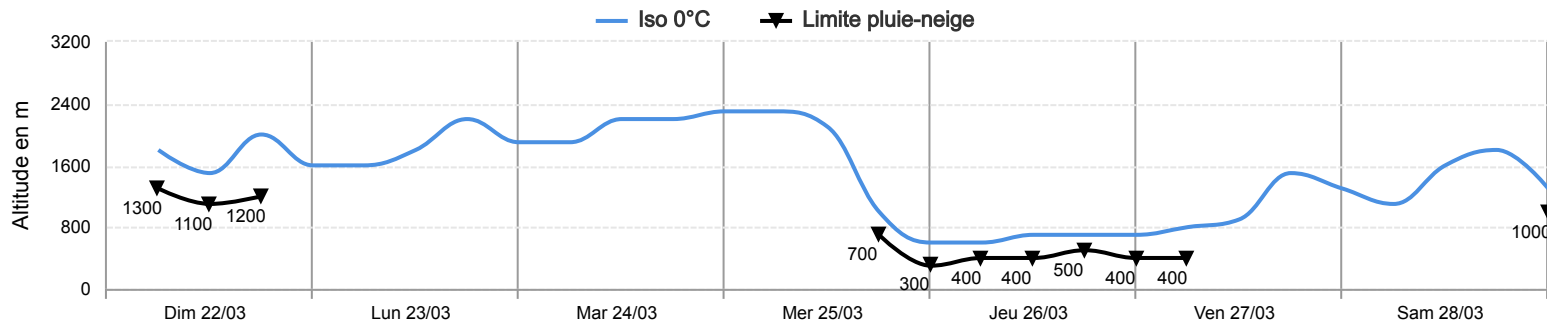

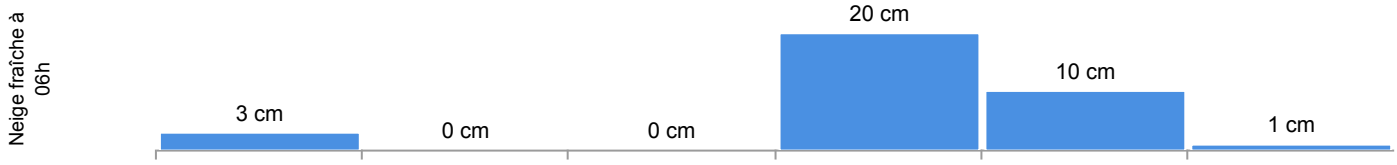

Risque d'avalanche	dim. 22/03	lun. 23/03	mar. 24/03	mer. 25/03	jeu. 26/03	ven. 27/03	sam. 28/03
	2	2	2	3	3	3	2

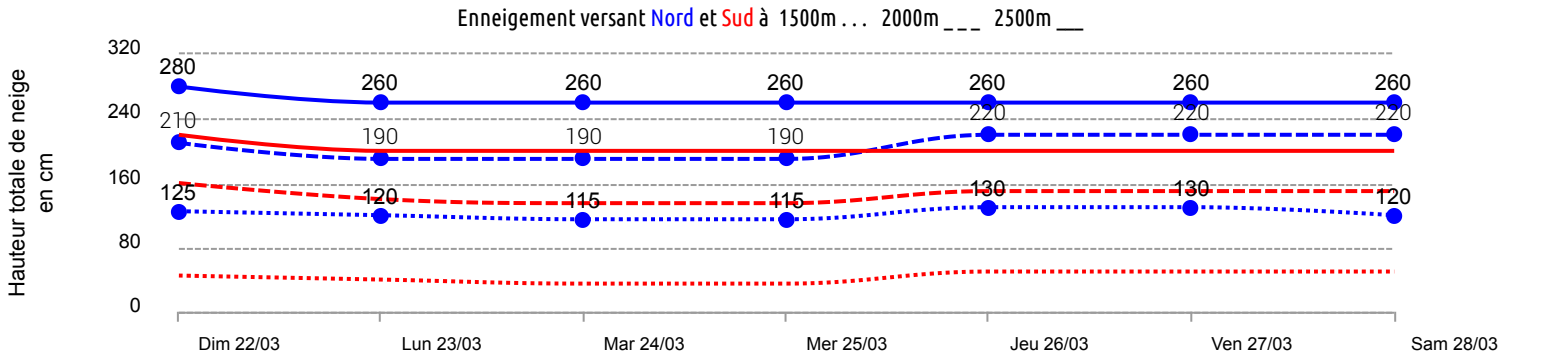

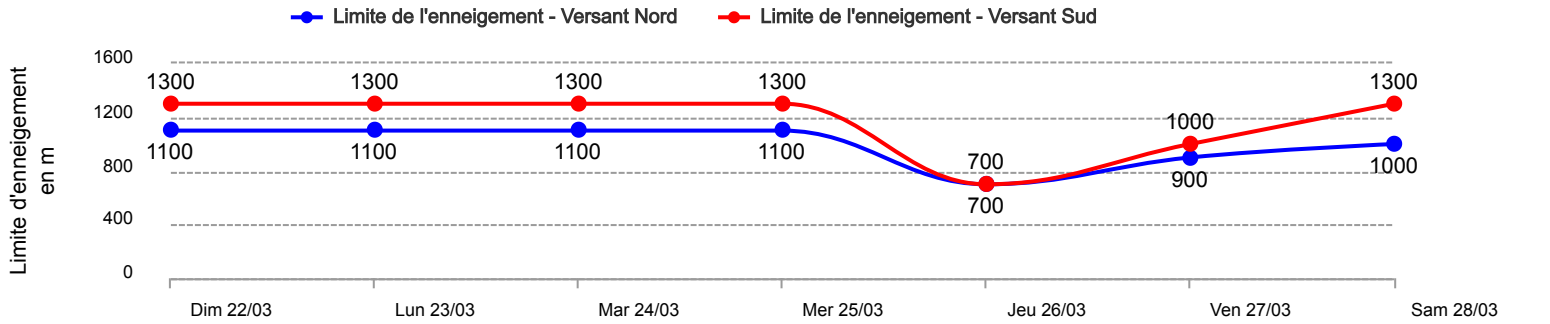

Pour consulter la vigilance en cours, veuillez vous rendre sur le site https://vigilance.meteofrance.fr/fr

Météo-France - 73 avenue de Paris, 94165 Saint-Mandé cedex - Contact : contact@meteo.fr

Bulletin neige & avalanches par téléphone au

0 892 68 10 20 Service 0,35 € / min + prix appel

Rédigé par Météo-France avec la contribution des observateurs du réseau nivo-météorologiques. Partenariat : ANMSM (Maires de Stations de Montagne), DSF (Domaines Skiables de France), ADSP (Directeurs de Pistes et de la Sécurité des Stations de Sports d'Hiver) et autres acteurs de la montagne.