Bulletin d'estimation du risque d'avalanche

(valable en dehors des pistes balisées et ouvertes)

MASSIF : Belledonne

Rédigé le samedi 28 mars 2026 à 16h

Estimation des risques pour le : DIMANCHE 29 MARS

QUELQUES PLAQUES DANS LA NEIGE FRAICHE/RÉCENTE VENTÉE.

2

2

N O E S

zones d'accumulation

Indice de risque limité.

Départs spontanés : Peu probables, ou rares coulées humides au soleil en cas d'éclaircies (incertain).

Déclenchements provoqués : Quelques plaques dans la neige fraîche/récente ventée, parfois loin des crêtes.

Indices de risque : 5 très fort - 4 fort - 3 marqué - 2 limité - 1 faible -- En noir : les pentes les plus dangereuses

Stabilité du manteau neigeux

Situation avalancheuse typique : neige ventée

Déclenchements provoqués : Quelques plaques à vent subsistent ce dimanche, dans les zones d'accumulations formées par le vent de Nord-Nord-Est qui faiblit un peu pour la journée. Elles peuvent être situées loin des crêtes, parfois même en bas de pente. Elles se retrouvent en tout versant, bien que plus fréquemment dans les versants à composante Sud à Est, qui ont été généralement plus chargés. Souvent difficiles à déclencher et d'aspect dur, mais localement il n'est pas exclu qu'elles présentent un aspect un peu plus friable voire poudreux, tout en étant plus réactives au passage d'un pratiquant. La petite couche de neige fraîche attendue jusqu'en journée de dimanche (5-10 cm) est également un peu ventée au début et ne vient pas fondamentalement changer la donne, quelques nouvelles plaques peu épaisses mais localement réactives venant se former préférentiellement dans ces mêmes zones d'accumulations.

Déclenchements spontanés : Peu probables, ou rares coulées humides de taille 1 dans les pentes ensoleillées (en cas d'éclaircies en journée, ce qui est très incertain) dans la neige fraîche/récente qui peut s'humidifier au soleil et près des rochers.

Qualité de la neige

Qualification de l'enneigement : L'enneigement est bon à basse altitude, et même excellent dés 1800 / 2000m. Peu de sous couche sous 1700m en plein Sud.
Limites skiables : Vers 1000 / 1200m selon le versant, avec prudence en Sud / sous les sapins

Qualité de la neige dimanche : Petite couche de neige fraîche tombant en nuit de samedi à dimanche (jusqu'en journée de dimanche dans certains secteurs de l'ouest du massif), ou à défaut neige récente tombée quelques jours plus tôt et souvent travaillée ou soufflée par le vent dans de nombreux endroits. Le manteau neigeux est parfois très irrégulier. Certaines crêtes et pentes les plus ventées, où la neige a été arrachée, peuvent être dégarnies et le ski se fait parfois sur la vieille croûte de regel. Toutefois, on retrouve des secteurs en neige poudreuse plus agréable, notamment en bas de pentes / dans les arbres. A noter que dans certaines pentes ayant été exposées au soleil, la neige récente s'est parfois humidifiée, on peut alors y retrouver des surfaces croûtées glissantes pouvant être à peine masquées par la petite couche de fraîche.

Aperçu météo pour le dimanche 29 mars

	nuit	matin	après-midi	soir
Pluie-Neige	400 m			
Iso 0 °C	800 m	900 m	1 400 m	1 300 m
Vent 2000 m	↓ 40 km/h	↓ 25 km/h	↓ 15 km/h	↓ 20 km/h
Vent 3000 m	↓ 45 km/h	↙ 35 km/h	↙ 20 km/h	↓ 25 km/h

Passage faiblement perturbé, un peu plus actif sur l'ouest du massif (5-10 cm possibles). Vent de NNE temporairement en perte de vitesse.

Épaisseur de neige hors-piste

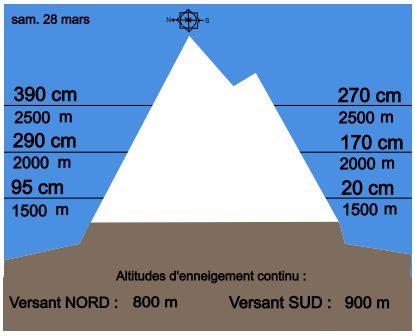

Précipitations à 1800 m

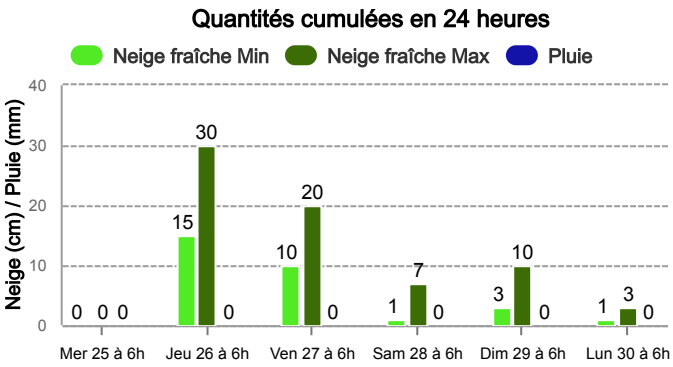

Tendance du lundi 30 mars

3

Indice de risque marqué

Lundi, risque à nouveau en hausse. Le vent de Nord se renforce, créant de nouvelles instabilités dans la neige fraîche/récente. En parallèle, une nouvelle perturbation gagne le massif, donnant un peu de neige surtout à partir de l'après-midi. A confirmer, il reste des incertitudes...

Pour consulter la vigilance en cours, veuillez vous rendre sur le site https://vigilance.meteofrance.fr/fr

Météo-France - 73 avenue de Paris, 94165 Saint-Mandé cedex - Contact : contact@meteo.fr

Rédigé par Météo-France avec la contribution des observateurs du réseau nivo-météorologiques. Partenariat : ANMSM (Maires de Stations de Montagne), DSF (Domaines Skiables de France), ADSP (Directeurs de Pistes et de la Sécurité des Stations de Sports d'Hiver) et autres acteurs de la montagne.

Bulletin neige & avalanches par téléphone au 0 892 68 10 20 Service 0,35 € / min + prix appel

RÉPUBLIQUE FRANÇAISE
Liberté Égalité Fraternité

METEO FRANCE
À VOS CÔTÉS, DANS UN CLIMAT QUI CHANGE

Bulletin d'estimation du risque d'avalanche

(valable en dehors des pistes balisées et ouvertes)

MASSIF : Belledonne

Rédigé le samedi 28 mars 2026 à 16h

Conditions nivo-météo des 7 derniers jours

	dim. 22/03				lun. 23/03				mar. 24/03				mer. 25/03				jeu. 26/03				ven. 27/03				sam. 28/03			
	03h	09h	15h	21h	03h	09h	15h	21h	03h	09h	15h	21h	03h	09h	15h	21h	03h	09h	15h	21h	03h	09h	15h	21h	03h	09h	15h	21h
Météo																												
Vent (km/h)	15	15	15	15	20	30	25	25	20	25	15	15	25	55	80	100	95	90	80	80	90	70	40	35	40	50	50	35
à 3000m																												
Vent (km/h)	15	10	20	15	15	20	15	15	15	10	10	10	10	30	55	70	65	60	65	60	55	50	35	25	30	40	40	25
à 2000m																												

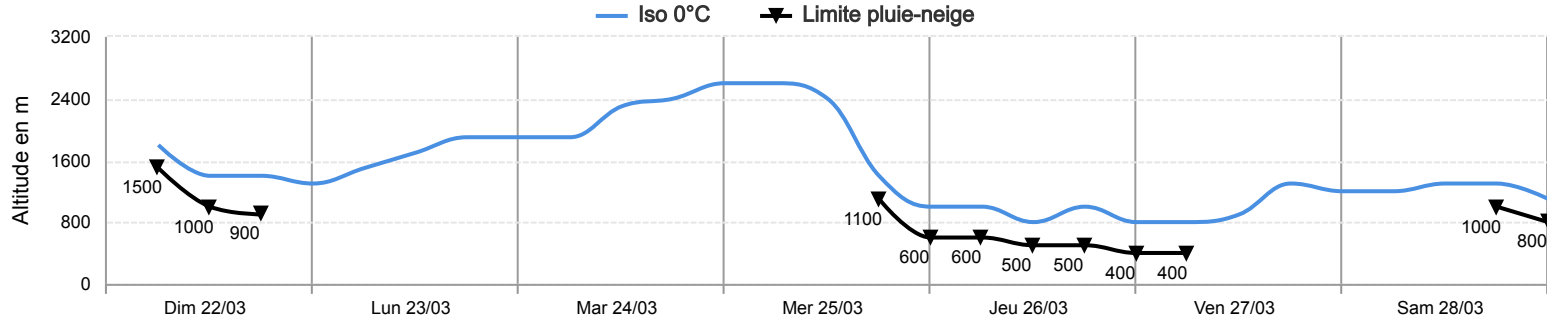

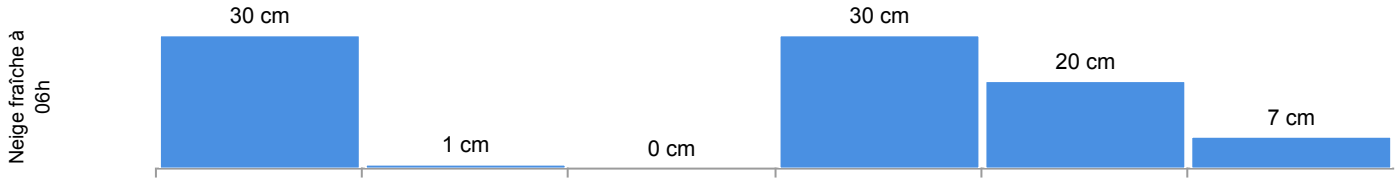

Risque d'avalanche	dim. 22/03	lun. 23/03	mar. 24/03	mer. 25/03	jeu. 26/03	ven. 27/03	sam. 28/03
	2	2	2	3	4	3	3

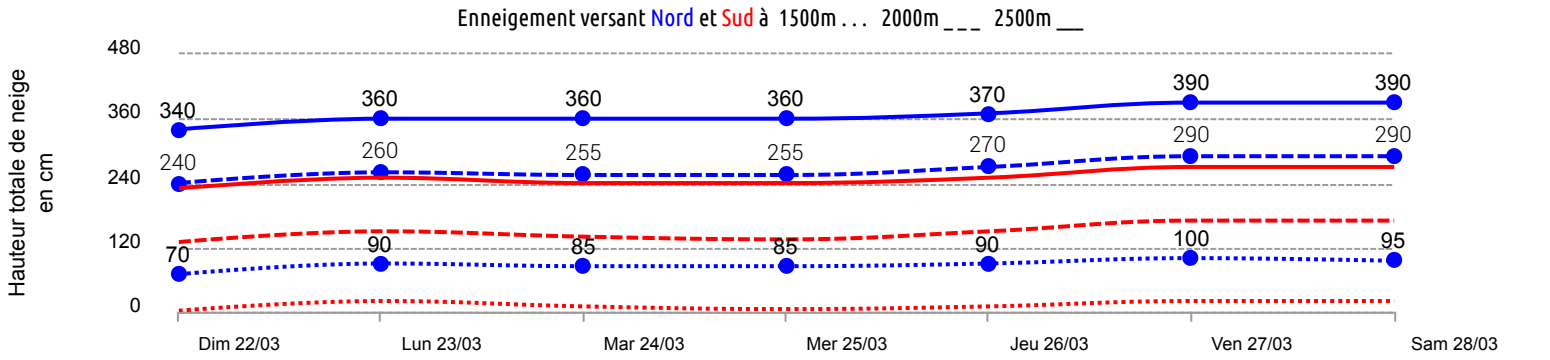

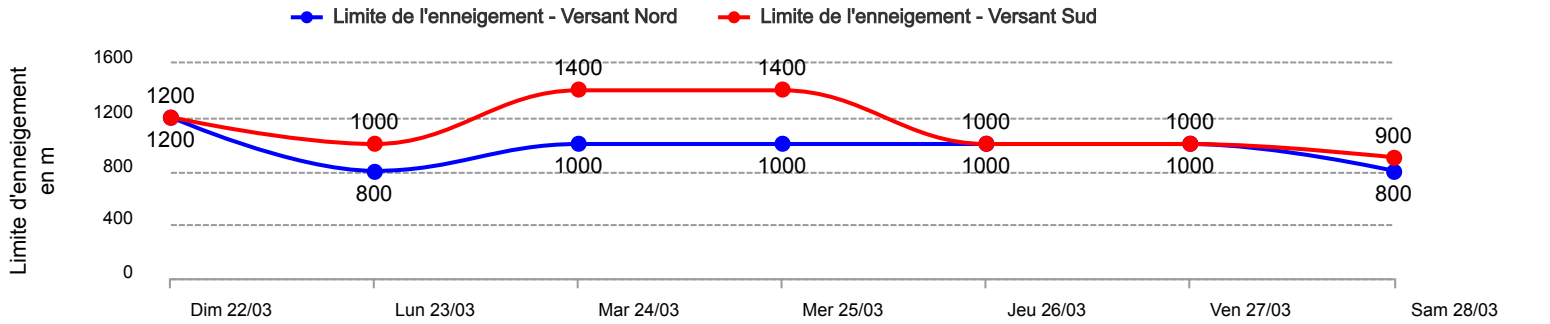

Pour consulter la vigilance en cours, veuillez vous rendre sur le site https://vigilance.meteofrance.fr/fr

Météo-France - 73 avenue de Paris, 94165 Saint-Mandé cedex - Contact : contact@meteo.fr

Bulletin neige & avalanches par téléphone au

0 892 68 10 20 Service 0,35 € / min + prix appel

Rédigé par Météo-France avec la contribution des observateurs du réseau nivo-météorologiques. Partenariat : ANMSM (Maires de Stations de Montagne), DSF (Domaines Skiables de France), ADSP (Directeurs de Pistes et de la Sécurité des Stations de Sports d'Hiver) et autres acteurs de la montagne.