Bulletin d'estimation du risque d'avalanche

(valable en dehors des pistes balisées et ouvertes)

MASSIF : Cerdagne Canigou

Rédigé le samedi 28 mars 2026 à 16h

Estimation des risques pour le : DIMANCHE 29 MARS

ENCORE DES STRUCTURES DE PLAQUES À VENT EN ALTITUDE

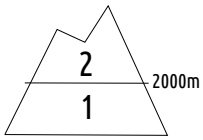

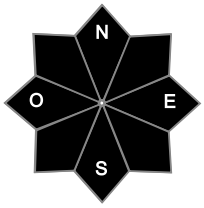

Au-dessus de 2000m indice de risque limité, plus bas indice faible.

Départs spontanés : Rares petits départs en neige récente dans des couloirs raides.

Déclenchements provoqués : Anciennes plaques en versants nord; formation de nouvelles fines plaques à vent au fil des chutes de neige ventées

Indices de risque : 5 très fort - 4 fort - 3 marqué - 2 limité - 1 faible -- En noir : les pentes les plus dangereuses

Stabilité du manteau neigeux

Situation avalancheuse typique : neige ventée couche fragile persistante

Déclenchements provoqués :
De nouvelles fines structures de plaques, parfois loin des crêtes, sont en formation dans les chutes de neige ventée de Nord commençant ce samedi soir. Leurs déclenchements devraient se limiter à des avalanches de petites tailles toutefois suffisantes pour déséquilibrer ou faire chuter un pratiquant.
De plus, des avalanches de plaques plus épaisses (petites à moyennes) sont encore possibles plutôt au-dessus de 2000/2200m dans un large secteur nord. En effet, quelques couches fragiles persistantes sont actuellement présentes, dès 2000/2200 m, mais plutôt au-delà de 2300/2400 m avec des avalanches déclenchables par un skieur. Elles sont souvent difficilement détectables, car masquées par les chutes de neige récente.
Observables : neige en surface travaillée par le vent, fissures devant les skis, "woomfs" éventuels.

Départs spontanés :
Des départs spontanés en neige sèche de petite taille (taille 1) sont possibles par surcharge par le vent dans les couloirs raides, pouvant éventuellement mobiliser en cascade les couches fragiles mentionnées plus haut.

Autre : Ambiance hivernale avec un très net refroidissement dès ce samedi soir accompagné d'un fort renforcement du vent.

Qualité de la neige

Enneigement :
L'enneigement est excellent et parmi les meilleurs de ces 20 dernières années. En altitude, les cumuls sont encore conséquents, mais les crêtes et sommets exposés au vent d'ouest à nord-ouest sont souvent complètement déneigés. Avec les nouvelles chutes de neige à partir de samedi soir, on pourra trouver dimanche une très fine couche de neige dès 1300/1500 m mais on chaussera toujours vers 1600/1700 m en Nord pour trouver une réelle sous-couche permettant de skier plus sereinement.

Qualité de la neige :
Dimanche matin, la montagne retrouve un aspect hivernal avec un saupoudrage jusqu'en bas du massif et quelques cm dès 1800m d'altitude. Vers les crêtes et sommets, les cumuls de neige sont très hétérogènes sous l'action du vent, avec des zones d'accumulations et des crêtes Ouest à Nord-Ouest pelées ou en neige dure voire glacée.

Aperçu météo pour le dimanche 29 mars

	nuit	matin	après-midi	soir

Quelques chutes de neige jusqu'en bas du massif avec du vent soutenu et des températures hivernales en montagne.

Pluie-Neige	600 m	600 m	800 m	
Iso 0 °C	1 100 m	1 000 m	1 200 m	1 400 m
Vent 2000 m	↘ 95 km/h	↓ 85 km/h	↓ 65 km/h	↘ 75 km/h
Vent 3000 m	↘ 120 km/h	↓ 110 km/h	↓ 90 km/h	↓ 90 km/h

Épaisseur de neige hors-piste

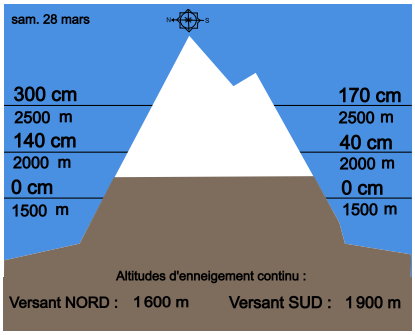

Précipitations à 1800 m

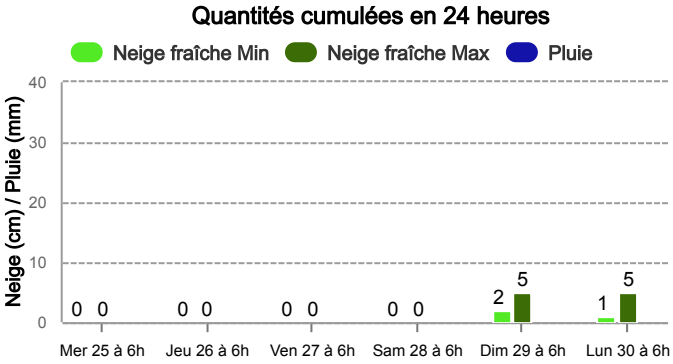

Tendance du lundi 30 mars

Indice de risque limité

Stationnaire sans apport significatif de neige supplémentaire mais avec toujours un vent soutenu.

Pour consulter la vigilance en cours, veuillez vous rendre sur le site https://vigilance.meteofrance.fr/fr

Météo-France - 73 avenue de Paris, 94165 Saint-Mandé cedex - Contact : contact@meteo.fr

Rédigé par Météo-France avec la contribution des observateurs du réseau nivo-météorologiques. Partenariat : ANMSM (Maires de Stations de Montagne), DSF (Domaines Skiables de France), ADSP (Directeurs de Pistes et de la Sécurité des Stations de Sports d'Hiver) et autres acteurs de la montagne.

Bulletin neige & avalanches par téléphone au
0 892 68 10 20 Service 0,35 € / min + prix appel

RÉPUBLIQUE FRANÇAISE
Liberté Égalité Fraternité

METEO FRANCE
À VOS CÔTÉS, DANS UN CLIMAT QUI CHANGE

Bulletin d'estimation du risque d'avalanche
(valable en dehors des pistes balisées et ouvertes)
MASSIF : Cerdagne Canigou

Rédigé le samedi 28 mars 2026 à 16h

Conditions nivo-météo des 7 derniers jours

	dim. 22/03				lun. 23/03				mar. 24/03				mer. 25/03				jeu. 26/03				ven. 27/03				sam. 28/03			
	03h	09h	15h	21h	03h	09h	15h	21h	03h	09h	15h	21h	03h	09h	15h	21h	03h	09h	15h	21h	03h	09h	15h	21h	03h	09h	15h	21h
Météo																												
Vent (km/h)	25	25	35	45	50	50	40	30	25	20	20	20	25	35	40	70	90	100	95	105	95	95	85	70	75	70	80	105
à 3000m																												
Vent (km/h)	15	15	25	35	35	35	30	20	15	10	10	10	15	20	30	45	75	80	80	85	75	75	65	55	60	50	60	80
à 2000m																												

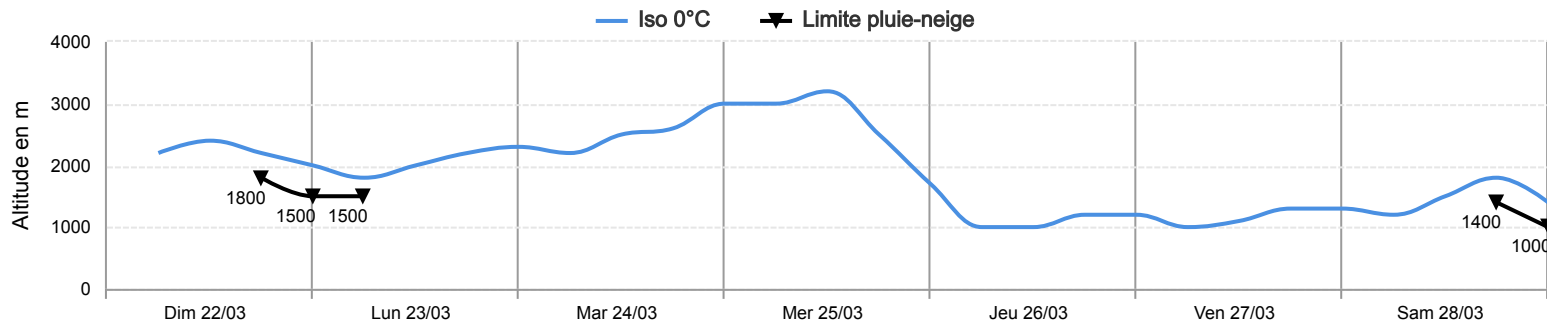

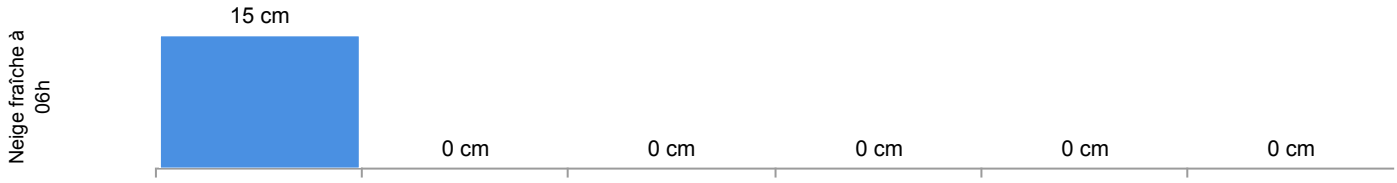

Risque d'avalanche	dim. 22/03	lun. 23/03	mar. 24/03	mer. 25/03	jeu. 26/03	ven. 27/03	sam. 28/03
	2	2	2	2	2	2	2

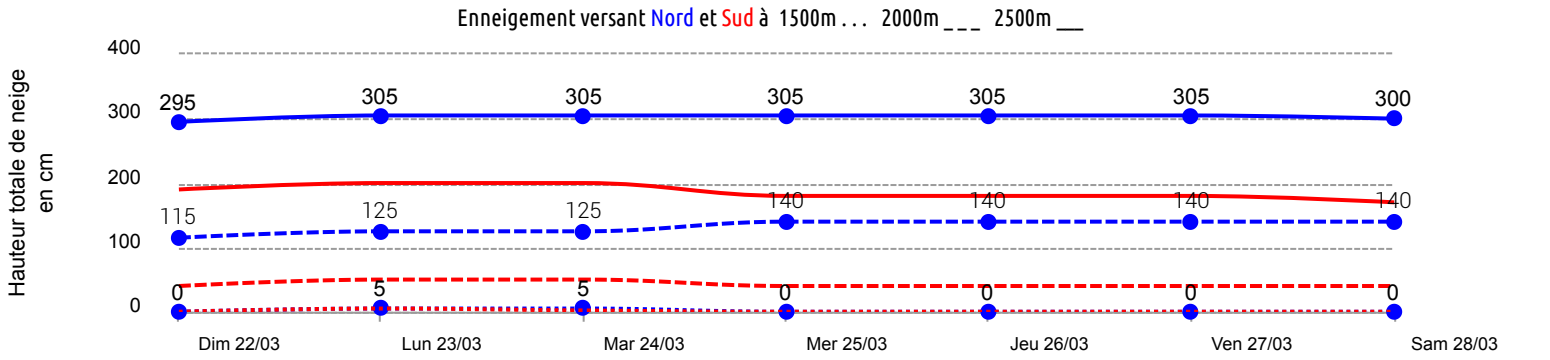

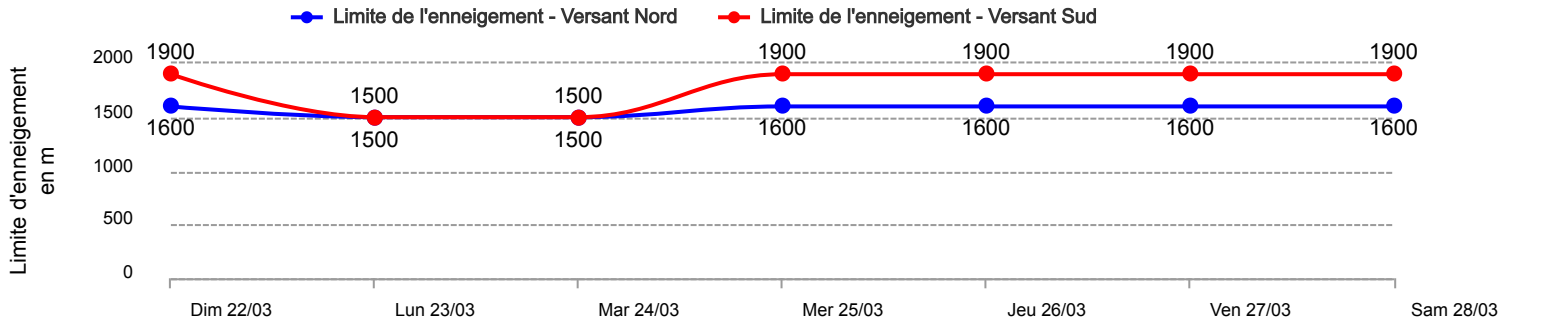

Pour consulter la vigilance en cours, veuillez vous rendre sur le site https://vigilance.meteofrance.fr/fr

Météo-France - 73 avenue de Paris, 94165 Saint-Mandé cedex - Contact : contact@meteo.fr

Rédigé par Météo-France avec la contribution des observateurs du réseau nivo-météorologiques. Partenariat : ANMSM (Maires de Stations de Montagne), DSF (Domaines Skiables de France), ADSP (Directeurs de Pistes et de la Sécurité des Stations de Sports d'Hiver) et autres acteurs de la montagne.

Bulletin neige & avalanches par téléphone au
0 892 68 10 20 Service 0,35 € / min + prix appel