Bulletin d'estimation du risque d'avalanche

(valable en dehors des pistes balisées et ouvertes)

MASSIF : Couserans

Rédigé le samedi 28 mars 2026 à 16h

Estimation des risques pour le : DIMANCHE 29 MARS

NOUVELLES INSTABILITÉS AVEC LES CHUTES DE NEIGE VENTÉES ET STRUCTURES DE PLAQUES PLUS ÉPAISSES EN ALTITUDE

3

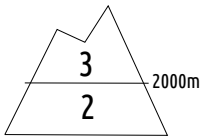

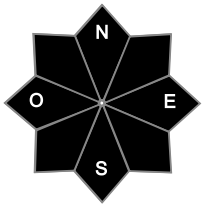

Au-dessus de 2000m indice de risque marqué, plus bas indice limité.

Départs spontanés : Quelques départs dans la neige récente dans les pentes raides principalement par surcharge due au transport de neige par le vent

Déclenchements provoqués : Avalanches de plaques facilement déclenchables dans les nouvelles chutes de neige ventée, parfois plus épaisses en cas de couche fragile enfouie

Indices de risque : 5 très fort - 4 fort - 3 marqué - 2 limité - 1 faible -- En noir : les pentes les plus dangereuses

Stabilité du manteau neigeux

Situation avalancheuse typique : neige fraîche couche fragile persistante

Déclenchements provoqués :

Avalanches de plaques facilement déclenchables au passage d'un skieur : de nouvelles structures de plaques, parfois loin des crêtes, sont en formation dans les chutes de neige ventée de Nord commençant samedi soir et qui se poursuivent en journée de dimanche. Les accumulations sont plutôt à attendre dans les versants d'un large Sud, mais pas seulement. De plus, au-dessus de 2000/2200m, des couches fragiles (grains anguleux, givre de surface voire neige roulée) peuvent être enfouies, et sont encore présentes, donnant des cassures plus épaisses et des avalanches de taille plus importante (taille 2 à rare 3). L'aspect des plaques sera plutôt dure en altitude et à proximités des crêtes et ruptures de pentes, parfois plus friables et plus difficilement identifiables à plus basse altitude et dans les endroits abrités du vent.

Observables : Quantité de neige fraiche (15/30 cm dès le matin à partir de 1800/2000 m et 10/15 cm supplémentaires en journée), neige travaillée par le vent en surface, fissures devant les skis, "woomfs".

Départs spontanés :

Des départs spontanés en neige sèche de taille petite à moyenne sont possibles dans les pentes raides. Le départ peut être par surcharge par le vent ou au gré des cumuls devenant plus importants en journée de dimanche. Ces avalanches pourront éventuellement mobiliser les couches fragiles mentionnées plus haut et donner alors de rares départs linéaires.

Autre : Ambiance hivernale avec un très net refroidissement dès ce samedi soir accompagné d'un fort renforcement du vent.

Qualité de la neige

Enneigement :

L'enneigement reste très bon pour la saison, après plusieurs hivers déficitaires. En altitude, les cumuls sont très conséquents, mais les crêtes et sommets exposés au vent d'ouest à nord-ouest sont souvent dégarnis.

Avec les nouvelles chutes de neige à basse altitude dès samedi après-midi, on pourra à nouveau chausser sur de la neige fraîche vers 1200/1300 m mais plutôt vers 1500/1600 m pour trouver une réelle sous-couche permettant de skier plus sereinement.

Qualité de la neige :

Dimanche matin, la montagne retrouve un aspect hivernal avec un saupoudrage dès 500/600m d'altitude, plusieurs cm de neige fraiche dès 1000m et déjà 10/20 cm à partir de 1500m. Vers le haut du massif, l'enneigement sera très hétérogène sous l'action du vent, avec des zones d'accumulations et des crêtes Ouest à Nord-Ouest pelées ou en neige dure voire glacée.

Aperçu météo pour le dimanche 29 mars

	nuit	matin	après-midi	soir

Neige jusqu'à basse altitude avec du vent fort en altitude et des températures hivernales.

Pluie-Neige	600 m	500 m	800 m	900 m
Iso 0 °C	1 100 m	800 m	1 100 m	1 300 m
Vent 2000 m	↓ 70 km/h	↓ 65 km/h	↓ 50 km/h	↓ 40 km/h
Vent 3000 m	↓ 100 km/h	↓ 110 km/h	↓ 90 km/h	↓ 70 km/h

Épaisseur de neige hors-piste

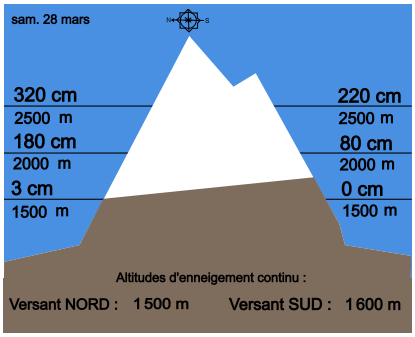

Précipitations à 1800 m

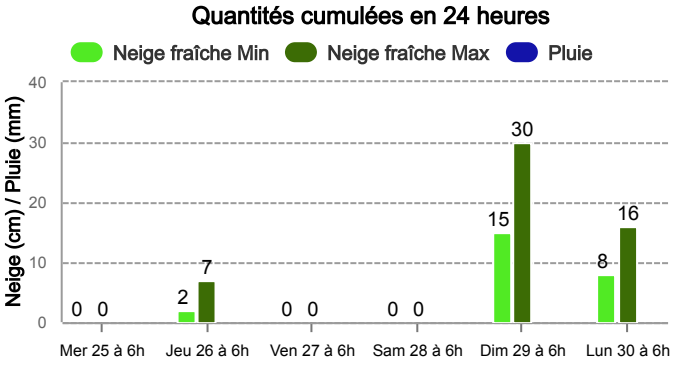

Tendance du lundi 30 mars

3

Indice de risque marqué

Stationnaire avec toujours du vent formant de nouvelles accumulations dans la neige récente.

Pour consulter la vigilance en cours, veuillez vous rendre sur le site https://vigilance.meteofrance.fr/fr

Météo-France - 73 avenue de Paris, 94165 Saint-Mandé cedex - Contact : contact@meteo.fr

Rédigé par Météo-France avec la contribution des observateurs du réseau nivo-météorologiques. Partenariat : ANMSM (Maires de Stations de Montagne), DSF (Domaines Skiables de France), ADSP (Directeurs de Pistes et de la Sécurité des Stations de Sports d'Hiver) et autres acteurs de la montagne.

Bulletin neige & avalanches par téléphone au

0 892 68 10 20 Service 0,35 € / min + prix appel

RÉPUBLIQUE FRANÇAISE
Liberté Égalité Fraternité

METEO FRANCE
À VOS CÔTÉS, DANS UN CLIMAT QUI CHANGE

Bulletin d'estimation du risque d'avalanche

(valable en dehors des pistes balisées et ouvertes)

MASSIF : Couserans

Rédigé le samedi 28 mars 2026 à 16h

Conditions nivo-météo des 7 derniers jours

	dim. 22/03				lun. 23/03				mar. 24/03				mer. 25/03				jeu. 26/03				ven. 27/03				sam. 28/03			
	03h	09h	15h	21h	03h	09h	15h	21h	03h	09h	15h	21h	03h	09h	15h	21h	03h	09h	15h	21h	03h	09h	15h	21h	03h	09h	15h	21h
Météo																												
Vent (km/h)	20	25	40	50	40	30	30	20	20	15	15	15	25	35	55	75	85	85	80	75	80	80	65	45	40	45	70	95
à 3000m	↓	↓	↓	↓	↓	↓	↓	↓	↓	↙	↓	↘	↓	↓	↓	↓	↓	↓	↓	↓	↓	↓	↓	↓	↓	↓	↓	↓
Vent (km/h)	10	15	30	35	30	20	20	10	10	10	10	10	10	20	40	55	55	50	50	45	50	50	40	20	20	20	30	60
à 2000m	↗	→	↘	↘	→	↙	↘	↓	↓	↙	↘	↑	↗	→	↘	↘	↓	↓	↓	↓	↓	↓	↓	↓	↓	↓	↓	↓

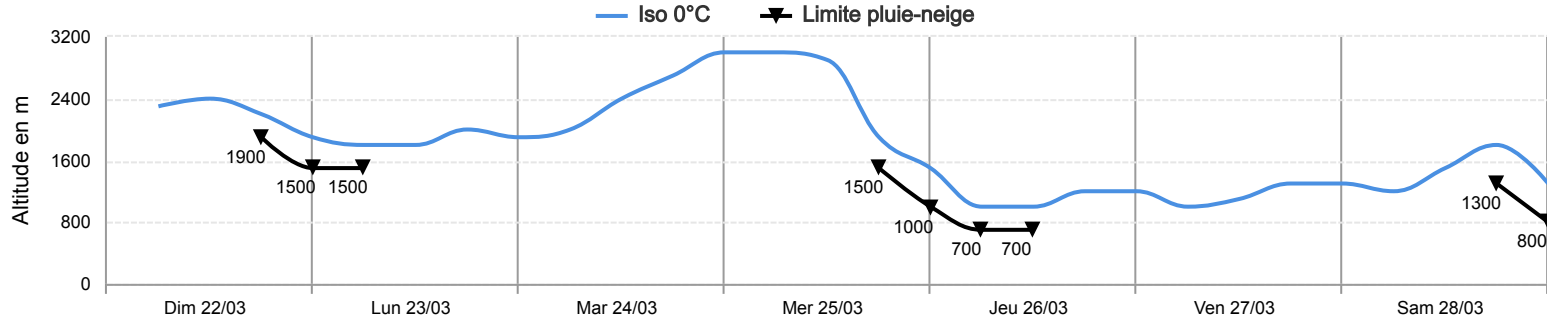

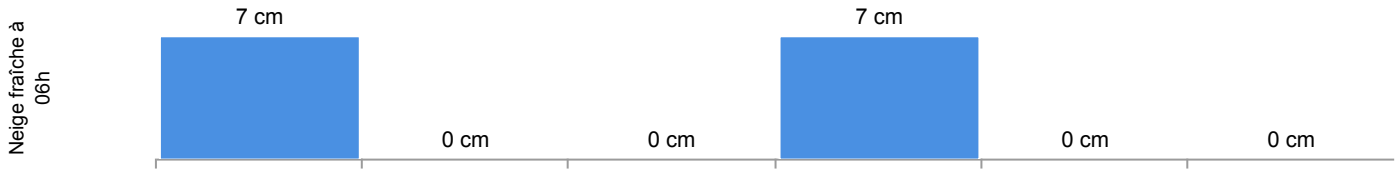

Risque d'avalanche	dim. 22/03	lun. 23/03	mar. 24/03	mer. 25/03	jeu. 26/03	ven. 27/03	sam. 28/03
	2	3	2	2	2	2	2

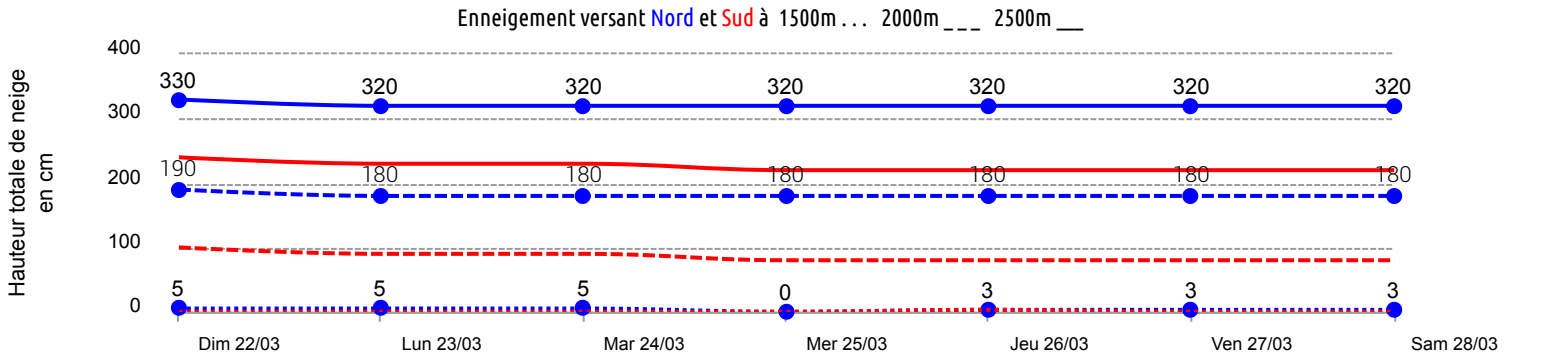

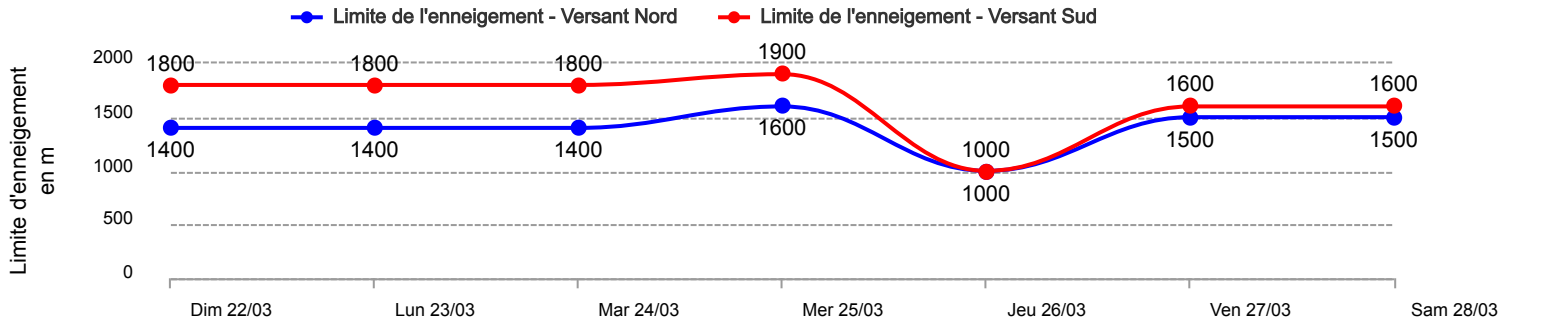

Pour consulter la vigilance en cours, veuillez vous rendre sur le site https://vigilance.meteofrance.fr/fr

Météo-France - 73 avenue de Paris, 94165 Saint-Mandé cedex - Contact : contact@meteo.fr

Rédigé par Météo-France avec la contribution des observateurs du réseau nivo-météorologiques. Partenariat : ANMSM (Maires de Stations de Montagne), DSF (Domaines Skiables de France), ADSP (Directeurs de Pistes et de la Sécurité des Stations de Sports d'Hiver) et autres acteurs de la montagne.

Bulletin neige & avalanches par téléphone au

0 892 68 10 20 Service 0,35 € / min + prix appel